# Bulletin d'estimation du risque d'avalanche
(valable en dehors des pistes balisées et ouvertes)

# MASSIF : Chartreuse

Rédigé le jeudi 9 avril 2026 à 17h

## Estimation des risques pour le : VENDREDI 10 AVRIL

**HUMIDIFICATION DU MANTEAU NEIGEUX EN TOUS VERSANTS**

2

2

N O E S

neige humide

Indice de risque limité.

**Départs spontanés :** Possibles avalanches en pentes raides/humidifiées, possibles en toutes orientations même en secteur Nord. Rare avalanche de glissement de taille 2 à 3 non exclue.

**Déclenchements provoqués :** En versants ensoleillés, possibles coulées ponctuelles sous les skis.

Indices de risque : 5 très fort - 4 fort - 3 marqué - 2 limité - 1 faible -- En noir : les pentes les plus dangereuses

## Stabilité du manteau neigeux

**Situation avalancheuse typique :** neige humide — avalanches de fond

**Départs spontanés :** - Après un regel nocturne plutôt médiocre, de nouvelles avalanches humides peuvent se produire ce jeudi dès la matinée, notamment dans les pentes réchauffées par le soleil, le plus souvent de taille 1 à 2. Dans un rare cas, une avalanche de glissement plus conséquente, au terrain, atteignant la taille 2 à 3, ne peut être exclue (alpage raide). Ces problématiques augmente au fil des heures au gré du parcours du soleil et du réchauffement des pentes. (Sud-est à Est le matin jusqu'à Ouest Sud-ouest en fin de journée).
- Une rupture spontanée de corniche est également possible l'après-midi et à surveiller dans les secteurs concernés.

**Déclenchements provoqués :** En pentes soutenues et bien humidifiées, le pratiquant pourrait faire couler la neige humide sous les skis.

**Autres :** A l'ombre (le matin surtout) neige souvent très dure ou croutée par le regel. Surfaces glissantes généralisées.

## Qualité de la neige

**Qualification de l'enneigement :** La fonte s'accélère, mais l'enneigement reste encore correct dès la moyenne altitude, et même très bon vers les hauteurs.

**Limites skiables :** Vers 1400/1600m en Nord, 1800/2200m au soleil...

**Qualité de la neige vendredi :** Neige printanière, regel nocturne très moyen, puis rapide humidification en journée, dans tous les versants. En Nord d'altitude toutefois, la neige peut encore être croutée/cassante le matin avec des restes de congères/effets du vent..

## Aperçu météo pour le vendredi 10 avril

| | nuit | matin | après-midi | soir |
|---|---|---|---|---|
| | | | | |

Journée légèrement plus nuageuse que les précédentes mais toujours très ensoleillée et douce.

| Pluie-Neige | | | | |
|---|---|---|---|---|
| Iso 0 °C | 3 100 m | 2 900 m | 3 000 m | 3 200 m |
| Vent 1500 m | ↓ 15 km/h | ↙ 10 km/h | ↓ 5 km/h | ↑ 5 km/h |
| Vent 2000 m | ↓ 25 km/h | ↓ 15 km/h | ↙ 10 km/h | → 15 km/h |

## Épaisseur de neige hors-piste

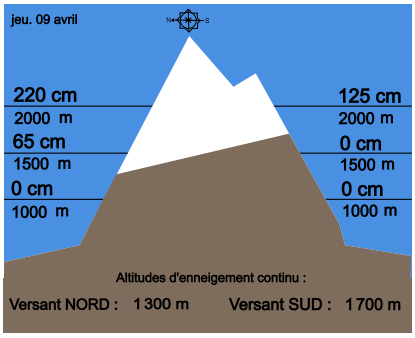


## Précipitations à 1800 m

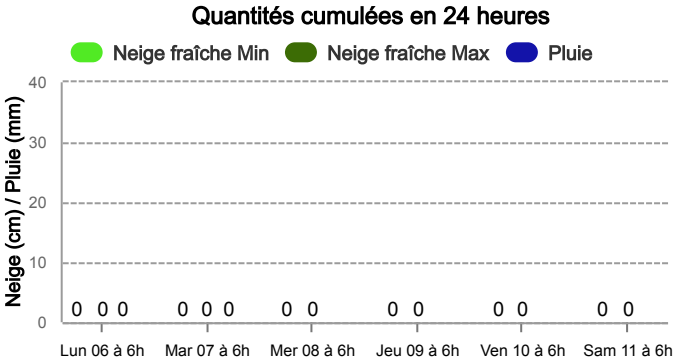


## Tendance du samedi 11 avril

2

**Indice de risque limité**

Humidification et tassement du manteau, peu d'évolutions.

Pour consulter la vigilance en cours, veuillez vous rendre sur le site https://vigilance.meteofrance.fr/fr


Météo-France - 73 avenue de Paris, 94165 Saint-Mandé cedex - Contact : contact@meteo.fr



Rédigé par Météo-France avec la contribution des observateurs du réseau nivo-météorologiques. Partenariat : ANMSM (Maires de Stations de Montagne), DSF (Domaines Skiables de France), ADSP (Directeurs de Pistes et de la Sécurité des Stations de Sports d'Hiver) et autres acteurs de la montagne.



Bulletin neige & avalanches par téléphone au 0 892 68 10 20 Service 0,35 € / min + prix appel

RÉPUBLIQUE FRANÇAISE
*Liberté Égalité Fraternité*

METEO FRANCE
À VOS CÔTÉS, DANS UN CLIMAT QUI CHANGE

# Bulletin d'estimation du risque d'avalanche

## (valable en dehors des pistes balisées et ouvertes)

# MASSIF : Chartreuse

Rédigé le jeudi 9 avril 2026 à 17h

## Conditions nivo-météo des 7 derniers jours

| | ven. 03/04 | | | | sam. 04/04 | | | | dim. 05/04 | | | | lun. 06/04 | | | | mar. 07/04 | | | | mer. 08/04 | | | | jeu. 09/04 | | | |
|---|---|---|---|---|---|---|---|---|---|---|---|---|---|---|---|---|---|---|---|---|---|---|---|---|---|---|---|---|
| | 03h | 09h | 15h | 21h | 03h | 09h | 15h | 21h | 03h | 09h | 15h | 21h | 03h | 09h | 15h | 21h | 03h | 09h | 15h | 21h | 03h | 09h | 15h | 21h | 03h | 09h | 15h | 21h |
| Météo | | | | | | | | | | | | | | | | | | | | | | | | | | | | |
| Vent (km/h) | 40 | 30 | 20 | 20 | 35 | 30 | 15 | 15 | 15 | 15 | 25 | 25 | 20 | 15 | 15 | 5 | 10 | 10 | 5 | 10 | 10 | 10 | 0 | 5 | 10 | 10 | 20 | 30 |
| à 2000m | | | | | | | | | | | | | | | | | | | | | | | | | | | | |
| Vent (km/h) | 30 | 15 | 15 | 10 | 15 | 15 | 10 | 10 | 15 | 15 | 20 | 20 | 10 | 10 | 10 | 0 | 0 | 10 | 5 | 5 | 5 | 5 | 5 | 5 | 5 | 5 | 15 | 20 |
| à 1500m | | | | | | | | | | | | | | | | | | | | | | | | | | | | |

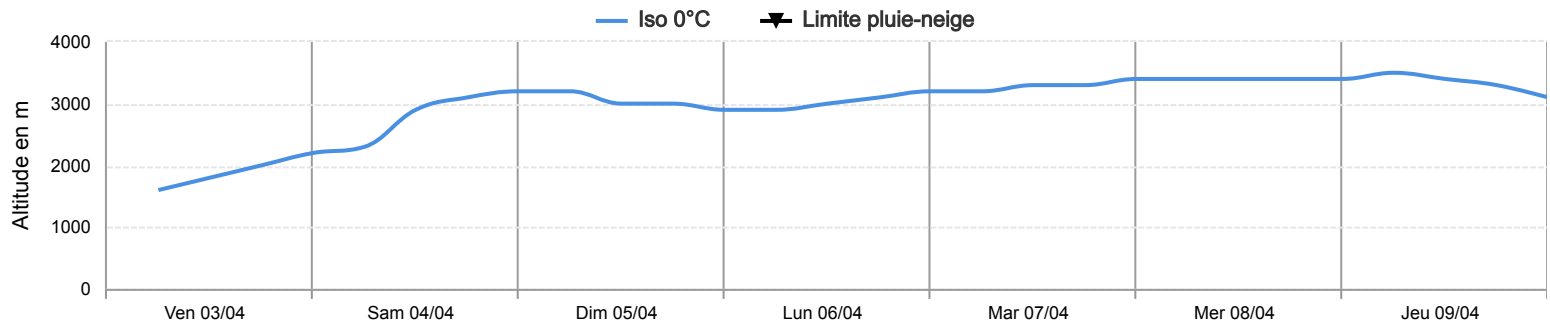


Neige fraîche à 06h

| 0 cm | 0 cm | 0 cm | 0 cm | 0 cm | 0 cm |
|---|---|---|---|---|---|

| Risque d'avalanche | ven. 03/04 | sam. 04/04 | dim. 05/04 | lun. 06/04 | mar. 07/04 | mer. 08/04 | jeu. 09/04 |
|---|---|---|---|---|---|---|---|
| | 2 | 2 | 2 | 2 | 2 | 2 | 2 |

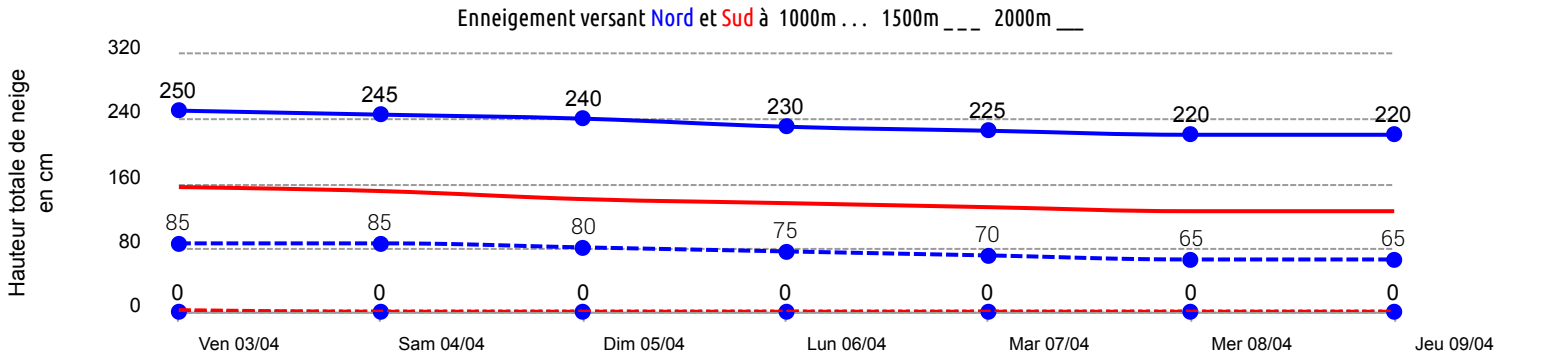


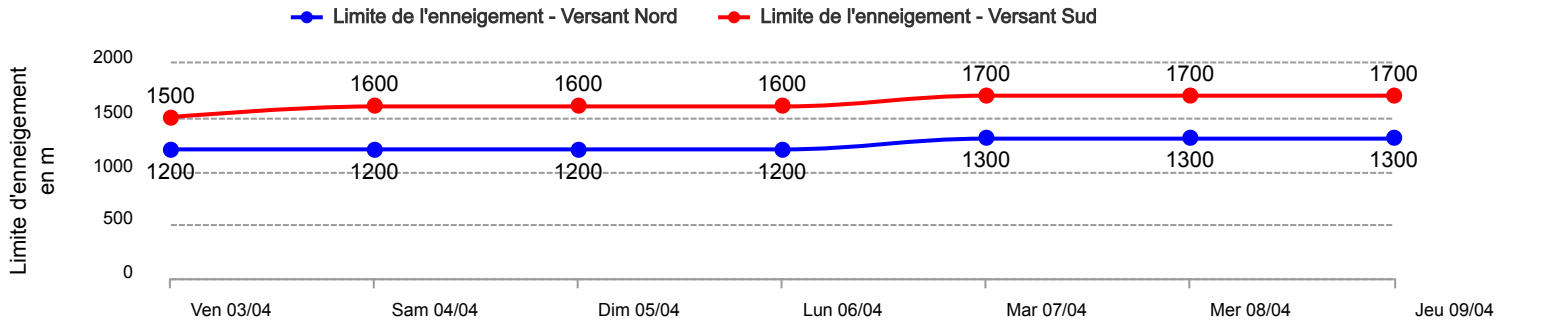


Pour consulter la vigilance en cours, veuillez vous rendre sur le site https://vigilance.meteofrance.fr/fr


Météo-France - 73 avenue de Paris, 94165 Saint-Mandé cedex - Contact : contact@meteo.fr


Bulletin neige & avalanches par téléphone au

0 892 68 10 20 Service 0,35 € / min + prix appel


Rédigé par Météo-France avec la contribution des observateurs du réseau nivo-météorologiques. Partenariat : ANMSM (Maires de Stations de Montagne), DSF (Domaines Skiables de France), ADSP (Directeurs de Pistes et de la Sécurité des Stations de Sports d'Hiver) et autres acteurs de la montagne.