Bulletin d'estimation du risque d'avalanche

(valable en dehors des pistes balisées et ouvertes)

MASSIF : Cinto Rotondo

Rédigé le jeudi 9 avril 2026 à 18h

Estimation des risques pour le : VENDREDI 10 AVRIL

L'HUMIDIFICATION DU MANTEAU NEIGEUX GAGNE EN ALTITUDE ET EN PROFONDEUR.

3

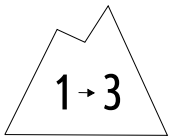

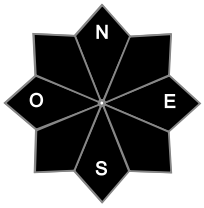

Indice de risque faible évoluant en marqué.

Départs spontanés : Coulées et avalanches de neige humide

Déclenchements provoqués : Peu probables

Indices de risque : 5 très fort - 4 fort - 3 marqué - 2 limité - 1 faible -- En noir : les pentes les plus dangereuses

Stabilité du manteau neigeux

Situation avalancheuse typique : neige humide

Départs spontanés : Des coulées et avalanches de neige humide sont attendues en journée, surtout dans les pentes raides bien ensoleillées, au fil de la course du soleil. En altitude, l'humidification gagnant en profondeur, des avalanches de taille moyenne et grande peuvent se produire, y compris dans les couloirs nord toujours bien chargés.
Déclenchements provoqués : Un skieur coupant une pente raide peut déclencher une coulée de neige humide, à plus forte raison aux heures les plus chaudes de la journée.
Autres : Présence de corniches, susceptibles de rompre à cause des conditions printanières. Persistance de surfaces dures et glacées.

Qualité de la neige

Qualification de l'enneigement : L'enneigement est excellent pour la saison. Au lac de Capitellu on relève près de 2 m de hauteur de neige totale. Sur la Maniccia, à 2400 m d'altitude dans le massif du Rotondo, on relève environ 3 m de hauteur de neige totale.
Limite d'enneigement skiable : vers 1600 m.
État de la neige : Évolution progressive vers une neige de printemps en toutes orientations. L'humidification gagne en profondeur tandis que le regel nocturne est moins efficace. Toutefois, les surfaces dures peuvent être fréquentes le matin en altitude. Dans les orientations Sud, le manteau neigeux est généralement humidifié sur toute son épaisseur, au moins jusqu'à 2200 m. En moyenne montagne, la croûte de regel est inexistante le matin, la neige devient molle voire pourrie l'après-midi.

Aperçu météo pour le vendredi 10 avril

Poursuite d'un temps sec et ensoleillé

	nuit	matin	après-midi	soir
Pluie-Neige				
Iso 0 °C	3 500 m	3 400 m	3 500 m	3 600 m
Vent 1500 m	→ 25 km/h	→ 25 km/h	→ 20 km/h	→ 15 km/h
Vent 3000 m	→ 35 km/h	↗ 30 km/h	→ 25 km/h	→ 20 km/h

Épaisseur de neige hors-piste

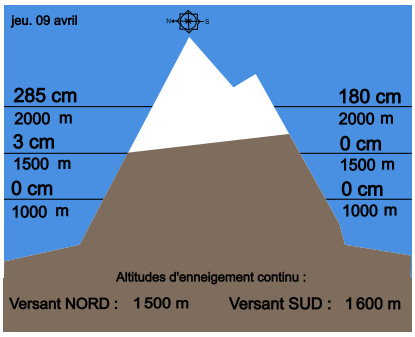

Précipitations à 1800 m

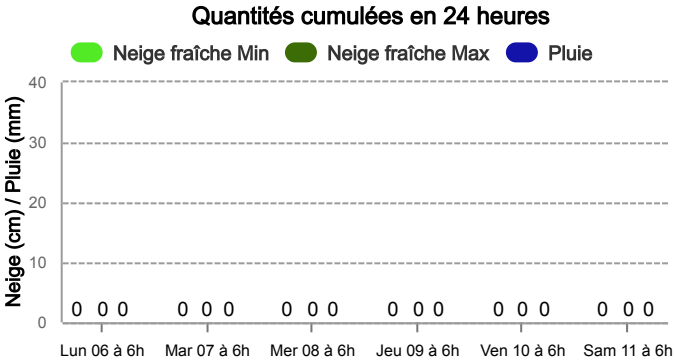

Tendance du samedi 11 avril

3

Indice de risque marqué

Le manteau neigeux continue de s'humidifier de plus en plus profondément. Risque d'avalanches de grande taille.

Pour consulter la vigilance en cours, veuillez vous rendre sur le site https://vigilance.meteofrance.fr/fr

Météo-France - 73 avenue de Paris, 94165 Saint-Mandé cedex - Contact : contact@meteo.fr

Rédigé par Météo-France avec la contribution des observateurs du réseau nivo-météorologiques. Partenariat : ANMSM (Maires de Stations de Montagne), DSF (Domaines Skiables de France), ADSP (Directeurs de Pistes et de la Sécurité des Stations de Sports d'Hiver) et autres acteurs de la montagne.

Bulletin neige & avalanches par téléphone au 0 892 68 10 20 Service 0,35 € / min + prix appel

RÉPUBLIQUE FRANÇAISE
Liberté Égalité Fraternité

METEO FRANCE
À VOS CÔTÉS, DANS UN CLIMAT QUI CHANGE

Bulletin d'estimation du risque d'avalanche

(valable en dehors des pistes balisées et ouvertes)

MASSIF : Cinto Rotondo

Rédigé le jeudi 9 avril 2026 à 18h

Conditions nivo-météo des 7 derniers jours

	ven. 03/04				sam. 04/04				dim. 05/04				lun. 06/04				mar. 07/04				mer. 08/04				jeu. 09/04			
	03h	09h	15h	21h	03h	09h	15h	21h	03h	09h	15h	21h	03h	09h	15h	21h	03h	09h	15h	21h	03h	09h	15h	21h	03h	09h	15h	21h
Météo																												
Vent (km/h)	60	50	40	25	40	40	30	40	25	15	10	15	25	20	20	20	25	20	20	15	15	10	20	15	15	15	35	30
à 3000m																												
Vent (km/h)	35	30	25	15	10	15	15	15	15	5	10	10	20	15	15	20	15	15	20	10	15	10	10	10	10	15	30	25
à 1500m																												

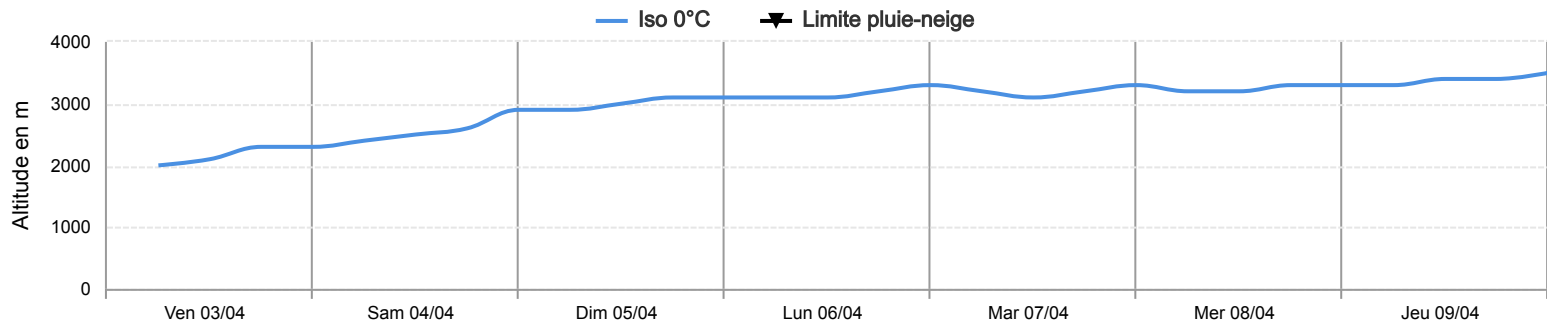

Neige fraîche à 06h

Ven 03/04	Sam 04/04	Dim 05/04	Lun 06/04	Mar 07/04	Mer 08/04	Jeu 09/04
0 cm	0 cm	0 cm	0 cm	0 cm	0 cm	

Risque d'avalanche	ven. 03/04	sam. 04/04	dim. 05/04	lun. 06/04	mar. 07/04	mer. 08/04	jeu. 09/04
	2	2	2	2	1	2	2

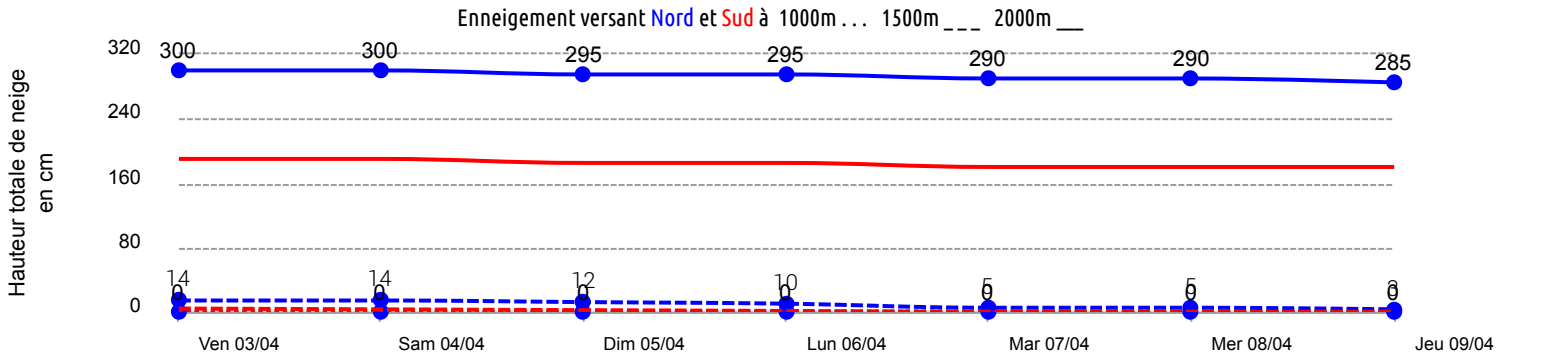

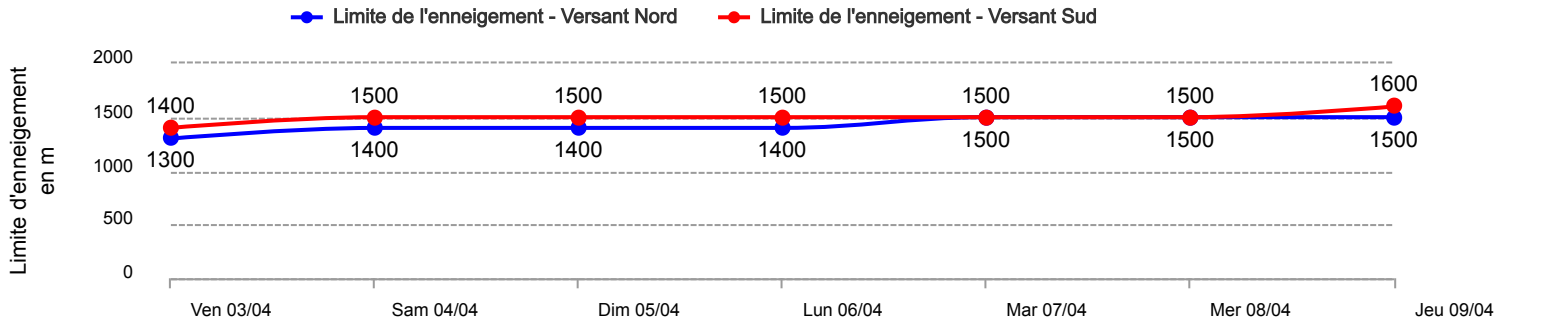

Pour consulter la vigilance en cours, veuillez vous rendre sur le site https://vigilance.meteofrance.fr/fr

Météo-France - 73 avenue de Paris, 94165 Saint-Mandé cedex - Contact : contact@meteo.fr

Bulletin neige & avalanches par téléphone au

0 892 68 10 20 Service 0,35 € / min + prix appel

Rédigé par Météo-France avec la contribution des observateurs du réseau nivo-météorologiques. Partenariat : ANMSM (Maires de Stations de Montagne), DSF (Domaines Skiables de France), ADSP (Directeurs de Pistes et de la Sécurité des Stations de Sports d'Hiver) et autres acteurs de la montagne.