aineva.it

Sonntag 12.04.2026

Veröffentlicht am 11.04.2026 um 17:00

Vormittag

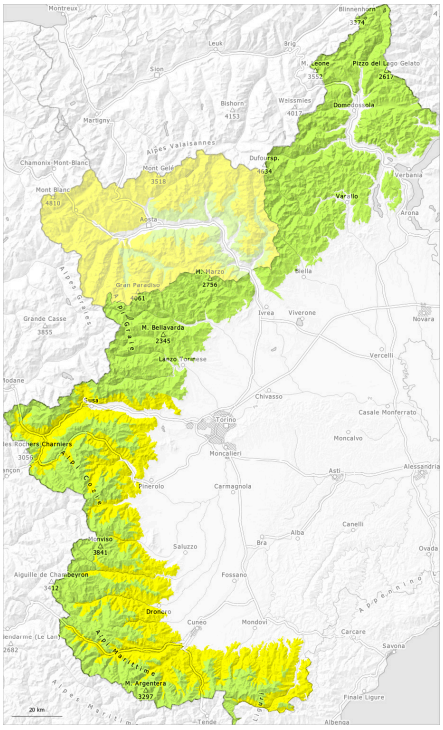

Nachmittag

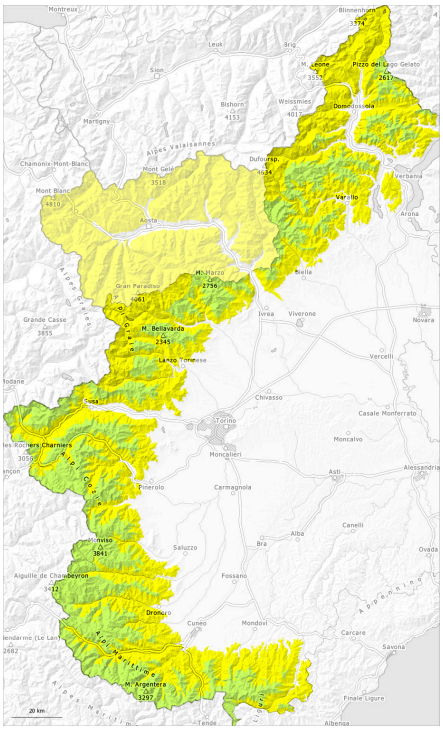

1	2	3	4	5
gering	mäßig	erheblich	groß	sehr groß

Gefahrenstufe 2 - Mäßig

AM:

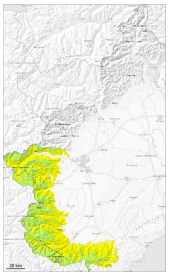

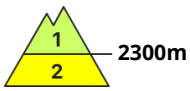

Tendenz: Lawinengefahr steigt
am Montag, den 13.04.2026

Nassschnee

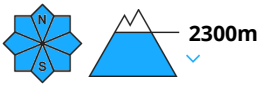

PM:

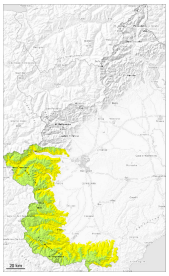

Tendenz: Lawinengefahr steigt
am Montag, den 13.04.2026

Nassschnee

Der Schneeregen führt ab dem Vormittag vor allem in tiefen und mittleren Lagen zu einer Anfeuchtung der Schneedecke. Feuchte Rutsche und Lawinen sind möglich.

Ab dem Vormittag fällt gebietsweise Regen bis auf 2300 m. Diese Situation führt in tiefen und mittleren Lagen zu einer deutlichen Anfeuchtung der Schneedecke.

Unterhalb von rund 2300 m und an sehr steilen Hängen sind mit dem Regen kleine bis mittlere nasse Rutsche und Lawinen möglich.
Dort wo die Schneefallgrenze höher liegt ist die Lawinengefahr höher.

Für Skitouren, Schneeschuhwanderungen sowie Variantenabfahrten sind die Verhältnisse ungünstig, sowohl aufgrund der starken Durchfeuchtung der Schneedecke in mittleren und tiefen Lagen als auch wegen lokal schlechter Sichtverhältnisse.

Schneedecke

Gefahrenmuster gm.10: frühjahrssituation

Unterhalb von rund 2300 m: Die Schneeoberfläche gefriert nur knapp und ist schon am Morgen aufgeweicht.
Der Regen führt am Nachmittag unterhalb von rund 2300 m zu einer zunehmenden Anfeuchtung der Schneedecke. Diese Situation führt zu einem Festigkeitsverlust innerhalb der Altschneedecke.

Tendenz

Am Montag fällt viel Schnee. Anstieg der Lawinengefahr mit dem Schneefall.

Gefahrenstufe 2 - Mäßig

AM:

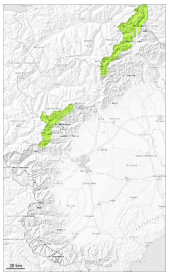

Tendenz: Lawinengefahr steigt
am Montag, den 13.04.2026

Nassschnee

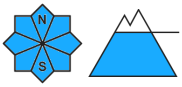

2300m

PM:

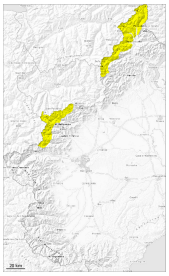

Tendenz: Lawinengefahr steigt
am Montag, den 13.04.2026

Triebschnee

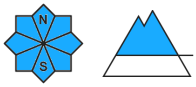

2200m

Nassschnee

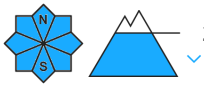

2200m

Neu- und Triebschnee in der Höhe. Feuchte Rutsche und Lawinen in tiefen Lagen.

Ab dem Nachmittag fallen oberhalb von rund 2200 m 5 bis 15 cm Schnee.
Diese Situation führt unterhalb von rund 2200 m zu einer Anfeuchtung der Schneedecke. In tiefen Lagen und an sehr steilen Hängen sind mit dem Regen meist kleine feuchte Rutsche und Lawinen möglich.

Zudem entstehen in mittleren und hohen Lagen am Nachmittag meist kleine Triebschneeansammlungen. Hohe Lagen: Die trockenen Lawinen können an sehr steilen Schattenhängen im grobkörnigen Altschnee ausgelöst werden und vereinzelt mittlere Größe erreichen. Dies vor allem mit großer Belastung.

Schneedecke

Gefahrenmuster gm.10: frühjahrssituation

Oberhalb von rund 2200 m: Die Schneeoberfläche gefriert tragfähig und weicht später auf als am Vortag. Der Regen führt am Nachmittag unterhalb von rund 2200 m zu einer zunehmenden Anfeuchtung der Schneedecke.

Hohe Lagen: Tief in der Altschneedecke sind v.a. an sehr steilen Nordost-, Nord- und Nordwesthängen grobkörnige Schwachschichten vorhanden.

Tendenz

> Der viele Neuschnee und die in mittleren und hohen Lagen entstehenden Triebschneeansammlungen werden zunehmend störanfällig.

Gefahrenstufe 2 - Mäßig

AM:

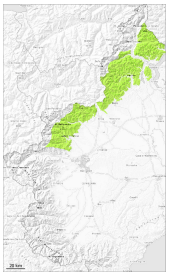

Tendenz: Lawinengefahr steigt
am Montag, den 13.04.2026

Nassschnee

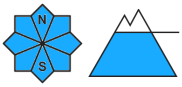

PM:

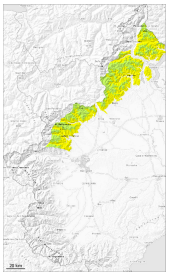

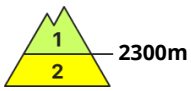

Tendenz: Lawinengefahr steigt
am Montag, den 13.04.2026

Nassschnee

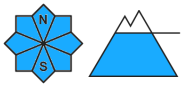

Der Regen führt am Nachmittag unterhalb von rund 2200 m zu einer Anfeuchtung der Schneedecke.

Am Nachmittag fällt gebietsweise Regen bis auf 2200 m. Diese Situation führt in tiefen und mittleren Lagen zu einer deutlichen Anfeuchtung der Schneedecke.
V.a. unterhalb von rund 2300 m und an sehr steilen Hängen sind mit der Durchnässung kleine bis mittlere feuchte Rutsche und Lawinen möglich.

Schneedecke

Gefahrenmuster gm.10: frühjahrssituation

Oberhalb von rund 2300 m: Die Schneeoberfläche gefriert tragfähig und weicht später auf als am Vortag. Der Regen führt am Nachmittag unterhalb von rund 2300 m zu einer zunehmenden Anfeuchtung der Schneedecke. Diese Situation führt zu einem Festigkeitsverlust innerhalb der Altschneedecke.

Tendenz

Am Montag fällt viel Schnee. Anstieg der Lawinengefahr mit dem Schneefall.