GOBIERNO DE ESPAÑA
VICEPRESIDENCIA TERCERA DEL GOBIERNO
MINISTERIO PARA LA TRANSICIÓN ECOLÓGICA Y EL RETO DEMOGRÁFICO

Boletín de información nivológica y de peligro de aludes

Pirineo Catalán

aemet Agencia Estatal de Meteorología

domingo, 12 de abril de 2026

Pronóstico hasta las 24 horas del lunes, día 13 de abril

(Válido fuera de pistas de esquí balizadas y abiertas)

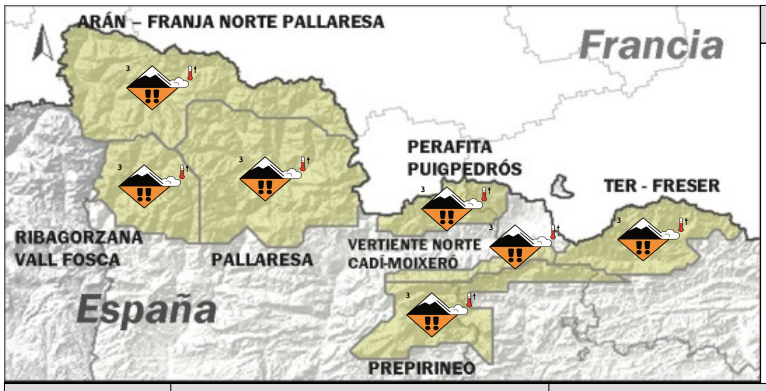

Problemas de aludes

- Placas de viento
- Deslizamientos basales
- Nieve reciente

Macizo	Peligro	Problemas de aludes, cota, orientación, tamaño	Innivación observada (m)
Arán - Franja norte Pallaresa	3 Notable	**Placas de viento** 2100 N O E S 2 **Nieve reciente** 1800 N O E S 2	2026-04-12 N S Cotas medias
Ribagorzana - Vall Fosca	3 Notable	**Placas de viento** 2100 N O E S 2 **Nieve reciente** 1800 N O E S 2	2026-04-12 N S Cotas medias
Pallaresa	3 Notable	**Placas de viento** 2100 N O E S 2 **Nieve reciente** 1800 N O E S 2	2026-04-12 N S Cotas medias

AEMET. Se autoriza la reproducción de su contenido citando la fuente.

Boletín de información nivológica y de peligro de aludes

Pirineo Catalán

Perafita - Puigpedrós	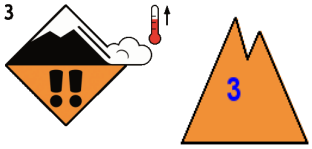 **Notable**	**Placas de viento** 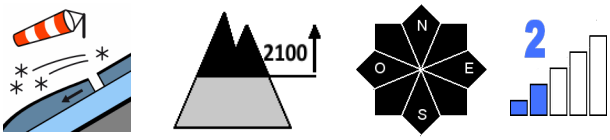 **Deslizamientos basales** 	2026-04-12
Ter - Freser	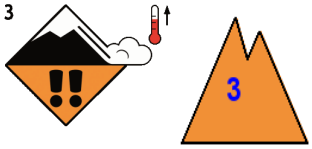 **Notable**	**Placas de viento** 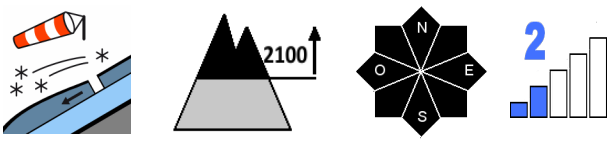 **Deslizamientos basales** 	2026-04-12
Vertiente norte Cadí - Moixeró	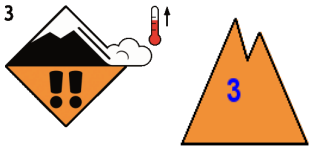 **Notable**	**Placas de viento** 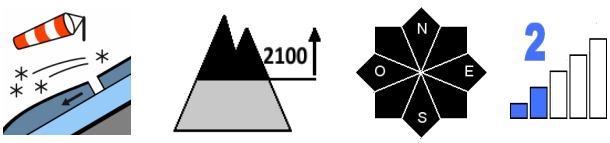 **Deslizamientos basales** 	2026-04-12
Prepirineo	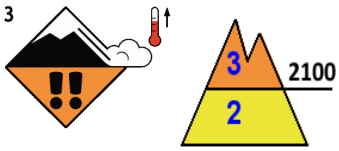 **Notable**	**Placas de viento** 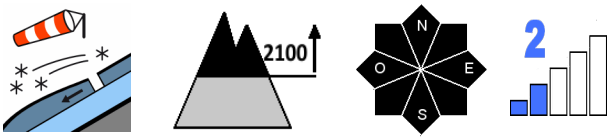 **Deslizamientos basales** 	2026-04-12

Estado del manto y observaciones recientes

Desde ayer por la tarde se han registrado precipitaciones en el entorno del Valle de Arán, que han continuado durante la jornada de hoy, extendiéndose de manera progresiva al resto de macizos, de oeste a este. Se espera que estas continúen a lo largo de la jornada de mañana aunque de manera más ocasional. La cota de nieve, que ayer por la tarde se situaba en torno a unos 2500 metros, ha ido descendiendo de manera progresiva, situándose en el entorno de las medianías durante el día de hoy. Se espera que esta continúe descendiendo, de manera más acusada en los macizos occidentales.

AEMET. Se autoriza la reproducción de su contenido citando la fuente.

Con todo esto, en la alta montaña se han podido alcanzar acumulaciones de unos 5-10 cm de nieve reciente, que se han depositado sobre un manto muy húmedo y de perfil primaveral, causado por el ambiente cálido de días previos. Por otro lado, en medianías, donde da comienzo el manto continuo, las lluvias han continuado compactándolo y aportándole más humedad. A pesar de ello, los espesores siguen estando por encima de lo que sería habitual a estas alturas de la temporada. A unos 2200 a 2400 metros se alcanzan los 120 a 220 cm en el Arán y Franja Norte Pallaresa y los 50-160 cm en el resto, aún más en ventisqueros y otras zonas propensas al depósito.

Cabe mencionar que las nuevas nevadas han ido acompañadas de vientos intensos de componente sur, que han podido formar placas de viento en cotas altas de todas las orientaciones, aunque con preferencia en las caras norte, donde, asimismo, pueden persistir estratos débiles a diferentes profundidades.

Evolución del manto y peligro de aludes para el lunes, día 13

Problemas de nieve reciente y placas de viento en cotas altas. Problema de nieve húmeda y situación de nieve reciente en medianías. Problema de deslizamientos basales en todas las cotas.

En cotas altas:
Desde hoy serán probables los aludes espontáneos de nieve reciente en cotas altas, pequeños (de tamaño 1, capaz de desestabilizar a una persona) o medianos (de tamaño 2, capaz de enterrar a una persona), preferentemente en los macizos occidentales donde las acumulaciones serán mayores.
En estas altitudes, los vientos continuarán soplando de manera intensa y venteando la nieve. El giro del viento a componente norte, llevará a que mañana podamos encontrar placas de viento en todas las orientaciones. Estas podrán activarse ante sobrecargas débiles como puede ser el paso de un solo esquiador, dando lugar a aludes generalmente medianos, sin descartar alguno localmente grande (de tamaño 3, capaz de enterrar a un grupo de personas) en caso de arrastrar nieve húmeda de niveles inferiores.

En medianías:
A pesar del descenso de las temperaturas, mañana todavía serán posibles los aludes de nieve húmeda, de tamaño pequeño o mediano. En los canales y otras zonas propensas a la acumulación serán posibles las coladas o aludes pequeños de nieve reciente, localmente medianos en el Arán y Franja Norte de la Pallaresa.

En todas las cotas:
El manto está muy húmedo en profundidad, sobre todo en medianías. Es por esto que en aquellas zonas de manto delgado sobre laderas herbosas o de roca lisa muy inclinadas serán posibles los deslizamientos basales, que podrían alcanzar el tamaño grande, preferentemente en cotas medias.

Predicción meteorológica para el lunes, día 13

Muy nuboso o cubierto, disminuyendo la nubosidad por la tarde. Visibilidad localmente reducida. Se esperan precipitaciones débiles o localmente moderadas, más generalizadas al inicio, tendiendo a quedar restringidas al Arán y la Franja Norte Pallaresa a lo largo de la

AEMET. Se autoriza la reproducción de su contenido citando la fuente.

mañana. Cota de nieve en torno a 900-1200 metros, algo más alta de madrugada en el Ripollès y Prepirineo. Temperaturas generalmente en ligero o moderado descenso. Heladas débiles, moderadas en cotas altas. De componente norte, generalmente moderado con intervalos de fuerte, aunque en zonas reguardadas de medianías y cotas bajas podrá soplar flojo. En cotas altas y zonas expuestas no se descarta alguna racha muy fuerte.

Datos en la atmósfera libre:

Altitud de la isoterma de 0 ºC: 1700 m
Altitud de la isoterma de -10 ºC: 3700 m

Viento a 1500 m: N 20 km/h
Viento a 3000 m: NW 30 km/h

Evolución para el martes día 14

Nivel de peligro sin cambios o en ligero descenso.

Escala europea de peligro de aludes

Débil | Limitado | Notable | Fuerte | Muy Fuerte

Problemas de aludes

Nieve reciente | Placas de viento | Capas débiles persistentes | Nieve húmeda | Deslizamientos basales | Sin problema evidente

Nota1: Se recuerda que, siempre que haya nieve, la ausencia total de peligro no existe. Hay que tener presente que en circunstancias desfavorables, con aludes de tamaño 1 (alud pequeño o colada) y tamaño 2 (alud mediano), se pueden sufrir severos daños personales.

Nota2: Los BPA se elaboran en base a información meteorológica así como al estado del manto nivoso a través de sondeos puntuales. Se advierte a los usuarios de la variabilidad de esta información al extrapolarla a zonas extensas de montaña. Por ello, AEMET no se hace responsable de su uso para la toma de decisiones que conciernen a la seguridad personal, ni de los riesgos físicos o materiales de ellas derivadas.

AEMET. Se autoriza la reproducción de su contenido citando la fuente.