GOBIERNO DE ESPAÑA
VICEPRESIDENCIA TERCERA DEL GOBIERNO
MINISTERIO PARA LA TRANSICIÓN ECOLÓGICA Y EL RETO DEMOGRÁFICO

Boletín de información nivológica y de peligro de aludes

Pirineo Navarro y Aragonés

aemet Agencia Estatal de Meteorología

domingo, 12 de abril de 2026

Pronóstico hasta las 24 horas del lunes, día 13 de abril

(Válido fuera de pistas de esquí balizadas y abiertas)

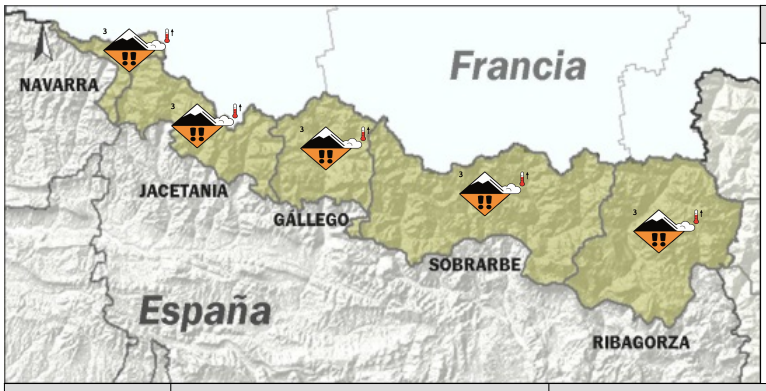

Problemas de aludes

Placas de viento

Nieve reciente

Macizo	Peligro	Problemas de aludes, cota, orientación, tamaño	Innivación observada (m)
Navarra	3 Notable	**Placas de viento**: 2100, N O E S, 2 **Nieve reciente**: 1800, N O E S, 2	2026-04-12 N S Cotas medias
Jacetania	3 Notable	**Placas de viento**: 2100, N O E S, 2 **Nieve reciente**: 1800, N O E S, 2	2026-04-12 N S Cotas medias
Gállego	3 Notable	**Placas de viento**: 2100, N O E S, 2 **Nieve reciente**: 1800, N O E S, 2	2026-04-12 N S Cotas medias

Boletín de información nivológica y de peligro de aludes

Pirineo Navarro y Aragonés

Sobrarbe	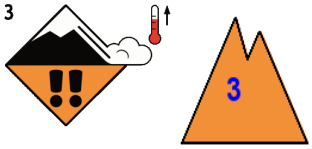 **Notable**	**Placas de viento** 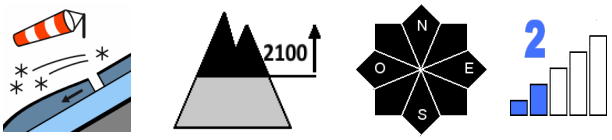 **Nieve reciente** 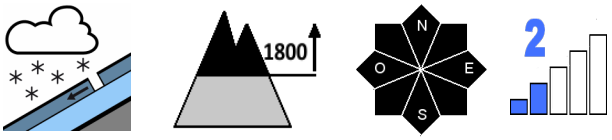	2026-04-12
Ribagorza	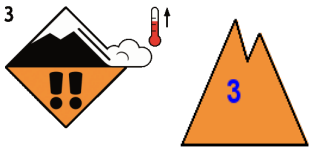 **Notable**	**Placas de viento** 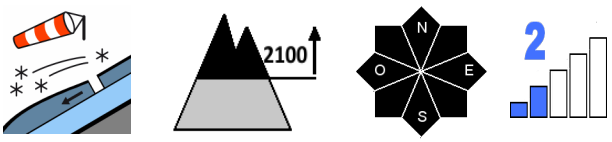 **Nieve reciente** 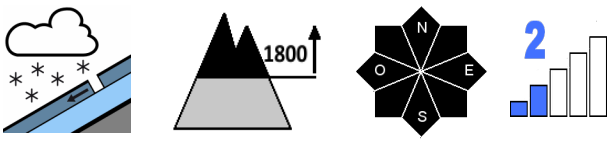	2026-04-12

Estado del manto y observaciones recientes

Desde ayer por la tarde se han registrado precipitaciones que han sido en algunos casos persistentes, superando localmente los 30 l/m2 en los macizos occidentales y alcanzando los 15 l/m2 en el resto. Se espera que estas continúen a lo largo de la tarde de hoy y que vayan remitiendo en las últimas horas, de oeste a este, para continuar durante la jornada de mañana aunque de manera menos copiosa. La cota de nieve, que ayer por la tarde se situaba en torno a unos 2500 metros, ha ido descendiendo de manera progresiva, esperándose que se puedan alcanzar los 800-1000 metros al final del día de hoy.

Con todo esto, en la alta montaña se han podido alcanzar acumulaciones importantes de nieve reciente, de unos 10-25 cm, que localmente han podido ser superiores. Estos nuevos centímetros se han depositado sobre un manto muy húmedo y de perfil primaveral, causado por el ambiente cálido de días previos. Por otro lado, en medianías, donde da comienzo el manto continuo, las lluvias han continuado compactándolo y aportándole más humedad. A pesar de ello, los espesores siguen estando por encima de lo que sería habitual a estas alturas de la temporada, superándose holgadamente los 100 cm en numerosas zonas por encima de 2000 a 2200 metros, más en ventisqueros y otras zonas propensas a la acumulación.

Cabe mencionar que las nuevas nevadas han ido acompañadas de vientos intensos de componente sur, que han podido formar placas de viento en cotas altas de todas las orientaciones, aunque con preferencia en las caras norte, donde, asimismo, pueden persistir estratos débiles a diferentes profundidades.

Se ha observado algún alud mediano de nieve húmeda en orientaciones norte.

AEMET. Se autoriza la reproducción de su contenido citando la fuente.

Evolución del manto y peligro de aludes para el lunes, día 13

Problemas de nieve reciente y placas de viento en cotas altas. Problema de nieve húmeda y situación de nieve reciente en medianías. Problema de deslizamientos basales en todas las cotas.

En cotas altas:
Desde hoy serán probables los aludes espontáneos de nieve reciente en cotas altas, pequeños (de tamaño 1, capaz de desestabilizar a una persona) o medianos (de tamaño 2, capaz de enterrar a una persona).
En estas altitudes, los vientos continuarán soplando de manera intensa y venteando la nieve. El giro del viento a componente norte, llevará a que mañana podamos encontrar placas de viento en todas las orientaciones. Estas podrán activarse ante sobrecargas débiles como puede ser el paso de un solo esquiador, dando lugar a aludes generalmente medianos, sin descartar alguno localmente grande (de tamaño 3, capaz de enterrar a un grupo de personas) en caso de arrastrar nieve húmeda de niveles inferiores.

En medianías:
A pesar del descenso de las temperaturas, mañana todavía serán posibles los aludes de nieve húmeda, de tamaño pequeño o mediano. En los canales y otras zonas propensas a la acumulación serán posibles las coladas o aludes pequeños de nieve reciente, que en caso de arrastrar nieve húmeda de niveles inferiores podrían alcanzar dimensiones mayores.

En todas las cotas:
El manto está muy húmedo en profundidad, sobre todo en medianías. Es por esto que en aquellas zonas de manto delgado sobre laderas herbosas o de roca lisa muy inclinadas serán posibles los deslizamientos basales, que podrían alcanzar el tamaño grande, preferentemente en cotas medias.

Predicción meteorológica para el lunes, día 13

Pirineo navarro:
Predominio de cielos nubosos o muy nubosos, con predominio de nubes bajas y de evolución diurna. Visibilidad localmente reducida. Se esperan precipitaciones débiles o localmente moderadas a lo largo del día, que en algún caso podrán ser en forma de chubascos. Cota de nieve en torno a unos 1000-1200 metros. Temperaturas mínimas sin cambios o en ligero descenso. Máximas en ligero o moderado ascenso. Heladas débiles, localmente moderadas en cotas altas. Soplarán vientos moderados o fuertes de componente norte.

Pirineo aragonés:
Predominio de cielos nubosos o muy nubosos, con predominio de nubes bajas y de evolución diurna. Visibilidad localmente reducida. Se esperan precipitaciones débiles o localmente moderadas en la divisoria con Francia, de manera más ocasional en el resto. Cota de nieve en torno a 900-1200 metros. Temperaturas en ligero o moderado descenso. Heladas débiles, moderadas en cotas altas y localmente fuertes en cumbres. Soplarán vientos moderados o fuertes de componente norte, con probables rachas muy fuertes en cotas altas y zonas expuestas. En zonas resguardadas de medianías y cotas bajas podrá soplar flojo.

AEMET. Se autoriza la reproducción de su contenido citando la fuente.

Datos en la atmósfera libre:

Altitud de la isoterma de 0 ºC: 1700 m
Altitud de la isoterma de -10 ºC: 3600 m

Viento a 1500 m: NE 25 km/h
Viento a 3000 m: N 40 km/h

Evolución para el martes día 14

Nivel de peligro sin cambios o en ligero descenso.

(Información elaborada a partir de los datos recibidos de los refugios de Linza, Lizara, Respomuso, Panticosa, Bachimaña, Góriz, Pineta, Estós, Angel Orús, La Renclusa y Belagua y de la estación de esquí de fondo de Llanos del Hospital)

Escala europea de peligro de aludes

Débil Limitado Notable Fuerte Muy Fuerte

Problemas de aludes

Nieve reciente Placas de viento Capas débiles persistentes Nieve húmeda Deslizamientos basales Sin problema evidente

Nota1: Se recuerda que, siempre que haya nieve, la ausencia total de peligro no existe. Hay que tener presente que en circunstancias desfavorables, con aludes de tamaño 1 (alud pequeño o colada) y tamaño 2 (alud mediano), se pueden sufrir severos daños personales.

Nota2: Los BPA se elaboran en base a información meteorológica así como al estado del manto nivoso a través de sondeos puntuales. Se advierte a los usuarios de la variabilidad de esta información al extrapolarla a zonas extensas de montaña. Por ello, AEMET no se hace responsable de su uso para la toma de decisiones que conciernen a la seguridad personal, ni de los riesgos físicos o materiales de ellas derivadas.

AEMET. Se autoriza la reproducción de su contenido citando la fuente.