Lunedì 13.04.2026

Pubblicato il 12.04.2026 alle ore 17:00

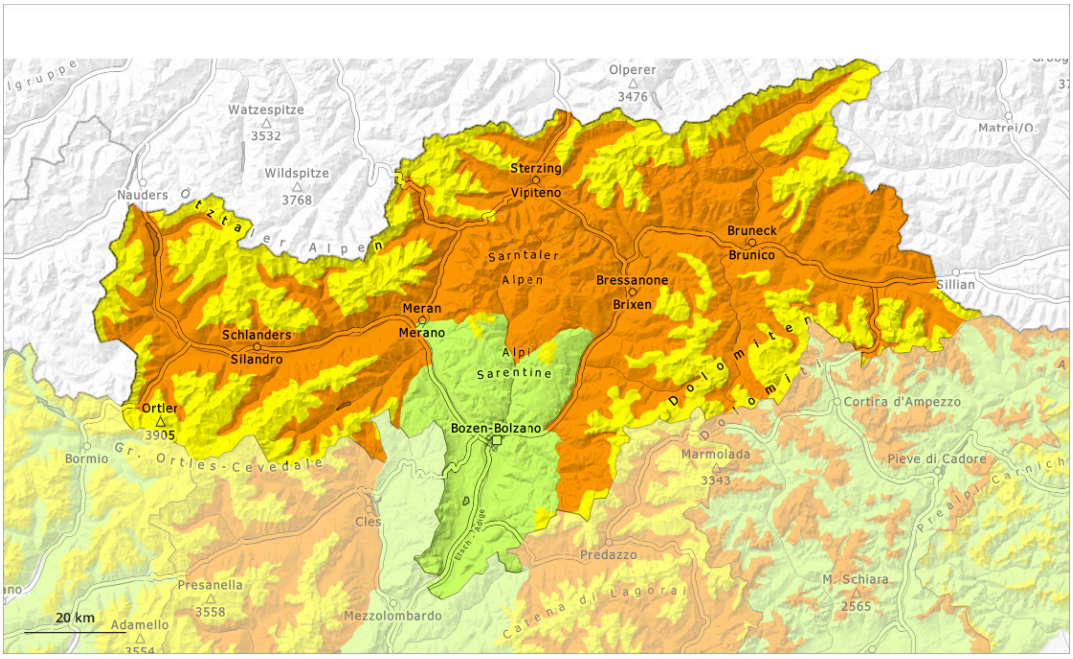

1	2	3	4	5
debole	moderato	marcato	forte	molto forte

Grado di pericolo 3 - Marcato

2800m

Tendenza: pericolo valanghe stabile
per Martedì il 14.04.2026

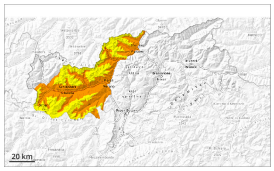

Neve bagnata

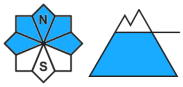

2800m

Lastrone da vento

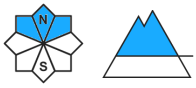

2800m

Strati deboli persistenti

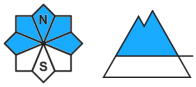

2500m

La neve bagnata è la principale fonte di pericolo. Neve ventata in alta montagna.

Con la pioggia, la probabilità di distacco di valanghe di neve bagnata aumenterà soprattutto al di sotto dei 2500 m circa, soprattutto sui pendii ripidi esposti a ovest, nord ed est. In queste aree, sono previste valanghe spontanee, anche di grandi dimensioni. Inoltre, in alcuni punti le valanghe umide e bagnate possono subire un distacco già in seguito al passaggio di un singolo appassionato di sport invernali, anche sui pendii ripidi esposti a ovest, nord ed est al di sotto dei 2800 m circa.

Isolati punti pericolosi per valanghe asciutte si trovano sui pendii ombreggiati molto ripidi al di sopra dei 2500 m circa. Tali punti pericolosi sono difficili da individuare. Sfavorevoli sono principalmente i punti di passaggio da poca a molta neve, (--). Inoltre in alta montagna gli accumuli di neve ventata di più recente formazione possono in parte subire un distacco, principalmente sui pendii ombreggiati vicino alle creste.

Manto nevoso

Situazione tipo st.3: pioggia su neve | st.6: neve a debole coesione e vento

La superficie del manto nevoso non riuscirà a rigelarsi durante la notte coperta e risulterà ammorbidita già al mattino. Cadrà pioggia sino al di sopra dei 2500 m. La pioggia causerà principalmente sui pendii ombreggiati ripidi una destabilizzazione all'interno del manto nevoso.

Cadranno da 10 a 20 cm di neve al di sopra dei 2500 m circa, localmente anche di più. Con vento forte in alta montagna si formeranno accumuli di neve ventata in parte facilmente distaccabili.

Sui pendii ripidi esposti a ovest, nord ed est al di sopra dei 2500 m circa: Nella parte superiore del manto di

neve vecchia si trovano, a livello isolato, strati fragili instabili. Nella parte basale del manto di neve vecchia si trovano strati fragili a cristalli sfaccettati.

Tendenza

Con l'abbassamento del limite delle nevicate, leggero calo del pericolo di valanghe di neve bagnata. In alcune aree, cadrà neve al di sopra dei 2000 m circa.

Grado di pericolo 3 - Marcato

2800m

Tendenza: pericolo valanghe stabile
per Martedì il 14.04.2026

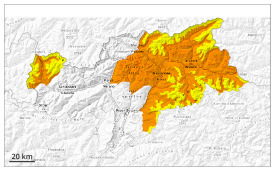

Neve bagnata

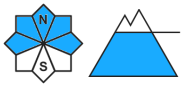

2800m

Strati deboli persistenti

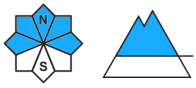

2500m

La neve bagnata è la principale fonte di pericolo. Con la pioggia, sono previste valanghe spontanee di neve bagnata.

Con la pioggia, la probabilità di distacco di valanghe di neve bagnata aumenterà soprattutto sui pendii ombreggiati ripidi al di sotto dei 2500 m circa. In queste aree, sono previste valanghe spontanee, anche di grandi dimensioni. Inoltre, in alcuni punti le valanghe umide e bagnate possono subire un distacco già in seguito al passaggio di un singolo appassionato di sport invernali, anche sui pendii ripidi esposti a ovest, nord ed est al di sotto dei 2800 m circa.

Isolati punti pericolosi per valanghe asciutte si trovano sui pendii ombreggiati molto ripidi al di sopra dei 2500 m circa.
Inoltre in alta montagna gli accumuli di neve ventata di più recente formazione possono a livello isolato subire un distacco, principalmente sui pendii ombreggiati vicino alle creste. Gli accumuli di neve ventata sono per lo più piccoli.

Manto nevoso

Situazione tipo st.3: pioggia su neve | st.1: strato debole persistente basale

La superficie del manto nevoso non riuscirà a rigelarsi durante la notte coperta e risulterà ammorbidita già al mattino. Cadrà pioggia sino ai 2500 m. La pioggia causerà principalmente sui pendii ombreggiati ripidi una destabilizzazione all'interno del manto nevoso.

Sui pendii ripidi esposti a ovest, nord ed est al di sopra dei 2500 m circa: Nella parte superiore del manto di neve vecchia si trovano, a livello isolato, strati fragili instabili. Nella parte basale del manto di neve vecchia si trovano strati fragili a cristalli sfaccettati.

Cadrà neve al di sopra dei 2500 m circa. Con vento forte in alta montagna si formeranno accumuli di neve ventata di piccole dimensioni.

Tendenza

Con l'abbassamento del limite delle nevicate, leggero calo del pericolo di valanghe di neve bagnata. In alcune aree, cadrà neve al di sopra dei 2000 m circa.

Grado di pericolo 2 - Moderato

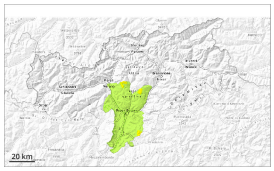

2000m

Tendenza: pericolo valanghe stabile
per Martedì il 14.04.2026

Neve bagnata

2000m

La neve bagnata è la principale fonte di pericolo. Con la pioggia, sono previste valanghe spontanee di neve bagnata.

Il pericolo di valanghe di neve umida e bagnata sarà superiore già al mattino. Con la pioggia, la probabilità di distacco di valanghe di neve bagnata aumenterà soprattutto sui pendii ombreggiati ripidi. Sono previste isolate valanghe spontanee, anche di medie dimensioni.

Manto nevoso

Situazione tipo st.10: situazione primaverile | st.1: strato debole persistente basale

La superficie del manto nevoso non riuscirà a rigelarsi durante la notte coperta e risulterà ammorbidita già al mattino. Cadrà pioggia sino al di sopra dei 2200 m. Verso sera le condizioni meteo causeranno un progressivo impregnamento del manto nevoso. Ciò causerà principalmente sui pendii ombreggiati ripidi una destabilizzazione all'interno del manto nevoso.

Tendenza

Con l'abbassamento del limite delle nevicate, leggero calo del pericolo di valanghe di neve bagnata. In alcune aree, cadrà neve al di sopra dei 2000 m circa.