# Lunedì 13.04.2026

Pubblicato il 12.04.2026 alle ore 17:00

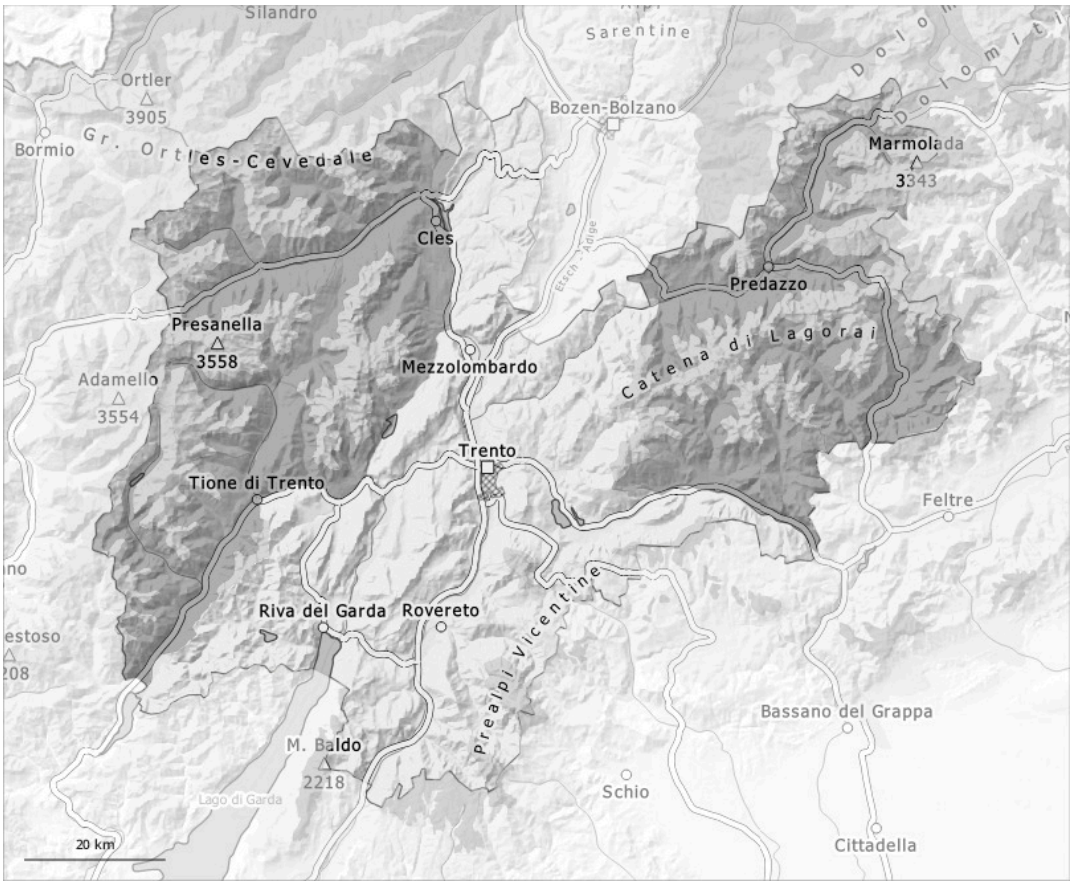


| 1 | 2 | 3 | 4 | 5 |
|---|---|---|---|---|
| debole | moderato | marcato | forte | molto forte |

## Grado di pericolo 3 - Marcato

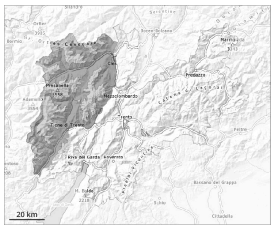

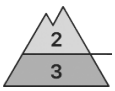


**2200m**

**Tendenza: pericolo valanghe stabile**
per Martedì il 14.04.2026

Neve bagnata

**2200m**

Neve fresca

**2200m**

## Con la pioggia, la probabilità di distacco di valanghe di neve bagnata aumenterà.

Con la pioggia, la probabilità di distacco di valanghe di neve bagnata aumenterà soprattutto al di sotto dei 2200 m circa, soprattutto sui pendii ripidi esposti a ovest, nord ed est. In queste aree, sono previste valanghe spontanee, a livello isolato anche di grandi dimensioni.

Inoltre in alta montagna gli accumuli di neve ventata di più recente formazione possono in parte subire un distacco, principalmente sui pendii vicino alle creste.
I punti pericolosi per valanghe asciutte si trovano sui pendii ombreggiati molto ripidi al di sopra dei 2200 m circa. Tali punti pericolosi sono difficili da individuare. Sfavorevoli sono principalmente i punti di passaggio da poca a molta neve, (--).

## Manto nevoso

**Situazione tipo** st.3: pioggia su neve st.6: neve a debole coesione e vento

Al di sotto dei 1800 m circa è presente solo poca neve. A quote superiori sono presenti dai 30 ai 80 cm di neve, con punte locali fino a 150 cm. La superficie del manto nevoso non riuscirà a rigelarsi durante la notte coperta e risulterà ammorbidita già al mattino. Cadrà pioggia sino ai 2200 m. La pioggia causerà principalmente sui pendii ombreggiati ripidi una destabilizzazione all'interno del manto nevoso.

Cadranno da 20 a 40 cm di neve al di sopra dei 2200 m circa, localmente anche di più. Con vento forte in alta montagna si formeranno accumuli di neve ventata in parte facilmente distaccabili.

Sui pendii ripidi esposti a ovest, nord ed est al di sopra dei 2400 m circa: Nella parte basale del manto di neve vecchia si trovano strati fragili con grani di grandi dimensioni.

## Tendenza

Con l'abbassamento del limite delle nevicate, leggero calo del pericolo di valanghe di neve bagnata. In

> alcune aree, cadrà neve al di sopra dei 2000 m circa.

## Grado di pericolo 3 - Marcato

**2200m**

**Tendenza: pericolo valanghe stabile**
per Martedì il 14.04.2026

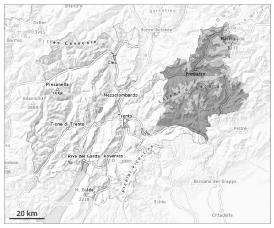

Neve bagnata

**2200m**

Strati deboli persistenti

**2400m**

## La neve bagnata è la principale fonte di pericolo. Con la pioggia, sono previste valanghe spontanee di neve bagnata.

Con la pioggia, la probabilità di distacco di valanghe di neve bagnata aumenterà soprattutto sui pendii ombreggiati ripidi al di sotto dei 2200 m circa. In queste aree, sono previste valanghe spontanee, anche di grandi dimensioni.

Isolati punti pericolosi per valanghe asciutte si trovano sui pendii ombreggiati molto ripidi al di sopra dei 2400 m circa. Tali punti pericolosi sono difficili da individuare. Sfavorevoli sono principalmente i punti di passaggio da poca a molta neve, (--).
Inoltre in alta montagna gli accumuli di neve ventata di più recente formazione possono a livello isolato subire un distacco, principalmente sui pendii ombreggiati vicino alle creste. Gli accumuli di neve ventata sono per lo più piccoli.

## Manto nevoso

**Situazione tipo** st.3: pioggia su neve | st.1: strato debole persistente basale

Al di sotto dei 1800 m circa è presente solo poca neve. A quote superiori sono presenti dai 30 ai 80 cm di neve, con punte locali fino a 150 cm. La superficie del manto nevoso non riuscirà a rigelarsi durante la notte coperta e risulterà ammorbidita già al mattino. La pioggia mista a neve causerà al di sotto dei 2200 m circa in alcuni punti una destabilizzazione all'interno del manto nevoso.

Sui pendii ripidi esposti a ovest, nord ed est al di sopra dei 2200 m circa: Nella parte basale del manto di neve vecchia si trovano strati fragili a cristalli sfaccettati.
Cadrà neve al di sopra dei 2200 m circa. Con vento forte in alta montagna si formeranno accumuli di neve ventata di piccole dimensioni.

## Tendenza

> Con l'abbassamento del limite delle nevicate, leggero calo del pericolo di valanghe di neve bagnata. In alcune aree, cadrà neve al di sopra dei 2000 m circa.

## Grado di pericolo 2 - Moderato

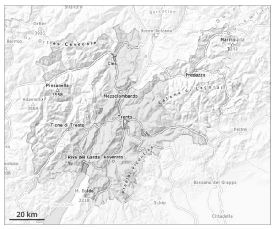

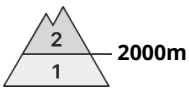


**Tendenza: pericolo valanghe stabile**
per Martedì il 14.04.2026

Neve bagnata

2000m

La neve bagnata è la principale fonte di pericolo. Con la pioggia, sono previste valanghe spontanee di neve bagnata.

Il pericolo di valanghe di neve umida e bagnata sarà superiore già al mattino. Con la pioggia, la probabilità di distacco di valanghe di neve bagnata aumenterà soprattutto sui pendii ombreggiati ripidi. Sono previste isolate valanghe spontanee, anche di medie dimensioni.

### Manto nevoso

**Situazione tipo** st.10: situazione primaverile | st.1: strato debole persistente basale

La superficie del manto nevoso non riuscirà a rigelarsi durante la notte coperta e risulterà ammorbidita già al mattino. Cadrà pioggia sino al di sopra dei 2200 m. Verso sera le condizioni meteo causeranno un progressivo impregnamento del manto nevoso. Ciò causerà principalmente sui pendii ombreggiati ripidi una destabilizzazione all'interno del manto nevoso.

### Tendenza

Con l'abbassamento del limite delle nevicate, leggero calo del pericolo di valanghe di neve bagnata. In alcune aree, cadrà neve al di sopra dei 2000 m circa.