Lunedì 13.04.2026

Pubblicato il 12.04.2026 alle ore 17:00

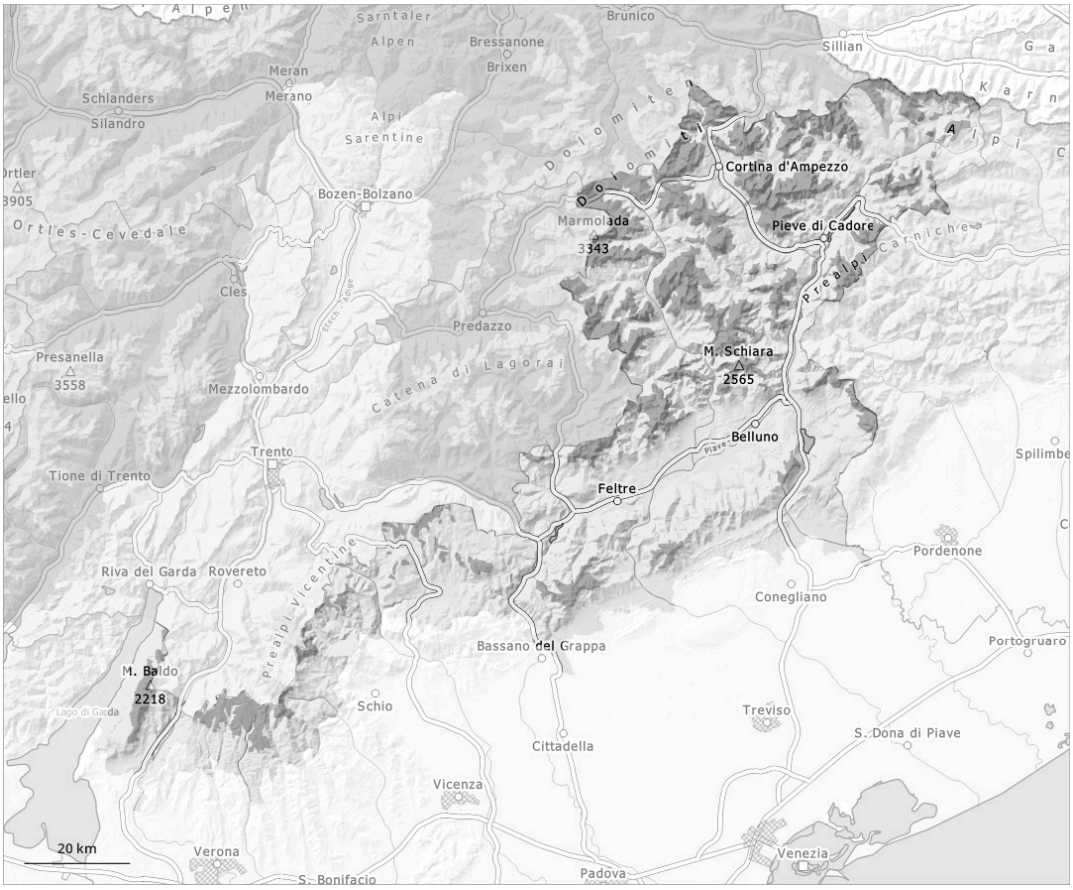

1	2	3	4	5
debole	moderato	marcato	forte	molto forte

Grado di pericolo 3 - Marcato

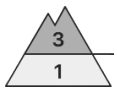

1200m

Tendenza: pericolo valanghe stabile
per Martedì il 14.04.2026

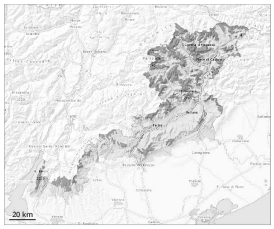

Neve bagnata

1200m

Neve bagnata

2500m

Lastrone da vento

2500m

Strati deboli persistenti

2000m

Neve bagnata e neve slittante sono la principale fonte di pericolo. Neve fresca e neve ventata al di sopra dei 2200 m circa.

In molte regioni lunedì cadranno sino a 20 cm di neve al di sopra dei 2500 m circa, localmente anche di più. Fino a martedì cadranno sino a 40 cm di neve, localmente anche di più. Cadrà pioggia sino ai 2000 m.
I punti pericolosi sono molto diffusi e con il cattivo tempo appena individuabili. I punti pericolosi per valanghe bagnate si trovano specialmente sulle scarpate al di sotto dei 2200 m circa. Nelle regioni più colpite dalle precipitazioni, questi punti pericolosi sono più diffusi. Soprattutto dai bacini di alimentazione non ancora completamente scaricati le valanghe bagnate possono raggiungere dimensioni piuttosto grandi.
La neve fresca può distaccarsi spontaneamente a tutte le esposizioni al di sopra dei 2500 m circa. Soprattutto sui pendii molto ripidi e ai piedi di pareti rocciose e dietro ai cambi di pendenza sono possibili valanghe di piccole e, a livello isolato, di medie dimensioni. Particolarmente pericolosi sono i punti alla base di pareti rocciose, (--).
Con neve fresca e vento forte proveniente da sud est principalmente al di sopra dei 2500 m circa si formeranno accumuli di neve ventata instabili. I nuovi accumuli di neve ventata possono in molti punti distaccarsi già in seguito al passaggio di un singolo appassionato di sport invernali e raggiungere dimensioni medie. I punti pericolosi si trovano soprattutto nei punti in prossimità delle creste, nelle conche e nei canaloni esposti da nord ovest a nord sino a nord est al di sopra dei 2500 m circa.
Sui pendii ombreggiati, gli strati deboli presenti nella neve vecchia possono distaccarsi in seguito al

passaggio di alcuni appassionati di sport invernali. Particolarmente pericolosi sono i punti di passaggio da poca a molta neve, dove nel manto di neve vecchia sono presenti strati deboli. Le valanghe possono coinvolgere il manto di neve vecchia e raggiungere dimensioni medie.

Manto nevoso

Situazione tipo st.3: pioggia su neve st.1: strato debole persistente basale

Sui pendii esposti a nord ovest, nord e nord est, all'interno del manto nevoso si trovano insidiosi strati fragili.
La pioggia mista a neve causerà soprattutto sui pendii ripidi al di sotto dei 2200 m circa diffusamente una destabilizzazione all'interno del manto nevoso.