BUTLLETÍ DEL PERILL D'ALLAUS DEL PRINCIPAT D'ANDORRA

Elaborado el 12/04/2026 16:00
Proxima actualización 13/04/2026 a las 16h

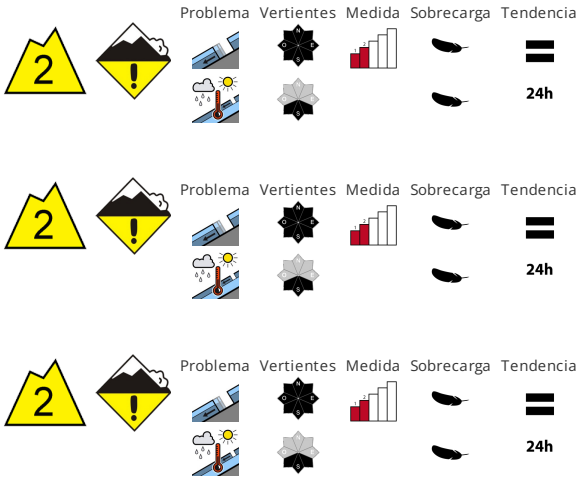

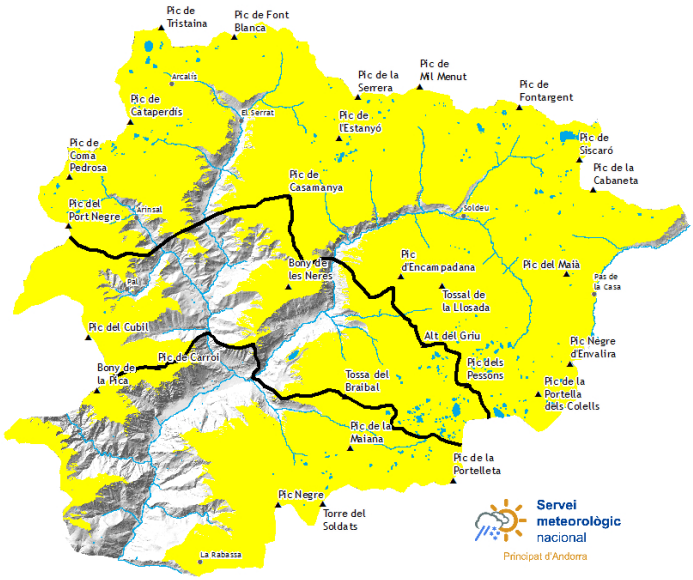

CALIDAD DE LA NIEVE

El poco de nieve reciente y las placas de viento en su mayoría pequeñas pueden fácilmente desencadenarse de manera natural o accidental especialmente en laderas solanas inclinadas. Con la subida de la temperatura diurna y la radiación solar, son probables purgas y avalanchas de nieve húmeda de tamaño pequeño y, localmente, mediano. Además son posibles algunos aludes de deslizamiento basal.

ESTABILIDAD DEL MANTO NIVOSO

La capa de nieve reciente es en su mayor parte estable, con una superficie blanda. En el transcurso de la jornada la radiación solar causará una progresiva humidificación del manto de nieve en las laderas solanas. Evitar las zonas con grietas de deslizamiento basal.

ESPESORES DEL MANTO NIVOSO FUERA DE PISTA

Zona norte		Espesor nieve		
Manto Nival		1500m	2000m	2500m
N	1600 m	0 cm	150 cm	250 cm
S	1800 m	0 cm	100 cm	180 cm

zona centro		Espesor nieve		
Manto Nival		1500m	2000m	2500m
N	1600 m	0 cm	120 cm	160 cm
S	1800 m	0 cm	60 cm	120 cm

Zona sur		Espesor nieve		
Manto Nival		1500m	2000m	2500m
N	1600 m	0 cm	120 cm	160 cm
S	1800 m	0 cm	60 cm	120 cm

Govern d'Andorra

Aquest butlletí ha estat elaborat seguint les normes i recomanacions de l'**European Avalanche Warning Services**, del qual el **Servei meteorològic Nacional** n'és membre

BUTLLETÍ DEL PERILL D'ALLAUS DEL PRINCIPAT D'ANDORRA

Servei meteorològic nacional
Principat d'Andorra

Información detallada por espacios naturales protegidos

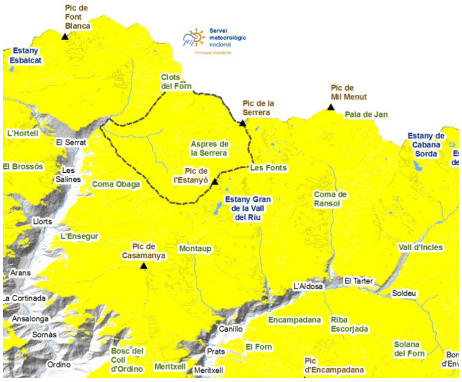

SORTENY

Después de la nevada de la noche del domingo, con nieve en todas las cotas del Parque Natural y sus accesos como Ransol, esperamos que el sol humidifique la nieve y purgue las vertientes soleadas. Sin embargo, en las cimas fronterizas con Francia, como la Serrera, todavía quedará nubosidad residual y débiles nevadas.

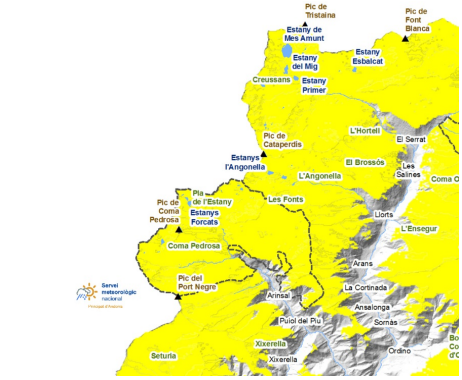

COMAPEDROSA

Nubosidad residual en el extremo norte del Parque Natural, pero los claros irán ganando protagonismo en el sur sobre todo por la tarde. La nieve nueva se humidificará, sobre todo en cotas bajas y en laderas sur y se compactará. En las vertientes más inclinadas bajarán purgas de nieve húmeda.

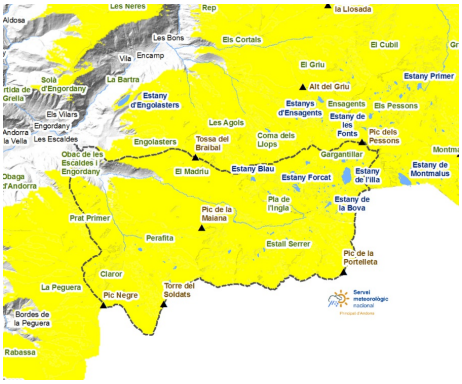

MADRIU-PERAFITA-CLAROR

A primera hora de la mañana, la visibilidad aún no será buena, pero los claros irán ganando protagonismo de sur a norte. El sol estabilizará el manto con su compactación, pero durante el durante el día esperamos purgas en las vertientes sur.

Govern d'Andorra

EAWS
EUROPEAN AVALANCHE WARNING SERVICES

Aquest butlletí ha estat elaborat seguint les normes i recomanacions de l'**European Avalanche Warning Services**, del qual el **Servei meteorològic Nacional** n'és membre

BUTLLETÍ DEL PERILL D'ALLAUS DEL PRINCIPAT D'ANDORRA

Servei meteorològic nacional
Principat d'Andorra

Espesores de nieve nueva de los últimos días (de las ultimas 24h mesurado a las 06:00h UTC)

	08/04/2026	09/04/2026	10/04/2026	11/04/2026
FEDA (Central)	0 cm	0 cm	0 cm	0 cm
Engolasters - FEDA	0 cm	0 cm	0 cm	0 cm
Bony de les Neres	0 cm	0 cm	0 cm	0 cm
Sorteny	0 cm	0 cm	0 cm	0 cm
Les Fonts d'Arinsal	0 cm	0 cm	0 cm	0 cm
Aixàs	0 cm	0 cm	0 cm	0 cm
Perafita	0 cm	0 cm	0 cm	0 cm
Tossa Espiolets	0 cm	0 cm	0 cm	0 cm
Grau Roig - FEDA	0 cm	0 cm	0 cm	0 cm
Fontverd	0 cm	0 cm	0 cm	0 cm
Coll Ordino	0 cm	0 cm	0 cm	0 cm
Ransol - FEDA	0 cm	0 cm	0 cm	0 cm
Setúria	0 cm	0 cm	0 cm	0 cm
Caborreu	0 cm	0 cm	0 cm	0 cm
La Solana	0 cm	0 cm	0 cm	0 cm
Coll Pa	0 cm	0 cm	0 cm	0 cm
Envalira Antenes	0 cm	0 cm	0 cm	0 cm
Vall del Riu FEDA	0 cm	0 cm	0 cm	0 cm