BUTLLETÍ DEL PERILL D'ALLAUS DEL PRINCIPAT D'ANDORRA

Préparé le 12/04/2026 16:00
Prochaine mise à jour le 13/04/2026 à 16h

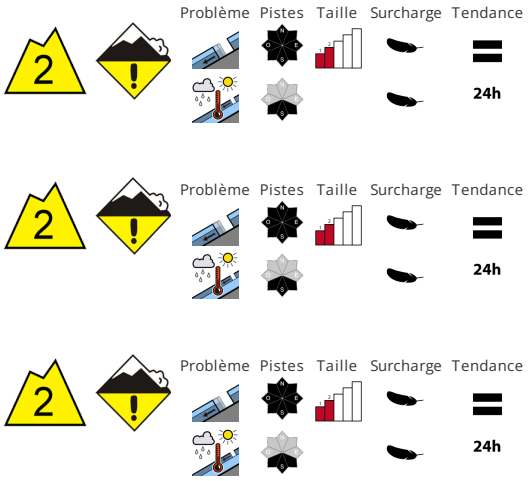

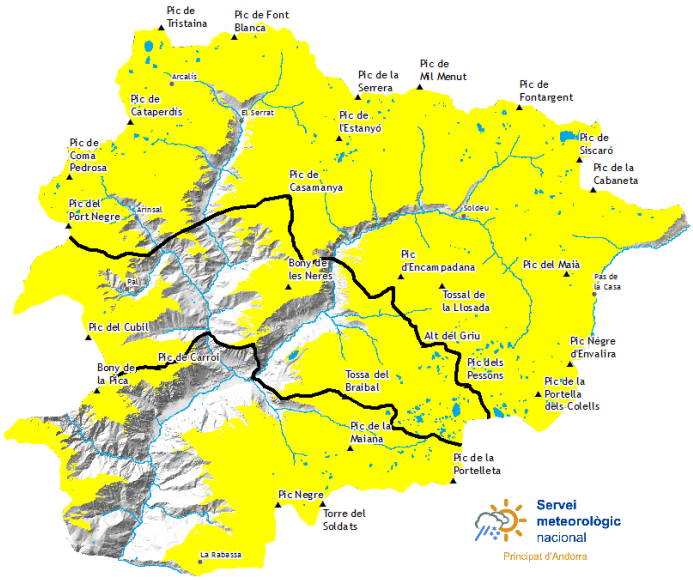

STABILITÉ DU MANTEAU NEIGEUX

Un peu de neige fraîche et les accumulations de neige soufflée généralement petites peuvent être déclenchées facilement ou glisser spontanément surtout sur les pentes raides ensoleillées. Des avalanches et coulées humides de petite et rarement moyenne taille sont ils sont à attendre avec le réchauffement diurne et le rayonnement solaire. En outre, des avalanches de glissement isolées sont possibles..

QUALITÈ DE LA NEIGE

La couche de neige fraîche est largement stable , avec une surface meuble. Le rayonnement solaire en cours de journée entraîne sur les pentes au soleil une humidification croissante du manteau neigeux. Les zones présentant des fissures de glissement doivent être évitées..

EPAISSEUR DE NEIGE HORS PISTE

Zone nord		Epaisseur de neige		
Nival manteau		1500m	2000m	2500m
N	1600 m	0 cm	150 cm	250 cm
S	1800 m	0 cm	100 cm	180 cm

Zone centre		Epaisseur de neige		
Nival manteau		1500m	2000m	2500m
N	1600 m	0 cm	120 cm	160 cm
S	1800 m	0 cm	60 cm	120 cm

Zone sud		Epaisseur de neige		
Nival manteau		1500m	2000m	2500m
N	1600 m	0 cm	120 cm	160 cm
S	1800 m	0 cm	60 cm	120 cm

BUTLLETÍ DEL PERILL D'ALLAUS DEL PRINCIPAT D'ANDORRA

Servei meteorològic nacional
Principat d'Andorra

Des informations détaillées par espace naturel protégé

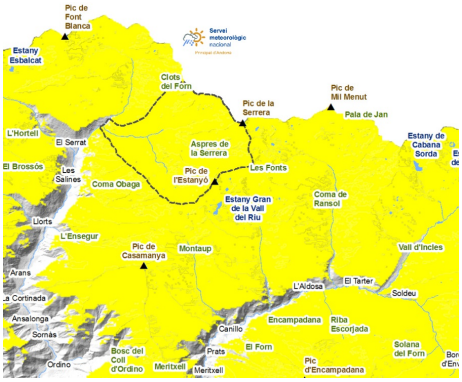

SORTENY

Après les chutes de neige de dimanche soir, avec de la neige à toutes les altitudes du Parc Naturel et ses accès comme Ransol, nous espérons que le soleil humidifiera la neige et dégagera les pentes ensoleillées. Il y aura néanmoins encore de la nébulosité résiduelle et de la faible neige sur les sommets limitrophes de la France, comme la Serra. , , ,

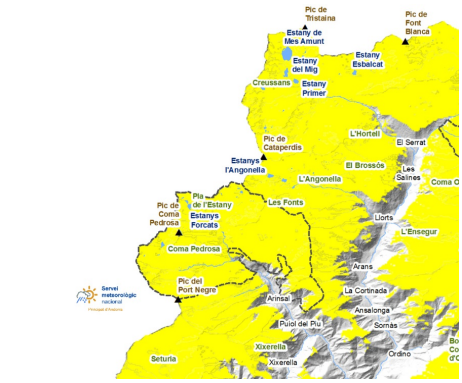

COMAPEDROSA

Nébulosité résiduelle dans la partie nord du Parc Naturel, mais les éclaircies gagneront en importance dans le sud, surtout dans l'après-midi. Surtout à basse altitude et sur les versants sud, la nouvelle neige sera humidifiée et compactée. Des purges de neige mouillée descendront sur les pentes les plus raides. , , , , ,

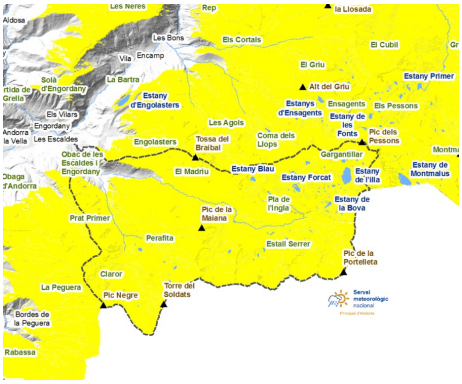

MADRIU-PERAFITA-CLAROR

Au petit matin, la visibilité ne sera toujours pas bonne, mais les clairières gagneront en importance du sud au nord. Le soleil va stabiliser le manteau avec son compactage, mais en journée on s'attend à des purges sur les versants sud. , , ,

Govern d'Andorra

EAWS
EUROPEAN AVALANCHE WARNING SERVICES

Aquest butlletí ha estat elaborat seguint les normes i recomanacions de l'**European Avalanche Warning Services**, del qual el **Servei meteorològic Nacional** n'és membre

BUTLLETÍ DEL PERILL D'ALLAUS DEL PRINCIPAT D'ANDORRA

Servei meteorològic nacional
Principat d'Andorra

Couche de neige fraiche des derniers jours (De 24 h mesurée à 06:00 h UTC)

	08/04/2026	09/04/2026	10/04/2026	11/04/2026
FEDA (Central)	0 cm	0 cm	0 cm	0 cm
Engolasters - FEDA	0 cm	0 cm	0 cm	0 cm
Bony de les Neres	0 cm	0 cm	0 cm	0 cm
Sorteny	0 cm	0 cm	0 cm	0 cm
Les Fonts d'Arinsal	0 cm	0 cm	0 cm	0 cm
Aixàs	0 cm	0 cm	0 cm	0 cm
Perafita	0 cm	0 cm	0 cm	0 cm
Tossa Espiolets	0 cm	0 cm	0 cm	0 cm
Grau Roig - FEDA	0 cm	0 cm	0 cm	0 cm
Fontverd	0 cm	0 cm	0 cm	0 cm
Coll Ordino	0 cm	0 cm	0 cm	0 cm
Ransol - FEDA	0 cm	0 cm	0 cm	0 cm
Setúria	0 cm	0 cm	0 cm	0 cm
Caborreu	0 cm	0 cm	0 cm	0 cm
La Solana	0 cm	0 cm	0 cm	0 cm
Coll Pa	0 cm	0 cm	0 cm	0 cm
Envalira Antenes	0 cm	0 cm	0 cm	0 cm
Vall del Riu FEDA	0 cm	0 cm	0 cm	0 cm