Bulletin d'estimation du risque d'avalanche
(valable en dehors des pistes balisées et ouvertes)

MASSIF : Aravis

Rédigé le dimanche 12 avril 2026 à 16h

Estimation des risques pour le : LUNDI 13 AVRIL

MANTEAU NEIGEUX HUMIDE.

2

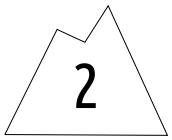

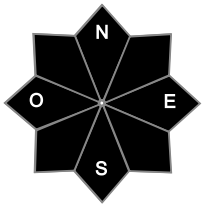

Indice de risque limité.

Départs spontanés : Avalanches en neige humide.

Déclenchements provoqués : Avalanches de neige humide sous les skis.

Indices de risque : 5 très fort - 4 fort - 3 marqué - 2 limité - 1 faible -- En noir : les pentes les plus dangereuses

Stabilité du manteau neigeux

Situation avalancheuse typique : neige humide couche fragile persistante

Départs spontanés :

* **Avalanches de neige humide** sur tous les versants jusqu'à 2300/2500 m sur tous sur les versants. Taille 1 à 2 (petite à moyenne).

*Facteur aggravant : **départ en cascade** possible sur un secteur Est à Nord Ouest sur de la **couche fragile persistante** enfouie sous environ **1m/1m20 de neige**. Taille 2 à 3 (moyenne à grande)*

* **Au-dessous de 2000m**, des avalanches de **plaques humides** peuvent aussi partir spontanément lors de l'humidification d'une couche fragile enfouie sous 30/40 cm de neige. Taille 1 à 2.
* Des **avalanches de fond** sont possibles à toute heure du jour et de la nuit, sur les pentes herbeuses ou les dalles rocheuses. Taille 2.

Déclenchements provoqués :

* Au passage d'un skieur, de la neige humide peut couler sous les skis. Ces avalanches concernent toutes les orientations et toutes altitudes. Au-delà de 2000m en ubacs, le skieur peut également déclencher une plaque humide de 30/40 cm d'épaisseur.
* Au-dessus de 2400 m : plaque de neige fraiche. De petite taille (Taille 1), mais qui pourrait au-dessus de 2000m en ubacs déclencher une plaque humide de 30/40 cm d'épaisseur.

Autres :

* En dessous de 2400 m : chutes de corniche possible au vu de l'humidification des versants nord d'altitude et de l'absence de regel nocturne.

Qualité de la neige

Enneigement :

L'enneigement est correct au-dessus de 2000m. En dessous, il commence à être déficitaire.
On peut chausser les skis au-dessus de 1700/1800 m en sud et 1400/1500 m en nord. Des traces de neige sont présentes sous ces altitudes, mais l'enneigement est loin d'être continu.

Qualité de la neige lundi :

* Absence de regel nocturne sous 2400 m.
* En dessous de 2000 m : neige humide
* Entre de 2000 m et 2400 m : fine couche de neige fraiche humide sur fond humide
* Au-dessus de 2400 m : fine couche de neige fraiche sur fond humide en cours de regel.

Aperçu météo pour le lundi 13 avril

	nuit	matin	après-midi	soir

Couvert toute la journée, quelques averses le matin puis en deuxième partie d'après-midi. Limite pluie-neige 1900/2000 m.

Pluie-Neige	2 100 m	2 000 m	2 000 m	1 700 m
Iso 0 °C	2 500 m	2 300 m	2 200 m	2 100 m
Vent 2000 m	↗ 15 km/h	↙ 15 km/h	↙ 20 km/h	↓ 15 km/h
Vent 2500 m	↑ 30 km/h	↖ 20 km/h	↙ 25 km/h	↙ 30 km/h

Épaisseur de neige hors-piste

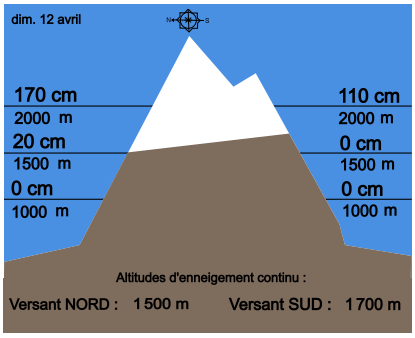

Précipitations à 1800 m

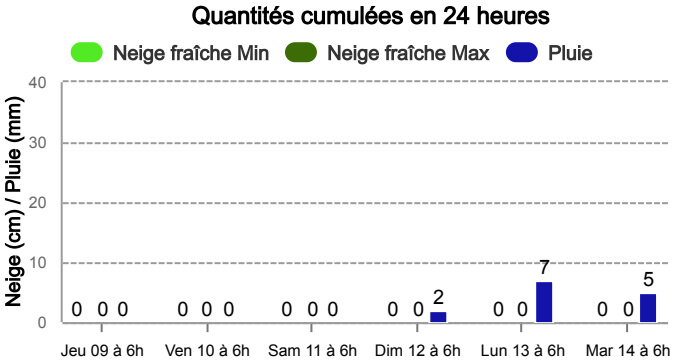

Tendance du mardi 14 avril

2

Indice de risque limité

Risque stationnaire. Pas de regel nocturne, couvert le matin puis rares éclaircies l'après-midi.

Pour consulter la vigilance en cours, veuillez vous rendre sur le site https://vigilance.meteofrance.fr/fr

Météo-France - 73 avenue de Paris, 94165 Saint-Mandé cedex - Contact : contact@meteo.fr

Rédigé par Météo-France avec la contribution des observateurs du réseau nivo-météorologiques. Partenariat : ANMSM (Maires de Stations de Montagne), DSF (Domaines Skiables de France), ADSP (Directeurs de Pistes et de la Sécurité des Stations de Sports d'Hiver) et autres acteurs de la montagne.

Bulletin neige & avalanches par téléphone au **0 892 68 10 20** Service 0,35 € / min + prix appel

Bulletin d'estimation du risque d'avalanche

(valable en dehors des pistes balisées et ouvertes)

MASSIF : Aravis

Rédigé le dimanche 12 avril 2026 à 16h

Conditions nivo-météo des 7 derniers jours

	lun. 06/04				mar. 07/04				mer. 08/04				jeu. 09/04				ven. 10/04				sam. 11/04				dim. 12/04			
	03h	09h	15h	21h	03h	09h	15h	21h	03h	09h	15h	21h	03h	09h	15h	21h	03h	09h	15h	21h	03h	09h	15h	21h	03h	09h	15h	21h
Météo																												
Vent (km/h)	40	30	30	20	10	10	5	10	20	25	5	5	10	15	15	15	20	15	15	20	20	25	25	25	35	30	30	30
à 2500m																												
Vent (km/h)	20	20	15	10	10	10	5	10	25	20	5	5	5	5	10	10	15	10	10	15	10	20	20	20	20	20	20	20
à 2000m																												

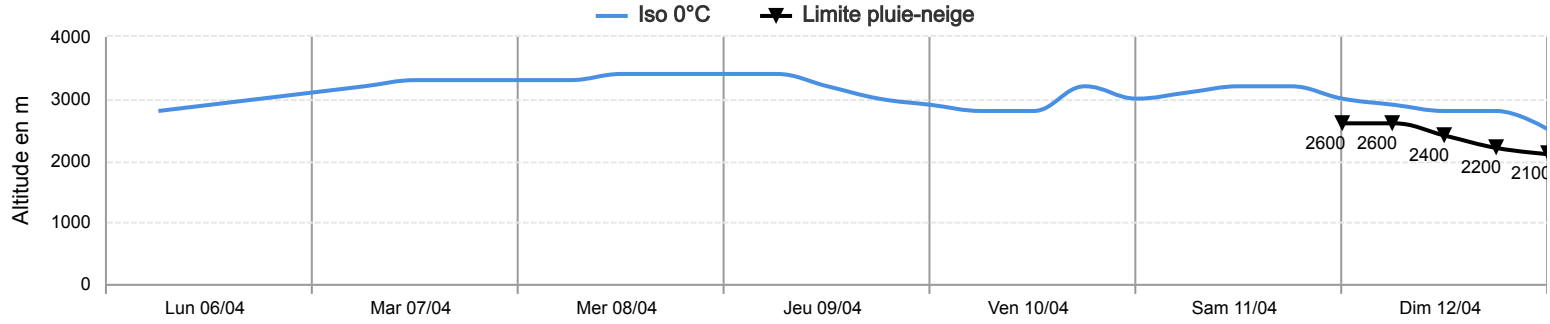

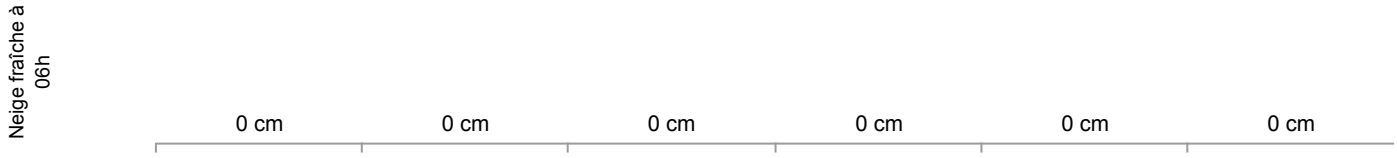

Risque d'avalanche	lun. 06/04	mar. 07/04	mer. 08/04	jeu. 09/04	ven. 10/04	sam. 11/04	dim. 12/04
	2	2	2	3	3	3	2

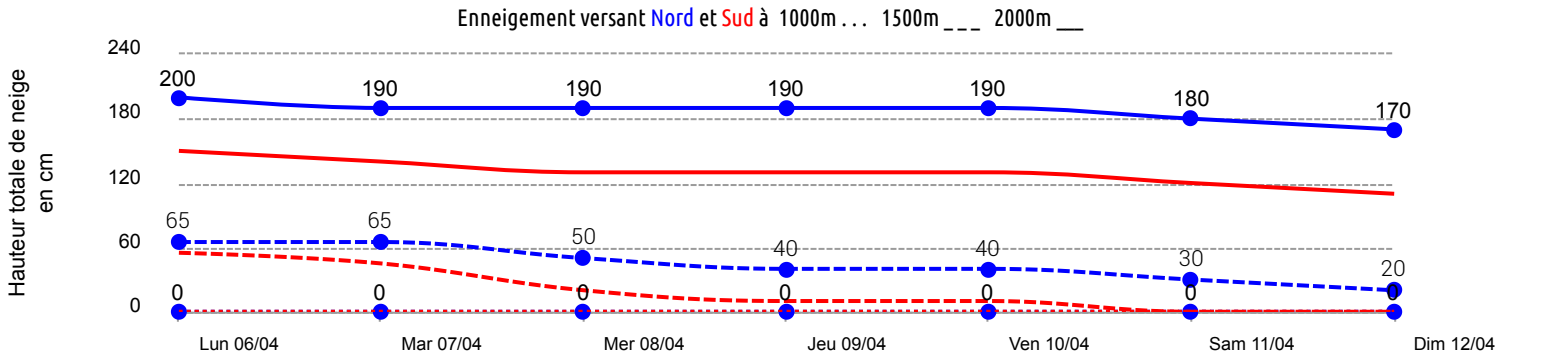

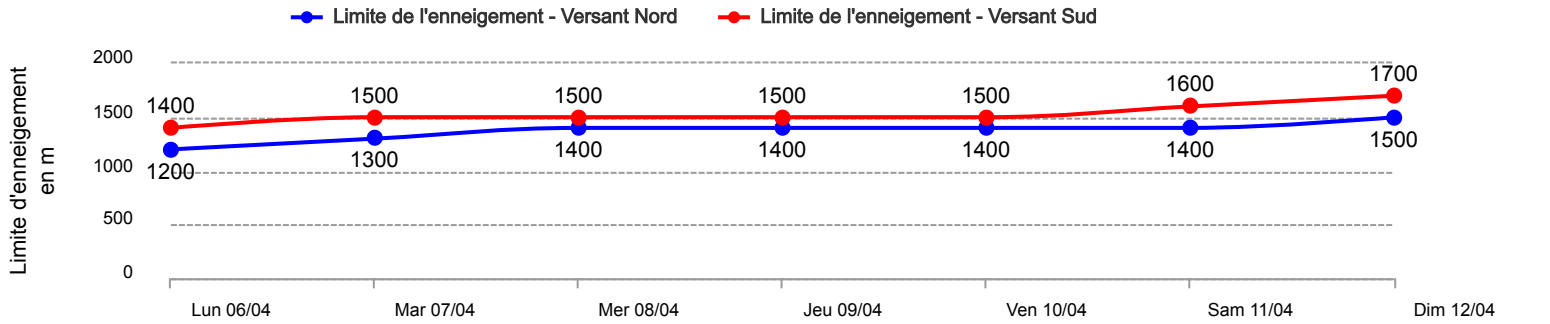

Pour consulter la vigilance en cours, veuillez vous rendre sur le site https://vigilance.meteofrance.fr/fr

Météo-France - 73 avenue de Paris, 94165 Saint-Mandé cedex - Contact : contact@meteo.fr

Bulletin neige & avalanches par téléphone au

0 892 68 10 20 Service 0,35 € / min + prix appel

Rédigé par Météo-France avec la contribution des observateurs du réseau nivo-météorologiques. Partenariat : ANMSM (Maires de Stations de Montagne), DSF (Domaines Skiables de France), ADSP (Directeurs de Pistes et de la Sécurité des Stations de Sports d'Hiver) et autres acteurs de la montagne.