Bulletin d'estimation du risque d'avalanche

(valable en dehors des pistes balisées et ouvertes)

MASSIF : Aspe Ossau

Rédigé le dimanche 12 avril 2026 à 16h

Estimation des risques pour le : LUNDI 13 AVRIL

CHUTES DE NEIGE PLUS OU MOINS VENTEES, COUCHE S'EPAISSISSANT AU COURS DE LA JOURNEE.

3

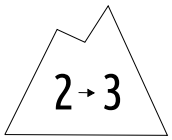

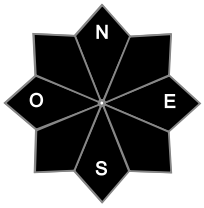

Indice de risque limité évoluant en marqué.

Départs spontanés : en neige récente.

Déclenchements provoqués : instabilités dans la neige récente et plaques en formation.

Indices de risque : 5 très fort - 4 fort - 3 marqué - 2 limité - 1 faible -- En noir : les pentes les plus dangereuses

Stabilité du manteau neigeux

Situation avalancheuse typique : neige ventée

Déclenchements provoqués : instabilités dans la **neige récente en tous secteurs**, subissant du **vent de nord** durant la journée.
- **déclenchement facile** par un seul skieur ou randonneur de **petites avalanches en matinée, devenant moyennes l'après-midi**. La **neige tombée dimanche** s'est souvent posée **sans vent**, constituant ainsi une **couche peu résistante aux sollicitations des plaques** qui **se forment et s'épaississent progressivement durant la journée** sous le vent de nord modéré, **au-dessus de 2000m**.
- **sous 2000m**, **déclenchement facile** de coulées de neige récente dans le **pentes raides**.

***Observables** : effet du vent visibles et indentifiables au-dessus de 2000m en versants nord, plus subtils et moins évidents en versants sud où se constituent des accumulations un peu plus importantes de neige d'aspect poudreux.*

Départs spontanés : en neige récente en tous secteurs.
- **départs ponctuels** de **coulées et petites avalanches de neige récente dans les pentes raides en matinée** durant les chutes,
- quelques **cassures linéaires plutôt au-dessus de 2000m dans l'après-midi** : les **chutes de neige** accompagnées de **vent de nord modéré** se poursuivant en journée, le **transport de la neige** provoquera des **surcharges** susceptibles de **déclencher les plaques décrites ci-dessus**, entraînant le départ d'**avalanches petites à parfois moyennes**.
- de **rares plaques de fond encore possibles en versant sud sur le haut du massif** : le départ d'une plaque ou accumulation se formant durant la journée peut localement déclencher quelques avalanches moyennes à rarement grandes par effet de cascade en entraînant la vieille neige encore en place en contrebas, mal ou très peu durcie, et restant mobilisable.

Autres : temps froid avec vent de nord désagréable. Pont de neige et corniches restant fragiles car le refroidissement avant les chutes de neige n'a été que superficiel et peu marqué.

Qualité de la neige

Enneigement : avec le retour de conditions hivernales, l'enneigement est bon pour la saison, débutant vers 1500 à 1600m. Saupoudrage ou quelques centimètres de neige sur un sol nu sous cette limite au petit matin, limite s'abaissant encore au cours de la journée sous les averses de neige.

État de la neige : temps froid et chutes de neige se poursuivant, on trouvera ce lundi de la neige fraîche et sèche dont l'épaisseur augmente au cours de la journée, plus ou moins travaillée par le vent de nord au fil des heures ; neige frittée près des cols et des crêtes, plus meuble partout ailleurs.

Cette neige récente repose souvent sur de la vieille neige humide à peine ou mal regelée mais portante.

Aperçu météo pour le lundi 13 avril

	nuit	matin	après-midi	soir

Temps froid, averses de neige à basse altitude pour la saison, vent de nord modéré en altitude.

Pluie-Neige	1 000 m	1 100 m	1 100 m	
Iso 0 °C	1 300 m	1 400 m	1 500 m	1 500 m
Vent 1500 m	↓ 15 km/h	↓ 15 km/h	↓ 10 km/h	↻ 5 km/h
Vent 3000 m	↓ 55 km/h	↓ 45 km/h	↓ 35 km/h	↙ 30 km/h

Épaisseur de neige hors-piste

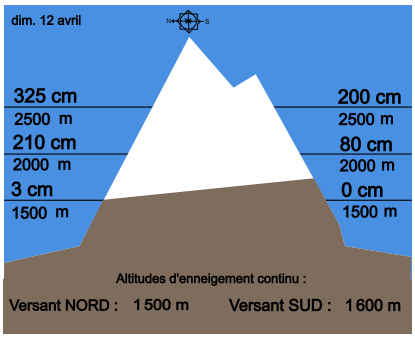

Précipitations à 1800 m

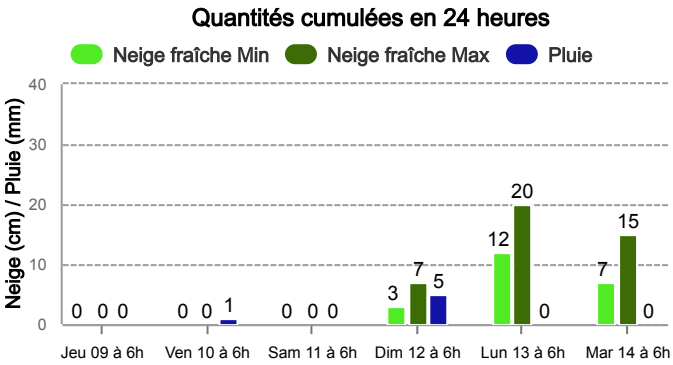

Tendance du mardi 14 avril

3

Indice de risque marqué

Retour d'un temps sec et ensoleillé, froid le matin, se radoucissant en journée : les instabilités persistent en matinée, se stabilisent lentement ensuite. Le risque devrait évoluer de marqué à limité.

Pour consulter la vigilance en cours, veuillez vous rendre sur le site https://vigilance.meteofrance.fr/fr

Météo-France - 73 avenue de Paris, 94165 Saint-Mandé cedex - Contact : contact@meteo.fr

Rédigé par Météo-France avec la contribution des observateurs du réseau nivo-météorologiques. Partenariat : ANMSM (Maires de Stations de Montagne), DSF (Domaines Skiables de France), ADSP (Directeurs de Pistes et de la Sécurité des Stations de Sports d'Hiver) et autres acteurs de la montagne.

Bulletin neige & avalanches par téléphone au

0 892 68 10 20 Service 0,35 € / min + prix appel

Bulletin d'estimation du risque d'avalanche

(valable en dehors des pistes balisées et ouvertes)

MASSIF : Aspe Ossau

Rédigé le dimanche 12 avril 2026 à 16h

Conditions nivo-météo des 7 derniers jours

	lun. 06/04				mar. 07/04				mer. 08/04				jeu. 09/04				ven. 10/04				sam. 11/04				dim. 12/04			
	03h	09h	15h	21h	03h	09h	15h	21h	03h	09h	15h	21h	03h	09h	15h	21h	03h	09h	15h	21h	03h	09h	15h	21h	03h	09h	15h	21h
Météo																												
Vent (km/h)	15	25	35	40	40	35	30	20	30	20	20	25	20	20	15	10	20	35	35	45	40	45	35	60	30	25	20	30
à 3000m																												
Vent (km/h)	10	10	10	20	20	15	20	15	10	15	10	5	5	5	5	2	5	5	10	25	25	25	20	10	15	10	10	10
à 1500m																												

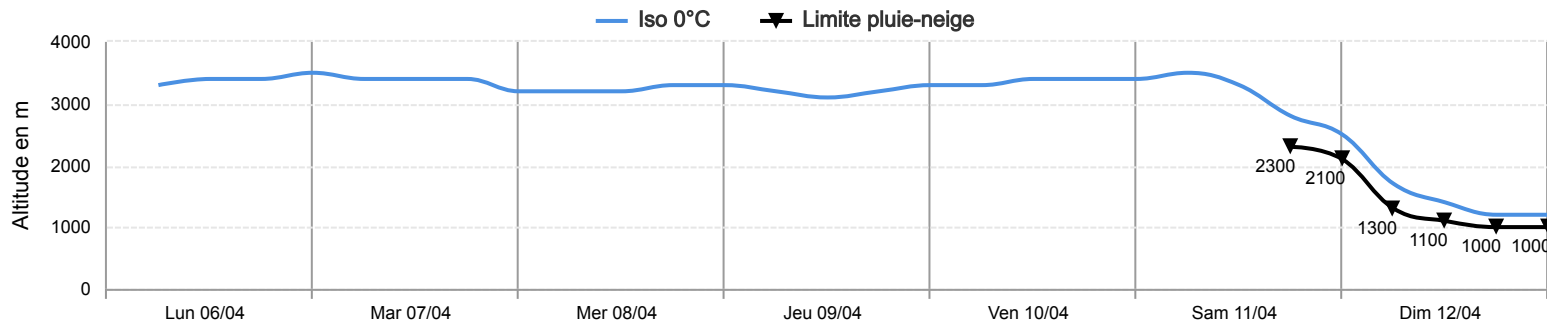

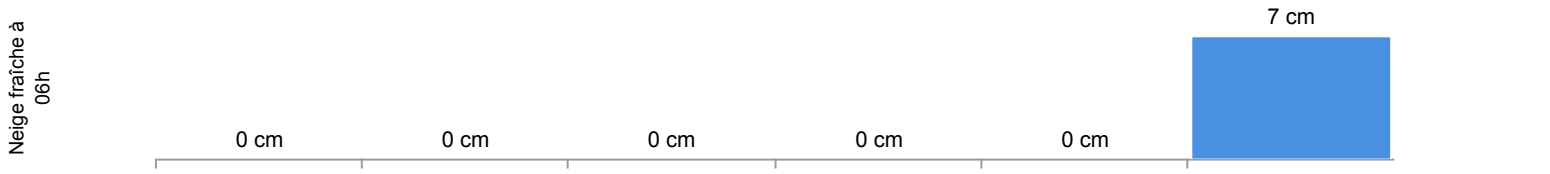

Risque d'avalanche	lun. 06/04	mar. 07/04	mer. 08/04	jeu. 09/04	ven. 10/04	sam. 11/04	dim. 12/04
	2	2	2	2	2	2	2

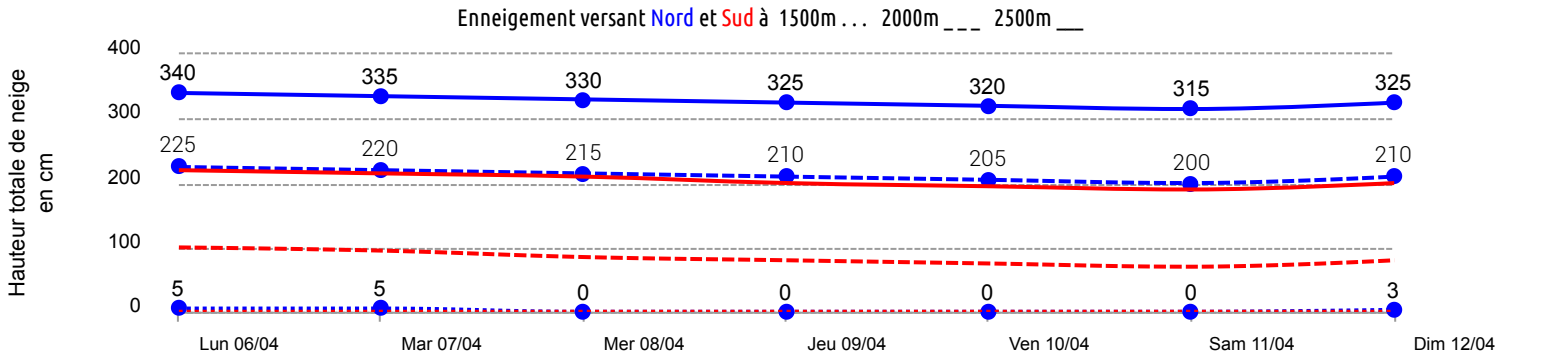

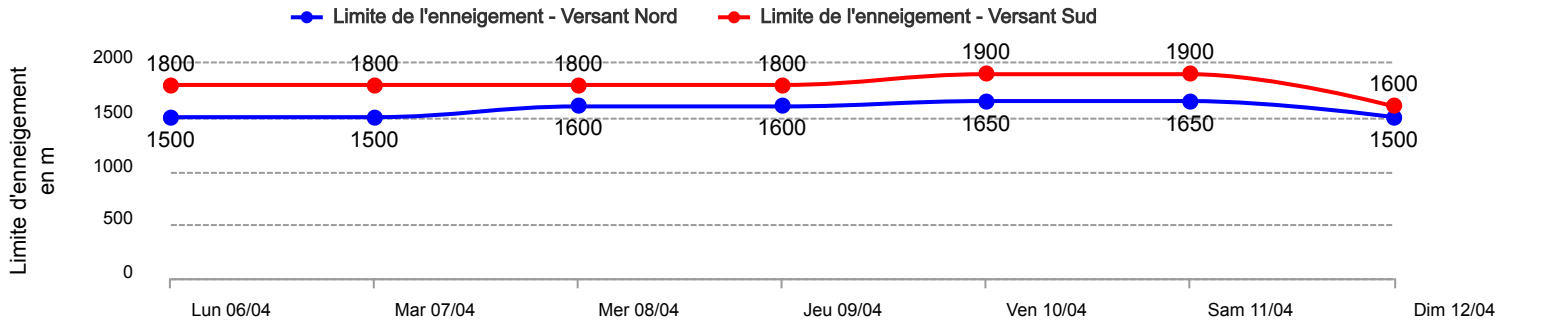

Pour consulter la vigilance en cours, veuillez vous rendre sur le site https://vigilance.meteofrance.fr/fr

Météo-France - 73 avenue de Paris, 94165 Saint-Mandé cedex - Contact : contact@meteo.fr

Bulletin neige & avalanches par téléphone au 0 892 68 10 20 Service 0,35 € / min + prix appel

Rédigé par Météo-France avec la contribution des observateurs du réseau nivo-météorologiques. Partenariat : ANMSM (Maires de Stations de Montagne), DSF (Domaines Skiables de France), ADSP (Directeurs de Pistes et de la Sécurité des Stations de Sports d'Hiver) et autres acteurs de la montagne.