Bulletin d'estimation du risque d'avalanche

(valable en dehors des pistes balisées et ouvertes)

MASSIF : Cerdagne Canigou

Rédigé le dimanche 12 avril 2026 à 16h

Estimation des risques pour le : LUNDI 13 AVRIL

BAISSE DU RISQUE SPONTANÉ, QUELQUES PLAQUES EN NEIGE FRAÎCHE.

2

2

N O E S

Indice de risque limité.

Départs spontanés : Petites coulées de surface de petites taille.

Déclenchements provoqués : Nombreuses plaques en formation de faible épaisseur.

Indices de risque : 5 très fort - 4 fort - 3 marqué - 2 limité - 1 faible -- En noir : les pentes les plus dangereuses

Stabilité du manteau neigeux

Situation avalancheuse typique : neige fraîche

Déclenchements provoqués :

Des petites plaques friables vont se former cette nuit et demain en altitude. Elle peuvent reposer sur une couche de neige fraîche tombée au préalable sans vent faisant office de couche fragile temporaire. Ces plaques sont très sensibles, pouvant être déclenchées au passage d'un simple randonneur mais elles restent de faible épaisseur (10 à 20cm), risquant surtout de déstabiliser un randonneur.

Cette neige a souvent un aspect poudreux mais elle a pris suffisamment de cohésion pour propager les contraintes.

Observables : transport de la neige par le vent, se méfier des combes où l'o pourra localement observer des accumulation de neige fraîche supérieures à 20 cm..

Départs spontanés :

De rares petites coulées de surface peuvent se produire durant les chutes de neige de cette nuit, se poursuivant lundi. Il s'agit essentiellement de petites avalanches de taille 1 se déclenchant dans les pentes raides sans grande conséquence.

Qualité de la neige

Enneigement :

L'enneigement demeure excellent voire exceptionnel pour la saison, un des meilleurs des 30 dernières années. Les nouvelles chutes de neige blanchissent la montagne dès 1300 à 1400m mais les quantités sont trop faibles pour modifier la limite skiable. On chausse le plus souvent à partir de 1500/1600 m en nord, 1700/1800 m en sud sur une couche de neige rapidement très épaisse, dépassant les 2 m à 2000m d'altitude.

Qualité de la neige :

On trouve lundi une petite couche de neige fraîche agréable à skier reposant sur un fond souvent dur et regelé au dessus de 1800m. La tramontane attendue lundi risque de travailler rapidement cette neige avec des cols et crêtes en neige dure et quelques combes abritées gardant une neige poudreuse..

Aperçu météo pour le lundi 13 avril

Temps froid et neigeux le matin, éclaircies le soir

	nuit	matin	après-midi	soir
Pluie-Neige	1 700 m	1 200 m		
Iso 0 °C	2 100 m	2 000 m	2 200 m	2 000 m
Vent 2000 m	30 km/h	50 km/h	50 km/h	45 km/h
Vent 3000 m	35 km/h	65 km/h	65 km/h	75 km/h

Épaisseur de neige hors-piste

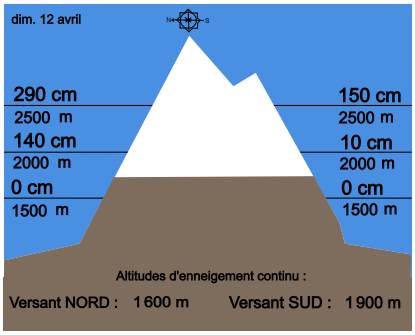

Précipitations à 1800 m

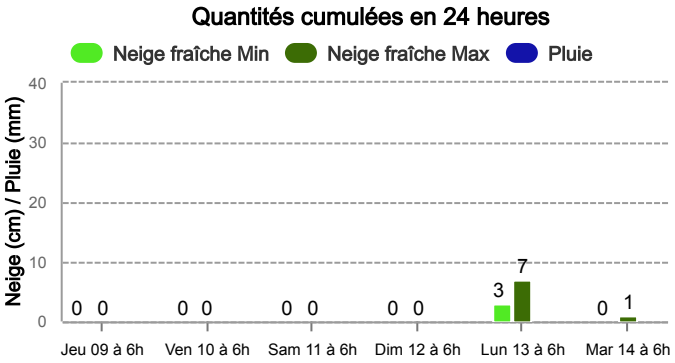

Tendance du mardi 14 avril

2

Indice de risque limité

Pas d'évolution significative.

Pour consulter la vigilance en cours, veuillez vous rendre sur le site https://vigilance.meteofrance.fr/fr

Météo-France - 73 avenue de Paris, 94165 Saint-Mandé cedex - Contact : contact@meteo.fr

Rédigé par Météo-France avec la contribution des observateurs du réseau nivo-météorologiques. Partenariat : ANMSM (Maires de Stations de Montagne), DSF (Domaines Skiables de France), ADSP (Directeurs de Pistes et de la Sécurité des Stations de Sports d'Hiver) et autres acteurs de la montagne.

Bulletin neige & avalanches par téléphone au

0 892 68 10 20 Service 0,35 € / min + prix appel

RÉPUBLIQUE FRANÇAISE
Liberté Égalité Fraternité

METEO FRANCE
À VOS CÔTÉS, DANS UN CLIMAT QUI CHANGE

Bulletin d'estimation du risque d'avalanche

(valable en dehors des pistes balisées et ouvertes)

MASSIF : Cerdagne Canigou

Rédigé le dimanche 12 avril 2026 à 16h

Conditions nivo-météo des 7 derniers jours

	lun. 06/04				mar. 07/04				mer. 08/04				jeu. 09/04				ven. 10/04				sam. 11/04				dim. 12/04			
	03h	09h	15h	21h	03h	09h	15h	21h	03h	09h	15h	21h	03h	09h	15h	21h	03h	09h	15h	21h	03h	09h	15h	21h	03h	09h	15h	21h
Météo																												
Vent (km/h)	15	20	35	30	30	25	20	20	30	35	35	25	25	25	25	25	30	20	25	25	30	30	45	45	40	30	30	20
à 3000m																												
Vent (km/h)	10	15	25	20	20	15	15	10	20	25	25	20	15	15	15	15	20	15	20	15	20	20	35	35	25	20	20	15
à 2000m																												

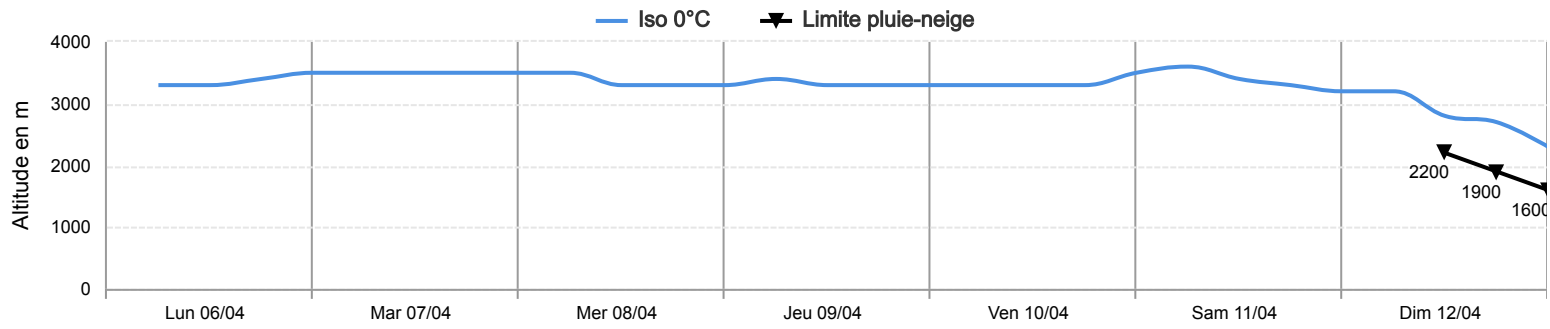

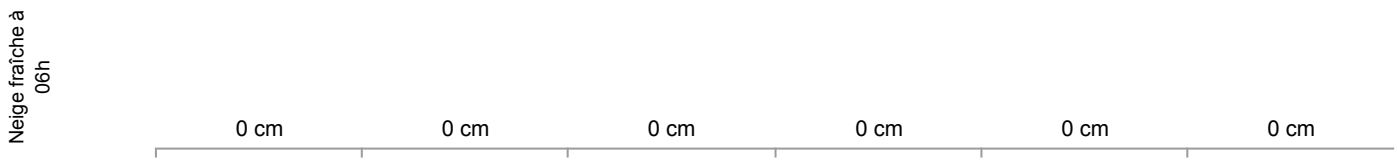

Risque d'avalanche	lun. 06/04	mar. 07/04	mer. 08/04	jeu. 09/04	ven. 10/04	sam. 11/04	dim. 12/04
	2	2	2	2	2	2	2

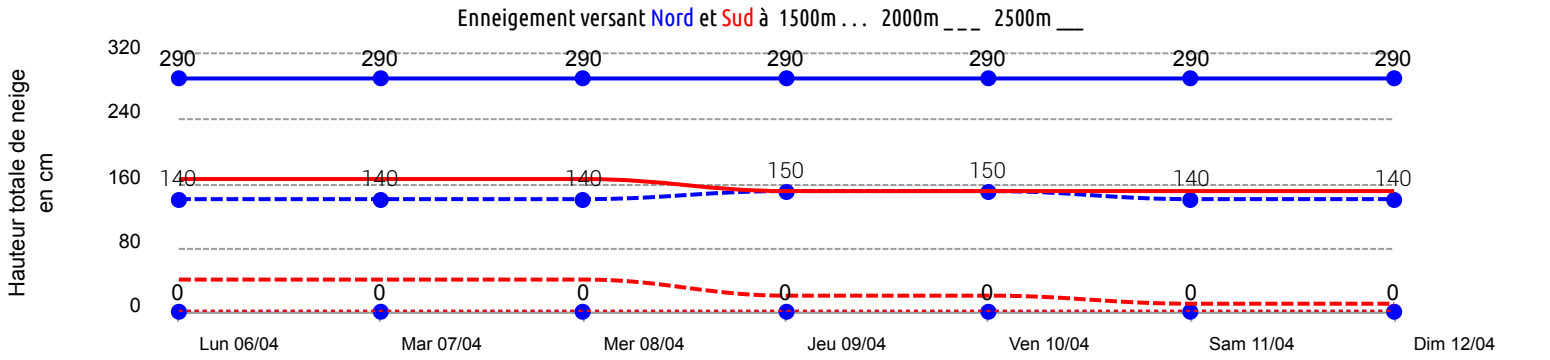

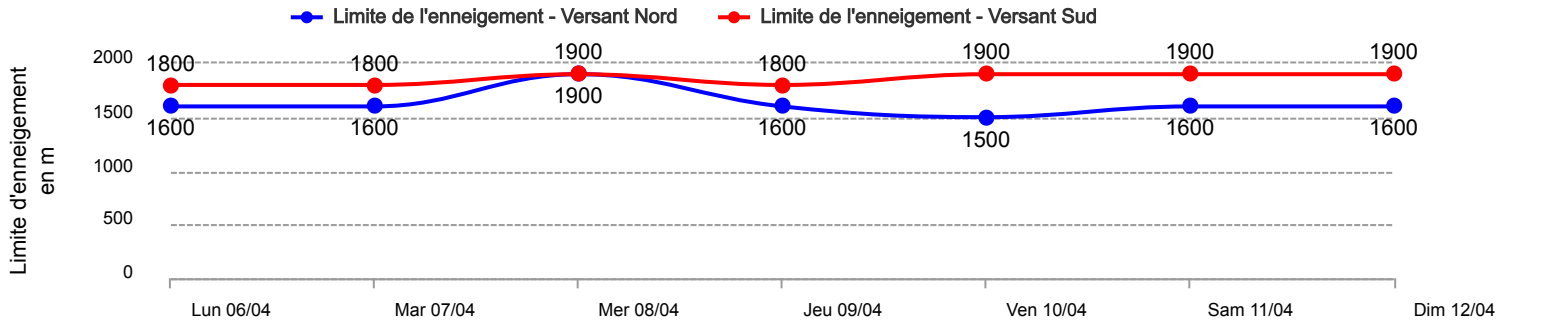

Pour consulter la vigilance en cours, veuillez vous rendre sur le site https://vigilance.meteofrance.fr/fr

Météo-France - 73 avenue de Paris, 94165 Saint-Mandé cedex - Contact : contact@meteo.fr

Rédigé par Météo-France avec la contribution des observateurs du réseau nivo-météorologiques. Partenariat : ANMSM (Maires de Stations de Montagne), DSF (Domaines Skiables de France), ADSP (Directeurs de Pistes et de la Sécurité des Stations de Sports d'Hiver) et autres acteurs de la montagne.

Bulletin neige & avalanches par téléphone au
0 892 68 10 20 Service 0,35 € / min + prix appel