RÉPUBLIQUE FRANÇAISE
Liberté Égalité Fraternité

METEO FRANCE
À VOS CÔTÉS, DANS UN CLIMAT QUI CHANGE

Bulletin d'estimation du risque d'avalanche
(valable en dehors des pistes balisées et ouvertes)

MASSIF : Devoluy

Rédigé le dimanche 12 avril 2026 à 16h

Estimation des risques pour le : LUNDI 13 AVRIL

MANTEAU NEIGEUX HUMIDE ET PLUTÔT STABLE

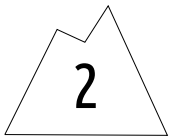

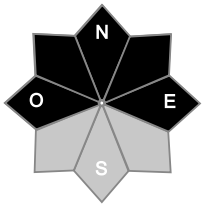

Indice de risque limité.

Départs spontanés : Résiduels en neige humide ou rare avalanche de glissement

Déclenchements provoqués : ponctuels dans la neige humide, parfois volumineux

Indices de risque : 5 très fort - 4 fort - 3 marqué - 2 limité - 1 faible -- En noir : les pentes les plus dangereuses

Stabilité du manteau neigeux

Situation avalancheuse typique : neige humide

Déclenchements provoqués : ponctuels dans la neige humide, mais pouvant mobiliser une grande partie du manteau neigeux en versant ouest, nord et est d'altitude, surtout au-dessus de 2200 m. Parfois déclenchables par un seul skieur, générant des avalanches de taille petite à moyenne.

Départs spontanés : en neige humide, en atténuation. Rares départs de taille moyenne encore possible en large versant nord, parfois sous forme d'avalanche de glissement, emportant tout le manteau neigeux.

Qualité de la neige

Enneigement encore excédentaire pour une mi-avril, notamment en ubacs et vallons d'altitude.

Limite d'enneigement skiable : vers 1400/1500 m en ubacs favorables (terrains herbeux, pistes forestières), 1900/2000 m en adrets pas trop raides.

État de la neige de surface : manteau neigeux humide regelant progressivement lundi avec le refroidissement de la masse d'air

Aperçu météo pour le lundi 13 avril

	nuit	matin	après-midi	soir
	Eclaircies dans une masse d'air plus frais l'après-midi			
Pluie-Neige	2 100 m			
Iso 0 °C	2 500 m	2 200 m	2 000 m	1 600 m
Vent 2000 m	30 km/h	25 km/h	25 km/h	40 km/h
Vent 3000 m	40 km/h	15 km/h	10 km/h	10 km/h

Épaisseur de neige hors-piste

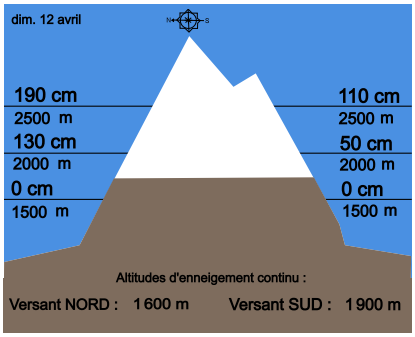

Précipitations à 1800 m

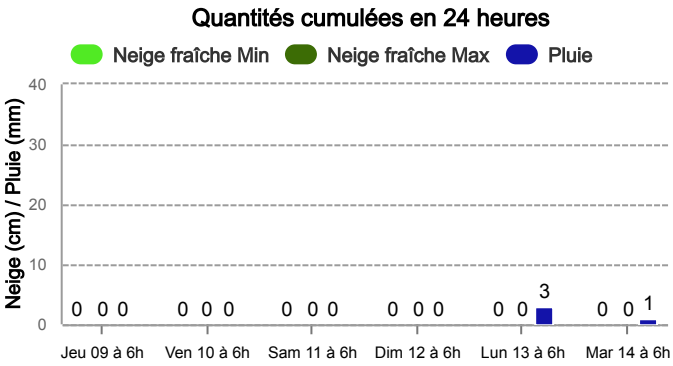

Tendance du mardi 14 avril

Indice de risque faible

Tendance à la baisse. Manteau neigeux bien stabilisé par le regel mardi matin. Risque faible

Pour consulter la vigilance en cours, veuillez vous rendre sur le site https://vigilance.meteofrance.fr/fr

Météo-France - 73 avenue de Paris, 94165 Saint-Mandé cedex - Contact : contact@meteo.fr

Rédigé par Météo-France avec la contribution des observateurs du réseau nivo-météorologiques. Partenariat : ANMSM (Maires de Stations de Montagne), DSF (Domaines Skiables de France), ADSP (Directeurs de Pistes et de la Sécurité des Stations de Sports d'Hiver) et autres acteurs de la montagne.

Bulletin neige & avalanches par téléphone au

0 892 68 10 20 Service 0,35 € / min + prix appel

Bulletin d'estimation du risque d'avalanche

(valable en dehors des pistes balisées et ouvertes)

MASSIF : Devoluy

Rédigé le dimanche 12 avril 2026 à 16h

Conditions nivo-météo des 7 derniers jours

	lun. 06/04				mar. 07/04				mer. 08/04				jeu. 09/04				ven. 10/04				sam. 11/04				dim. 12/04			
	03h	09h	15h	21h	03h	09h	15h	21h	03h	09h	15h	21h	03h	09h	15h	21h	03h	09h	15h	21h	03h	09h	15h	21h	03h	09h	15h	21h
Météo																												
Vent (km/h)	25	20	10	10	10	5	5	10	10	10	5	5	5	15	30	50	40	30	30	30	25	20	15	20	25	35	50	50
à 3000m																												
Vent (km/h)	10	10	15	10	5	10	15	5	5	5	10	5	10	15	25	35	35	30	30	15	10	10	20	15	15	15	20	30
à 2000m																												

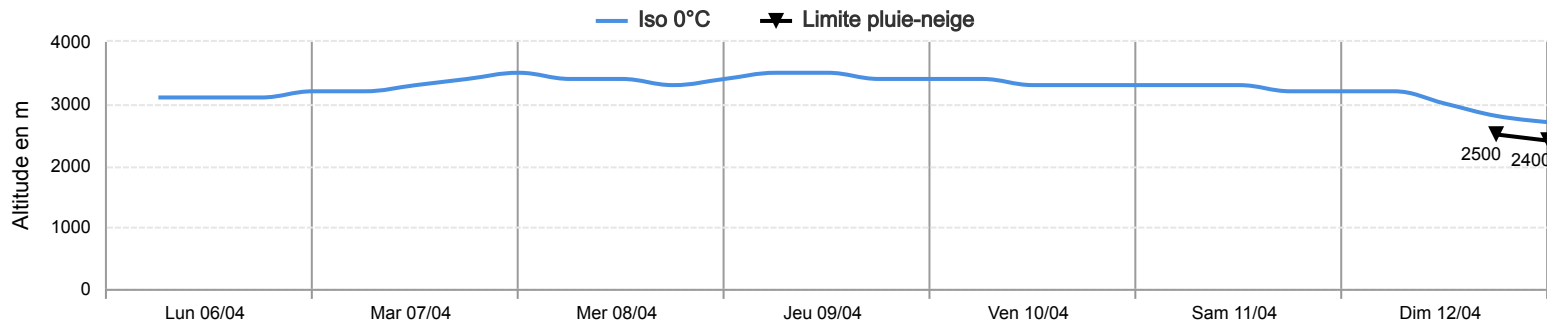

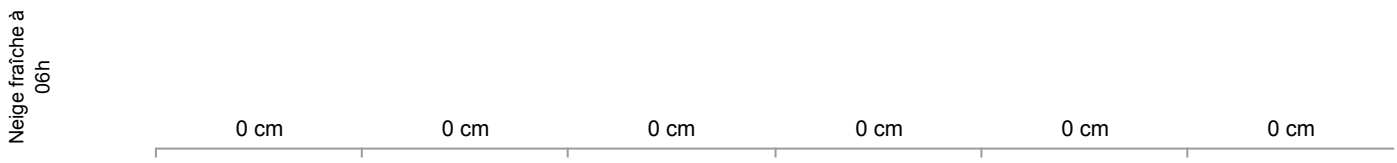

Risque d'avalanche	lun. 06/04	mar. 07/04	mer. 08/04	jeu. 09/04	ven. 10/04	sam. 11/04	dim. 12/04
	2	2	2	2	2	2	2

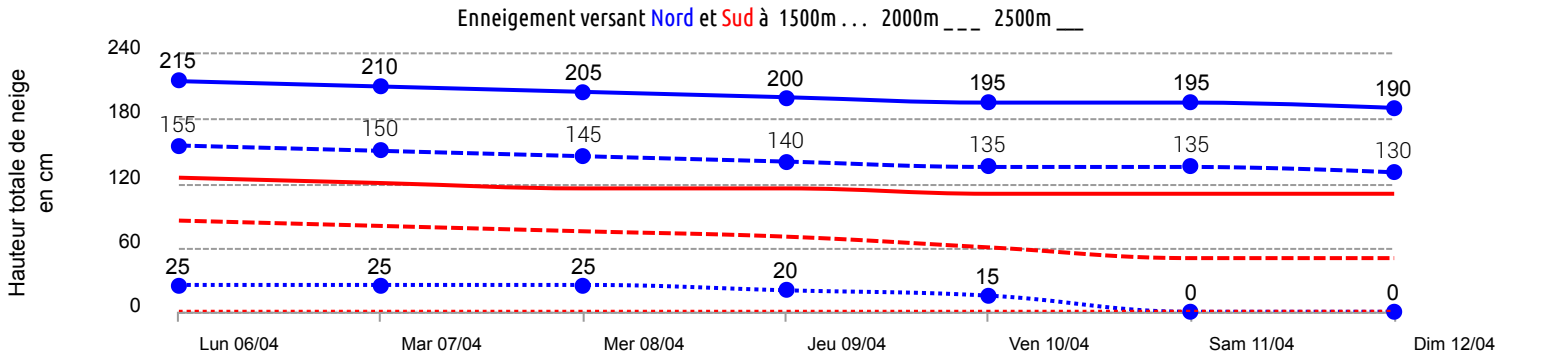

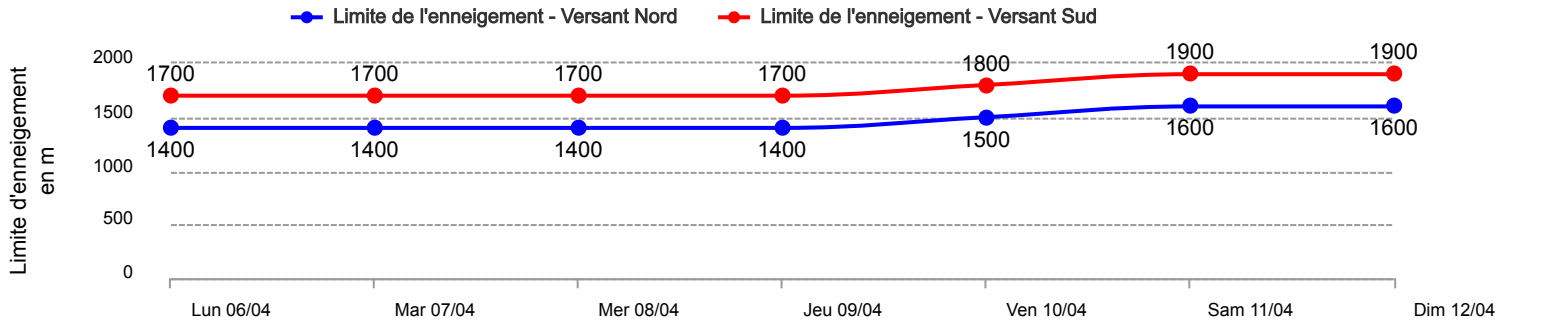

Pour consulter la vigilance en cours, veuillez vous rendre sur le site https://vigilance.meteofrance.fr/fr

Météo-France - 73 avenue de Paris, 94165 Saint-Mandé cedex - Contact : contact@meteo.fr

Bulletin neige & avalanches par téléphone au

0 892 68 10 20 Service 0,35 € / min + prix appel

Rédigé par Météo-France avec la contribution des observateurs du réseau nivo-météorologiques. Partenariat : ANMSM (Maires de Stations de Montagne), DSF (Domaines Skiables de France), ADSP (Directeurs de Pistes et de la Sécurité des Stations de Sports d'Hiver) et autres acteurs de la montagne.