Bulletin d'estimation du risque d'avalanche
(valable en dehors des pistes balisées et ouvertes)

MASSIF : Embrunais Parpaillon

Rédigé le dimanche 12 avril 2026 à 16h

Estimation des risques pour le : LUNDI 13 AVRIL

MANTEAU NEIGEUX HUMIDE ET PLUTÔT STABLE

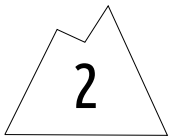

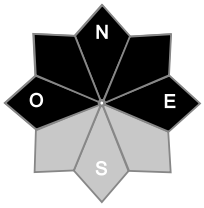

Indice de risque limité.

Départs spontanés : Résiduels en neige humide

Déclenchements provoqués : ponctuels dans la neige humide, parfois volumineux

Indices de risque : 5 très fort - 4 fort - 3 marqué - 2 limité - 1 faible -- En noir : les pentes les plus dangereuses

Stabilité du manteau neigeux

Situation avalancheuse typique : neige humide

Déclenchements provoqués : ponctuels dans la neige humide, mais pouvant mobiliser une grande partie du manteau neigeux en versant est, nord et ouest d'altitude, surtout au-dessus de 2200 m. Parfois déclenchables par un seul skieur, générant des avalanches de taille petite à moyenne.

Départs spontanés : en neige humide, en atténuation. Rares départs de taille moyenne encore possible en large versant nord

Qualité de la neige

Enneigement déficitaire pour un début avril, notamment en adrets, parfois secs jusqu'à 2500 m.
Hauteurs de neige observées vers 2500 m : 79 cm à la nivôse du Parpaillon à 2500 m.

Limite d'enneigement skiable : au plus bas à 1700/1800 m en ubacs bien protégés ou sur pistes forestières, plutôt 2200/2300 m en adrets.

État de la neige de surface : manteau neigeux humide, regel très limité à partir de 2700/2800 m.

Aperçu météo pour le lundi 13 avril

	nuit	matin	après-midi	soir
	Rares éclaircies, un peu plus frais			
Pluie-Neige			2 200 m	
Iso 0 °C	2 700 m	2 400 m	2 500 m	2 500 m
Vent 2000 m	← 20 km/h	← 20 km/h	← 20 km/h	↙ 20 km/h
Vent 3000 m	↖ 35 km/h	← 25 km/h	← 25 km/h	↙ 30 km/h

Épaisseur de neige hors-piste

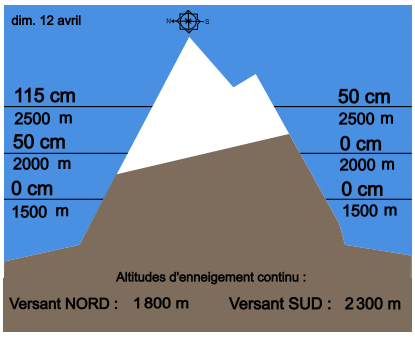

Précipitations à 1800 m

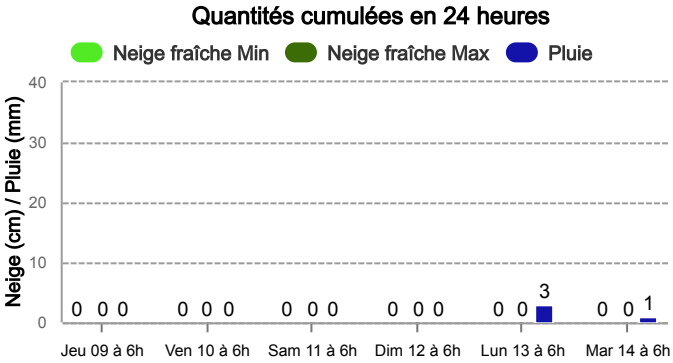

Tendance du mardi 14 avril

Indice de risque faible

Tendance à la baisse. Manteau neigeux bien stabilisé par le regel mardi matin. Risque faible

Pour consulter la vigilance en cours, veuillez vous rendre sur le site https://vigilance.meteofrance.fr/fr

Météo-France - 73 avenue de Paris, 94165 Saint-Mandé cedex - Contact : contact@meteo.fr

Rédigé par Météo-France avec la contribution des observateurs du réseau nivo-météorologiques. Partenariat : ANMSM (Maires de Stations de Montagne), DSF (Domaines Skiables de France), ADSP (Directeurs de Pistes et de la Sécurité des Stations de Sports d'Hiver) et autres acteurs de la montagne.

Bulletin neige & avalanches par téléphone au **0 892 68 10 20** Service 0,35 € / min + prix appel

Bulletin d'estimation du risque d'avalanche

(valable en dehors des pistes balisées et ouvertes)

MASSIF : Embrunais Parpaillon

Rédigé le dimanche 12 avril 2026 à 16h

Conditions nivo-météo des 7 derniers jours

	lun. 06/04				mar. 07/04				mer. 08/04				jeu. 09/04				ven. 10/04				sam. 11/04				dim. 12/04			
	03h	09h	15h	21h	03h	09h	15h	21h	03h	09h	15h	21h	03h	09h	15h	21h	03h	09h	15h	21h	03h	09h	15h	21h	03h	09h	15h	21h
Météo																												
Vent (km/h)	30	20	15	10	10	5	10	15	10	10	5	10	10	20	20	20	25	20	25	30	25	30	20	20	25	30	35	35
à 3000m																												
Vent (km/h)	10	10	20	10	10	5	20	10	5	10	15	10	10	5	20	15	15	10	20	10	10	10	20	10	10	10	15	15
à 2000m																												

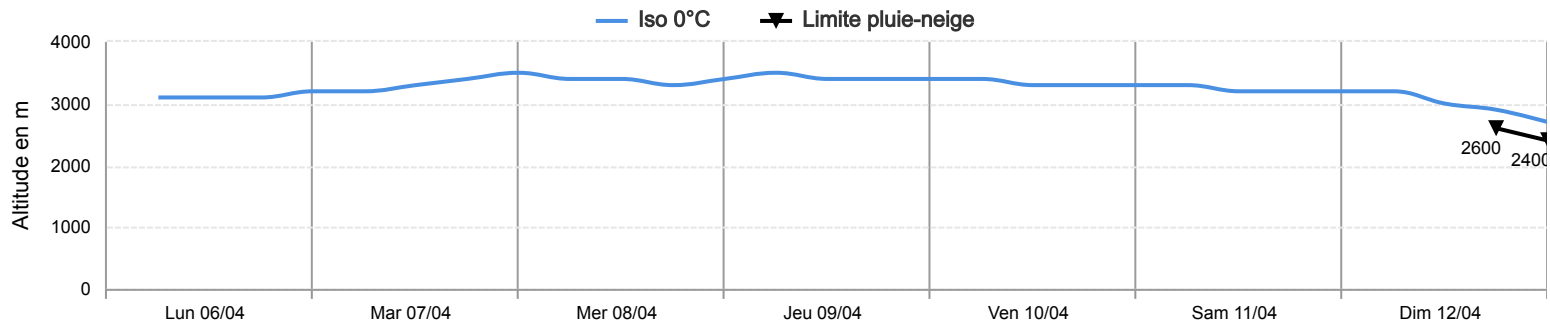

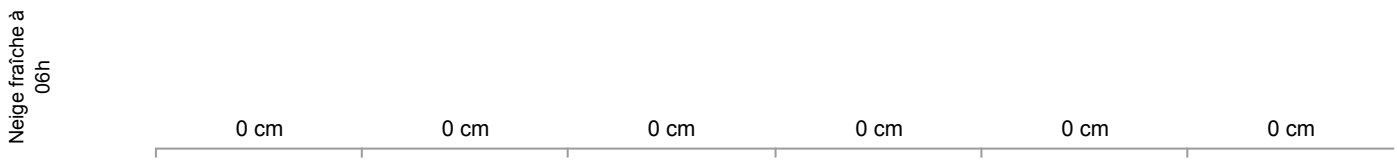

Risque d'avalanche	lun. 06/04	mar. 07/04	mer. 08/04	jeu. 09/04	ven. 10/04	sam. 11/04	dim. 12/04
	2	2	2	3	3	3	2

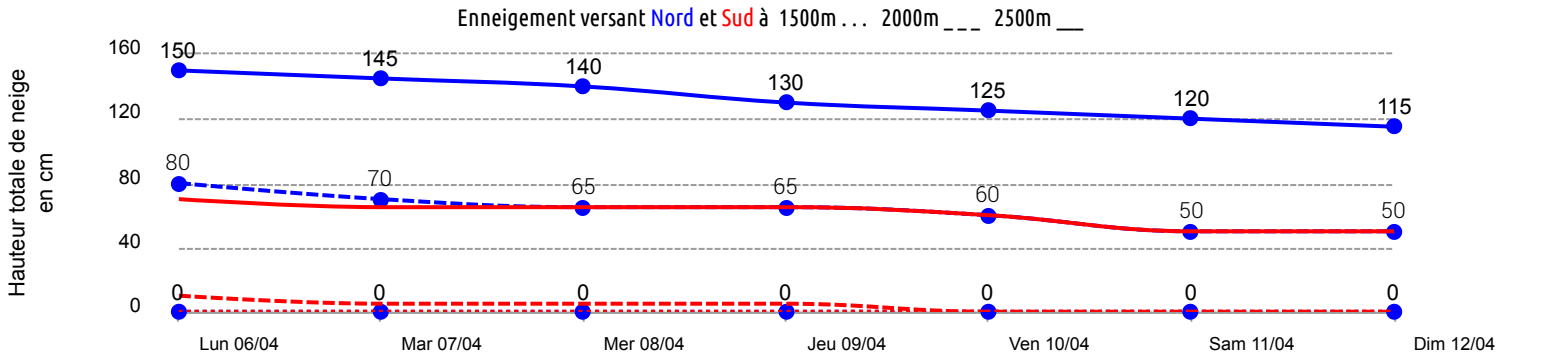

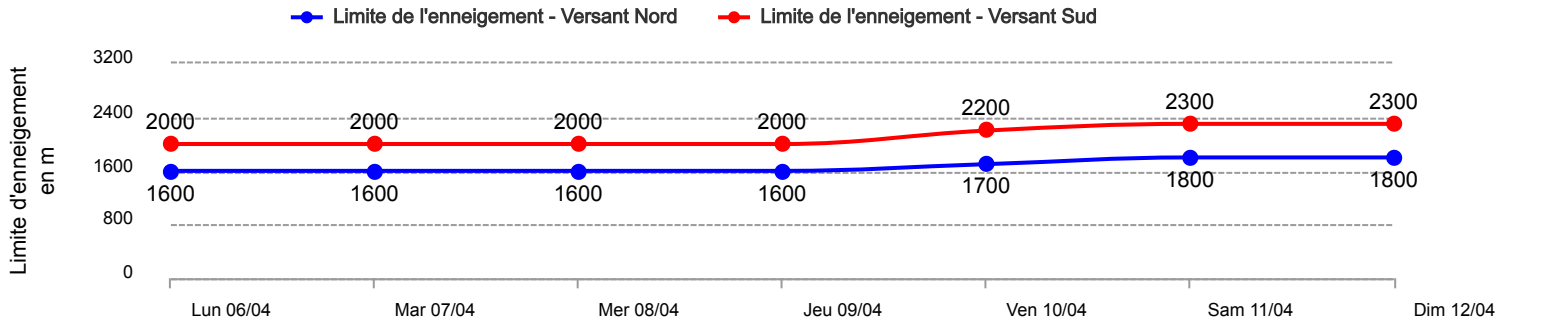

Pour consulter la vigilance en cours, veuillez vous rendre sur le site https://vigilance.meteofrance.fr/fr

Météo-France - 73 avenue de Paris, 94165 Saint-Mandé cedex - Contact : contact@meteo.fr

Rédigé par Météo-France avec la contribution des observateurs du réseau nivo-météorologiques. Partenariat : ANMSM (Maires de Stations de Montagne), DSF (Domaines Skiables de France), ADSP (Directeurs de Pistes et de la Sécurité des Stations de Sports d'Hiver) et autres acteurs de la montagne.

Bulletin neige & avalanches par téléphone au

0 892 68 10 20 Service 0,35 € / min + prix appel