Bulletin d'estimation du risque d'avalanche

(valable en dehors des pistes balisées et ouvertes)

MASSIF : Grandes-Rousses

Rédigé le dimanche 12 avril 2026 à 16h

Estimation des risques pour le : LUNDI 13 AVRIL

CIEL COUVERT, QUELQUES AVERSES DE NEIGE EN ALTITUDE, POURSUITE DE L'HUMIDIFICATION EN MOYENNE MONTAGNE

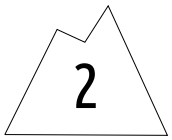

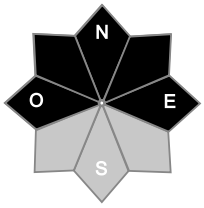

Indice de risque limité.

Départs spontanés : Avalanches humides et de glissement en pentes ensoleillées. Rares avalanches de grandes tailles possibles.

Déclenchements provoqués : En pente bien humide, coulée ponctuelle sous les skis. Rares plaques superficielles vers les Ecrins.

Indices de risque : 5 très fort - 4 fort - 3 marqué - 2 limité - 1 faible -- En noir : les pentes les plus dangereuses

Stabilité du manteau neigeux

Situation avalancheuse typique : neige humide avalanches de fond

Départs spontanés :

- Pas de regel nocturne sous 2300 / 2500m environ. Sous ces altitudes, des avalanches humides peuvent encore partir à toute heure, de tailles petites à moyennes. Au-dessus de 2300m, le risque diminue légèrement grâce au léger regel nocturne, mais reprends en journée. Les coulées sont moins fréquentes en secteurs Sud-Ouest à Sud-Est où l'humidification a déjà purgé la plupart des pentes la semaine dernière. En Nord-Est et Nord-Ouest en revanche, l'humidification gagne en profondeur et on ne peut exclure qu'elle atteigne localement des couches fragiles enfouies dans le manteau, auquel cas une avalanche plus conséquente est envisageable, avec un départ linéaire et/ou jusqu'au terrain.
- A toute heure (parfois même la nuit) et dans la plupart des versants hormis en plein Nord, des avalanches de glissement peuvent se produire. De tailles moyennes, voire rarement de grandes tailles. Surtout en alpage raide / sur les dalles rocheuses. Parfois précédées par l'ouverture d'une fissure (gueule de baleine).
- Une rupture spontanée de corniche est également possible l'après-midi et à surveiller dans les secteurs concernés.

Déclenchements provoqués :

- En pentes soutenues et bien humidifiées, le pratiquant pourrait faire couler la neige humide sous les skis. Très localement en large Nord-Ouest à Nord-Est d'altitude, le départ d'une coulée ponctuelle pourrait venir solliciter les couches fragiles persistantes et faire partir en cascade une plaque (de taille petite à moyenne, parfois grande).
- Très localement vers les Ecrins, surtout au-dessus de 3000m, des plaques superficielles et de largeur limitées peuvent se former dans les 10-20cm de neige récente.

Qualité de la neige

Qualification de l'enneigement : L'enneigement s'est fortement réduit la semaine dernière mais reste toujours bon dès la moyenne montagne peu ensoleillée, et dans les combes d'altitude... L'enneigement devient en revanche moins généreux aux basses altitudes et en versants bien ensoleillés.

Limites skiables : Vers 1400/1600m en plein Nord (hors sapins), 1800/1900m au soleil...

Qualité de la neige lundi : Regel inexistant sous 2300 / 2500m environ. Au-dessus, regel assez médiocre avec une croûte pas toujours portante. Au-dessus de 2200m environ on retrouve parfois une fine couche de neige récente tombée sous les averses dimanche soir, jusqu'à 15cm vers les Ecrins. En journée, forte humidification sous 3000m, parfois même plus haut dans le brouillard, la neige récente colle aux skis.

Aperçu météo pour le lundi 13 avril

	nuit	matin	après-midi	soir

Journée encore maussade, avec un temps très nuageux et du brouillard de pente. Quelques averses en journée, donnant un peu de neige au-dessus de 1900 / 2000m.

	nuit	matin	après-midi	soir
Pluie-Neige	2 100 m	2 000 m	2 100 m	2 000 m
Iso 0 °C	2 500 m	2 400 m	2 400 m	2 300 m
Vent 2000 m	↖ 20 km/h	↖ 15 km/h	↙ 15 km/h	↙ 10 km/h
Vent 3000 m	↖ 35 km/h	↖ 25 km/h	← 20 km/h	↙ 20 km/h

Épaisseur de neige hors-piste

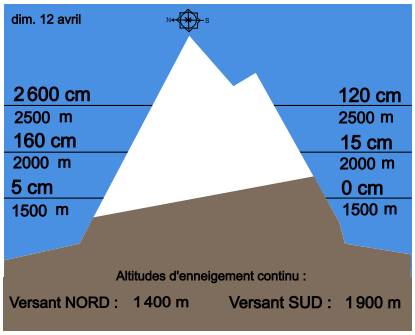

Précipitations à 1800 m

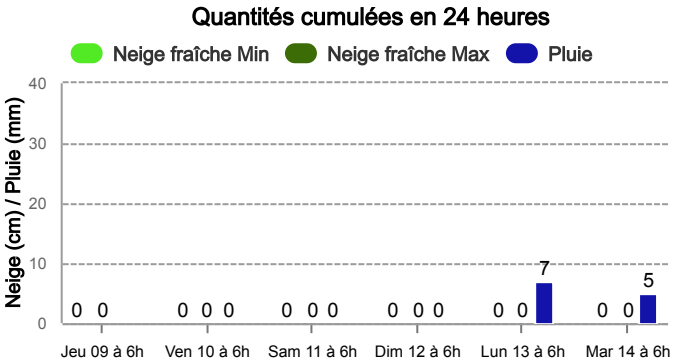

Tendance du mardi 14 avril

Indice de risque limité

Mardi, mer de nuage sous 2500 / 3000m en matinée. En journée, les nuages gonflent et donnent quelques averses. Le manteau reste très humide, avec toujours quelques coulées.

Pour consulter la vigilance en cours, veuillez vous rendre sur le site https://vigilance.meteofrance.fr/fr

Météo-France - 73 avenue de Paris, 94165 Saint-Mandé cedex - Contact : contact@meteo.fr

Rédigé par Météo-France avec la contribution des observateurs du réseau nivo-météorologiques. Partenariat : ANMSM (Maires de Stations de Montagne), DSF (Domaines Skiables de France), ADSP (Directeurs de Pistes et de la Sécurité des Stations de Sports d'Hiver) et autres acteurs de la montagne.

Bulletin neige & avalanches par téléphone au

0 892 68 10 20 Service 0,35 € / min + prix appel

RÉPUBLIQUE FRANÇAISE
Liberté Égalité Fraternité

METEO FRANCE
À VOS CÔTÉS, DANS UN CLIMAT QUI CHANGE

Bulletin d'estimation du risque d'avalanche

(valable en dehors des pistes balisées et ouvertes)

MASSIF : Grandes-Rousses

Rédigé le dimanche 12 avril 2026 à 16h

Conditions nivo-météo des 7 derniers jours

	lun. 06/04				mar. 07/04				mer. 08/04				jeu. 09/04				ven. 10/04				sam. 11/04				dim. 12/04			
	03h	09h	15h	21h	03h	09h	15h	21h	03h	09h	15h	21h	03h	09h	15h	21h	03h	09h	15h	21h	03h	09h	15h	21h	03h	09h	15h	21h
Météo																												
Vent (km/h)	25	20	15	5	10	0	5	10	15	5	5	5	10	20	20	30	35	25	25	20	20	20	25	20	25	25	25	25
à 3000m																												
Vent (km/h)	10	10	10	0	5	0	5	5	10	0	0	5	5	10	20	25	20	20	10	0	10	10	15	10	10	15	20	15
à 2000m																												

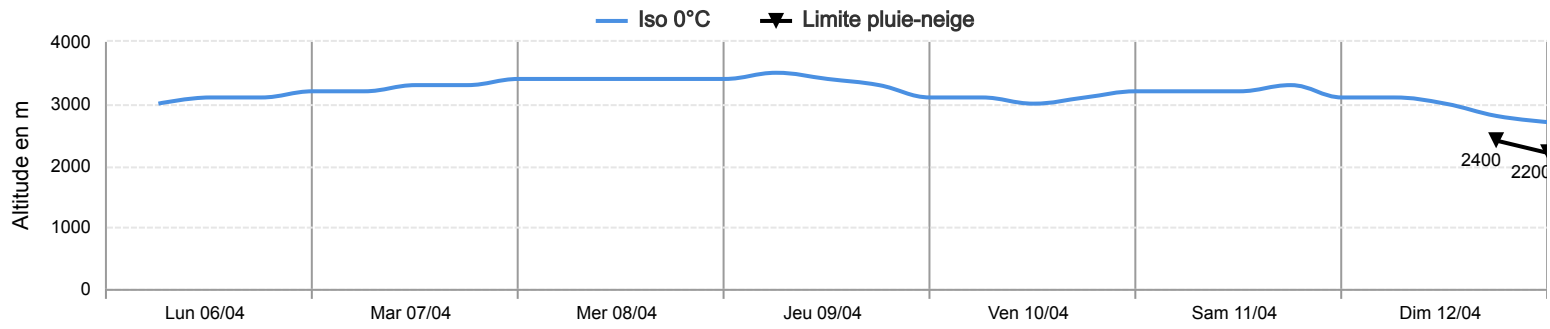

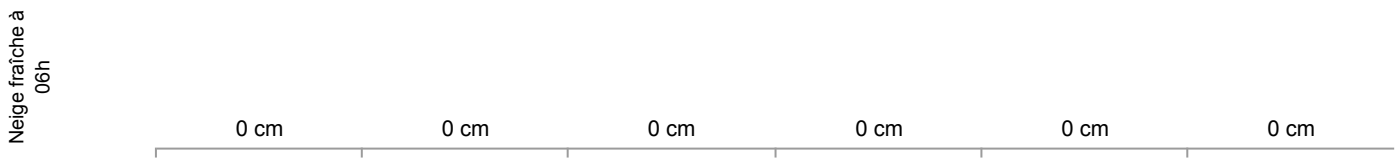

Risque d'avalanche	lun. 06/04	mar. 07/04	mer. 08/04	jeu. 09/04	ven. 10/04	sam. 11/04	dim. 12/04
	2	2	2	2	2	2	2

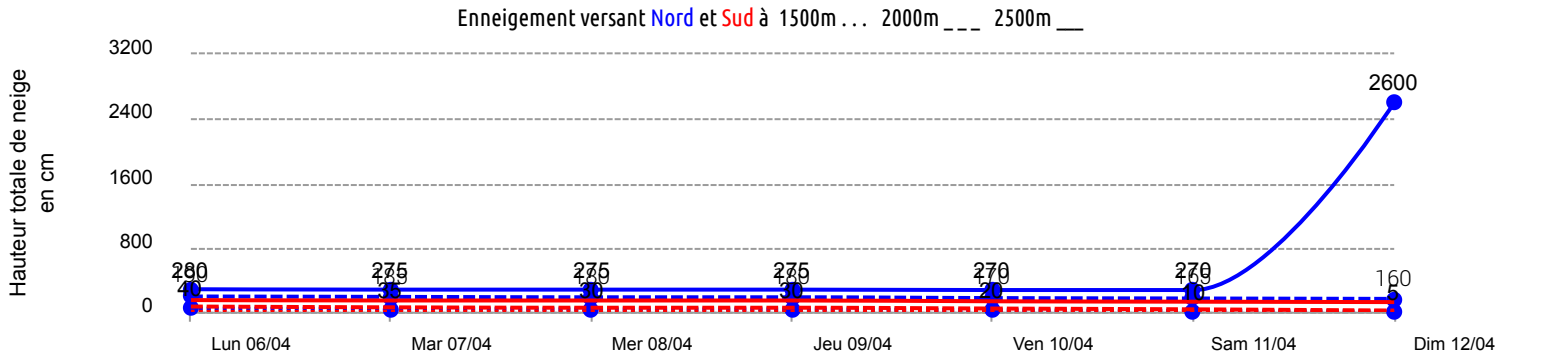

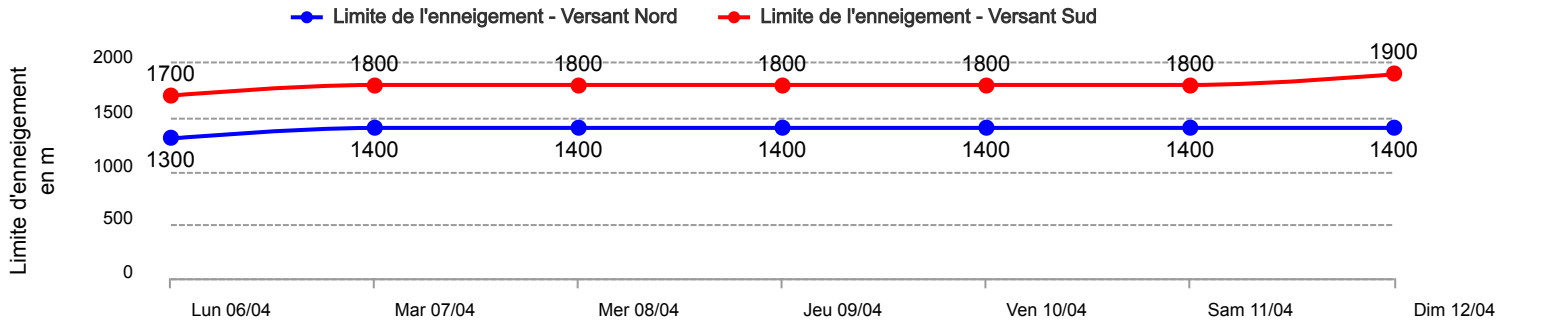

Pour consulter la vigilance en cours, veuillez vous rendre sur le site https://vigilance.meteofrance.fr/fr

Météo-France - 73 avenue de Paris, 94165 Saint-Mandé cedex - Contact : contact@meteo.fr

Bulletin neige & avalanches par téléphone au

0 892 68 10 20 Service 0,35 € / min + prix appel

Rédigé par Météo-France avec la contribution des observateurs du réseau nivo-météorologiques. Partenariat : ANMSM (Maires de Stations de Montagne), DSF (Domaines Skiables de France), ADSP (Directeurs de Pistes et de la Sécurité des Stations de Sports d'Hiver) et autres acteurs de la montagne.