Bulletin d'estimation du risque d'avalanche
(valable en dehors des pistes balisées et ouvertes)

MASSIF : Haut-Var Haut-Verdon

Rédigé le dimanche 12 avril 2026 à 16h

Estimation des risques pour le : LUNDI 13 AVRIL

NOUVELLES PLAQUES EN FORMATION AU DESSUS DE 2500 M, MANTEAU NEIGEUX RESTANT BIEN HUMIDE EN DESSOUS

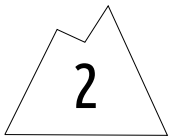

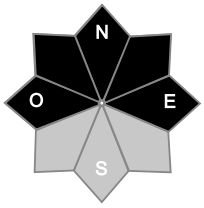

Indice de risque limité.

Départs spontanés : en neige humide en moyenne montagne, de neige fraîche au dessus de 2500 m

Déclenchements provoqués : plaques à vent en formation au dessus de 2500 m

Indices de risque : 5 très fort - 4 fort - 3 marqué - 2 limité - 1 faible -- En noir : les pentes les plus dangereuses

Stabilité du manteau neigeux

Situation avalancheuse typique : neige humide neige ventée

Déclenchements provoqués : plaques en formations au dessus de 2500 m environ, avec les chutes ventées. Sous l'action d'un vent d'est modéré, ces instabilité sont possibles dans toutes les orientations mais plus nombreuses en ouest, nord et est. Plaques d'épaisseur limitée mais facilement déclenchables, pouvant engendrer des avalanches petites à moyennes (taille 1 à 2).
Sous 2300/2500 m, le pratiquant peut déclencher sous les skis une avalanche dans la neige humide / pourrie dans les pentes raides. Taille moyenne en général.

Départs spontanés : sous 2200/2400 m, des avalanches de neige humide peuvent encore se produire à tout moment, en particulier en versant nord, favorisées par les pluies sous 2000/2200 m et par l'eau qui continue de percoler dans le manteau neigeux. Avalanches le plus souvent de taille moyenne (taille 2). Au dessus de 2500 m, des petits départs de neige sèche ventée sont possibles en pentes raides pendant les chutes.

Qualité de la neige

Enneigement encore légèrement excédentaire pour la saison.
Hauteurs de neige observées : vers 2000 m, 126 cm dans le vallon de Valdemars et , 58 cm à la Sanguinière dans le Haut-Var.

Enneigement skiable généralement à partir de 1800 m en terrain favorable et 2200 m en adrets peu pentus.

État de la neige en surface : sous 2300/2500 m, manteau neigeux bien humide dans toutes les orientations. On retrouve 5/10 cm de neige fraîche au dessus de 2500 m, souvent travaillée par le vent d'Est.

Aperçu météo pour le lundi 13 avril

	nuit	matin	après-midi	soir

Temps plus frais et faiblement perturbé. 5/10 cm possibles au dessus de 2200 m

Pluie-Neige	2 000 m	2 000 m	2 200 m	
Iso 0 °C	2 300 m	2 300 m	2 500 m	2 600 m
Vent 2000 m	← 35 km/h	↙ 25 km/h	↓ 25 km/h	↓ 25 km/h
Vent 3000 m	← 50 km/h	← 40 km/h	↓ 30 km/h	↙ 30 km/h

Épaisseur de neige hors-piste

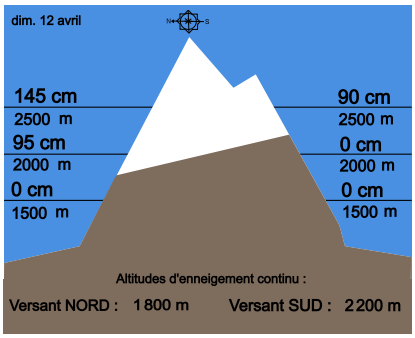

Précipitations à 1800 m

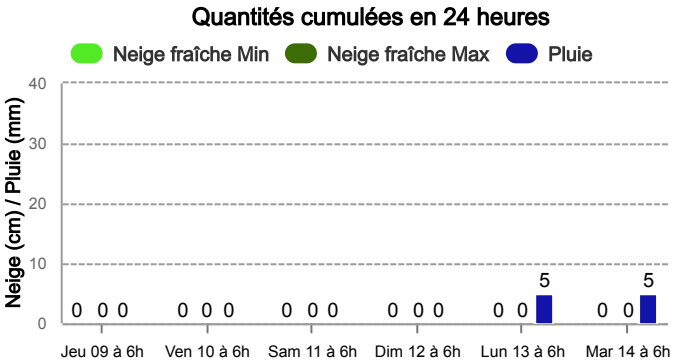

Tendance du mardi 14 avril

Indice de risque limité

Risque restant limité avec la reprise de l'activité naturelle à la faveur de belles éclaircies. Les quelques averses n'ont pas d'impact sur le manteau neigeux.

Pour consulter la vigilance en cours, veuillez vous rendre sur le site https://vigilance.meteofrance.fr/fr

Météo-France - 73 avenue de Paris, 94165 Saint-Mandé cedex - Contact : contact@meteo.fr

Rédigé par Météo-France avec la contribution des observateurs du réseau nivo-météorologiques. Partenariat : ANMSM (Maires de Stations de Montagne), DSF (Domaines Skiables de France), ADSP (Directeurs de Pistes et de la Sécurité des Stations de Sports d'Hiver) et autres acteurs de la montagne.

Bulletin neige & avalanches par téléphone au
0 892 68 10 20 Service 0,35 € / min + prix appel

Bulletin d'estimation du risque d'avalanche

(valable en dehors des pistes balisées et ouvertes)

MASSIF : Haut-Var Haut-Verdon

Rédigé le dimanche 12 avril 2026 à 16h

Conditions nivo-météo des 7 derniers jours

	lun. 06/04				mar. 07/04				mer. 08/04				jeu. 09/04				ven. 10/04				sam. 11/04				dim. 12/04			
	03h	09h	15h	21h	03h	09h	15h	21h	03h	09h	15h	21h	03h	09h	15h	21h	03h	09h	15h	21h	03h	09h	15h	21h	03h	09h	15h	21h
Météo																												
Vent (km/h)	30	25	20	20	20	15	15	15	10	10	15	15	15	15	25	35	40	20	30	25	25	25	30	15	15	20	30	50
à 3000m																												
Vent (km/h)	15	15	20	10	10	10	15	10	5	10	15	10	5	10	20	20	20	15	25	15	20	15	20	10	10	15	25	35
à 2000m																												

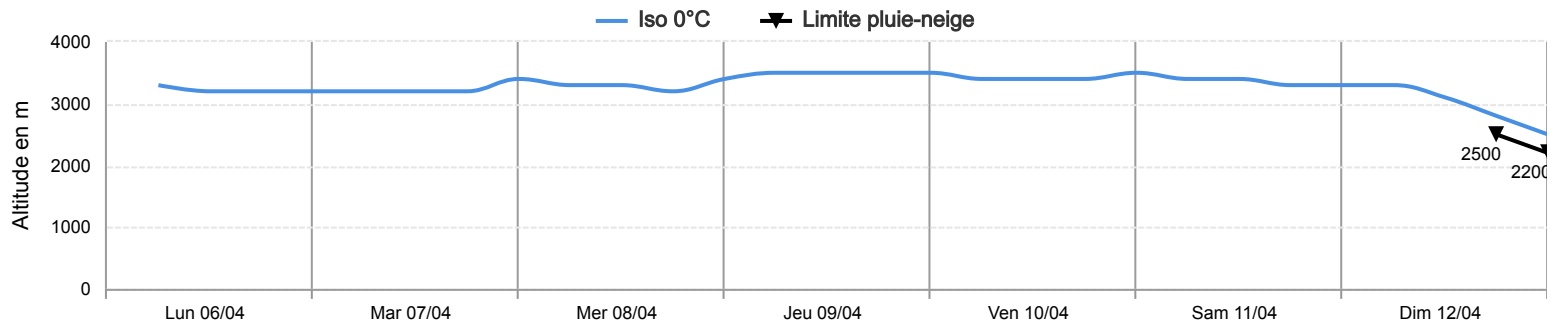

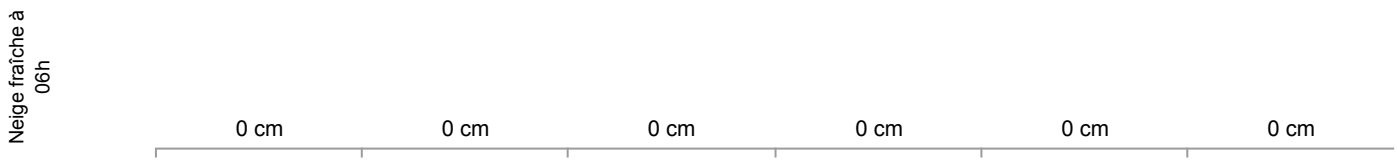

Risque d'avalanche	lun. 06/04	mar. 07/04	mer. 08/04	jeu. 09/04	ven. 10/04	sam. 11/04	dim. 12/04
	2	2	2	3	3	3	2

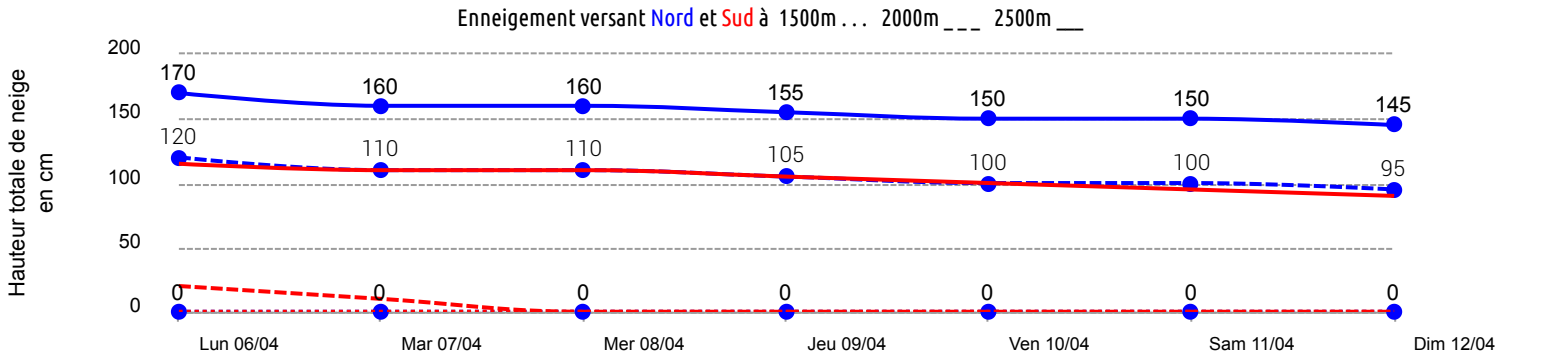

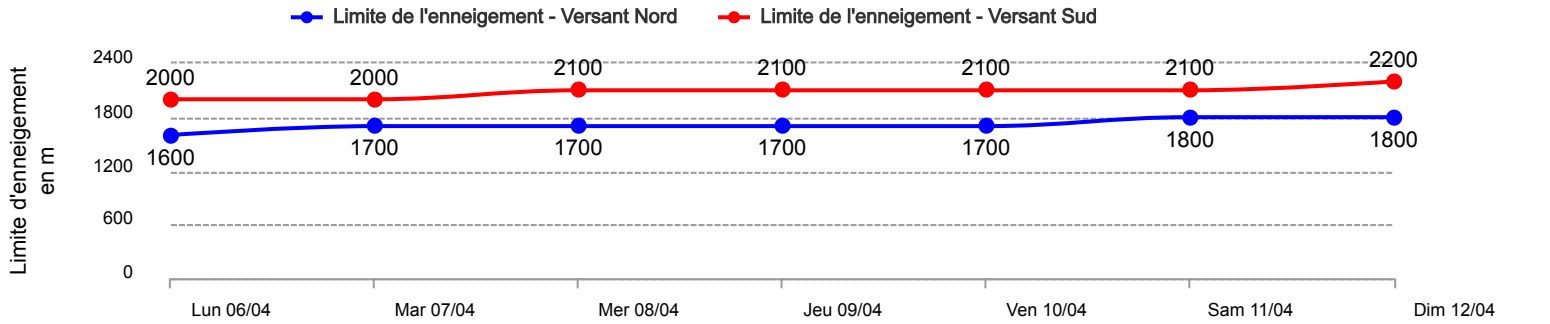

Pour consulter la vigilance en cours, veuillez vous rendre sur le site https://vigilance.meteofrance.fr/fr

Météo-France - 73 avenue de Paris, 94165 Saint-Mandé cedex - Contact : contact@meteo.fr

Bulletin neige & avalanches par téléphone au

0 892 68 10 20 Service 0,35 € / min + prix appel

Rédigé par Météo-France avec la contribution des observateurs du réseau nivo-météorologiques. Partenariat : ANMSM (Maires de Stations de Montagne), DSF (Domaines Skiables de France), ADSP (Directeurs de Pistes et de la Sécurité des Stations de Sports d'Hiver) et autres acteurs de la montagne.