Bulletin d'estimation du risque d'avalanche
(valable en dehors des pistes balisées et ouvertes)

MASSIF : Haute-Ariege

Rédigé le dimanche 12 avril 2026 à 16h

Estimation des risques pour le : LUNDI 13 AVRIL

NOUVELLES CHUTES DE NEIGE VENTÉES, NOUVELLES INSTABILITÉS.

3

2→3

N O E S

Indice de risque limité évoluant en marqué.

Départs spontanés : Quelques coulées de surface dans les pentes raides pendant les chutes en altitude.

Déclenchements provoqués : Nouvelles plaques en formation s'épaississant au fil de la journée.

Indices de risque : 5 très fort - 4 fort - 3 marqué - 2 limité - 1 faible -- En noir : les pentes les plus dangereuses

Stabilité du manteau neigeux

Situation avalancheuse typique : neige fraîche — neige ventée

Déclenchements provoqués : Evolution d'un risque limité à un risque marqué.
De nombreuses plaques friables vont se former cette nuit et prendre de l'épaisseur en journée avec le renforcement du vent de Nord-Ouest. Elle peuvent reposer sur une couche de neige fraîche tombée au préalable sans vent faisant office de couche fragile temporaire. Ces plaques sont très sensibles, pouvant être déclenchées au passage d'un simple randonneur. Elle sont de faible épaisseur lundi matin (10 à 20cm) mais elles pourront se multiplier et atteindre 30 à 40cm suivant le transport par le vent en journée.
Cette neige a souvent un aspect poudreux mais elle a pris suffisamment de cohésion pour propager les contraintes ; un déclenchement à distance peut aussi se produire.
Observables : transport de la neige par le vent, disparition des traces de montée, fissures devant les skis.

Départs spontanés :
De nombreuses petites coulées de surface peuvent se produire durant les chutes de neige de cette nuit, se poursuivant lundi. Il s'agit essentiellement de petites avalanches de taille 1 se déclenchant dans les pentes raides sans grande conséquence.
Observables : Cumuls de neige fraîche dépassant les 20 à 30cm.

Qualité de la neige

Enneigement :
L'enneigement demeure excellent pour la saison, un des meilleurs des 30 dernières années. Les nouvelles chutes de neige blanchissent à nouveau la montagne dès 1200 à 1300m d'altitude lundi mais il faut en général atteindre 1400 à 1500m pour trouver une sous couche versant Nord et 1800m versant Sud. cette couche augmente très vite en prenant de l'altitude avec des cumuls dépassant les 2m dès 1800 à 1900m, 3 à 4 m vers 2500m.

Qualité de la neige :
Lundi matin, on trouve une couche de neige fraîche, souvent fine et humide entre 1100 et 1500m puis prenant de l'épaisseur avec l'altitude. Elle est froide et poudreuse au dessus de 1800m dans les combes abritées du vent mais devient travaillée par le vent de Nord-Ouest durant la journée de lundi. Quelques cols et crêtes risquent de rester en neige très dure voire en glace à haute altitude.

Aperçu météo pour le lundi 13 avril

	nuit	matin	après-midi	soir
Temps hivernal				
Pluie-Neige	1 000 m	1 100 m	1 400 m	1 300 m
Iso 0 °C	1 500 m	1 400 m	1 900 m	1 600 m
Vent 2000 m	↓ 15 km/h	↓ 30 km/h	↻ 30 km/h	↓ 30 km/h
Vent 3000 m	↓ 45 km/h	↓ 50 km/h	↓ 45 km/h	↓ 50 km/h

Épaisseur de neige hors-piste

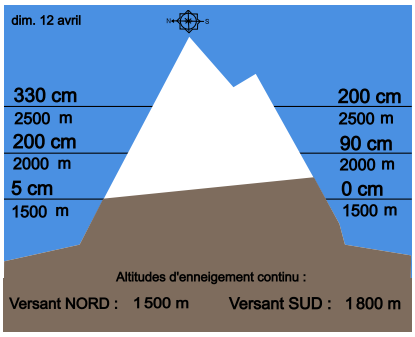

Précipitations à 1800 m

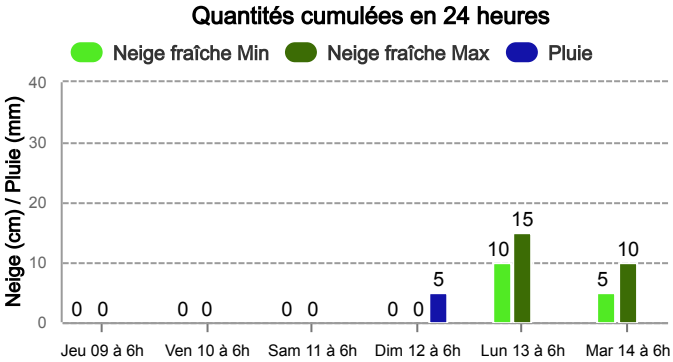

Tendance du mardi 14 avril

3

Indice de risque marqué

Maintient d'un risque marqué dans la neige récente.

Pour consulter la vigilance en cours, veuillez vous rendre sur le site https://vigilance.meteofrance.fr/fr

Météo-France - 73 avenue de Paris, 94165 Saint-Mandé cedex - Contact : contact@meteo.fr

Rédigé par Météo-France avec la contribution des observateurs du réseau nivo-météorologiques. Partenariat : ANMSM (Maires de Stations de Montagne), DSF (Domaines Skiables de France), ADSP (Directeurs de Pistes et de la Sécurité des Stations de Sports d'Hiver) et autres acteurs de la montagne.

Bulletin neige & avalanches par téléphone au 0 892 68 10 20 Service 0,35 € / min + prix appel

RÉPUBLIQUE FRANÇAISE
Liberté Égalité Fraternité

METEO FRANCE
À VOS CÔTÉS, DANS UN CLIMAT QUI CHANGE

Bulletin d'estimation du risque d'avalanche
(valable en dehors des pistes balisées et ouvertes)

MASSIF : Haute-Ariege

Rédigé le dimanche 12 avril 2026 à 16h

Conditions nivo-météo des 7 derniers jours

	lun. 06/04				mar. 07/04				mer. 08/04				jeu. 09/04				ven. 10/04				sam. 11/04				dim. 12/04			
	03h	09h	15h	21h	03h	09h	15h	21h	03h	09h	15h	21h	03h	09h	15h	21h	03h	09h	15h	21h	03h	09h	15h	21h	03h	09h	15h	21h
Météo																												
Vent (km/h)	15	20	35	30	30	25	20	20	30	35	35	25	20	20	20	20	20	20	20	30	30	35	45	45	45	30	25	20
à 3000m																												
Vent (km/h)	10	15	25	20	20	15	15	10	20	20	20	15	10	10	10	10	10	10	10	20	20	25	35	35	15	15	15	15
à 2000m																												

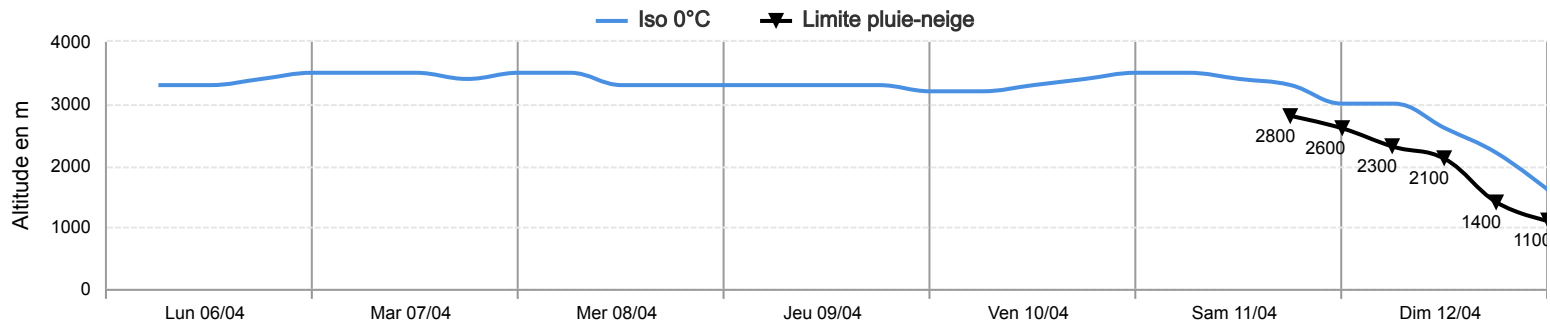

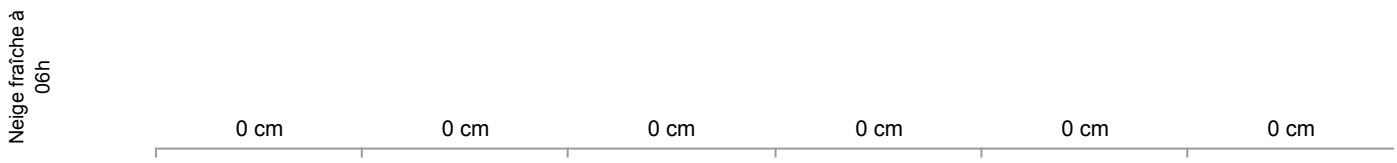

Risque d'avalanche	lun. 06/04	mar. 07/04	mer. 08/04	jeu. 09/04	ven. 10/04	sam. 11/04	dim. 12/04
	2	2	2	2	2	3	2

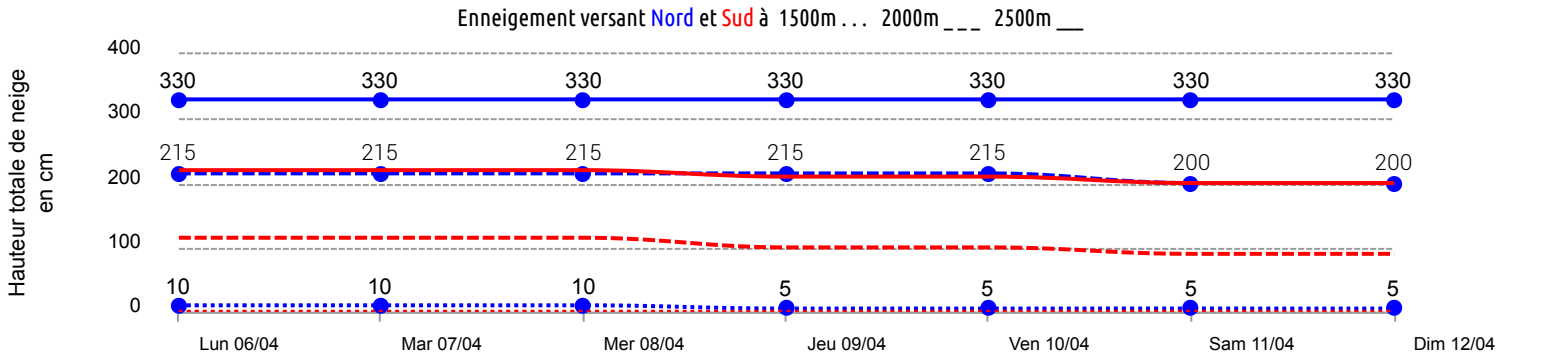

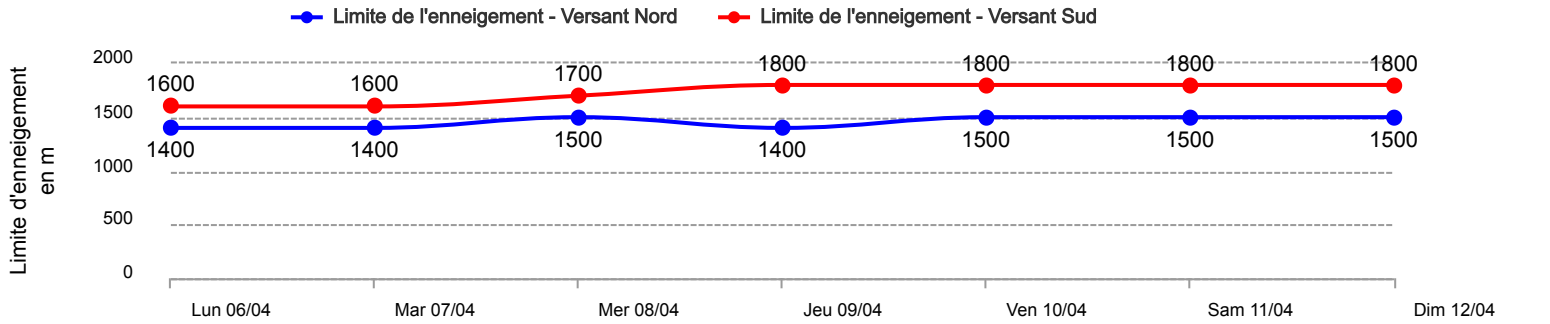

Pour consulter la vigilance en cours, veuillez vous rendre sur le site https://vigilance.meteofrance.fr/fr

Météo-France - 73 avenue de Paris, 94165 Saint-Mandé cedex - Contact : contact@meteo.fr

Bulletin neige & avalanches par téléphone au
0 892 68 10 20 Service 0,35 € / min + prix appel

Rédigé par Météo-France avec la contribution des observateurs du réseau nivo-météorologiques. Partenariat : ANMSM (Maires de Stations de Montagne), DSF (Domaines Skiables de France), ADSP (Directeurs de Pistes et de la Sécurité des Stations de Sports d'Hiver) et autres acteurs de la montagne.