RÉPUBLIQUE FRANÇAISE
Liberté Égalité Fraternité

METEO FRANCE
À VOS CÔTÉS, DANS UN CLIMAT QUI CHANGE

Bulletin d'estimation du risque d'avalanche

(valable en dehors des pistes balisées et ouvertes)

MASSIF : Mont-Blanc

Rédigé le dimanche 12 avril 2026 à 16h

Estimation des risques pour le : LUNDI 13 AVRIL

MANTEAU NEIGEUX HUMIDE SOUS 3000 M, FROID ET VENTÉE AU-DESSUS DE 3000 M

2

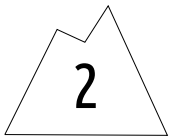

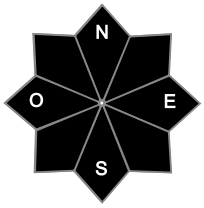

Indice de risque limité.

Départs spontanés : Avalanches en neige humide.

Déclenchements provoqués : plaques en neige fraiche au-dessus de 3000 m.

Indices de risque : 5 très fort - 4 fort - 3 marqué - 2 limité - 1 faible -- En noir : les pentes les plus dangereuses

Stabilité du manteau neigeux

Situation avalancheuse typique : neige ventée neige humide

Déclenchements provoqués :
* Au-dessus de 2400 m et surtout **au-dessus de 3000 m** : **plaques friables dans la neige fraiche**. Surtout présente au-dessus de 2800/3000 m et **plus épaisse proche de la frontière Italienne**. **Facile à déclencher**, ces plaques **s'épaississent au fil des chutes de neige**. Taille 1 à 2 (petite à moyenne)
* En dessous de 2400 m et surtout sous 2000 m : de la neige humide peut couler sous les skis. Ces avalanches concernent toutes les orientations et toutes altitudes. Au-delà de 2000m en ubacs, le skieur peut également déclencher une plaque humide de 30/40 cm d'épaisseur.

Départs spontanés :
* **Avalanches de neige humide** sur tous les versants jusqu'à 2300/2500 m sur tous sur les versants. Taille 1 à 2 (petite à moyenne).
Facteur aggravant : au-dessus de 1800 m, départ en cascade possible sur un secteur Est à Nord Ouest sur de la couche fragile persistante enfouie sous environ 1m/1m20 de neige. Taille 2 à 3 (moyenne à grande)
* Entre 2000 et 2400 m, des avalanches de plaques humides peuvent aussi partir spontanément lors de l'humidification d'une couche fragile enfouie sous 30/40 cm de neige. Taille 1 à 2.
* Au-dessus de 2800/3000 m : avalanches ponctuelles de neige fraiche sous les averses de neige. Plus probable et large proche de la frontière Italienne. Taille 1 (petite)
* En dessous de 2500 m : des avalanches de fond sont possibles à toute heure du jour et de la nuit, sur les pentes herbeuses ou les dalles rocheuses. Taille 2.

Autres :
* En dessous de 2400 m : chutes de corniche possible au vu de l'humidification des versants nord d'altitude et de l'absence de regel nocturne.

Qualité de la neige

Enneigement :
L'enneigement est correct au-dessus de 2700m. En dessous, il commence à être déficitaire.
On peut chausser les skis au-dessus de 1700/1800 m en sud et 1400/1500 m en nord. Des traces de neige sont présentes sous ces altitudes, mais l'enneigement est loin d'être continu.

Qualité de la neige lundi :
* Absence de regel nocturne sous 2400 m.
* En dessous de 2000 m : neige humide
* Entre de 2000 m et 2400 m : fine couche de neige fraiche humide sur fond humide
* Au-dessus de 2400 m : fine couche de neige fraiche sur fond humide en cours de regel.
* Au-dessus de 2800/3000 m : fine couche de neige fraiche légèrement ventée, de plus en plus épaisse au fil des chutes et en se rapprochant de la frontière Italienne.

Aperçu météo pour le lundi 13 avril

	nuit	matin	après-midi	soir
	Couvert toute la journée, averses de neige toute la journée dans le coeur du massif. Surtout en fin d'après-midi coté Aiguilles Rouges.			
Pluie-Neige	2 200 m	2 000 m	2 100 m	1 900 m
Iso 0 °C	2 600 m	2 500 m	2 500 m	2 300 m
Vent 2000 m	↖ 10 km/h	↖ 15 km/h	↓ 15 km/h	↙ 10 km/h
Vent 4000 m	↖ 45 km/h	↖ 35 km/h	↖ 30 km/h	← 25 km/h

Pour consulter la vigilance en cours, veuillez vous rendre sur le site https://vigilance.meteofrance.fr/fr

Météo-France - 73 avenue de Paris, 94165 Saint-Mandé cedex - Contact : contact@meteo.fr

Rédigé par Météo-France avec la contribution des observateurs du réseau nivo-météorologiques. Partenariat : ANMSM (Maires de Stations de Montagne), DSF (Domaines Skiables de France), ADSP (Directeurs de Pistes et de la Sécurité des Stations de Sports d'Hiver) et autres acteurs de la montagne.

Bulletin neige & avalanches par téléphone au
0 892 68 10 20 Service 0,35 € / min + prix appel

RÉPUBLIQUE FRANÇAISE
Liberté Égalité Fraternité

METEO FRANCE
À VOS CÔTÉS, DANS UN CLIMAT QUI CHANGE

Bulletin d'estimation du risque d'avalanche

(valable en dehors des pistes balisées et ouvertes)

MASSIF : Mont-Blanc

Rédigé le dimanche 12 avril 2026 à 16h

Épaisseur de neige hors-piste

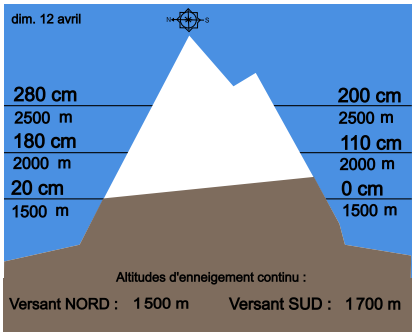

Précipitations à 1800 m

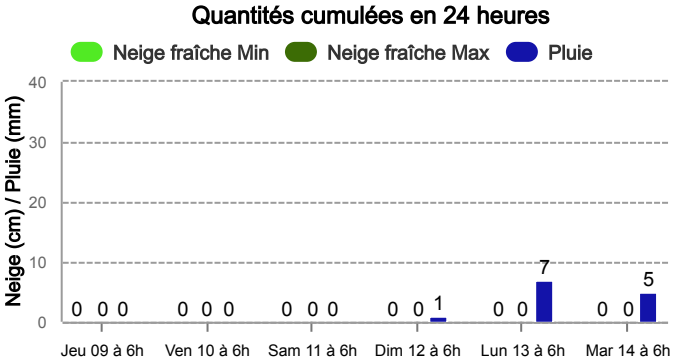

Tendance du mardi 14 avril

Indice de risque limité

Risque stationnaire. Couvert le matin puis rares éclaircies l'après-midi.

Pour consulter la vigilance en cours, veuillez vous rendre sur le site https://vigilance.meteofrance.fr/fr

Météo-France - 73 avenue de Paris, 94165 Saint-Mandé cedex - Contact : contact@meteo.fr

Rédigé par Météo-France avec la contribution des observateurs du réseau nivo-météorologiques. Partenariat : ANMSM (Maires de Stations de Montagne), DSF (Domaines Skiables de France), ADSP (Directeurs de Pistes et de la Sécurité des Stations de Sports d'Hiver) et autres acteurs de la montagne.

Bulletin neige & avalanches par téléphone au

0 892 68 10 20 Service 0,35 € / min + prix appel

RÉPUBLIQUE FRANÇAISE
Liberté Égalité Fraternité

METEO FRANCE
À VOS CÔTÉS, DANS UN CLIMAT QUI CHANGE

Bulletin d'estimation du risque d'avalanche

(valable en dehors des pistes balisées et ouvertes)

MASSIF : Mont-Blanc

Rédigé le dimanche 12 avril 2026 à 16h

Conditions nivo-météo des 7 derniers jours

	lun. 06/04				mar. 07/04				mer. 08/04				jeu. 09/04				ven. 10/04				sam. 11/04				dim. 12/04			
	03h	09h	15h	21h	03h	09h	15h	21h	03h	09h	15h	21h	03h	09h	15h	21h	03h	09h	15h	21h	03h	09h	15h	21h	03h	09h	15h	21h
Météo																												
Vent (km/h)	40	20	15	10	10	10	20	30	20	30	20	20	15	30	30	45	50	60	55	60	60	60	50	60	60	55	60	50
à 4000m																												
Vent (km/h)	30	10	15	10	10	10	5	10	20	20	5	10	5	5	5	5	15	20	20	20	20	20	25	20	20	15	20	15
à 2000m																												

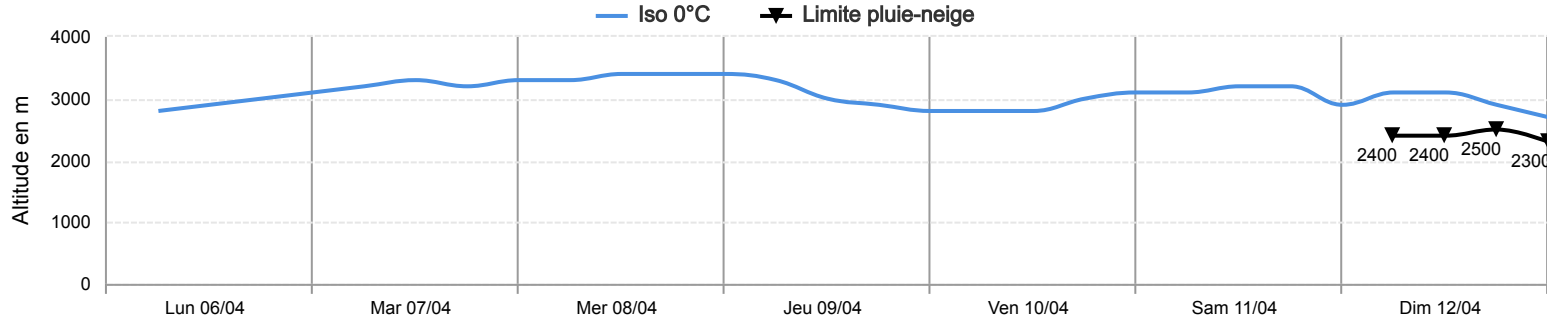

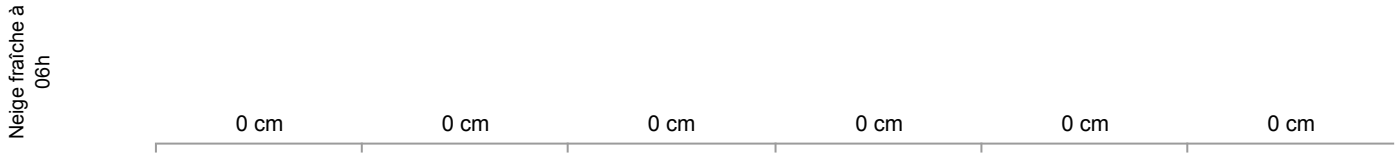

Risque d'avalanche	lun. 06/04	mar. 07/04	mer. 08/04	jeu. 09/04	ven. 10/04	sam. 11/04	dim. 12/04
	2	2	2	3	3	3	2

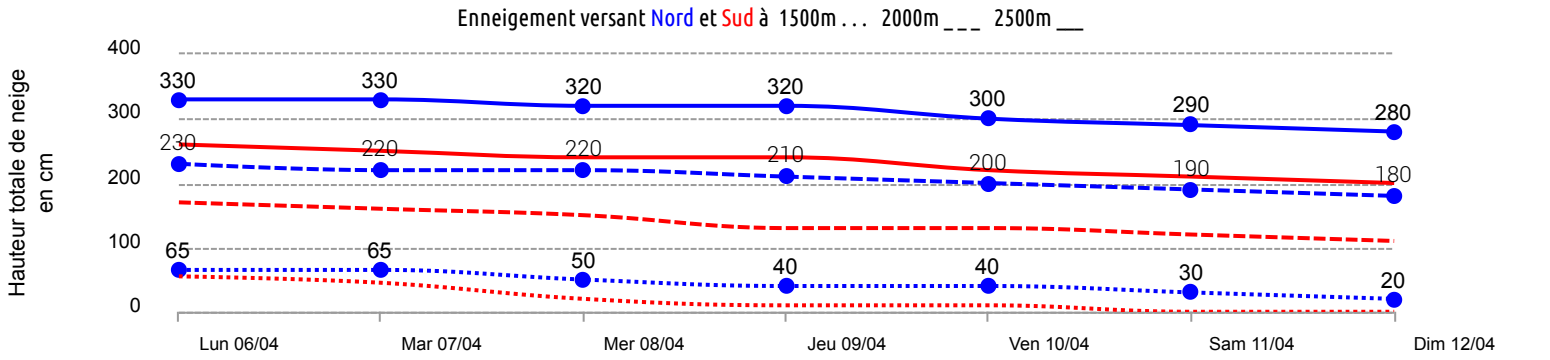

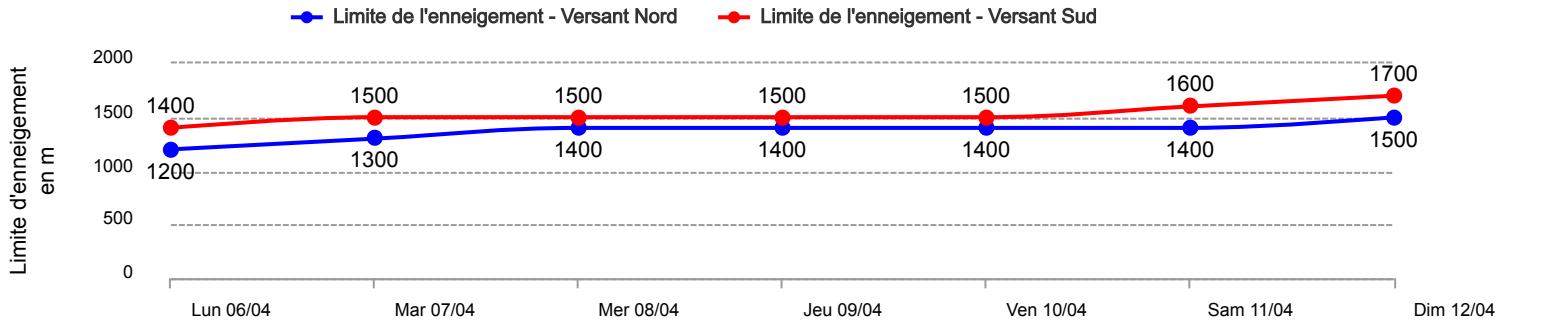

Pour consulter la vigilance en cours, veuillez vous rendre sur le site https://vigilance.meteofrance.fr/fr

Météo-France - 73 avenue de Paris, 94165 Saint-Mandé cedex - Contact : contact@meteo.fr

Rédigé par Météo-France avec la contribution des observateurs du réseau nivo-météorologiques. Partenariat : ANMSM (Maires de Stations de Montagne), DSF (Domaines Skiables de France), ADSP (Directeurs de Pistes et de la Sécurité des Stations de Sports d'Hiver) et autres acteurs de la montagne.

Bulletin neige & avalanches par téléphone au

0 892 68 10 20 Service 0,35 € / min + prix appel