Bulletin d'estimation du risque d'avalanche
(valable en dehors des pistes balisées et ouvertes)

MASSIF : Pelvoux

Rédigé le dimanche 12 avril 2026 à 16h

Estimation des risques pour le : LUNDI 13 AVRIL

UN PEU DE NEIGE FRAÎCHE EN ALTITUDE SUR UN MANTEAU NEIGEUX PLUTÔT HUMIDE ET STABLE

2

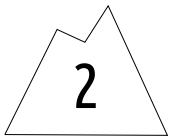

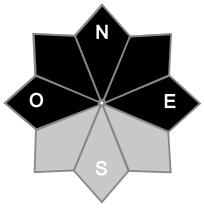

Indice de risque limité.

Départs spontanés : de plus en plus résiduels dans la neige humide

Déclenchements provoqués : petites instabilités dans la neige fraîche à haute altitude

Indices de risque : 5 très fort - 4 fort - 3 marqué - 2 limité - 1 faible -- En noir : les pentes les plus dangereuses

Stabilité du manteau neigeux

Situation avalancheuse typique : neige fraîche neige humide

Déclenchements provoqués : rares instabilités en formation dans la neige récente à haute altitude, au-dessus de 2400 m. Possibles en toute orientation, elles sont plus nombreuses en ouest, nord et nord-est, et plutôt localisées en cœur de massif. Un seul skieur peut les déclencher, générant des avalanches de taille petite, à rarement moyenne, en cas de départ linéaire dans les accumulations de neige ventée. Les chutes de neige prévues sont modestes, tombent peu ventées et sur un manteau neigeux plutôt sain, n'aggravant pas significativement le danger d'avalanche.
Sous 2400 m, le manteau neigeux est complètement humide. Les déclenchements sont ponctuels, mais peuvent mobiliser l'ensemble du manteau neigeux et générer des avalanches de taille moyenne en versant ouest, nord-ouest, nord-est ou est.

Départs spontanés : en neige humide, en atténuation. Départs encore possibles notamment dimanche soir d'avalanches de taille petite à moyenne sous 2400 m, en particulier sous la pluie.

Qualité de la neige

Enneigement déficitaire pour une mi-avril en adrets, proche des normales en ubacs et fonds de vallons.
Hauteurs de neige observées vers 2500 m : 251 cm à la nivôse des Ecrins à 3000 m, 143 cm au Pré de Madame Carle à 1900 m.

Limite d'enneigement skiable : généralement vers 1600/1700 m, très localement 1400/1500 m en ubacs favorables (terrains herbeux, pistes forestières), 2000/2100 m en adrets pas trop raides.

État de la neige de surface : un peu de neige à partir de 2000/2200 m, sur un manteau humide ou mal regelé jusque 2700/2800 m.

Aperçu météo pour le lundi 13 avril

	nuit	matin	après-midi	soir

Couvert et faiblement perturbé ; 10/15 cm de fraîche entre dimanche soir et lundi matin à haute altitude

Pluie-Neige	2 100 m	2 000 m	2 200 m	
Iso 0 °C	2 500 m	2 400 m	2 500 m	2 600 m
Vent 2000 m	↖ 15 km/h	↓ 15 km/h	↓ 20 km/h	↙ 20 km/h
Vent 3000 m	↖ 35 km/h	← 30 km/h	↙ 25 km/h	↙ 20 km/h

Épaisseur de neige hors-piste

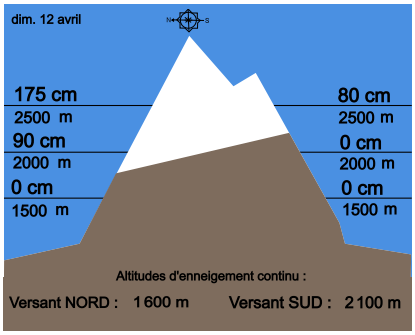

Précipitations à 1800 m

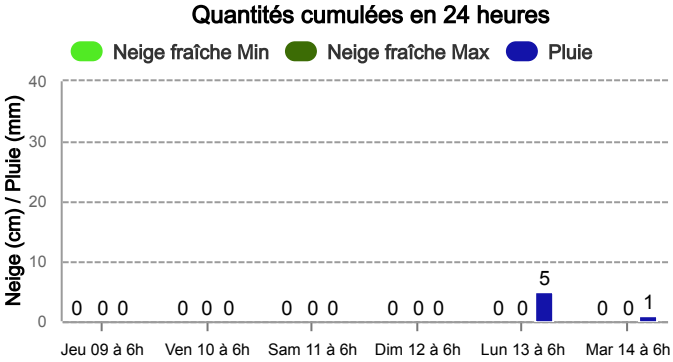

Tendance du mardi 14 avril

2

Indice de risque limité

Tendance à la baisse, mais dépendant des quantités de neige effectivement tombées dimanche soir. Risque restant a priori limité en altitude

Pour consulter la vigilance en cours, veuillez vous rendre sur le site https://vigilance.meteofrance.fr/fr

Météo-France - 73 avenue de Paris, 94165 Saint-Mandé cedex - Contact : contact@meteo.fr

Rédigé par Météo-France avec la contribution des observateurs du réseau nivo-météorologiques. Partenariat : ANMSM (Maires de Stations de Montagne), DSF (Domaines Skiables de France), ADSP (Directeurs de Pistes et de la Sécurité des Stations de Sports d'Hiver) et autres acteurs de la montagne.

Bulletin neige & avalanches par téléphone au
0 892 68 10 20 Service 0,35 € / min + prix appel

RÉPUBLIQUE FRANÇAISE
Liberté Égalité Fraternité

METEO FRANCE
À VOS CÔTÉS, DANS UN CLIMAT QUI CHANGE

Bulletin d'estimation du risque d'avalanche
(valable en dehors des pistes balisées et ouvertes)

MASSIF : Pelvoux

Rédigé le dimanche 12 avril 2026 à 16h

Conditions nivo-météo des 7 derniers jours

	lun. 06/04				mar. 07/04				mer. 08/04				jeu. 09/04				ven. 10/04				sam. 11/04				dim. 12/04			
	03h	09h	15h	21h	03h	09h	15h	21h	03h	09h	15h	21h	03h	09h	15h	21h	03h	09h	15h	21h	03h	09h	15h	21h	03h	09h	15h	21h
Météo																												
Vent (km/h)	25	20	15	10	15	5	10	10	5	5	10	10	10	15	25	30	25	25	25	20	20	20	15	20	20	20	30	35
à 3000m																												
Vent (km/h)	10	10	15	5	5	5	10	5	5	5	10	5	5	10	20	20	20	20	20	10	10	10	15	5	5	15	10	15
à 2000m																												

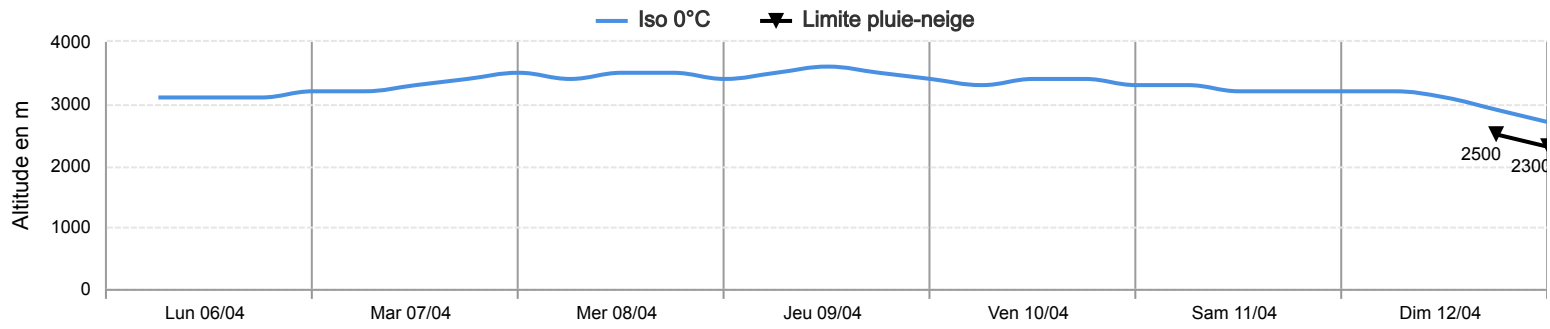

Neige fraîche à 06h

lun. 06/04	mar. 07/04	mer. 08/04	jeu. 09/04	ven. 10/04	sam. 11/04
0 cm	0 cm	0 cm	0 cm	0 cm	0 cm

Risque d'avalanche	lun. 06/04	mar. 07/04	mer. 08/04	jeu. 09/04	ven. 10/04	sam. 11/04	dim. 12/04
	2	2	2	3	3	3	2

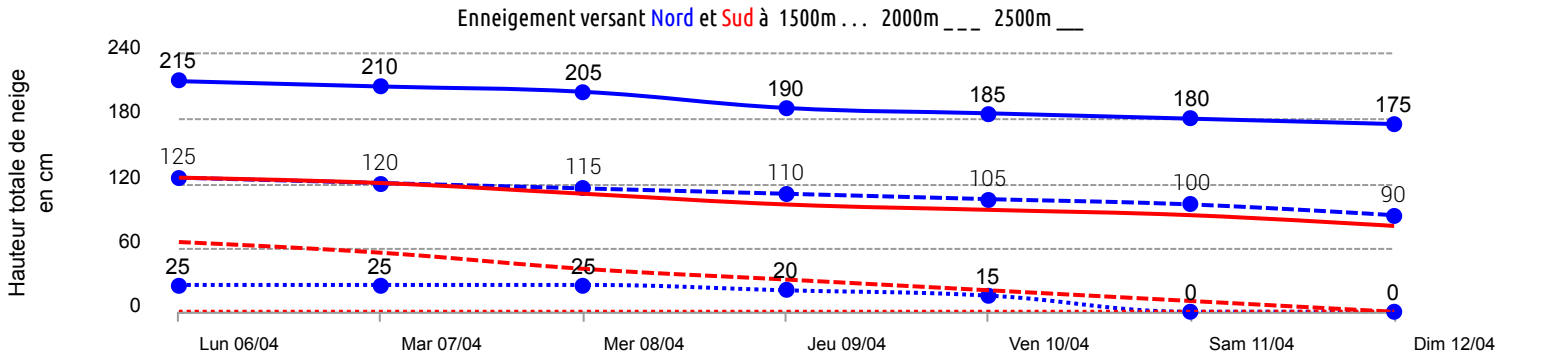

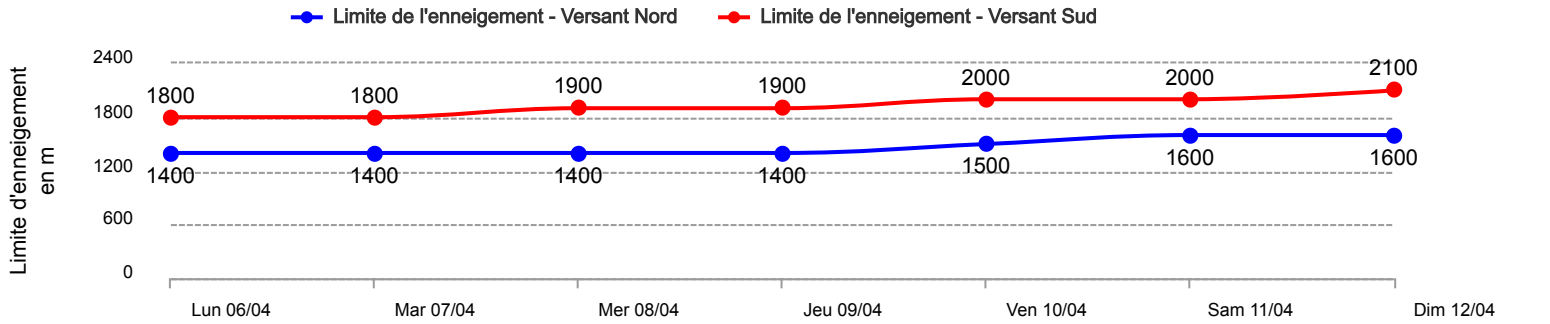

Pour consulter la vigilance en cours, veuillez vous rendre sur le site https://vigilance.meteofrance.fr/fr

Météo-France - 73 avenue de Paris, 94165 Saint-Mandé cedex - Contact : contact@meteo.fr

Bulletin neige & avalanches par téléphone au **0 892 68 10 20** Service 0,35 € / min + prix appel

Rédigé par Météo-France avec la contribution des observateurs du réseau nivo-météorologiques. Partenariat : ANMSM (Maires de Stations de Montagne), DSF (Domaines Skiables de France), ADSP (Directeurs de Pistes et de la Sécurité des Stations de Sports d'Hiver) et autres acteurs de la montagne.