Bulletin d'estimation du risque d'avalanche

(valable en dehors des pistes balisées et ouvertes)

MASSIF : Queyras

Rédigé le dimanche 12 avril 2026 à 16h

Estimation des risques pour le : LUNDI 13 AVRIL

NEIGE DEVENANT ABONDANTE A LA FRONTIÈRE ITALIENNE

3

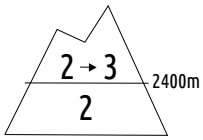

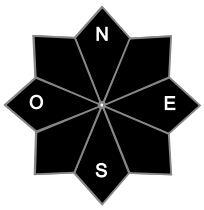

Au-dessus de 2400m indice de risque limité évoluant en marqué, plus bas indice limité.

Départs spontanés : Avalanches de neige fraîche à haute altitude sur le secteur frontalier, taille moyenne à grande en fin de journée

Déclenchements provoqués : Nombreuses instabilités en formation sur le secteur frontalier italien

Indices de risque : 5 très fort - 4 fort - 3 marqué - 2 limité - 1 faible -- En noir : les pentes les plus dangereuses

Stabilité du manteau neigeux

Situation avalancheuse typique : neige fraîche couche fragile persistante

Déclenchements provoqués : nombreuses instabilités de surface en formation sous les chutes de neige modérément ventées. Localisées surtout à la frontière italienne au-dessus de 2400 m (secteur Fonts de Cervières, Le Roux, Valpréveyre, L'Échalp), elles sont facilement déclenchables par un seul skieur. Avalanches possibles en toute orientation et de taille petite à moyenne. Cet apport important de neige fraîche tombe sur un manteau généralement humide et plutôt sain (voire un sol nu en adrets) ; en ubacs de haute altitude, il peut cependant réactiver les couches fragiles enfouies à la base du manteau neigeux, générant alors une avalanche de grande taille, avec déclenchement possible à distance.
Sur l'ouest du massif où les chutes sont négligeables, le danger est plus limité, les instabilités se situent dans la neige encore humide, plutôt sous 2400 m.

Départs spontanés : de neige fraîche ventée, taille petite à moyenne sur le secteur frontalier italien, grande non exclue en fin de journée dans les secteurs d'accumulation par la lombarde à haute altitude. Sur le reste du massif, rares et ponctuels en neige humide, taille petite à moyenne en versants nord.

Qualité de la neige

Enneigement nettement déficitaire pour une mi-avril avant l'épisode de ce lundi, notamment en adrets, parfois secs jusqu'à 2500 m.
Hauteurs de neige observées vers 2500 m : 115 cm en versant nord du col Izoard et au-dessus de Saint-Véran à 2700 m, 65 cm à la Nivôse du Col Agnel à 2630 m.

Limite d'enneigement skiable : au plus bas à 1700/1800 m en ubacs bien protégés ou sur pistes forestières, plutôt 2200/2300 m en adrets.

État de la neige de surface : neige fraîche de plus en plus épaisse en allant vers la frontière italienne, tombant sèche et modérément ventée à partir de 2300/2400 m. Sur la majeure partie du massif, manteau neigeux humide, regel très limité à partir de 2600/2800 m.

Aperçu météo pour le lundi 13 avril

	nuit	matin	après-midi	soir
Retour d'Est très frontalier et doux				
Pluie-Neige	2 000 m	1 900 m	1 900 m	2 000 m
Iso 0 °C	2 400 m	2 300 m	2 400 m	2 400 m
Vent 2000 m	← 25 km/h	↙ 20 km/h	↙ 25 km/h	↙ 15 km/h
Vent 3000 m	← 25 km/h	← 40 km/h	↓ 30 km/h	↙ 30 km/h

Épaisseur de neige hors-piste

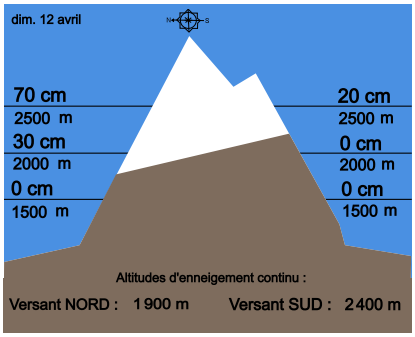

Précipitations à 1800 m

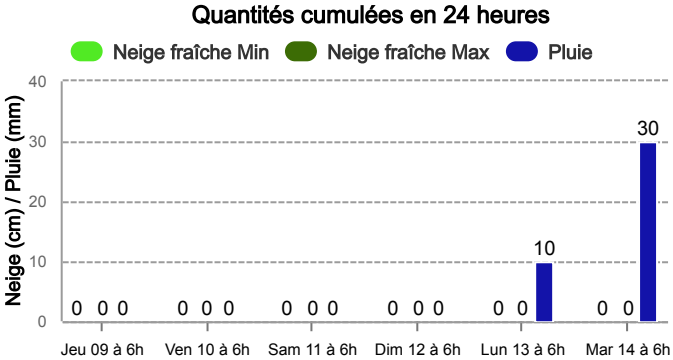

Tendance du mardi 14 avril

3 **Indice de risque marqué**

Tendance à la baisse avec l'arrêt des précipitations. Risque encore marqué en début de journée sur le secteur frontalier italien.

Pour consulter la vigilance en cours, veuillez vous rendre sur le site https://vigilance.meteofrance.fr/fr

Météo-France - 73 avenue de Paris, 94165 Saint-Mandé cedex - Contact : contact@meteo.fr

Rédigé par Météo-France avec la contribution des observateurs du réseau nivo-météorologiques. Partenariat : ANMSM (Maires de Stations de Montagne), DSF (Domaines Skiables de France), ADSP (Directeurs de Pistes et de la Sécurité des Stations de Sports d'Hiver) et autres acteurs de la montagne.

Bulletin neige & avalanches par téléphone au
0 892 68 10 20 Service 0,35 € / min + prix appel

RÉPUBLIQUE FRANÇAISE
Liberté Égalité Fraternité

METEO FRANCE
À VOS CÔTÉS, DANS UN CLIMAT QUI CHANGE

Bulletin d'estimation du risque d'avalanche
(valable en dehors des pistes balisées et ouvertes)

MASSIF : Queyras

Rédigé le dimanche 12 avril 2026 à 16h

Conditions nivo-météo des 7 derniers jours

	lun. 06/04				mar. 07/04				mer. 08/04				jeu. 09/04				ven. 10/04				sam. 11/04				dim. 12/04			
	03h	09h	15h	21h	03h	09h	15h	21h	03h	09h	15h	21h	03h	09h	15h	21h	03h	09h	15h	21h	03h	09h	15h	21h	03h	09h	15h	21h
Météo																												
Vent (km/h)	30	20	20	20	20	15	15	10	10	10	10	10	15	20	25	25	30	30	35	25	25	25	25	15	20	25	30	30
à 3000m																												
Vent (km/h)	10	10	20	5	5	5	20	5	5	5	15	5	5	10	25	15	20	20	25	10	10	10	25	10	10	15	30	20
à 2000m																												

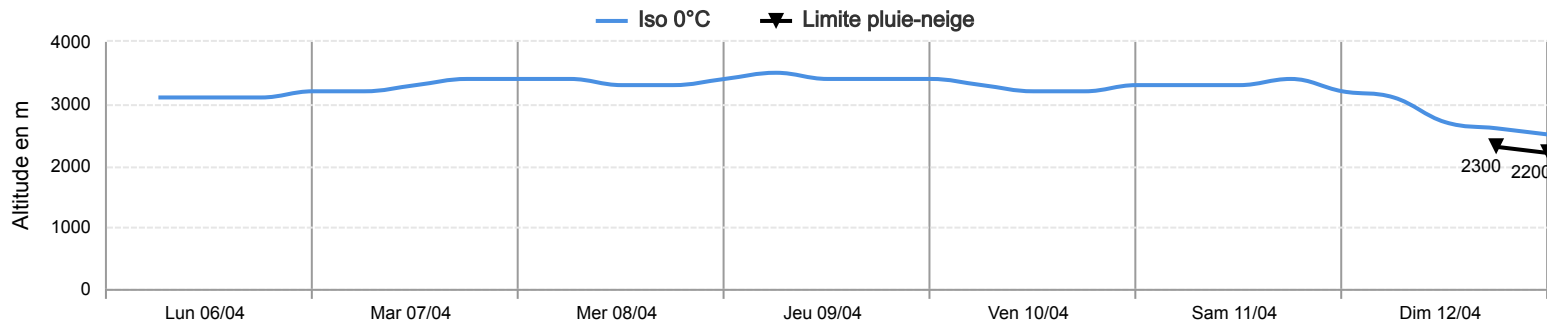

Neige fraîche à 06h

lun. 06/04	mar. 07/04	mer. 08/04	jeu. 09/04	ven. 10/04	sam. 11/04	dim. 12/04
0 cm	0 cm	0 cm	0 cm	0 cm	0 cm	

Risque d'avalanche	lun. 06/04	mar. 07/04	mer. 08/04	jeu. 09/04	ven. 10/04	sam. 11/04	dim. 12/04
	2	2	2	3	3	3	2

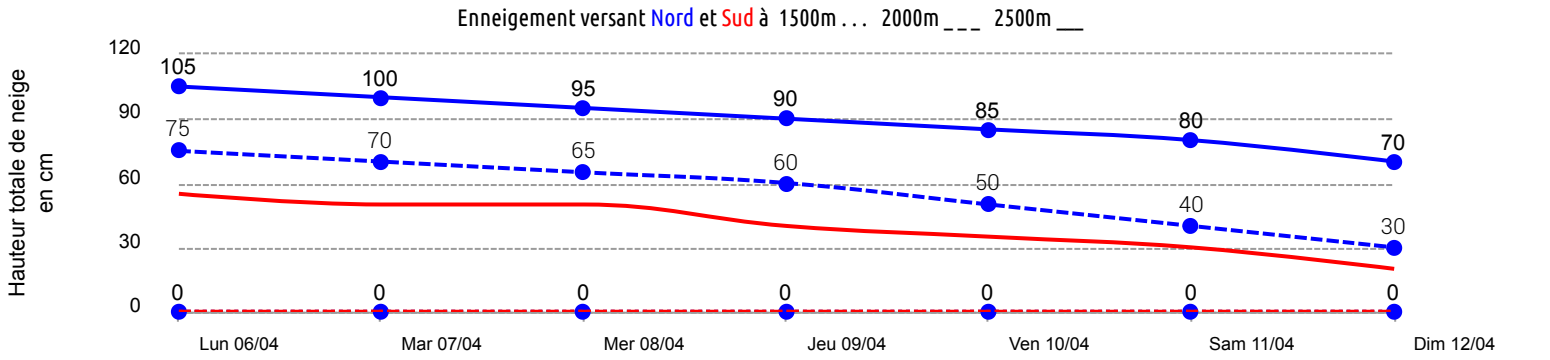

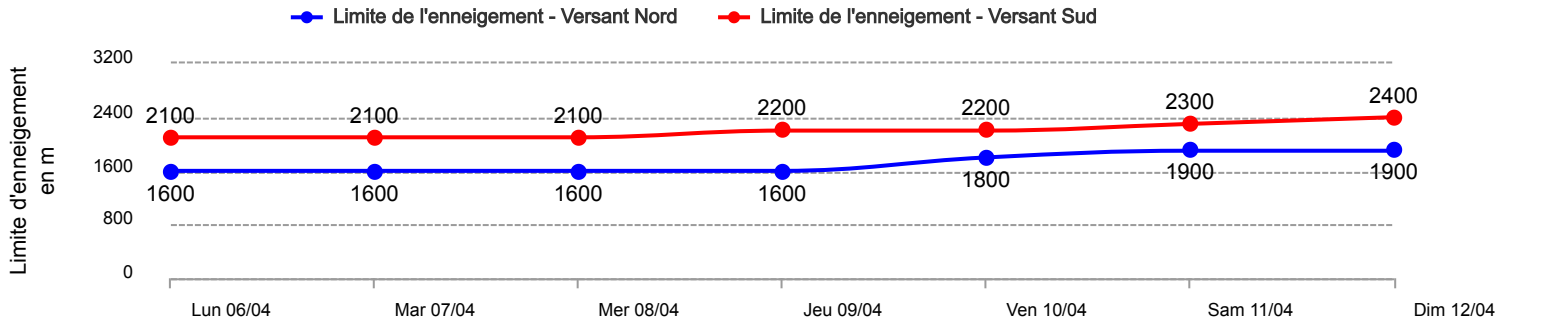

Pour consulter la vigilance en cours, veuillez vous rendre sur le site https://vigilance.meteofrance.fr/fr

Météo-France - 73 avenue de Paris, 94165 Saint-Mandé cedex - Contact : contact@meteo.fr

Bulletin neige & avalanches par téléphone au **0 892 68 10 20** Service 0,35 € / min + prix appel

Rédigé par Météo-France avec la contribution des observateurs du réseau nivo-météorologiques. Partenariat : ANMSM (Maires de Stations de Montagne), DSF (Domaines Skiables de France), ADSP (Directeurs de Pistes et de la Sécurité des Stations de Sports d'Hiver) et autres acteurs de la montagne.