Bulletin d'estimation du risque d'avalanche
(valable en dehors des pistes balisées et ouvertes)

MASSIF : Vercors

Rédigé le dimanche 12 avril 2026 à 16h

Estimation des risques pour le : LUNDI 13 AVRIL

MANTEAU ENTIEREMENT HUMIDE, FINE COUCHE DE NEIGE RECENTE EN ALTITUDE

2

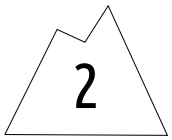

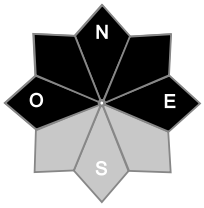

Indice de risque limité.

Départs spontanés : Quelques coulées humides ou un rare départ au terrain

Déclenchements provoqués : Coulée ponctuelles sous les skis en pentes raides

Indices de risque : 5 très fort - 4 fort - 3 marqué - 2 limité - 1 faible -- En noir : les pentes les plus dangereuses

Stabilité du manteau neigeux

Situation avalancheuse typique : neige humide avalanches de fond

Départs spontanés :

-Le manteau neigeux est la plupart du temps humide jusqu'à la base, hormis peut être dans les versants Nord d'altitude. L'humidification se poursuit et s'accélère sous les averses dans la nuit de dimanche à lundi, favorisant le risque de coulées humides, notamment en versants Nord. En plein Sud le risque de coulées est plus faible, la plupart des coulées étant déjà parties lors de la semaine dernière.

- Dans les pentes raides herbeuses ou sur les dalles rocheuses, un rare départ au terrain reste possible, parfois précédé par l'ouverture d'une fissure (gueule de baleine).

Déclenchements provoqués :

- En pente raide, possibilité de faire partir une petite coulée humide sous les skis.

Qualité de la neige

Qualification de l'enneigement : L'enneigement est toujours correct en moyenne montagne peu ensoleillée, mais il se dégrade fortement depuis maintenant une grosse semaine. La fonte se poursuit ce lundi, mais ralentit sur le haut du massif avec l'arrivée d'air moins doux.

Limites skiables : Vers 1200/1500m en plein Nord (hors sapins), 1700/1800m au soleil...

Qualité de la neige lundi : Neige humide voire pourrie sur l'ensemble du massif. La masse d'air se rafraîchit légèrement l'après-midi et quelques cm de neige récente humide sont possibles au-dessus de 1500m.

Aperçu météo pour le lundi 13 avril

	nuit	matin	après-midi	soir

Journée encore maussade, temps très nuageux avec de rares averses en journée.

Pluie-Neige	2 200 m	1 600 m	1 400 m	1 400 m
Iso 0 °C	2 500 m	2 200 m	2 000 m	2 000 m
Vent 1500 m	↓ 15 km/h	↓ 20 km/h	↓ 30 km/h	↓ 35 km/h
Vent 2000 m	← 15 km/h	↓ 20 km/h	↓ 35 km/h	↙ 35 km/h

Épaisseur de neige hors-piste

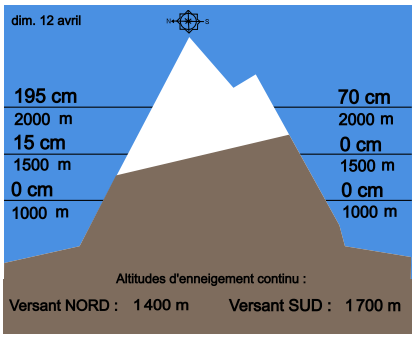

Précipitations à 1800 m

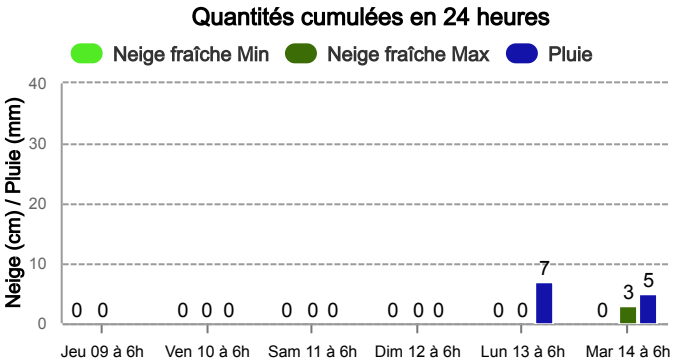

Tendance du mardi 14 avril

2

Indice de risque limité

Mardi, risque limité. Le massif reste plongé dans le nuage, dans une masse d'air assez douce. Le manteau neigeux reste humide, avec quelques coulées ou départs au terrain.

Pour consulter la vigilance en cours, veuillez vous rendre sur le site https://vigilance.meteofrance.fr/fr

Météo-France - 73 avenue de Paris, 94165 Saint-Mandé cedex - Contact : contact@meteo.fr

Rédigé par Météo-France avec la contribution des observateurs du réseau nivo-météorologiques. Partenariat : ANMSM (Maires de Stations de Montagne), DSF (Domaines Skiables de France), ADSP (Directeurs de Pistes et de la Sécurité des Stations de Sports d'Hiver) et autres acteurs de la montagne.

Bulletin neige & avalanches par téléphone au
0 892 68 10 20 Service 0,35 € / min + prix appel

Bulletin d'estimation du risque d'avalanche

(valable en dehors des pistes balisées et ouvertes)

MASSIF : Vercors

Rédigé le dimanche 12 avril 2026 à 16h

Conditions nivo-météo des 7 derniers jours

	lun. 06/04				mar. 07/04				mer. 08/04				jeu. 09/04				ven. 10/04				sam. 11/04				dim. 12/04			
	03h	09h	15h	21h	03h	09h	15h	21h	03h	09h	15h	21h	03h	09h	15h	21h	03h	09h	15h	21h	03h	09h	15h	21h	03h	09h	15h	21h
Météo																												
Vent (km/h)	20	20	15	5	5	15	10	10	10	10	5	10	15	15	25	45	40	35	25	20	20	25	20	15	25	15	15	10
à 2000m																												
Vent (km/h)	10	10	10	5	5	5	5	10	10	5	5	5	10	10	20	25	20	30	20	10	15	15	20	10	15	15	20	15
à 1500m																												

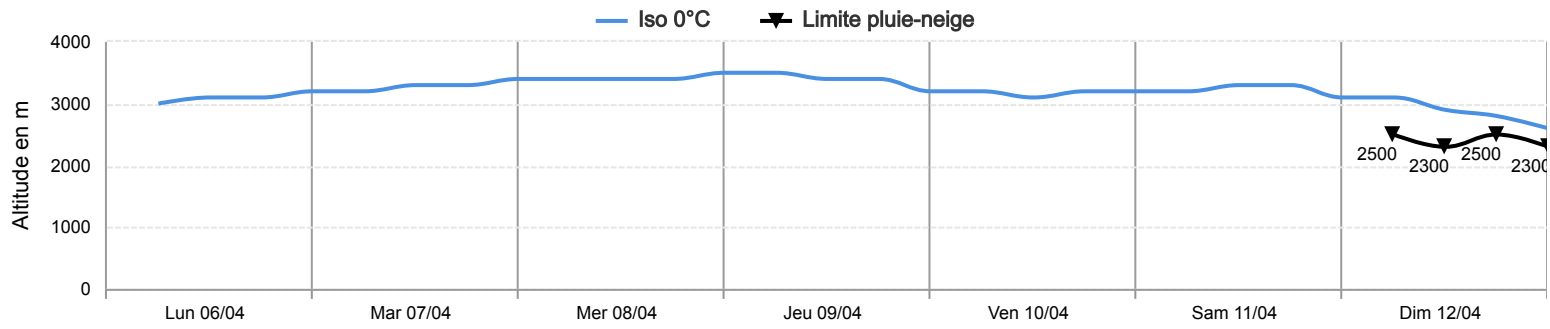

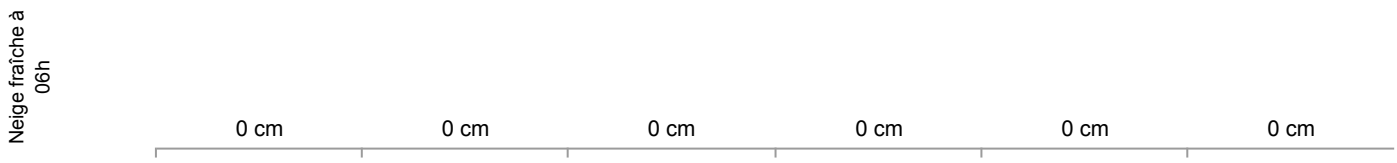

Risque d'avalanche	lun. 06/04	mar. 07/04	mer. 08/04	jeu. 09/04	ven. 10/04	sam. 11/04	dim. 12/04
	2	2	2	2	2	2	2

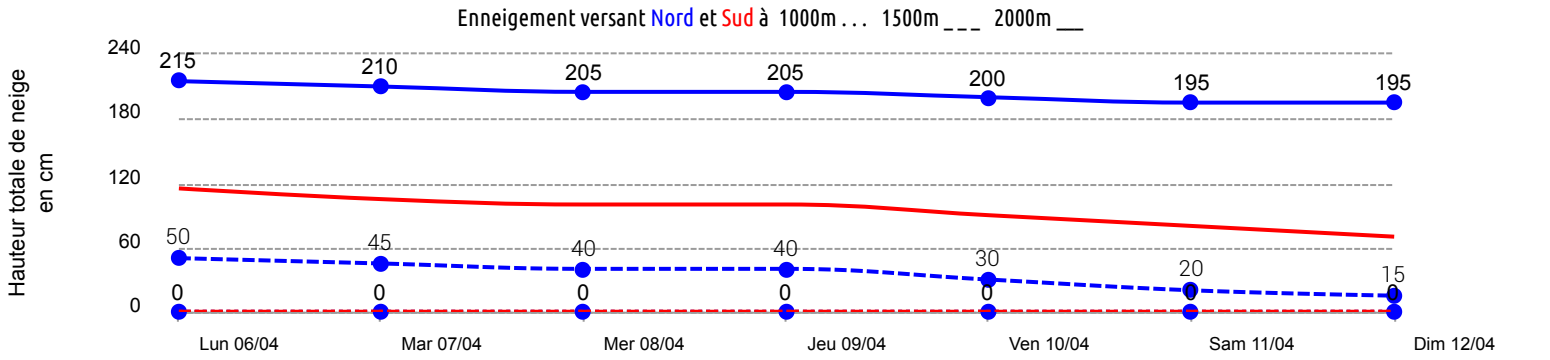

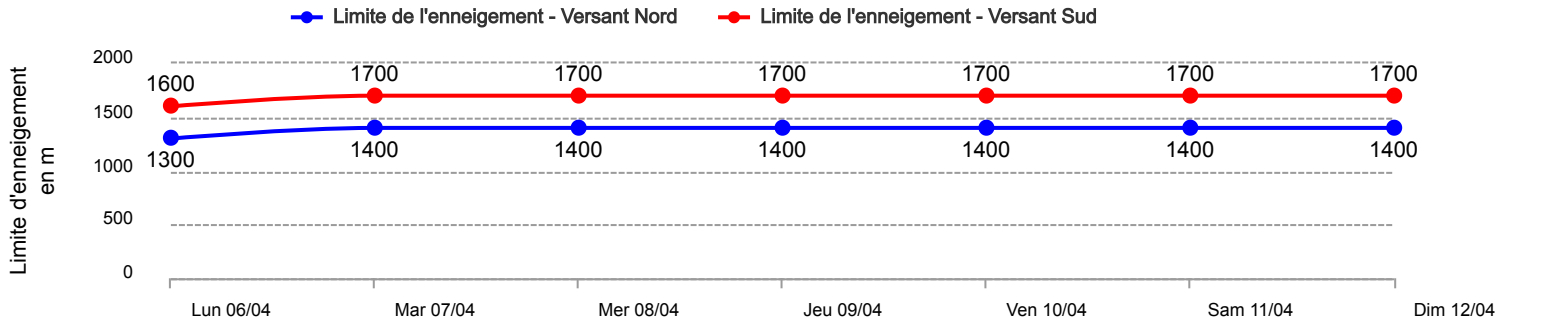

Pour consulter la vigilance en cours, veuillez vous rendre sur le site https://vigilance.meteofrance.fr/fr

Météo-France - 73 avenue de Paris, 94165 Saint-Mandé cedex - Contact : contact@meteo.fr

Rédigé par Météo-France avec la contribution des observateurs du réseau nivo-météorologiques. Partenariat : ANMSM (Maires de Stations de Montagne), DSF (Domaines Skiables de France), ADSP (Directeurs de Pistes et de la Sécurité des Stations de Sports d'Hiver) et autres acteurs de la montagne.

Bulletin neige & avalanches par téléphone au

0 892 68 10 20 Service 0,35 € / min + prix appel