RÉPUBLIQUE FRANÇAISE
Liberté Égalité Fraternité

METEO FRANCE
À VOS CÔTÉS, DANS UN CLIMAT QUI CHANGE

Bulletin d'estimation du risque d'avalanche
(valable en dehors des pistes balisées et ouvertes)

MASSIF : Beaufortain

Rédigé le dimanche 12 avril 2026 à 17h

Estimation des risques pour le : LUNDI 13 AVRIL

CIEL COUVERT, MAUVAIS REGEL ET HUMIDIFICATION MÊME EN PLEIN NORD.

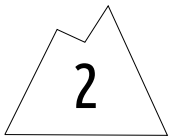

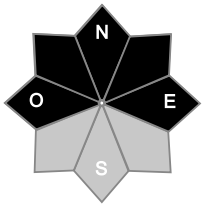

Indice de risque limité.

Départs spontanés : quelques départs en neige humide possibles à toutes heures, même en nord.

Déclenchements provoqués : petites coulées sous les skis dans la neige fortement humidifiée (pourrie).

Indices de risque : 5 très fort - 4 fort - 3 marqué - 2 limité - 1 faible -- En noir : les pentes les plus dangereuses

Stabilité du manteau neigeux

Situation avalancheuse typique : neige humide

Départs spontanés :
- **Quelques départs en neige humide** sont attendus en **tous versants** et **à toute heure de la journée**. Ce sont principalement des **départs ponctuels (poires)**, donnant des **petites à moyennes avalanches**. En effet, le regel est très mauvais et malgré l'absence de soleil, la masse d'air très douce combinée à la présence d'une épaisse couverture nuageuse va permettre la poursuite de l'activité en neige humide. On s'attend à une activité moins soutenue que les jours précédents, notamment en versants ensoleillés. En revanche, les versants nord encaissés et protégés du soleil (restés en neige froide jusqu'à maintenant) subissent leur première humidification marquée et seront donc eux aussi concernés par ce risque.
- **Rares avalanches de glissement** (plaques de fond) à toute heure sur terrain propice, notamment en Nord sous 2400 m. Taille 2.

Déclenchements provoqués : avalanche de neige humide (pourrie) sous les skis en coupant une pente trop humidifiée (dès le matin).

Autres : chutes de corniches possibles à toute heure.

Qualité de la neige

Enneigement : l'enneigement est revenu au niveau des normales suite à la chaleur des derniers jours (fonte accélérée de 5 à 10 cm par jour).

Limite skiable : vers 1200/1300 m en Nord, 1600/1700 m en Sud.

Qualité de la neige : regel mauvais ou inexistant. Neige humide voire profondément pourrie partout dès le matin. Collante possible en Nord, dans les rares secteurs qui étaient encore en neige froide et s'humidifient eux aussi. Quelques centimètres de fraiche à partir de 2200 m mais souvent humide sous 2500 m.

Aperçu météo pour le lundi 13 avril

	nuit	matin	après-midi	soir

Ciel bouché à tous les étages, bouillard et effet jour blanc fréquent. Quelques gouttes l'après-midi.

Pluie-Neige			2 000 m	1 800 m
Iso 0 °C	2 600 m	2 400 m	2 400 m	2 200 m
Vent 2000 m	← 15 km/h	↙ 15 km/h	↓ 15 km/h	↙ 10 km/h
Vent 3000 m	↖ 30 km/h	← 20 km/h	↙ 20 km/h	← 20 km/h

Épaisseur de neige hors-piste

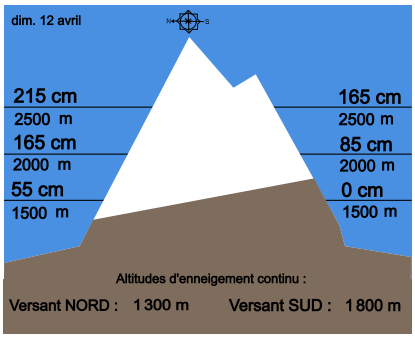

Précipitations à 1800 m

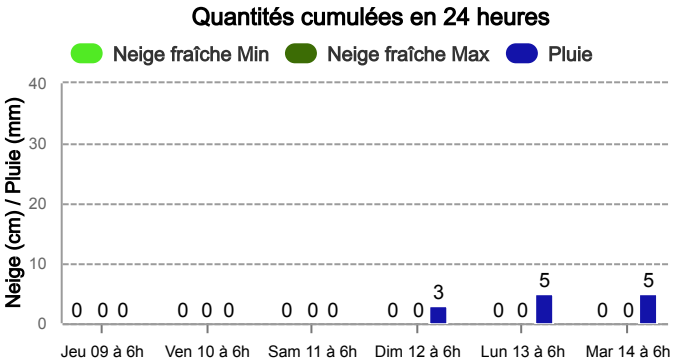

Tendance du mardi 14 avril

Indice de risque limité

Le temps maussade et humide persiste, empêchant un bon regel, le risque reste donc limité pour une problématique de neige humide.

Pour consulter la vigilance en cours, veuillez vous rendre sur le site https://vigilance.meteofrance.fr/fr

Météo-France - 73 avenue de Paris, 94165 Saint-Mandé cedex - Contact : contact@meteo.fr

Rédigé par Météo-France avec la contribution des observateurs du réseau nivo-météorologiques. Partenariat : ANMSM (Maires de Stations de Montagne), DSF (Domaines Skiables de France), ADSP (Directeurs de Pistes et de la Sécurité des Stations de Sports d'Hiver) et autres acteurs de la montagne.

Bulletin neige & avalanches par téléphone au
0 892 68 10 20 Service 0,35 € / min + prix appel

RÉPUBLIQUE FRANÇAISE
Liberté Égalité Fraternité

METEO FRANCE
À VOS CÔTÉS, DANS UN CLIMAT QUI CHANGE

Bulletin d'estimation du risque d'avalanche
(valable en dehors des pistes balisées et ouvertes)
MASSIF : Beaufortain

Rédigé le dimanche 12 avril 2026 à 17h

Conditions nivo-météo des 7 derniers jours

	lun. 06/04				mar. 07/04				mer. 08/04				jeu. 09/04				ven. 10/04				sam. 11/04				dim. 12/04			
	03h	09h	15h	21h	03h	09h	15h	21h	03h	09h	15h	21h	03h	09h	15h	21h	03h	09h	15h	21h	03h	09h	15h	21h	03h	09h	15h	21h
Météo																												
Vent (km/h)	30	20	15	15	10	5	5	15	15	10	5	5	10	20	30	15	15	20	30	20	15	20	25	25	25	30	35	35
à 3000m																												
Vent (km/h)	15	10	10	10	5	0	5	5	10	5	0	0	5	15	25	10	10	15	25	10	10	10	15	15	15	15	20	20
à 2000m																												

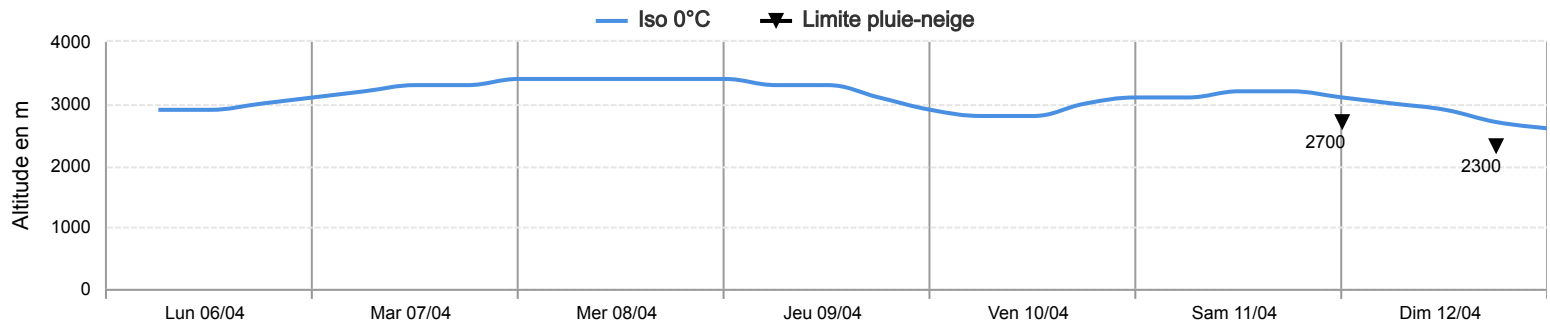

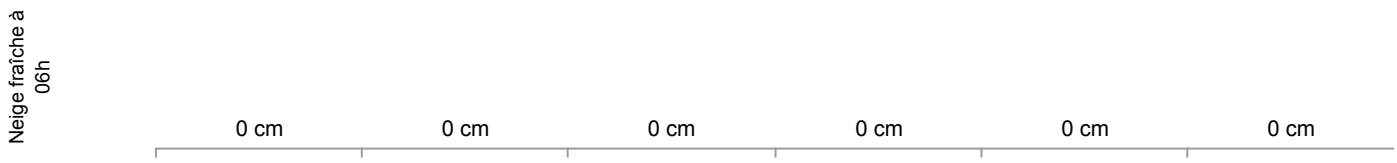

Risque d'avalanche	lun. 06/04	mar. 07/04	mer. 08/04	jeu. 09/04	ven. 10/04	sam. 11/04	dim. 12/04
	2	2	2	2	2	2	2



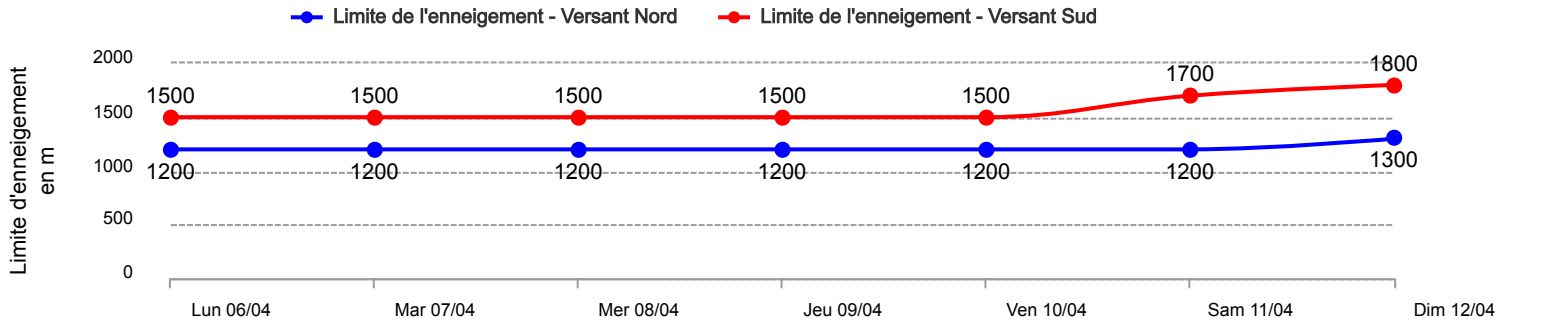

Pour consulter la vigilance en cours, veuillez vous rendre sur le site https://vigilance.meteofrance.fr/fr

Météo-France - 73 avenue de Paris, 94165 Saint-Mandé cedex - Contact : contact@meteo.fr

Bulletin neige & avalanches par téléphone au **0 892 68 10 20** Service 0,35 € / min + prix appel

Rédigé par Météo-France avec la contribution des observateurs du réseau nivo-météorologiques. Partenariat : ANMSM (Maires de Stations de Montagne), DSF (Domaines Skiables de France), ADSP (Directeurs de Pistes et de la Sécurité des Stations de Sports d'Hiver) et autres acteurs de la montagne.