Bulletin d'estimation du risque d'avalanche

(valable en dehors des pistes balisées et ouvertes)

MASSIF : Maurienne

Rédigé le dimanche 12 avril 2026 à 17h

Estimation des risques pour le : LUNDI 13 AVRIL

CIEL COUVERT, MAUVAIS REGEL ET HUMIDIFICATION MÊME EN PLEIN NORD. HIVERNAL SECTEUR THABOR

2

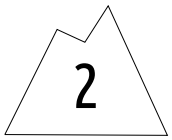

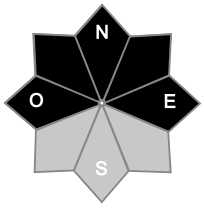

Indice de risque limité.

Départs spontanés : quelques départs en neige humide possibles à toutes heures, même en nord.

Déclenchements provoqués : petites coulées sous les skis dans la neige fortement humidifiée (pourrie).

Indices de risque : 5 très fort - 4 fort - 3 marqué - 2 limité - 1 faible -- En noir : les pentes les plus dangereuses

Stabilité du manteau neigeux

Situation avalancheuse typique : neige humide neige fraîche

Départs spontanés :

- **Quelques départs en neige humide** sont attendus en **tous versants** et **à toute heure de la journée**. Les départs peuvent être ponctuels (poires), donnant des **petites à moyennes avalanches,** mais aussi plus rarement **linéaires (plaques) donnant alors de grandes avalanches (taille 3)** car l'eau de fonte qui percole dans le manteau atteint désormais les couches fragiles enfouies du début de saison. **Ces cassures linéaires semblent plus probables en versants Est/Nord/Ouest, sous 2700 m**.

En effet, le regel est très mauvais et malgré un soleil quasi inexistant, la masse d'air douce combinée à la présence d'une épaisse couverture nuageuse va permettre la poursuite de l'activité en neige humide. On s'attend à une activité moins soutenue que les jours précédents, notamment en versants ensoleillés. En revanche, les versants nord encaissés et protégés du soleil (restés en neige froide jusqu'à maintenant) subissent leur première humidification marquée et seront donc eux aussi concernés par ce risque.

- **Rares avalanches de glissement** (plaques de fond) à toute heure sur terrain propice, notamment sous 2500 m. Taille 2.

Déclenchements provoqués : avalanche de neige humide (pourrie) sous les skis en coupant une pente trop humidifiée (notamment aux altitudes intermédiaires 2000/2800 m). Coulées sous les skis voire cassure linéaire pouvant donner une rare grande avalanche quand les couches fragiles du début de saison s'humidifient.

Secteur Thabor : retour d'Est en cours. En altitude, nouvelles plaques d'aspect poudreux, de plus en plus fréquentes, réactive et épaisses en cours de journée. Cassures jsuqu'à 20 cm en fin de journée.

Autres : chutes de corniches possibles à toute heure.

Qualité de la neige

Enneigement : l'enneigement est revenu au niveau des normales suite à la chaleur des derniers jours (fonte accélérée de 5 à 10 cm par jour).

Limite skiable : vers 1400/1500 m en Nord, 1800/1900 m en Sud.

Qualité de la neige : regel mauvais ou inexistant. Neige humide voire profondément pourrie partout dès le matin. Collante possible en Nord, dans les rares secteurs qui étaient encore en neige froide et s'humidifient eux aussi. Quelques centimètres de fraiche à partir de 2300 m (jsuqu'à 15/20 cm vers le Thabor) mais souvent humide sous 2600 m.

Aperçu météo pour le lundi 13 avril

	nuit	matin	après-midi	soir

Ciel bouché à tous les étages, bouillard et effet jour blanc fréquent. Quelques gouttes l'après-midi. Secteur Thabor concerné par un retour d'Est.

Pluie-Neige	1 900 m	2 000 m	2 100 m	1 800 m
Iso 0 °C	2 300 m	2 400 m	2 400 m	2 100 m
Vent 2000 m	↖ 20 km/h	↙ 15 km/h	↓ 10 km/h	↓ 5 km/h
Vent 3000 m	↖ 30 km/h	↖ 25 km/h	↗ 20 km/h	↓ 15 km/h

Épaisseur de neige hors-piste

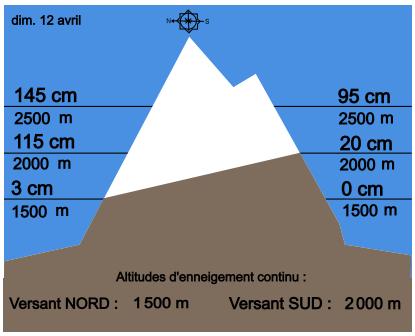

Précipitations à 1800 m

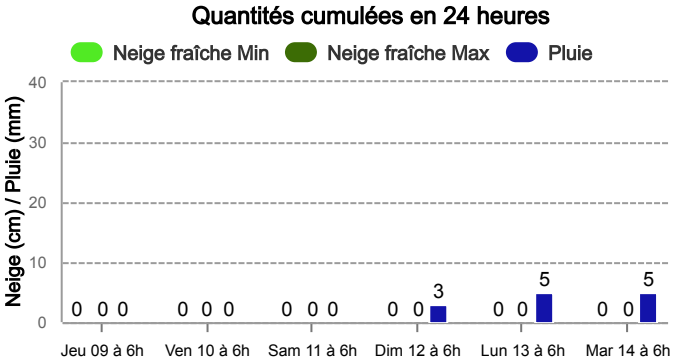

Tendance du mardi 14 avril

2

Indice de risque limité

Le temps maussade et humide persiste, empêchant un bon regel, le risque reste donc limité pour une problématique de neige humide.

Pour consulter la vigilance en cours, veuillez vous rendre sur le site https://vigilance.meteofrance.fr/fr

Météo-France - 73 avenue de Paris, 94165 Saint-Mandé cedex - Contact : contact@meteo.fr

Rédigé par Météo-France avec la contribution des observateurs du réseau nivo-météorologiques. Partenariat : ANMSM (Maires de Stations de Montagne), DSF (Domaines Skiables de France), ADSP (Directeurs de Pistes et de la Sécurité des Stations de Sports d'Hiver) et autres acteurs de la montagne.

Bulletin neige & avalanches par téléphone au 0 892 68 10 20 Service 0,35 € / min + prix appel

RÉPUBLIQUE FRANÇAISE
Liberté Égalité Fraternité

METEO FRANCE
À VOS CÔTÉS, DANS UN CLIMAT QUI CHANGE

Bulletin d'estimation du risque d'avalanche
(valable en dehors des pistes balisées et ouvertes)

MASSIF : Maurienne

Rédigé le dimanche 12 avril 2026 à 17h

Conditions nivo-météo des 7 derniers jours

	lun. 06/04				mar. 07/04				mer. 08/04				jeu. 09/04				ven. 10/04				sam. 11/04				dim. 12/04			
	03h	09h	15h	21h	03h	09h	15h	21h	03h	09h	15h	21h	03h	09h	15h	21h	03h	09h	15h	21h	03h	09h	15h	21h	03h	09h	15h	21h
Météo																												
Vent (km/h)	30	20	15	15	10	5	10	10	10	10	5	5	10	20	30	15	15	20	30	20	15	20	25	25	25	25	30	30
à 3000m																												
Vent (km/h)	15	10	10	10	0	0	5	0	0	0	0	0	5	15	25	10	10	15	25	10	10	10	10	15	15	15	20	20
à 2000m																												

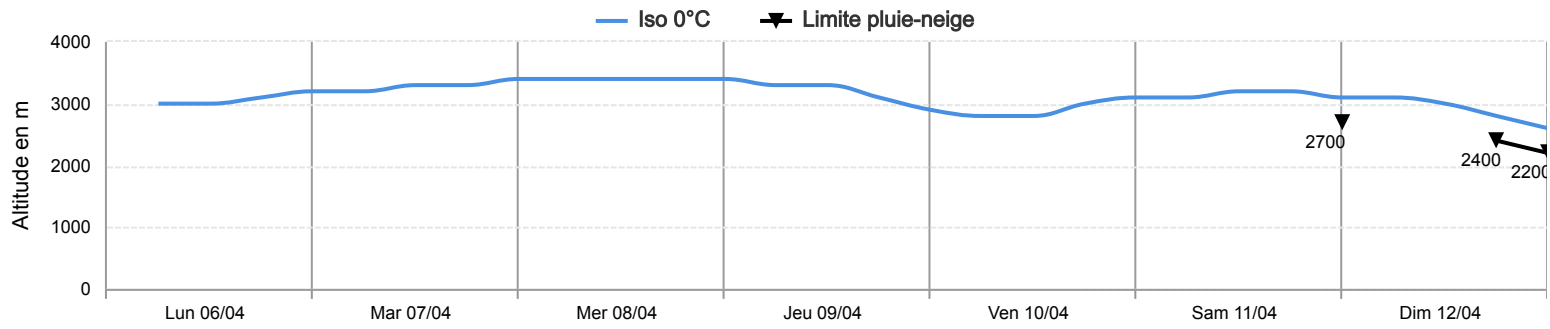

Neige fraîche à 06h

lun. 06/04	mar. 07/04	mer. 08/04	jeu. 09/04	ven. 10/04	sam. 11/04	dim. 12/04
0 cm	0 cm	0 cm	0 cm	0 cm	0 cm	

Risque d'avalanche	lun. 06/04	mar. 07/04	mer. 08/04	jeu. 09/04	ven. 10/04	sam. 11/04	dim. 12/04
	2	2	3	3	3	3	2

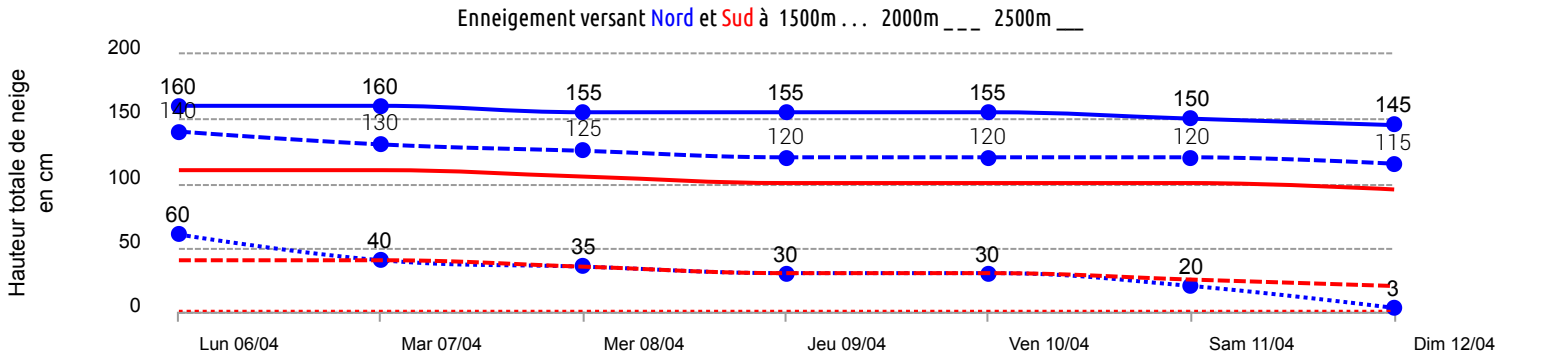

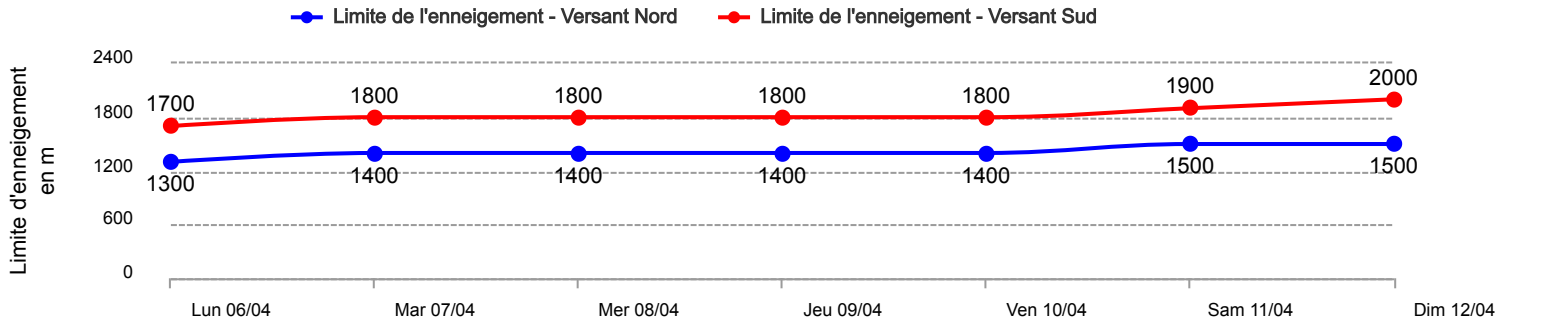

Pour consulter la vigilance en cours, veuillez vous rendre sur le site https://vigilance.meteofrance.fr/fr

Météo-France - 73 avenue de Paris, 94165 Saint-Mandé cedex - Contact : contact@meteo.fr

Rédigé par Météo-France avec la contribution des observateurs du réseau nivo-météorologiques. Partenariat : ANMSM (Maires de Stations de Montagne), DSF (Domaines Skiables de France), ADSP (Directeurs de Pistes et de la Sécurité des Stations de Sports d'Hiver) et autres acteurs de la montagne.

Bulletin neige & avalanches par téléphone au
0 892 68 10 20 Service 0,35 € / min + prix appel