Danger d'avalanche

actualisé le 12.4.2026, 17:00

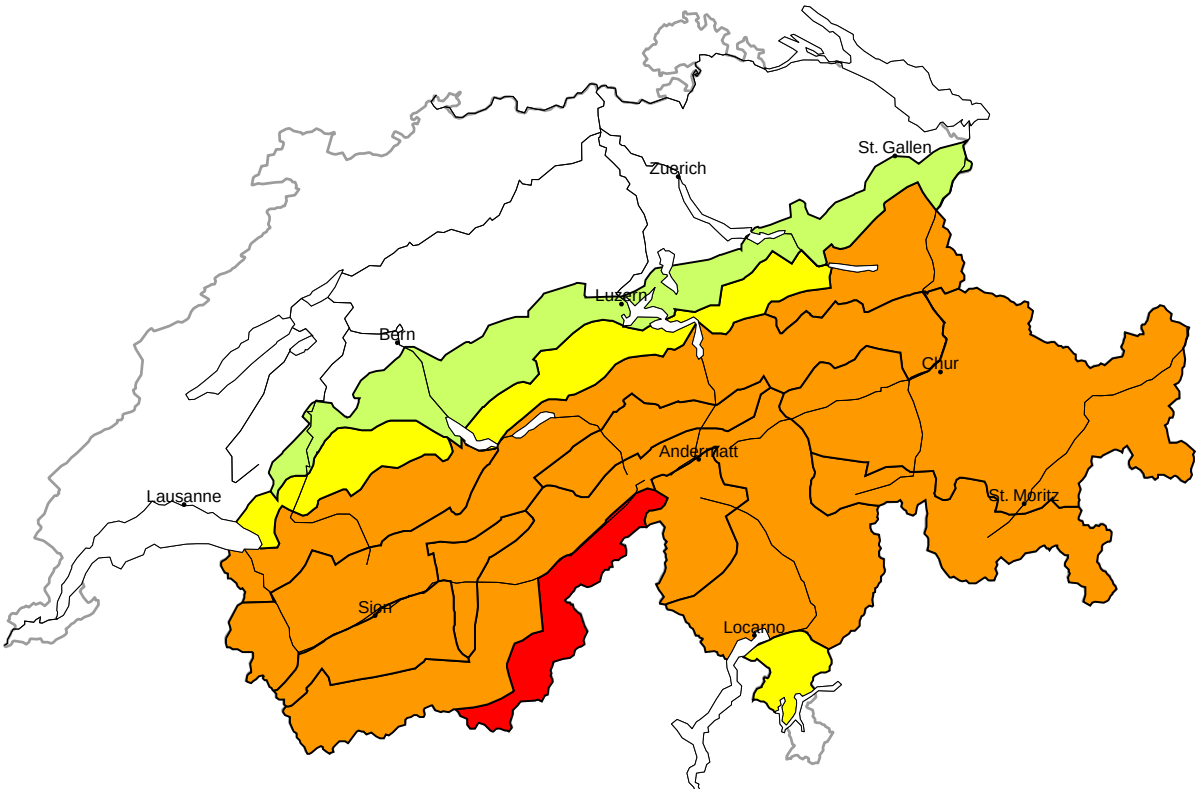

région A

Fort (4-)

Neige fraîche, Couche fragile persistante

Endroits dangereux

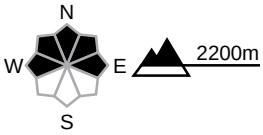

Description des dangers
La neige fraîche abondante et la neige soufflée sont fragiles. Des avalanches sèches peuvent se déclencher dans la neige ancienne. À partir de la seconde moitié de nuit des avalanches spontanées sont à attendre, de manière isolée, également de très grande taille. Elles peuvent entraîner la neige ancienne mouillée et s'avancer jusque dans les vallées. Les tronçons exposés des voies de communication peuvent être menacés partiellement. Les conditions pour les sports de neige en dehors des pistes sécurisées sont très dangereuses.

Fort (4)

Neige humide

Avec la pluie intensive des avalanches mouillées nombreuses sont à attendre, surtout sur les pentes raides exposées à l'ouest, au nord et à l'est en dessous d'environ 2200 m. Des avalanches mouillées peuvent parfois entraîner l'ensemble du manteau neigeux et atteindre une grande taille.

Degrés de danger 1 faible 2 limité 3 marqué 4 fort 5 très fort

région B

Marqué (3+)

Neige fraîche, Couche fragile persistante

Endroits dangereux

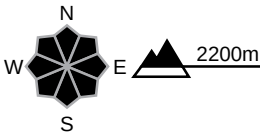

Description des dangers
La neige fraîche et la neige soufflée sont fragiles en altitude. Des avalanches spontanées sèches de plus en plus fréquentes sont possibles. Des avalanches sèches peuvent parfois se déclencher dans la neige ancienne et atteindre une grande taille. Elles peuvent entraîner la neige ancienne mouillée et s'avancer jusqu'aux prairies.

Marqué (3)

Neige humide

Avec la pluie des avalanches mouillées très nombreuses sont à attendre, surtout sur les pentes raides exposées à l'ouest, au nord et à l'est en dessous d'environ 2200 m. Des avalanches mouillées peuvent parfois entraîner l'ensemble du manteau neigeux et atteindre une grande taille. Pour des randonnées les conditions sont très critiques.

région C

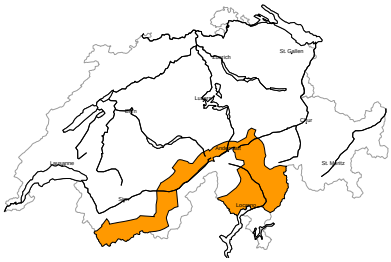

Marqué (3=)

Neige fraîche, Couche fragile persistante

Endroits dangereux

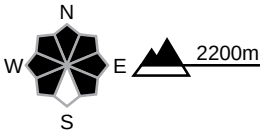

Description des dangers
La neige fraîche et la neige soufflée sont fragiles en altitude. Des avalanches sèches peuvent aussi se déclencher dans la neige ancienne et atteindre une grande taille. En cours de journée des avalanches spontanées isolées sont possibles. Les randonnées et descentes hors-piste demandent de l' expérience dans l'évaluation du danger d'avalanche et de la retenue.

Marqué (3)

Neige humide

Avec la pluie des avalanches mouillées très nombreuses sont à attendre, surtout sur les pentes raides exposées à l'ouest, au nord et à l'est en dessous d'environ 2200 m. Des avalanches mouillées peuvent parfois entraîner l'ensemble du manteau neigeux et atteindre une grande taille. Pour des randonnées les conditions sont très critiques.

région D

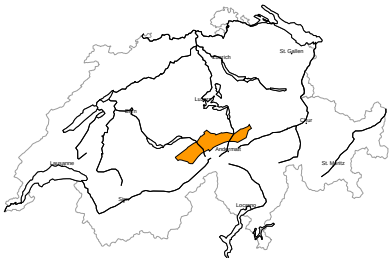

Marqué (3-)

Neige soufflée, Couche fragile persistante

Endroits dangereux

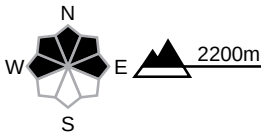

Description des dangers
Des accumulations de neige soufflée susceptibles d'être déclenchées se forment avec la neige fraîche et le vent de sud. Des amateurs de sports d'hiver seuls peuvent déclencher des avalanches. En outre, des avalanches sèches peuvent par endroits être déclenchées dans la neige ancienne et atteindre une grande taille de manière isolée.
Les randonnées demandent une expérience dans l'évaluation du danger d'avalanche.

Marqué (3)

Neige humide

La surface de la neige regèle peu et se ramollit rapidement. Des avalanches de neige mouillée et de glissement sont à attendre. Ceci surtout sur les pentes raides exposées à l'est, au sud et à l'ouest entre environ 2000 et 2800 m comme sur les pentes raides exposées au nord en dessous d'environ 2400 m. Des avalanches mouillées peuvent aussi par endroits être déclenchées par des personnes. Des avalanches peuvent atteindre une grande taille.
Pour des randonnées les conditions sont critiques.

région E

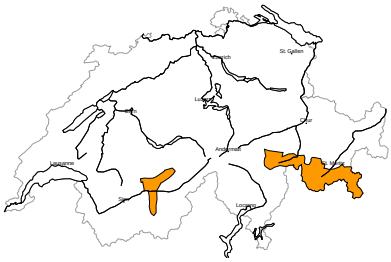

Marqué (3-)

Neige soufflée, Couche fragile persistante

Endroits dangereux

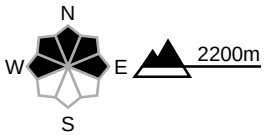

Description des dangers
Des accumulations de neige soufflée susceptibles d'être déclenchées se forment avec la neige fraîche et le vent de sud. Des amateurs de sports d'hiver seuls peuvent déclencher des avalanches. En outre, des avalanches sèches peuvent par endroits être déclenchées dans la neige ancienne et atteindre une grande taille de manière isolée.
Les randonnées demandent une expérience dans l'évaluation du danger d'avalanche.

Marqué (3)

Neige humide

Avec la pluie des avalanches mouillées très nombreuses sont à attendre, surtout sur les pentes raides exposées à l'ouest, au nord et à l'est en dessous d'environ 2200 m. Des avalanches mouillées peuvent parfois entraîner l'ensemble du manteau neigeux et atteindre une grande taille. Pour des randonnées les conditions sont très critiques.

région F

Marqué (3)

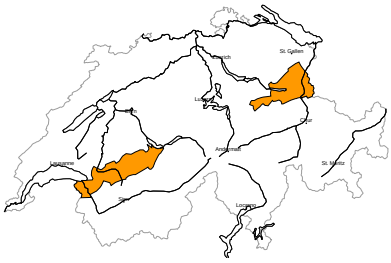

Neige humide

La surface de la neige regèle peu et se ramollit rapidement. Des avalanches de neige mouillée et de glissement sont à attendre. Ceci surtout sur les pentes raides exposées à l'est, au sud et à l'ouest entre environ 2000 et 2800 m comme sur les pentes raides exposées au nord en dessous d'environ 2400 m. Des avalanches mouillées peuvent aussi par endroits être déclenchées par des personnes. Des avalanches peuvent atteindre une grande taille.
Pour des randonnées les conditions sont critiques.

Faible (1)

Aucune situation avalancheuse typique prédominante

Endroits dangereux

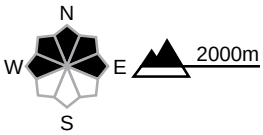

Description des dangers
Il ne faut pratiquement pas s'attendre à des avalanches sèches. Des endroits dangereux très isolés se situent surtout sur les pentes extrêmement raides à l'ombre en altitude.

région G

Marqué (3)

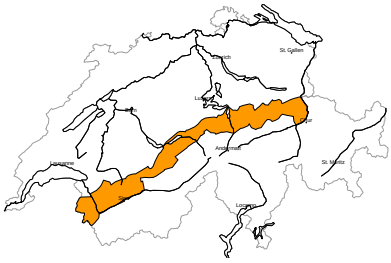

Neige humide

La surface de la neige regèle peu et se ramollit rapidement. Des avalanches de neige mouillée et de glissement sont à attendre. Ceci surtout sur les pentes raides exposées à l'est, au sud et à l'ouest entre environ 2000 et 2800 m comme sur les pentes raides exposées au nord en dessous d'environ 2400 m. Des avalanches mouillées peuvent aussi par endroits être déclenchées par des personnes. Des avalanches peuvent atteindre une grande taille.
Pour des randonnées les conditions sont critiques.

Limité (2=)

Neige soufflée

Endroits dangereux

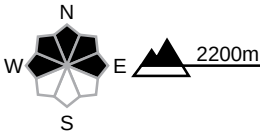

Description des dangers
Des accumulations de neige soufflée en partie fragiles se forment avec la neige fraîche et le vent de sud en altitude. Celles-ci se situent surtout à proximité des crêtes, dans les combes et couloirs. Les avalanches peuvent par endroits être déclenchées par un seul amateur de sports d'hiver et atteindre une taille moyenne.
Un choix prudent des itinéraires est recommandé.

région H

Marqué (3)

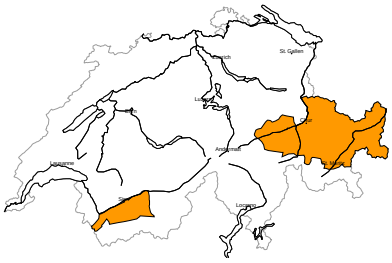

Neige humide

La surface de la neige regèle peu. À partir de la matinée des avalanches mouillées sont possibles. Ceci surtout sur les pentes raides ensoleillées entre environ 2000 et 3000 m comme sur les pentes raides exposées au nord en dessous d'environ 2400 m. Des avalanches mouillées peuvent être déclenchées par des personnes. Des bruits sourds isolés peuvent attirer l'attention sur le danger. Des avalanches peuvent atteindre une grande taille.
Les conditions de randonnées sont critiques.

Limité (2=)

Neige soufflée, Couche fragile persistante

Endroits dangereux

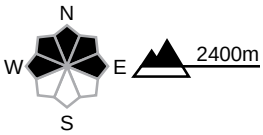

Description des dangers
Des avalanches sèches peuvent par endroits être déclenchées dans la neige ancienne et atteindre une grande taille de manière isolée. Ces endroits dangereux sont à peine identifiables même pour un oeil exercé. Prudence dans les endroits plutôt faiblement enneigés sur les terrains de randonnée rarement fréquentés.
Des accumulations de neige soufflée plutôt petites se forment avec le vent de sud localement.
Un choix prudent des itinéraires est recommandé.

région I

Limité (2)

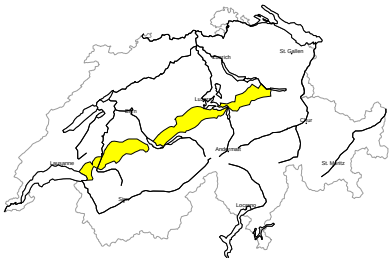

Neige humide

Des avalanches de neige mouillée et de glissement sont possibles, également de taille moyenne. Les endroits dangereux se situent surtout sur les pentes exposées à l'ouest, au nord et à l'est.
Un choix prudent des itinéraires est important.

Faible (1)

Aucune situation avalancheuse typique prédominante

Endroits dangereux

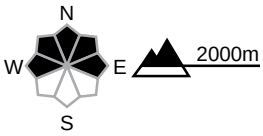

Description des dangers
Il ne faut pratiquement pas s'attendre à des avalanches sèches. Des endroits dangereux très isolés se situent surtout sur les pentes extrêmement raides à l'ombre en altitude.

région J — Limité (2)

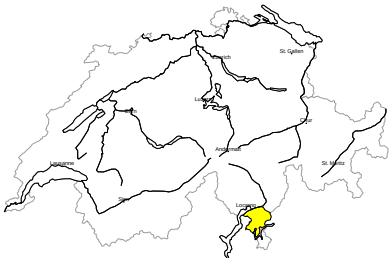

Neige humide

Avec la pluie des avalanches mouillées sont possibles, surtout sur les pentes raides exposées à l'ouest, au nord et à l'est. Des avalanches peuvent atteindre une taille moyenne de manière isolée.
Même une petite avalanche peut entraîner des personnes et les faire chuter.

région K — Faible (1)

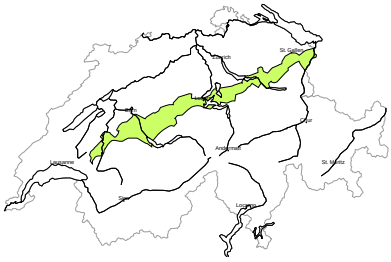

Neige humide

Sur les pentes raides herbeuses des coulées mouillées isolées sont possibles. Il convient de tenir compte du danger d'être emporté et entraîné dans une chute.

Manteau neigeux et météo

actualisé le 12.4.2026, 17:00

Manteau neigeux

Avec un temps doux, des nuits partiellement couvertes et temporairement de la pluie, l'humidification du manteau neigeux a progressé pendant la semaine passée. Le manteau neigeux est humidifié sur les pentes exposées au sud jusqu'à environ 3000 m et sur les pentes aux expositions est et ouest jusqu'à 2500 à 2700 m. Sur les pentes exposées au nord, il est humidifié en dessous de 2000 m et l'humidification se poursuit entre 2000 et 2400 m.
Avec les chutes de neige attendues,qui seront parfois intenses dans le sud, de grandes accumulations de neige soufflée se formeront en altitude. Des avalanches spontanées peuvent parfois entraîner tout le manteau neigeux, surtout sur les pentes exposées au nord. Cela concerne surtout les régions du Valais touchées par les précipitations les plus abondantes, mais localement aussi les autres régions. Des personnes peuvent en outre déclencher des avalanches dans la neige fraîche et la neige soufflée.
Avec la pluie, il faut s'attendre à davantage d'avalanches de neige mouillée et de glissement.

Rétrospective météo de ce dimanche

Le temps était généralement nuageux avec de faibles averses dans les Préalpes. La limite pluie-neige se situait à 2000 m. Les Grisons ont parfois bénéficié d'éclaircies.

Neige fraîche
-

Température
À la mi-journée à 2000 m, aux alentours de +3 °C dans le nord et le Tessin et +6 °C dans les régions intra-alpines

Vent
de secteur sud, faible à modéré, mais en journée modéré à fort sur la crête nord des Alpes

Prévisions météorologiques jusqu'à lundi

Dimanche soir, il y aura des précipitations dans le sud, qui s'intensifieront pendant la nuit de dimanche à lundi et qui seront parfois très abondantes dans certaines régions du sud. Les précipitations s'étendront également au nord, mais elles y seront plus faibles. La limite des chutes de neige se situera entre 1800 et 2000 m. Dans les régions de la crête principale des Alpes du Haut-Valais avec les précipitations les plus abondantes, elle descendra et se situera le lundi matin entre 1500 et 1700 m.

Neige fraîche
Jusqu'à lundi après-midi au-dessus de 2200 à 2400 m:
- Région du Mont Rose, vallée de la Saas, région du Simplon: de 60 à 80 cm
- Reste de la crête principale des Alpes du Haut-Valais, nord-ouest du Tessin: de 40 à 60 cm
- Reste de la crête principale des Alpes depuis le Grand-Saint-Bernard jusqu'au col du Lukmanier, crête nord des Alpes depuis le Lötschental jusquà la Reuss, vallées inférieures de la Maggia, Leventina: de 20 à 40 cm
- Reste du Valais, reste de la crête principale des Alpes à l'ouest du Tödi, crête principale des Alpes depuis le Lukmanier jusque dans la région de la Bernina: de 15 à 30 cm
- Ailleurs: quelques centimètres ou temps sec

Température
A la mi-journée à 2000 m, +2 °C dans l'ouest et le sud, et +4 °C dans l'est

Vent
De secteur sud à sud-est, pendant la nuit de dimanche à lundi fort en haute montagne, et sinon modéré à fort, diminuant l'après-midi

Tendance

Mardi
Le temps sera très nuageux avec de faibles précipitations. La limite des chutes de neige se situera entre 1500 et 1800 m dans le nord et entre 1800 et 2000 m dans le sud. En cours de journée, le ciel se dégagera surtout en Valais et dans le sud. Le vent sera faible à modéré de secteur nord-est.
Le danger d'avalanches de neige sèche diminuera dans le sud. Les conditions pour les randonnées resteront cependant critiques en altitude. Dans le nord, le danger d'avalanches de neige sèche n'évoluera guère. Des avalanches de neige mouillée seront possibles dans toutes les régions, surtout sur les pentes aux expositions ouest, nord et est en dessous d'environ 2400 m. Dans les régions avec de la neige fraîche, il faudra s'attendre sous l'effet du rayonnement en altitude à des avalanches de neige meuble à partir de la neige fraîche, et à moyenne altitude, à des coulées humides et des avalanches de glissement.

Mercredi
Le temps sera assez ensoleillé, mais de faibles averses éparses seront possibles en cours de journée. L'isotherme zéro degré montera à 2800 m. Le vent sera généralement faible. Le danger d'avalanches de neige sèche diminuera. Le danger d'avalanches de neige mouillée augmentera en cours de journée.