GOBIERNO DE ESPAÑA
VICEPRESIDENCIA TERCERA DEL GOBIERNO
MINISTERIO PARA LA TRANSICIÓN ECOLÓGICA Y EL RETO DEMOGRÁFICO

Boletín de información nivológica y de peligro de aludes

# Pirineo Catalán

aemet Agencia Estatal de Meteorología

## lunes, 13 de abril de 2026

## Pronóstico hasta las 24 horas del martes, día 14 de abril

(Válido fuera de pistas de esquí balizadas y abiertas)

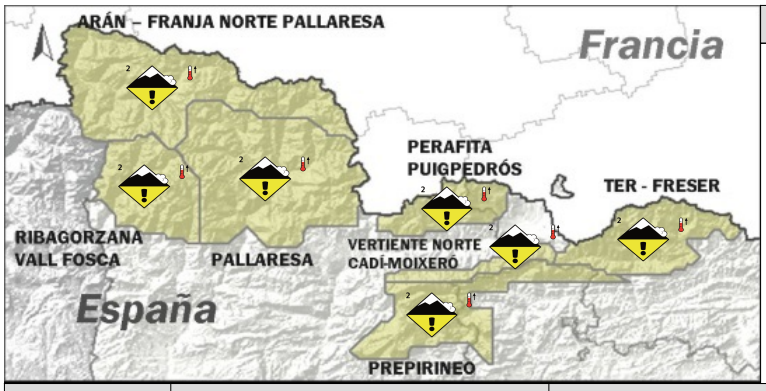


### Problemas de aludes

Placas de viento

Nieve húmeda

| Macizo | Peligro | Problemas de aludes, cota, orientación, tamaño | Innivación observada (m) |
|---|---|---|---|
| Arán - Franja norte Pallaresa | 2 Limitado | Placas de viento: 2200, N O E S, 2<br>Nieve húmeda: N O E S, 2 | 2026-04-13<br>N S Cotas medias |
| Ribagorzana - Vall Fosca | 2 Limitado | Placas de viento: 2 / 1, 2200, N O E S, 1<br>Nieve húmeda: N O E S, 2 | 2026-04-13<br>N S Cotas medias |
| Pallaresa | 2 Limitado | Placas de viento: 2 / 1, 2200, N O E S, 1<br>Nieve húmeda: N O E S, 2 | 2026-04-13<br>N S Cotas medias |


AEMET. Se autoriza la reproducción de su contenido citando la fuente.

Boletín de información nivológica y de peligro de aludes

# Pirineo Catalán



| | | | |
|---|---|---|---|
| **Perafita - Puigpedrós** | 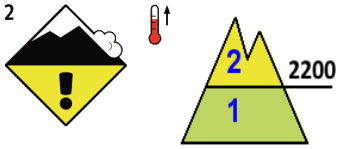  **Limitado** | **Placas de viento** **Nieve húmeda** 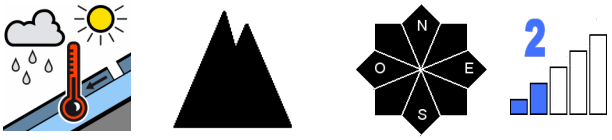  | 2026-04-13 Cotas medias |
| **Ter - Freser** | 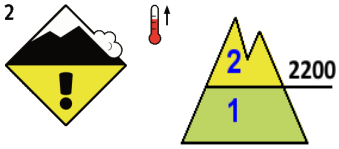  **Limitado** | **Placas de viento** **Nieve húmeda** 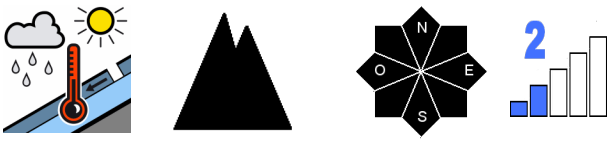  | 2026-04-13 Cotas medias |
| **Vertiente norte Cadí - Moixeró** | 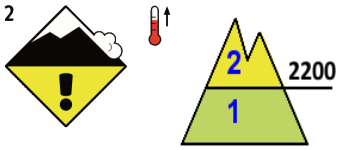  **Limitado** | **Placas de viento** **Nieve húmeda** 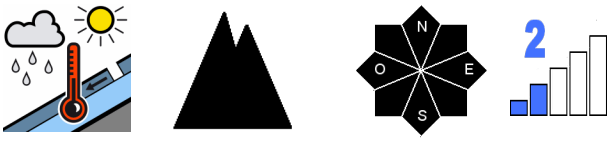  | 2026-04-13 Cotas medias |
| **Prepirineo** | 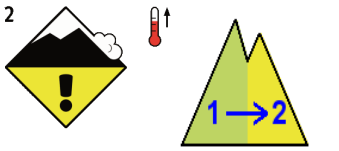  **Limitado** | **Placas de viento** **Nieve húmeda** 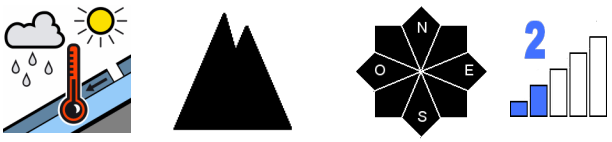  | 2026-04-13 Cotas medias |

## Estado del manto y observaciones recientes

Durante las últimas 72 h se han registrado precipitaciones débiles o localmente moderadas en todos los sectores, acumulándose unos 15-20 l/m2. Inicialmente fueron en forma líquida hasta cotas altas, bajando ayer la cota de nieve hasta los 1000 m al final del día.

La nieve reciente se ha depositado sobre un manto muy húmedo y de perfil primaveral, causado por el ambiente cálido de días previos. Las nevadas han ido acompañadas de vientos intensos de componente sur girando a norte, que han formado en cotas altas placas de viento en todas las orientaciones.


AEMET. Se autoriza la reproducción de su contenido citando la fuente.

Hay nieve esquiable por encima de 1800-2000 m en umbrías y de 2100-2300 m en solanas. Los espesores son excedentarios para la época en la mayoría de sectores: 194 cm en Lac Redón a 2247 m en el Arán-F.N.Pallaresa, 157 cm en Cadí Nord a 2143 m en el V.N Cadí-Moixeró y 78 cm en el Port del Comte a 2316 m en el Prepirineo.

## Evolución del manto y peligro de aludes para el martes, día 14

Problemas de nieve húmeda y, en cotas altas, de placas de viento.

Mañana martes, tras un rehielo nocturno efectivo, podrán formarse costras que sustenten el manto a primeras horas. No obstante, a consecuencia del aumento de la temperatura diurna y la radiación solar, en el transcurso de la jornada se esperan purgas y aludes de nieve húmeda, más probables en solanas y a partir del mediodía, e incluso se podrían producir deslizamientos basales en terrenos herbosos o de roca lisa. Por lo general, serán pequeños (riesgo de caída) o medianos (capaz de enterrar a una persona), sin descartar que alguno pudiera alcanzar un tamaño algo mayor.
En cotas altas, principalmente cerca de crestas y collados, se formaron placas de viento durante las recientes nevadas que podrán engrosarse por el transporte de nieve reciente con el viento del norte. Se estabilizarán rápidamente en laderas soleadas, pero se mantendrán frágiles en las umbrías. Su ruptura accidental podrá desencadenar aludes pequeños o localmente medianos, raramente grandes (capaz de enterrar a un grupo de personas) en zonas de mayor acumulación o si se ve afectada alguna capa débil persistente en profundidad.

## Predicción meteorológica para el martes, día 14

Poco nuboso o despejado, con cielos nubosos o muy nubosos de madrugada y últimas horas en en el Arán y divisoria fronteriza.
No se descartan precipitaciones débiles de madrugada en la divisoria fronteriza del Arán-Franja Norte Pallaresa, con la cota de nieve en 1000-1200 metros.
Temperatura mínimas sin cambios o en ligero descenso, y máximas en ligero o moderado ascenso. Heladas débiles o moderadas.
Viento moderado de componente norte, fuerte en cotas altas.

Datos en la atmósfera libre:

Altitud de la isoterma de 0 ºC: 2400 m
Altitud de la isoterma de -10 ºC: 4300 m

Viento a 1500 m: N 30 km/h
Viento a 3000 m: N 60 km/h

## Evolución para el miércoles día 15

Nivel de peligro sin cambios.

Escala europea de peligro de aludes

Débil | Limitado | Notable | Fuerte | Muy Fuerte

Problemas de aludes

Nieve reciente | Placas de viento | Capas débiles persistentes | Nieve húmeda | Deslizamientos basales | Sin problema evidente


AEMET. Se autoriza la reproducción de su contenido citando la fuente.

Nota1: Se recuerda que, siempre que haya nieve, la ausencia total de peligro no existe. Hay que tener presente que en circunstancias desfavorables, con aludes de tamaño 1 (alud pequeño o colada) y tamaño 2 (alud mediano), se pueden sufrir severos daños personales.

Nota2: Los BPA se elaboran en base a información meteorológica así como al estado del manto nivoso a través de sondeos puntuales. Se advierte a los usuarios de la variabilidad de esta información al extrapolarla a zonas extensas de montaña. Por ello, AEMET no se hace responsable de su uso para la toma de decisiones que conciernen a la seguridad personal, ni de los riesgos físicos o materiales de ellas derivadas.


AEMET. Se autoriza la reproducción de su contenido citando la fuente.