GOBIERNO DE ESPAÑA
VICEPRESIDENCIA TERCERA DEL GOBIERNO
MINISTERIO PARA LA TRANSICIÓN ECOLÓGICA Y EL RETO DEMOGRÁFICO

Boletín de información nivológica y de peligro de aludes

Pirineo Navarro y Aragonés

aemet Agencia Estatal de Meteorología

lunes, 13 de abril de 2026

Pronóstico hasta las 24 horas del martes, día 14 de abril

(Válido fuera de pistas de esquí balizadas y abiertas)

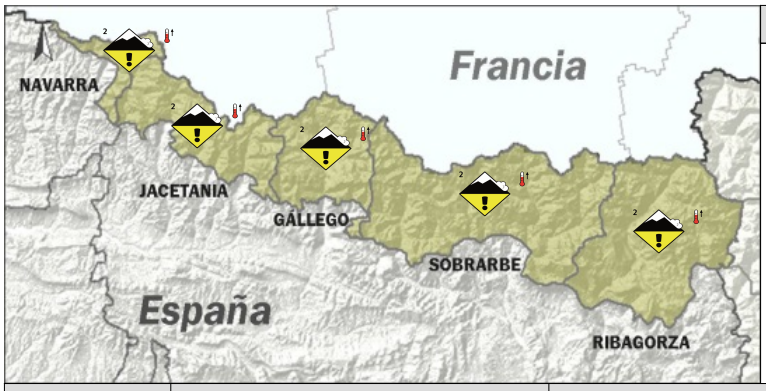

Problemas de aludes

Placas de viento

Nieve húmeda

Macizo	Peligro	Problemas de aludes, cota, orientación, tamaño	Innivación observada (m)
Navarra	2 Limitado	Placas de viento: 2200, N O E S, 2 Nieve húmeda: N O E S, 2	2026-04-13 N S Cotas medias
Jacetania	2 Limitado	Placas de viento: 2200, N O E S, 2 Nieve húmeda: N O E S, 2	2026-04-13 N S Cotas medias
Gállego	2 Limitado	Placas de viento: 2200, N O E S, 2 Nieve húmeda: N O E S, 2	2026-04-13 N S Cotas medias

AEMET. Se autoriza la reproducción de su contenido citando la fuente.

Boletín de información nivológica y de peligro de aludes

Pirineo Navarro y Aragonés

Sobrarbe	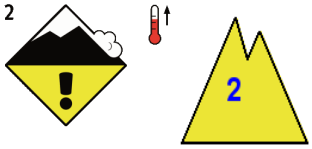 **Limitado**	**Placas de viento** **Nieve húmeda** 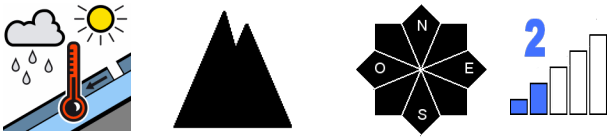	2026-04-13
Ribagorza	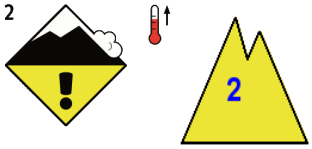 **Limitado**	**Placas de viento** 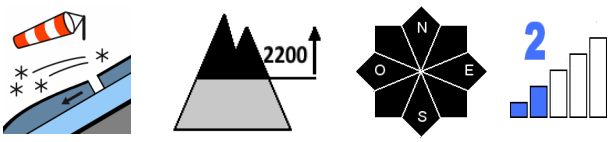 **Nieve húmeda** 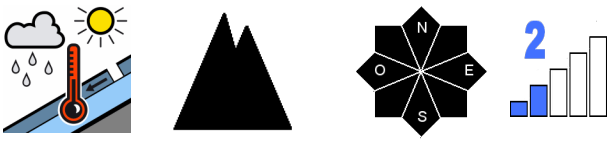	2026-04-13

Estado del manto y observaciones recientes

Durante las últimas 72 h se han registrado precipitaciones localmente moderadas en todos los sectores, acumulándose unos 20-30 l/m2. Inicialmente fueron en forma líquida hasta cotas altas, bajando ayer la cota de nieve hasta los 1000 m al final del día.
La nieve reciente se ha depositado sobre un manto muy húmedo y de perfil primaveral, causado por el ambiente cálido de días previos. Las nevadas han ido acompañadas de vientos intensos de componente sur girando a norte, que han formado en cotas altas placas de viento en todas las orientaciones.
Comienza el manto continuo en cotas medias, con espesores elevados para la época : 160 cm en Llano de la Contienda a 1749 m en el sector navarro, 120 cm en La Raca a 2276 m en la Jacetania, 150 cm en Respomuso a 2145 m en el Alto Gállego, 75 cm en Góriz a 2195 m en el Sobrarbe y 175 cm en la Renclusa a 2140 m en la Ribagorza.
En las últimas 24 h se han observado numerosos aludes pequeños, raramente medianos, en el Alto Gállego y la Ribagorza. De nieve reciente, húmeda, puntual con salida a 2500-3000 m en orientación NW, y con salida a 2250-2500 m en orientación SE.

Evolución del manto y peligro de aludes para el martes, día 14

Problemas de nieve húmeda y, en cotas altas, de placas de viento.

Mañana martes, tras un rehielo nocturno efectivo, podrán formarse costras que sustenten el manto a primeras horas. No obstante, a consecuencia del aumento de la temperatura diurna y la radiación solar, en el transcurso de la jornada se esperan purgas y aludes de nieve húmeda, más probables en solanas y a partir del mediodía, e incluso se podrían producir deslizamientos basales en terrenos herbosos o de roca lisa. Por lo general, serán pequeños (riesgo de caída) o medianos (capaz de enterrar a una persona), sin descartar que alguno pudiera alcanzar un tamaño algo mayor.

AEMET. Se autoriza la reproducción de su contenido citando la fuente.

En cotas altas, principalmente cerca de crestas y collados, se formaron placas de viento durante las recientes nevadas que podrán engrosarse por el transporte de nieve reciente con el viento del norte. Se estabilizarán rápidamente en laderas soleadas, pero se mantendrán frágiles en las umbrías. Su ruptura accidental podrá desencadenar aludes pequeños o localmente medianos, raramente grandes (capaz de enterrar a un grupo de personas) en zonas de mayor acumulación o si se ve afectada alguna capa débil persistente en profundidad.

Predicción meteorológica para el martes, día 14

Pirineo navarro:
Intervalos nubosos, con nubes bajas y medias. No se descartan algunas precipitaciones débiles en el área occidental en la segunda mitad del día, con la cota de nieve en torno a 2000 metros. Temperaturas mínimas con pocos cambios. Máximas en moderado ascenso. Heladas débiles, localmente moderadas en cotas altas. Viento moderado de componente norte con intervalos fuerte, más intenso en cotas altas.
Pirineo aragonés:
Intervalos de nubes bajas en la divisoria fronteriza, predominando los cielos poco nubosos o despejados en el resto. Temperaturas mínimas sin cambios o en ligero descenso, y máximas en ligero o moderado ascenso. Heladas débiles o moderadas. Viento moderado de componente norte, fuerte en cotas altas sin descartar rachas muy fuertes en el área oriental.

Datos en la atmósfera libre:

Altitud de la isoterma de 0 ºC: 2400 m
Altitud de la isoterma de -10 ºC: 4300 m

Viento a 1500 m: N 30 km/h
Viento a 3000 m: N 60 km/h

Evolución para el miércoles día 15

Nivel de peligro sin cambios.

(Información elaborada a partir de los datos recibidos de los refugios de Linza, Lizara, Respomuso, Panticosa, Bachimaña, Góriz, Pineta, Estós, Angel Orús, La Renclusa, Cap de Llauset y Belagua, de las estaciones de esquí de Formigal y Panticosa (lagos) y de Ordesa Pradera)

Escala europea de peligro de aludes

Débil | Limitado | Notable | Fuerte | Muy Fuerte

Problemas de aludes

Nieve reciente | Placas de viento | Capas débiles persistentes | Nieve húmeda | Deslizamientos basales | Sin problema evidente

Nota1: Se recuerda que, siempre que haya nieve, la ausencia total de peligro no existe. Hay que tener presente que en circunstancias desfavorables, con aludes de tamaño 1 (alud pequeño o colada) y tamaño 2 (alud mediano), se pueden sufrir severos daños personales.

Nota2: Los BPA se elaboran en base a información meteorológica así como al estado del manto nivoso a través de sondeos puntuales. Se advierte a los usuarios de la variabilidad de esta información al extrapolarla a zonas extensas de montaña. Por ello, AEMET no se hace responsable de su uso para la toma de decisiones que conciernen a la seguridad personal, ni de los riesgos físicos o materiales de ellas derivadas.

AEMET. Se autoriza la reproducción de su contenido citando la fuente.