Dienstag 14.04.2026

Veröffentlicht am 13.04.2026 um 17:00

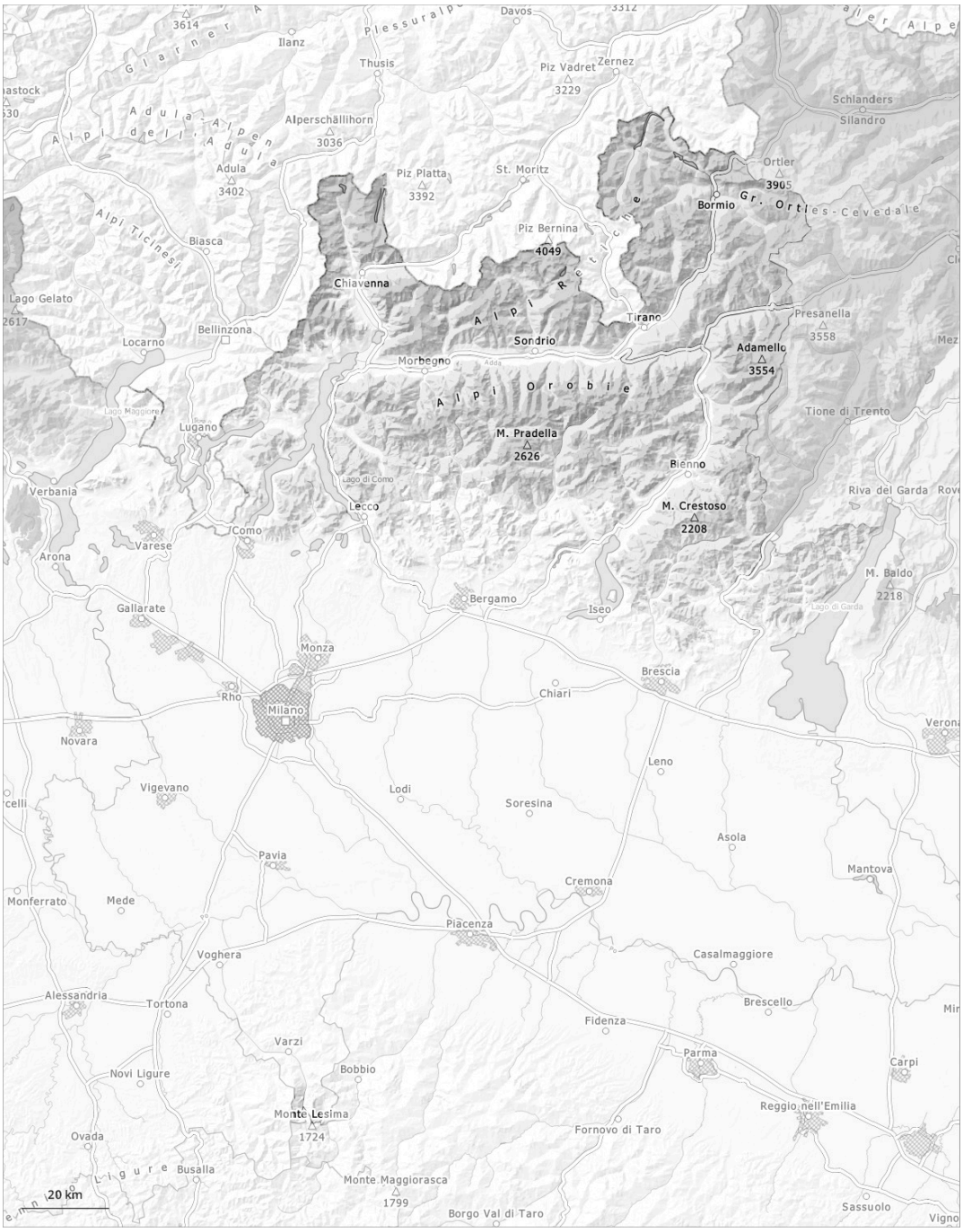

1	2	3	4	5
gering	mäßig	erheblich	groß	sehr groß

Gefahrenstufe 2 - Mäßig

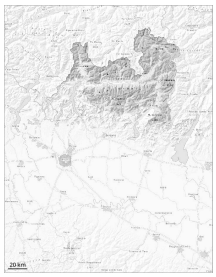

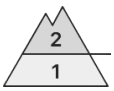

Waldgrenze

Tendenz: Lawinengefahr bleibt gleich
am Mittwoch, den 15.04.2026

Neuschnee

Waldgrenze

Nassschnee

Waldgrenze

Neu- und Triebschnee liegen auf einer recht günstigen Altschneeoberfläche.

Mit Schneefall oberhalb von rund 1800 m und mäßigem bis starkem Wind entstanden frische Triebschneeansammlungen. Die Gefahrenstellen für trockene Lawinen liegen oberhalb von rund 2500 m. Mit dem Regen steigt die Auslösebereitschaft von nassen Lawinen v.a. an steilen Schattenhängen unterhalb von rund 2500 m an.
Mittlere Lawinen sind möglich.

Schneedecke

Gefahrenmuster gm.6: lockerer schnee und wind | gm.10: frühjahrssituation

Die Schneeoberfläche konnte in der bedeckten Nacht kaum abkühlen und ist schon am Morgen aufgeweicht.
Es fiel verbreitet Schnee oberhalb von rund 1900 m.
Mit Wind entstanden im Hochgebirge leicht auslösbare Triebschneeansammlungen.
Steile Schattenhänge oberhalb von rund 2500 m: Im unteren Teil der Altschneedecke sind kantig aufgebaute Schwachschichten vorhanden.
Unterhalb von rund 1800 m liegt für Schneesport meist zu wenig Schnee.

Gefahrenstufe 1 - Gering

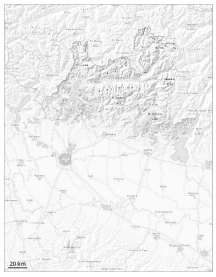

Tendenz: Lawinengefahr bleibt gleich
am Mittwoch, den 15.04.2026

Nassschnee

1800m

Es fällt verbreitet Regen bis in hohe Lagen.

Die Schneeoberfläche ist nicht gefroren und ist schon am Morgen aufgeweicht.

Schneedecke

Gefahrenmuster gm.10: frühjahrssituation

Mit Regen bis in hohe Lagen und entsteht eine teils ungünstige Lawinensituation.