Martedì 14.04.2026

Pubblicato il 13.04.2026 alle ore 17:00

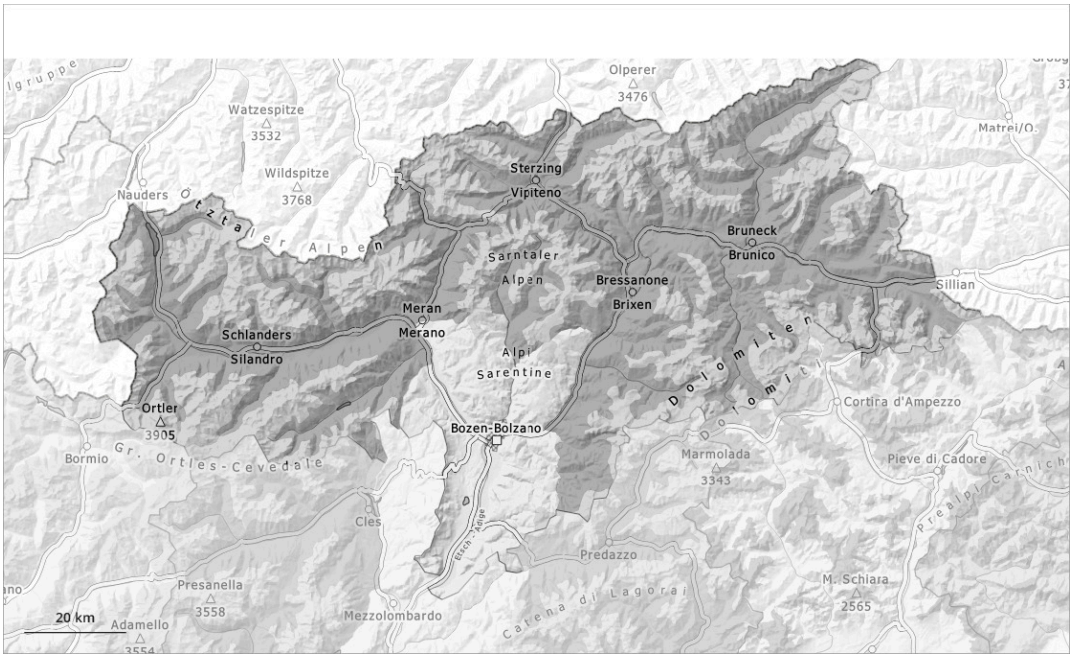

1	2	3	4	5
debole	moderato	marcato	forte	molto forte

Grado di pericolo 3 - Marcato

2500m

Tendenza: pericolo valanghe stabile
per Mercoledì il 15.04.2026

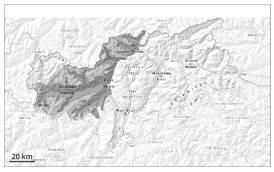

Neve bagnata

2500m

Lastrone da vento

2500m

Strati deboli persistenti

2500m

La neve bagnata è la principale fonte di pericolo. Neve ventata in alta montagna.

Il pericolo di valanghe di neve bagnata rimarrà invariato, soprattutto sui pendii ripidi esposti a ovest, nord ed est. In queste aree, sono possibili valanghe spontanee, anche di grandi dimensioni. Soprattutto nelle aree con tanta neve, nei canaloni ripidi le valanghe di neve bagnata possono a livello isolato avanzare sino alle zone non innevate. Inoltre, in alcuni punti le valanghe umide e bagnate possono subire un distacco già in seguito al passaggio di un singolo appassionato di sport invernali.

Punti pericolosi per valanghe asciutte si trovano sui pendii molto ripidi esposti a ovest, nord ed est al di sopra dei 2500 m circa. Gli accumuli di neve ventata di più recente formazione possono subire un distacco in seguito al passaggio di un singolo appassionato di sport invernali, principalmente nelle zone in prossimità delle creste, nelle conche e nei canaloni. Tali punti pericolosi sono in parte innevati e difficili da individuare. Sfavorevoli sono principalmente i punti di passaggio da poca a molta neve, (--). Le valanghe possono a livello molto isolato coinvolgere gli strati più profondi raggiungere grandi dimensioni.

Manto nevoso

Situazione tipo st.3: pioggia su neve st.6: neve a debole coesione e vento

Cadrà pioggia sino ai 2500 m. La pioggia causerà principalmente sui pendii ombreggiati ripidi una destabilizzazione all'interno del manto nevoso.

Cadranno sino a 15 cm di neve al di sopra dei 2500 m circa, localmente anche di più. Con vento a tratti forte proveniente da sud est in quota si formeranno accumuli di neve ventata in parte facilmente distaccabili.

Sui pendii ripidi esposti a ovest, nord ed est al di sopra dei 2500 m circa: Nella parte superiore del manto di neve vecchia si trovano, a livello isolato, strati fragili instabili. Nella parte basale del manto di neve vecchia si trovano strati fragili a cristalli sfaccettati.

Tendenza

Il pericolo di valanghe di neve umida e bagnata rimarrà invariato. Con il rialzo termico e l'irradiazione solare diurni, sono previste sempre più numerose valanghe spontanee, soprattutto nelle aree dove gli apporti di neve fresca sono stati considerevoli.

Grado di pericolo 3 - Marcato

2500m

Tendenza: pericolo valanghe stabile
per Mercoledì il 15.04.2026

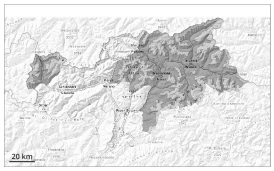

Neve bagnata

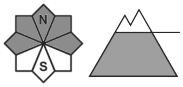

2500m

Strati deboli persistenti

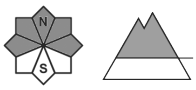

2500m

La neve bagnata è la principale fonte di pericolo. Con la pioggia, sono possibili valanghe spontanee di neve bagnata.

Il pericolo di valanghe di neve bagnata rimarrà invariato, soprattutto sui pendii molto ripidi esposti a ovest, nord ed est al di sotto dei 2500 m circa. In queste aree, sono possibili valanghe spontanee, a livello isolato anche di grandi dimensioni. Principalmente nelle aree con tanta neve, nei canaloni ripidi le valanghe di neve bagnata possono a livello isolato avanzare sino alle zone non innevate. Inoltre, in alcuni punti le valanghe umide e bagnate possono subire un distacco già in seguito al passaggio di un singolo appassionato di sport invernali.

Isolati punti pericolosi per valanghe asciutte si trovano sui pendii ombreggiati molto ripidi al di sopra dei 2500 m circa. Tali punti pericolosi sono difficili da individuare.
Inoltre in alta montagna gli accumuli di neve ventata di più recente formazione possono a livello isolato subire un distacco, principalmente sui pendii ombreggiati vicino alle creste. Gli accumuli di neve ventata sono per lo più piccoli.

Manto nevoso

Situazione tipo st.3: pioggia su neve | st.1: strato debole persistente basale

Cadrà pioggia sino ai 2500 m. La pioggia causerà principalmente sui pendii ombreggiati ripidi una destabilizzazione all'interno del manto nevoso.

Sui pendii ripidi esposti a ovest, nord ed est al di sopra dei 2500 m circa: Nella parte superiore del manto di neve vecchia si trovano, a livello isolato, strati fragili instabili. Nella parte basale del manto di neve vecchia si trovano strati fragili a cristalli sfaccettati.

Cadrà neve al di sopra dei 2500 m circa. Con vento a tratti forte proveniente da sud est in alta montagna si sono formati accumuli di neve ventata di piccole dimensioni.

Tendenza

Il pericolo di valanghe di neve bagnata rimarrà invariato.

Grado di pericolo 2 - Moderato

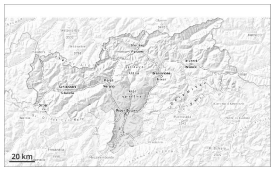

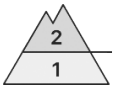

2000m

Tendenza: pericolo valanghe in diminuzione
per Mercoledì il 15.04.2026

Neve bagnata

2000m

La neve bagnata è la principale fonte di pericolo. Con la pioggia, sono possibili valanghe spontanee di neve bagnata.

Il pericolo di valanghe di neve umida e bagnata sarà superiore già al mattino. Con la pioggia, la probabilità di distacco di valanghe di neve bagnata aumenterà soprattutto sui pendii ombreggiati ripidi. Sono possibili al più isolate valanghe spontanee, anche di medie dimensioni.

Manto nevoso

Situazione tipo st.10: situazione primaverile st.1: strato debole persistente basale

La superficie del manto nevoso non riuscirà praticamente quasi a rigelarsi e risulterà ammorbidita già al mattino. Cadrà pioggia sino ad alta quota. La pioggia causerà principalmente sui pendii ombreggiati ripidi una destabilizzazione all'interno del manto nevoso.

Tendenza

Con l'attenuarsi delle precipitazioni, calo del pericolo di valanghe di neve bagnata.