ICGC Institut Cartogràfic i Geològic de Catalunya

Servei Meteorològic de Catalunya meteo.cat

Boletín de peligro de aludes para el Pirineo de Catalunya
Del 13/04/2026 al 14/04/2026

(Válido fuera pistas de esquí y zonas no controladas)

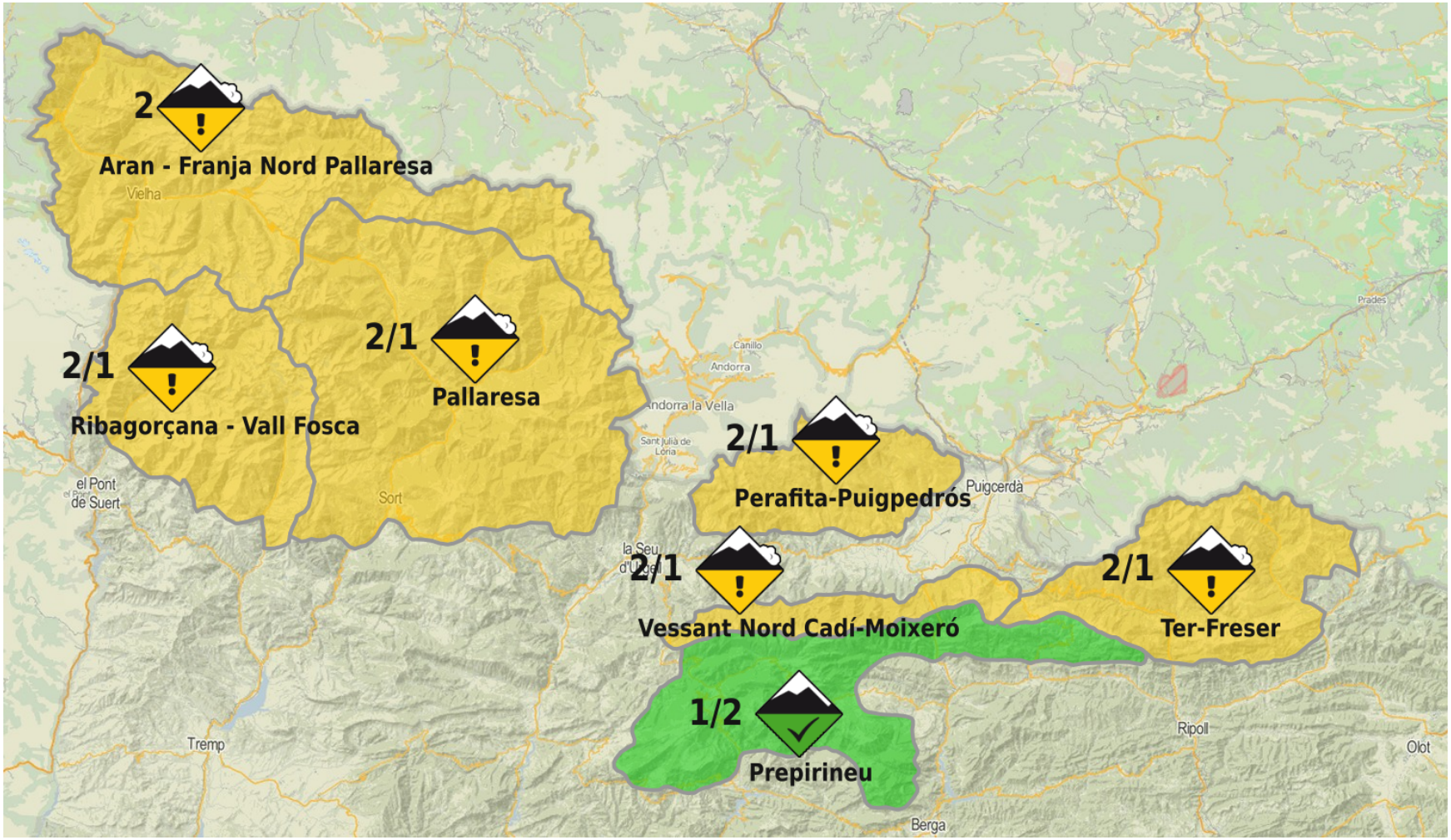

5 MUY FUERTE	4 FUERTE	3 NOTABLE	2 LIMITADO	1 DÉBIL

ICGC Institut Cartogràfic i Geològic de Catalunya

meteo.cat Servei Meteorològic de Catalunya

Boletín de peligro de aludes Aran - Franja Nord Pallaresa Del 13/04/2026 al 14/04/2026

(Válido fuera pistas de esquí y zonas no controladas)

LIMITADO (2).

Situación primaria

Nieve venteada

Distribución

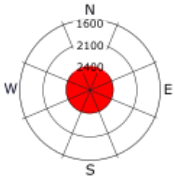

Tamaño

Origen

Tendencia

Situación secundaria

Nieve húmeda

Distribución

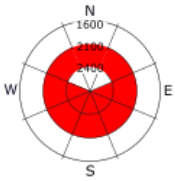

Tamaño

Origen

Tendencia

Estado del manto nivoso

Durante el fin de semana, gran parte de la precipitación ha estado en forma de agua hasta 2.500 m; ha dejado un grosor de unos 5-10 cm por encima de 2.200 m. Se espera alguna avalancha de placa de tamaño 1 (pequeña, suficiente para arrastrarnos) bajo collados y crestas en cotas altas en cualquier orientación, localmente de tamaño 2 (mediano, con capacidad de cubrir a una persona) en la Franja Norte de la Pallaresa donde ha soplado viento del N. Internamente el manto durante el lunes aún está bastante húmedo por la lluvia. Durante el resto del lunes todavía caerá algún alud húmedo junto a sectores rocosos de tamaño 2 (mediano). El martes por la mañana ya encontraremos un manto rehelado con algo de nieve reciente encima y placas de viento en cotas altas. Hay que fijarse en la localización de estas placas de viento en cotas altas; en cotas medias y bajas a medida que avance la jornada controlad la penetración de la bota o el esquí en la nieve húmeda.

Distribución del manto nivoso

Hay nieve en el suelo por encima de 1.800-1.900 m en umbrías y de 2.000 m en solanas. Los espesores a unos 2.200 m rondan los 140-220 cm. Los valores están muy por encima de los normales por la época.

Tendencia para las próximas 48-72h

En los próximos días predominará la fusión de día y el rehielo bastante potente de noche. El manto estará endurecido y estable por las mañanas, con purgas de nieve húmeda desde media mañana. Evolución del peligro: SIN CAMBIOS

El próximo boletín será emitido el día 2026-04-14

5 MUY FUERTE	4 FUERTE	3 NOTABLE	2 LIMITADO	1 DÉBIL

EAWS EUROPEAN AVALANCHE WARNING SERVICES

ICGC Institut Cartogràfic i Geològic de Catalunya

Servei Meteorològic de Catalunya

Boletín de peligro de aludes Ribagorçana - Vall Fosca Del 13/04/2026 al 14/04/2026

(Válido fuera pistas de esquí y zonas no controladas)

LIMITADO (2) por encima de 2.400 m.
DÉBIL (1) por debajo.

Situación primaria

Nieve venteada

Distribución

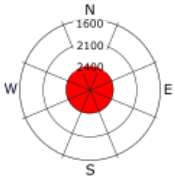

Tamaño

Origen

Tendencia

Situación secundaria

Nieve húmeda

Distribución

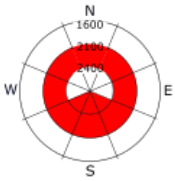

Tamaño

Origen

Tendencia

Estado del manto nivoso

Durante el fin de semana, gran parte de la precipitación ha estado en forma de agua hasta cotas altas; ha dejado un grosor de unos 5 cm por encima de 2.200-2.300 m y unos 10-15 cm en las cotas más altas. Se espera algún alud de placa de tamaño 1 (pequeño, suficiente para arrastrarnos) bajo collados y crestas en cotas altas. Internamente el manto durante el lunes todavía está bastante húmedo por la lluvia, pero progresivamente se irá rehelando por las bajas temperaturas. Durante el resto del lunes todavía podría caer algún alud de fusión junto a sectores rocosos, localmente de tamaño 2 (mediano, con capacidad de cubrir a una persona). El martes por la mañana ya encontraremos un manto rehelado con algo de nieve reciente encima y alguna placa de viento en las cotas más altas. Hay que fijarse en la localización de estas placas de viento en cotas altas; en cotas medias y bajas a medida que avance la jornada controlad la penetración de la bota o el esquí en la nieve húmeda.

Distribución del manto nivoso

Hay nieve por encima de 1.800-2.000 m pero esquiable en N por encima de 1.900 m y de 2.300 m en S. Prácticamente no han variado los grosores de nieve en el suelo. Alcanzan los 80-100 cm a unos 2.200 m, con frecuentes deflaciones y acumulaciones por encima del nivel del bosque. Estos valores están algo por debajo de los normales para la época.

Tendencia para las próximas 48-72h

En los próximos días predominará la fusión de día y el rehielo bastante potente de noche. El manto estará endurecido y estable por las mañanas, con purgas de nieve húmeda desde media mañana. Evolución del peligro: SIN CAMBIOS

El próximo boletín será emitido el día 2026-04-14

5 MUY FUERTE	4 FUERTE	3 NOTABLE	2 LIMITADO	1 DÉBIL

EAWS EUROPEAN AVALANCHE WARNING SERVICES

ICGC Institut Cartogràfic i Geològic de Catalunya

Servei Meteorològic de Catalunya

Boletín de peligro de aludes Pallaresa
Del 13/04/2026 al 14/04/2026

(Válido fuera pistas de esquí y zonas no controladas)

LIMITADO (2) por encima de 2.400 m.
DÉBIL (1) por debajo.

Situación primaria

Nieve venteada

Distribución

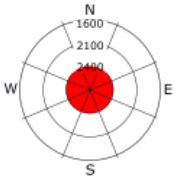

Tamaño

Origen

Tendencia

Situación secundaria

Nieve húmeda

Distribución

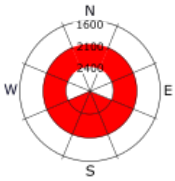

Tamaño

Origen

Tendencia

Estado del manto nivoso

Durante el fin de semana, gran parte de la precipitación ha estado en forma de agua hasta cotas altas; ha dejado un grosor de unos 5 cm por encima de 2.200-2.300 m y unos 10-15 cm en las cotas más altas. Se espera algún alud de placa de tamaño 1 (pequeño, suficiente para arrastrarnos) bajo collados y crestas en cotas altas. Internamente el manto durante el lunes todavía está bastante húmedo por la lluvia, pero progresivamente se irá rehelando por las bajas temperaturas. Durante el resto del lunes todavía podría caer algún alud de fusión junto a sectores rocosos, localmente de tamaño 2 (mediano, con capacidad de cubrir a una persona). El martes por la mañana ya encontraremos un manto rehelado con algo de nieve reciente encima y alguna placa de viento en las cotas más altas. Hay que fijarse en la localización de estas placas de viento en cotas altas; en cotas medias y bajas a medida que avance la jornada controlad la penetración de la bota o el esquí en la nieve húmeda.

Distribución del manto nivoso

Hay nieve por encima de 1.800-2.000 m pero esquiable en N por encima de 1.900 m y de 2.300 m en S. Prácticamente no han variado los grosores de nieve en el suelo. Alcanzan los 80-100 cm a unos 2.200 m, con frecuentes deflaciones y acumulaciones por encima del nivel del bosque.

Tendencia para las próximas 48-72h

En los próximos días predominará la fusión de día y el rehielo bastante potente de noche. El manto estará endurecido y estable por las mañanas, con purgas de nieve húmeda desde media mañana. Evolución del peligro: SIN CAMBIOS

El próximo boletín será emitido el día 2026-04-14

5 MUY FUERTE	4 FUERTE	3 NOTABLE	2 LIMITADO	1 DÉBIL

EAWS EUROPEAN AVALANCHE WARNING SERVICES

ICGC Institut Cartogràfic i Geològic de Catalunya

Servei Meteorològic de Catalunya

Boletín de peligro de aludes Perafita-Puigpedrós Del 13/04/2026 al 14/04/2026

(Válido fuera pistas de esquí y zonas no controladas)

LIMITADO (2) por encima de 2.400 m.
DÉBIL (1) por debajo.

Situación primaria

Nieve venteada

Distribución

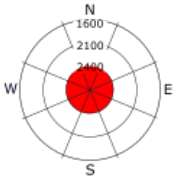

Tamaño

Origen

Tendencia

Situación secundaria

Nieve húmeda

Distribución

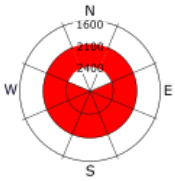

Tamaño

Origen

Tendencia

Estado del manto nivoso

Durante el fin de semana, gran parte de la precipitación ha estado en forma de agua hasta cotas altas; ha dejado un grosor de unos 5 cm por encima de 2.200-2.300 m y unos 10-15 cm en las cotas más altas. Se espera algún alud de placa de tamaño 1 (pequeño, suficiente para arrastrarnos) bajo collados y crestas en cotas altas. Internamente el manto durante el lunes todavía está bastante húmedo por la lluvia, pero progresivamente se irá rehelando por las bajas temperaturas. Durante el resto del lunes todavía podría caer algún alud de fusión junto a sectores rocosos, localmente de tamaño 2 (mediano, con capacidad de cubrir a una persona). El martes por la mañana ya encontraremos un manto rehelado con algo de nieve reciente encima y alguna placa de viento en las cotas más altas. Hay que fijarse en la localización de estas placas de viento en cotas altas; en cotas medias y bajas a medida que avance la jornada controlad la penetración de la bota o el esquí en la nieve húmeda.

Distribución del manto nivoso

Hay nieve por encima de 1.800 a 2.000 m. Prácticamente no han variado los grosores de nieve en el suelo. Alcanzan los 50-90 cm a unos 2.300 m, con frecuentes deflaciones y acumulaciones por encima del nivel del bosque. Estos valores son los normales para la época.

Tendencia para las próximas 48-72h

En los próximos días predominará la fusión de día y el rehielo bastante potente de noche. El manto estará endurecido y estable por las mañanas, con purgas de nieve húmeda desde media mañana. Evolución del peligro: SIN CAMBIOS

El próximo boletín será emitido el día 2026-04-14

5 MUY FUERTE	4 FUERTE	3 NOTABLE	2 LIMITADO	1 DÉBIL

EAWS EUROPEAN AVALANCHE WARNING SERVICES

ICGC Institut Cartogràfic i Geològic de Catalunya

Servei Meteorològic de Catalunya meteo.cat

Boletín de peligro de aludes Vessant Nord Cadí-Moixeró Del 13/04/2026 al 14/04/2026

(Válido fuera pistas de esquí y zonas no controladas)

LIMITADO (2) por encima de 2.200 m.
DÉBIL (1) por debajo.

Situación primaria

Nieve venteada

Distribución

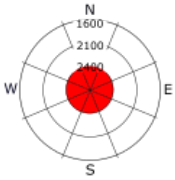

Tamaño

Origen

Tendencia

Situación secundaria

Nieve húmeda

Distribución

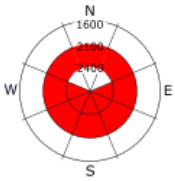

Tamaño

Origen

Tendencia

Estado del manto nivoso

Durante el fin de semana, gran parte de la precipitación ha estado en forma de agua hasta cotas altas; ha dejado un grosor de unos 10-15 cm por encima de 2.200-2.300 m. Se espera algún alud de placa de tamaño 1 (pequeño, suficiente para arrastrarnos) bajo collados y crestas en cotas altas en cualquier orientación. Internamente el manto durante el lunes todavía está bastante húmedo por la lluvia, pero progresivamente se irá rehelando por las bajas temperaturas. Durante el resto del lunes todavía podría caer algún alud de fusión junto a sectores rocosos, localmente de tamaño 2 (mediano, con capacidad de cubrir a una persona). El martes por la mañana ya encontraremos un manto rehelado con algo de nieve reciente encima y alguna placa de viento en las cotas más altas. Hay que fijarse en la localización de estas placas de viento en cotas altas; en cotas medias y bajas a medida que avance la jornada controlad la penetración de la bota o el esquí en la nieve húmeda.

Distribución del manto nivoso

Hay nieve por encima de 1.800 m. Prácticamente no han variado los grosores de nieve en el suelo. Alcanzan los 130-150 cm a unos 2.200 m, con frecuentes deflaciones y acumulaciones por encima del nivel del bosque. Estos valores están muy por encima de los normales para la época.

Tendencia para las próximas 48-72h

En los próximos días predominará la fusión de día y el rehielo bastante potente de noche. El manto estará endurecido y estable por las mañanas, con purgas de nieve húmeda desde media mañana. Evolución del peligro: SIN CAMBIOS

El próximo boletín será emitido el día 2026-04-14

5 MUY FUERTE	4 FUERTE	3 NOTABLE	2 LIMITADO	1 DÉBIL

EAWS EUROPEAN AVALANCHE WARNING SERVICES

ICGC Institut Cartogràfic i Geològic de Catalunya

Servei Meteorològic de Catalunya

Boletín de peligro de aludes Prepirineu
Del 13/04/2026 al 14/04/2026

(Válido fuera pistas de esquí y zonas no controladas)

DÉBIL (1). LIMITADO (2) a partir de mediodía.

Situación primaria

Nieve húmeda

Distribución

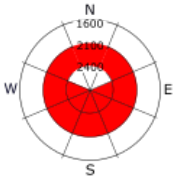

Tamaño

Origen

Tendencia

Situación secundaria

Nieve venteada

Distribución

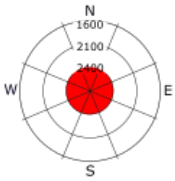

Tamaño

Origen

Tendencia

Estado del manto nivoso

Gran parte de la precipitación del domingo ha estado en forma de agua hasta las cimas; al final ha dejado un grosor de unos 5-10 cm en las cotas más altas. Se espera algún alud de placa de tamaño 1 (pequeño, suficiente para arrastrarnos) bajo collados y crestas en cotas altas en cualquier orientación. Internamente el manto durante el lunes todavía está bastante húmedo por la lluvia, pero progresivamente se irá rehelando por las bajas temperaturas. Durante el resto del lunes todavía podría caer algún alud de fusión junto a sectores rocosos, localmente de tamaño 2 (mediano, con capacidad de cubrir a una persona). El martes por la mañana ya encontraremos un manto rehelado con algo de nieve reciente encima y alguna placa de viento en las cotas más altas. Hay que fijarse en la localización de estas placas de viento en cotas altas; en cotas medias y bajas a medida que avance la jornada controle la penetración de la bota o el esquí en la nieve húmeda.

Distribución del manto nivoso

Hay nieve por encima de 1.900-2.000 m en N y de 2.100 m en S. Prácticamente no han variado los grosores de nieve en el suelo. Alcanzan los 60-80 cm a unos 2.200 m, con frecuentes deflaciones y acumulaciones por encima del nivel del bosque.

Tendencia para las próximas 48-72h

En los próximos días predominará la fusión de día y el rehielo bastante potente de noche. El manto estará endurecido y estable por las mañanas, con purgas de nieve húmeda desde media mañana. Evolución del peligro: SIN CAMBIOS

El próximo boletín será emitido el día 2026-04-14

5 MUY FUERTE	4 FUERTE	3 NOTABLE	2 LIMITADO	1 DÉBIL

EAWS EUROPEAN AVALANCHE WARNING SERVICES

ICGC Institut Cartogràfic i Geològic de Catalunya

Servei Meteorològic de Catalunya

Boletín de peligro de aludes Ter-Freser
Del 13/04/2026 al 14/04/2026

(Válido fuera pistas de esquí y zonas no controladas)

LIMITADO (2) por encima de 2.200 m.
DÉBIL (1) por debajo.

Situación primaria

Nieve venteada

Distribución

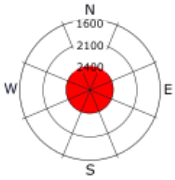

Tamaño

Origen

Tendencia

Situación secundaria

Nieve húmeda

Distribución

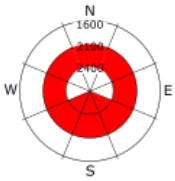

Tamaño

Origen

Tendencia

Estado del manto nivoso

Durante el fin de semana, gran parte de la precipitación ha estado en forma de agua hasta cotas altas; ha dejado un grosor de unos 10 cm por encima de 2.200-2.300 m. Se espera algún alud de placa de tamaño 1 (pequeño, suficiente para arrastrarnos) en cotas altas en cualquier orientación, localmente de tamaño 2 (mediano, con capacidad de cubrir una persona) en orientaciones S. Internamente el manto durante el lunes todavía está bastante húmedo por la lluvia, pero progresivamente se irá rehelando por las bajas temperaturas. Durante el resto del lunes todavía podría caer algún alud de fusión junto a sectores rocosos, localmente de tamaño 2 (mediano). El martes por la mañana ya encontraremos un manto rehelado con algo de nieve reciente encima y alguna placa de viento en las cotas más altas. Hay que fijarse en la localización de estas placas de viento en cotas altas; en cotas medias y bajas a medida que avance la jornada controlad la penetración de la bota o el esquí en la nieve húmeda.

Distribución del manto nivoso

Hay nieve por encima de 1.800. Prácticamente no han variado los grosores de nieve en el suelo. Alcanzan los 50-80 cm a unos 2.100 m, y más de 130-190 cm por encima de 2.400 m, con frecuentes deflaciones y acumulaciones por encima del nivel del bosque. Estos valores están por encima de la media para la época.

Tendencia para las próximas 48-72h

En los próximos días predominará la fusión de día y el rehielo bastante potente de noche. El manto estará endurecido y estable por las mañanas, con purgas de nieve húmeda desde media mañana. Evolución del peligro: SIN CAMBIOS

El próximo boletín será emitido el día 2026-04-14

5 MUY FUERTE	4 FUERTE	3 NOTABLE	2 LIMITADO	1 DÉBIL

EAWS EUROPEAN AVALANCHE WARNING SERVICES