BUTLLETÍ DEL PERILL D'ALLAUS DEL PRINCIPAT D'ANDORRA

Servei meteorològic nacional
Principat d'Andorra

Elaborat el 13/04/2026 16:00
Propera actualització 14/04/2026 a les 16h

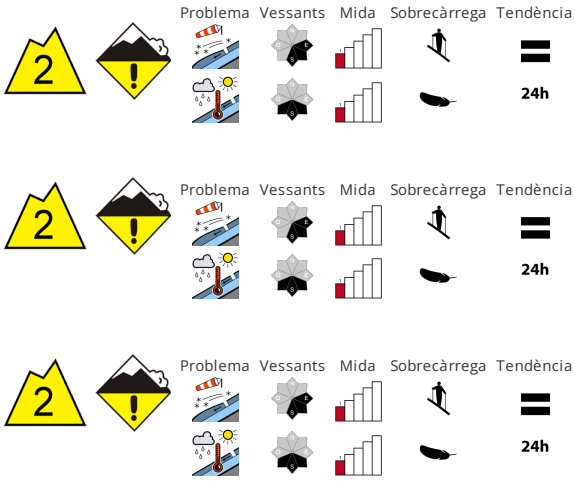

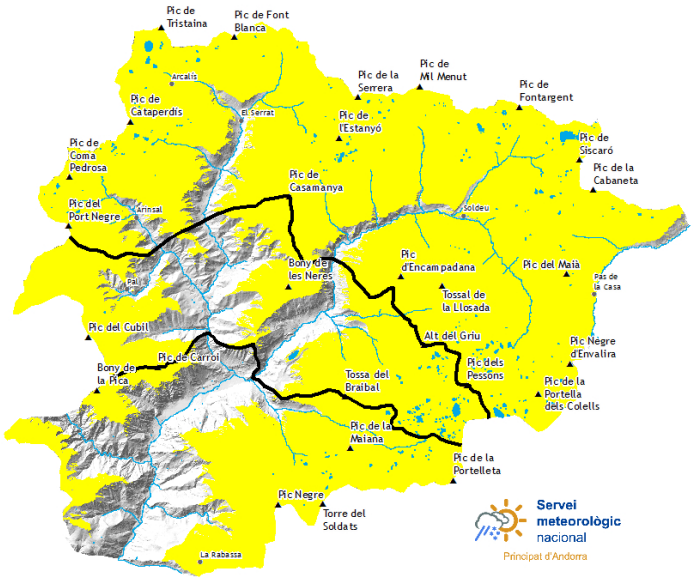

ESTABILITAT DEL MANTELL NIVAL

La mica de neu recent i les plaques de vent a vegades grans poden fàcilment desencadenar-se de manera natural o accidental en vessants inclinats orientats a est, sud-est i sud. Amb l'augment de la temperatura diürna i la radiació solar, són probables purgues i allaus de neu humida de mida petita i, localment, mitjana. A més, són possibles algunes allaus de lliscament basal. Els indrets perillosos són fàcils de reconèixer.

QUALITAT DE LA NEU

La capa de neu recent és majoritàriament estable, amb una superfície solta. Els gruixos de neu varien molt per la influència del vent. En el transcurs de la jornada la radiació solar causarà una progressiva humidificació del mantell de neu als vessants assolellats. Evitar les zones amb esquerdes de lliscament basal.

GRUIXOS DEL MANTELL NIVAL FORA DE PISTA

Zona nord		Gruix neu		
Mantell Nival		1500m	2000m	2500m
N	1600 m	0 cm	150 cm	250 cm
S	1800 m	0 cm	100 cm	180 cm

Zona centre		Gruix neu		
Mantell Nival		1500m	2000m	2500m
N	1600 m	0 cm	120 cm	160 cm
S	1800 m	0 cm	60 cm	120 cm

Zona sud		Gruix neu		
Mantell Nival		1500m	2000m	2500m
N	1600 m	0 cm	120 cm	160 cm
S	1800 m	0 cm	60 cm	120 cm

Govern d'Andorra

EAWS EUROPEAN AVALANCHE WARNING SERVICES

Aquest butlletí ha estat elaborat seguint les normes i recomanacions de l'**European Avalanche Warning Services**, del qual el **Servei meteorològic Nacional** n'és membre

BUTLLETÍ DEL PERILL D'ALLAUS DEL PRINCIPAT D'ANDORRA

Servei meteorològic nacional
Principat d'Andorra

Informació detallada per espais naturals protegits

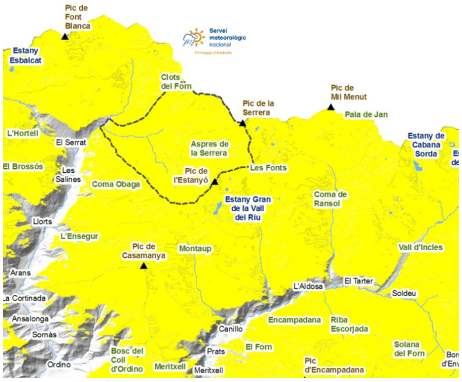

SORTENY

Després de la nevada del vespre de diumenge, amb neu a totes les cotes del Parc Natural i els seus accessos com Ransol, esperem que el sol humidifiqui la neu i purgui els vessants assolellats. Tot i així, als cims fronterers amb França, com la Serrera, encara quedarà nuvolositat residual. A cotes baixes el vent ha deixat a la vista la neu vella tacada pel fang de la pluja de diumenge al matí i aquesta s´ha regelat.

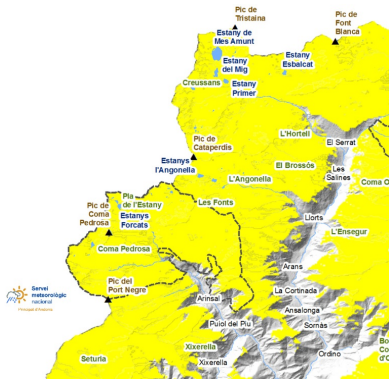

COMAPEDROSA

Nuvolositat residual a l´extrem nord del Parc Natural, però les clarianes guanyaran protagonisme. La neu nova s´humidificarà, sobretot a cotes baixes i als vessants sud i es compactarà. Als vessants més inclinats baixaran purgues de neu humida. A primera hora, amb la neu encara dura a cotes baixes, serà més difícil i tècnic circular per cotes mitges que per les cotes altes, on hi ha més neu recent.

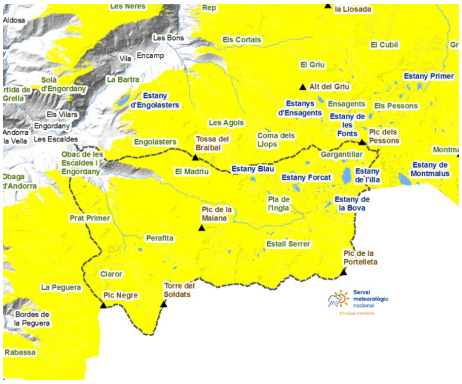

MADRIU-PERAFITA-CLAROR

El sol estabilitzarà el mantell amb la seva compactació, però durant el dia esperem purgues als vessants sud. Serà més segur circular per la neu marró i dura per evitar les plaques de vent.

Govern d'Andorra

EAWS
EUROPEAN AVALANCHE WARNING SERVICES

Aquest butlletí ha estat elaborat seguint les normes i recomanacions de l'**European Avalanche Warning Services**, del qual el **Servei meteorològic Nacional** n'és membre

BUTLLETÍ DEL PERILL D'ALLAUS DEL PRINCIPAT D'ANDORRA

Servei meteorològic nacional
Principat d'Andorra

Gruixos de neu nova dels darrers dies (de les últimes 24h mesurat a les 06:00h UTC)

	09/04/2026	10/04/2026	11/04/2026	12/04/2026
FEDA (Central)	0 cm	0 cm	0 cm	0 cm
Engolasters - FEDA	0 cm	0 cm	0 cm	0 cm
Bony de les Neres	0 cm	0 cm	0 cm	4 cm
Sorteny	0 cm	0 cm	0 cm	0 cm
Les Fonts d'Arinsal	0 cm	0 cm	0 cm	11 cm
Aixàs	0 cm	0 cm	0 cm	0 cm
Perafita	0 cm	0 cm	0 cm	10 cm
Tossa Espiolets	0 cm	0 cm	0 cm	8 cm
Grau Roig - FEDA	0 cm	0 cm	0 cm	3 cm
Fontverd	0 cm	0 cm	0 cm	4 cm
Ransol - FEDA	0 cm	0 cm	0 cm	0 cm
Setúria	0 cm	0 cm	0 cm	5 cm
Caborreu	0 cm	0 cm	0 cm	0 cm
La Solana	0 cm	0 cm	0 cm	10 cm
Coll Pa	0 cm	0 cm	0 cm	17 cm
Envalira Antenes	0 cm	0 cm	0 cm	0 cm
Vall del Riu FEDA	0 cm	0 cm	0 cm	0 cm