MINISTERO DELLA DIFESA

meteomont
Servizio Nazionale di previsione neve e valanghe

EAWS EUROPEAN AVALANCHE WARNING SERVICES

CARABINIERI

## ALPI PENNINE

Bollettino Valanghe N. 404/2026 del 13/04/2026 ore 14.00
Validità 48 ore prossima emissione 14/04/2026

**A cura del Servizio METEOMONT dell'ARMA dei CARABINIERI**
**In collaborazione con Servizio Meteorologico dell'Aeronautica militare**

## SITUAZIONE alle 14:00 del 13/04/2026

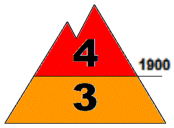


**SITUAZIONE TIPO: neve a debole coesione e vento.**




**SITUAZIONE TIPO: pioggia su neve.**

| Quota neve (mslm) | Nord | Sud |
|---|---|---|
| | 1700 | 1800 - 1700 |

| Altezza Neve (cm) | Neve al suolo | Neve Fresca | Quota (mslm) |
|---|---|---|---|
| | 167 | 031 | 2820 |
| | 154 | 044 | 2075 |

**VALANGHE OSSERVATE: -.**

## PREVISIONI 14/04/2026

# GRADO DI PERICOLO: FORTE 4

## SITUAZIONE TIPO: neve a debole coesione e vento.

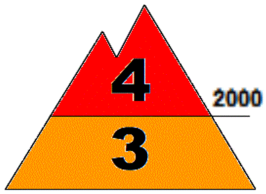





## SITUAZIONE TIPO: pioggia su neve.

**MANTO NEVOSO: La stabilità del manto nevoso è molto scarsa su molti punti (aree) per tutte le esposizioni al di sopra di 2000 mslm, possibili valanghe di dimensioni grandi.**
**La stabilità del manto nevoso è molto scarsa su alcuni punti (aree) per versanti da ovest a est al di sotto di 2000 mslm, possibili valanghe di dimensioni grandi.**

## AVVERTENZE

In considerazioni delle avverse condizioni meteorologiche e dei rilevanti cumuli di neve fresca, sono assolutamente da evitare le attività escursionistiche al di fuori delle piste battute e segnalate.

## SCALA EUROPEA DEL GRADO DI PERICOLO VALANGHE

## LEGENDA PROBLEMA

**Bollettino realizzato su scala sinottica-regionale (standard EAWS). La sua valutazione non può escludere in alcun modo la necessità di una seria e capace valutazione locale del pericolo (singolo pendio) che può essere anche sensibilmente diverso. Le previsioni meteorologiche sono relative all'orario UTC (per l'Italia +1 in inverno e +2 in estate).**

**Bollettino sottoposto a processi di: Acquisizione e controllo del C-Sifa e della rete di Osservatori e Esperti - Validazione del Previsore di turno - Certificazione della Sezione Meteomont.**

MINISTERO DELLA DIFESA

meteomont
Servizio Nazionale di previsione neve e valanghe

EAWS EUROPEAN AVALANCHE WARNING SERVICES

CARABINIERI

# ALPI PENNINE

## PREVISIONE METEO

| Quota | | 14/04/2026 h6:00 | 14/04/2026 h12:00 | 14/04/2026 h18:00 |
|---|---|---|---|---|
| 1000 | Venti | 02 nodi da N-Ovest | 01 Nodi da S-Est | 02 Nodi da S-Est |
| | Temperature | +06 °C | +08 °C | +07 °C |
| | Temp.percepita | 6 °C | 8 °C | 7 °C |
| 2000 | Venti | 01 Nodi da Est | 01 Nodi da Nord | 02 Nodi da Est |
| | Temperature | +03 °C | +04 °C | +04 °C |
| | Temp.percepita | 3 °C | 4 °C | 4 °C |
| 3000 | Venti | 03 Nodi da Nord | 02 Nodi da N-Est | 03 Nodi da N-Est |
| | Temperature | -03 °C | -02 °C | -03 °C |
| | Temp.percepita | -5 °C | -2 °C | -5 °C |
| Zero termico | | 2400-2600 m. | 2600-2800 m. | 2500-2700 m. |
| Fenomeno | | — | | |
| Stato del cielo | | | | |

## LEGENDA FENOMENI

— Assenza Fenomeni · Nebbia · Foschia · Pioggia debole · Pioggia moderata · Pioggia forte · Temporali

Nevicata debole · Nevicata moderata · Nevicata forte

## STATO DEL CIELO

Sereno · Poco nuvoloso · Nuvoloso · Molto nuvoloso · Coperto

## Parametri meteonivometrici registrati presso i campi di rilevamento il 13/04/2026.

| Località | Comune | Quota (m.s.l.m.) | Altezza neve (cm) | Neve caduta nelle 24 ore (cm) | Temp. Min (°C) | Temp. Max (°C) | Condizioni del tempo |
|---|---|---|---|---|---|---|---|
| OPACO DI PECETTO | Macugnaga (VB) | 1330 | 0 | 0 | N.P. | N.P. | Pioggia debole continua |

**(*) Rilievi fuori campo**

**L'INFORMAZIONE E' PREVENZIONE - LEGGI L'ATTUALE GRADO DI PERICOLO VALANGHE!**

**IL CAPO DEL CENTRO NAZIONALE METEOMONT**
**(Ten. Col. RFI Emanuela Gini)**
**FIRMA AUTOGRAFA OMESSA AI SENSI**
**DELL'ART.3 DEL D.LGS N.39/1993**