MINISTERO DELLA DIFESA

meteomont
Servizio Nazionale di previsione neve e valanghe

EAWS EUROPEAN AVALANCHE WARNING SERVICES

CARABINIERI

AERONAUTICA MILITARE SERVIZIO METEOROLOGICO

## GRAN SASSO OVEST

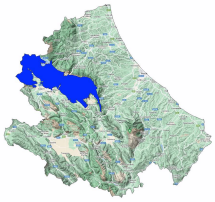

Bollettino Valanghe N. 392/2026 del 12/04/2026 ore 14.00
Validità 48 ore prossima emissione 13/04/2026

**A cura del Servizio METEOMONT dell'ARMA dei CARABINIERI**
**In collaborazione con Servizio Meteorologico dell'Aeronautica militare**

## SITUAZIONE alle 14:00 del 12/04/2026

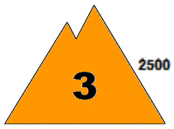


**SITUAZIONE TIPO: passaggio da poca a molta neve.**




**SITUAZIONE TIPO: situazione primaverile.**

| Quota neve (mslm) | Nord | Sud |
|---|---|---|
| | 1200 - 1300 | 1400 - 1500 |

| Altezza Neve (cm) | Neve al suolo | Neve Fresca | Quota (mslm) |
|---|---|---|---|
| | 360 | 000 | 2565 |
| | 000 | 000 | 1400 |

**VALANGHE OSSERVATE: Nessuna valanga.**

## PREVISIONI 13/04/2026

# GRADO DI PERICOLO: MARCATO 3

## SITUAZIONE TIPO: passaggio da poca a molta neve.

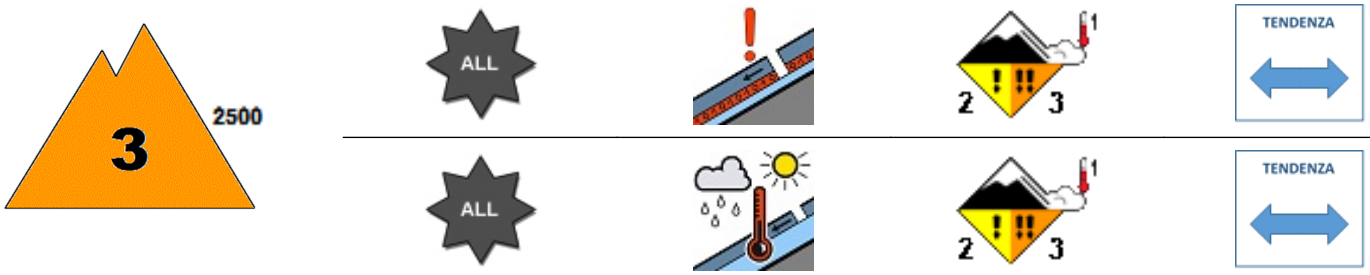


## SITUAZIONE TIPO: situazione primaverile.

**MANTO NEVOSO: La stabilità del manto nevoso è scarsa su alcuni punti (aree) per tutte le esposizioni al di sopra di 2500 mslm, possibili valanghe di dimensioni grandi.**
**La stabilità del manto nevoso è scarsa su alcuni punti (aree) per tutte le esposizioni al di sotto di 2500 mslm, possibili valanghe di dimensioni grandi.**

## AVVERTENZE

Il rialzo termico diurno richiede un'attenta valutazione temporale dell'escursione che eviti l'attraversamento di pendii ripidi nelle ore più calde della giornata.

## SCALA EUROPEA DEL GRADO DI PERICOLO VALANGHE

## LEGENDA PROBLEMA

**Bollettino realizzato su scala sinottica-regionale (standard EAWS). La sua valutazione non può escludere in alcun modo la necessità di una seria e capace valutazione locale del pericolo (singolo pendio) che può essere anche sensibilmente diverso. Le previsioni meteorologiche sono relative all'orario UTC (per l'Italia +1 in inverno e +2 in estate).**

MINISTERO DELLA DIFESA

meteomont
Servizio Nazionale di previsione neve e valanghe

EAWS EUROPEAN AVALANCHE WARNING SERVICES

CARABINIERI

# GRAN SASSO OVEST

## PREVISIONE METEO

| Quota | | 13/04/2026 h6:00 | 13/04/2026 h12:00 | 13/04/2026 h18:00 |
|---|---|---|---|---|
| 1000 | Venti | 04 Nodi da S-Est | 05 Nodi da S-Est | 03 Nodi da S-Est |
| | Temperature | +09 °C | +10 °C | +08 °C |
| | Temp.percepita | 8 °C | 9 °C | 7 °C |
| 2000 | Venti | 14 Nodi da S-Est | 12 Nodi da Sud | 10 Nodi da Sud |
| | Temperature | +06 °C | +05 °C | +05 °C |
| | Temp.percepita | 2 °C | 1 °C | 1 °C |
| 3000 | Venti | 21 Nodi da S-Est | 15 Nodi da Sud | 16 Nodi da Sud |
| | Temperature | -01 °C | -01 °C | -01 °C |
| | Temp.percepita | -9 °C | -8 °C | -8 °C |
| Zero termico | | 2800-3000 m. | 2700-2900 m. | 2700-2900 m. |
| Fenomeno | | — | | |
| Stato del cielo | | | | |

## LEGENDA FENOMENI

Assenza Fenomeni — Nebbia — Foschia — Pioggia debole — Pioggia moderata — Pioggia forte — Temporali

Nevicata debole — Nevicata moderata — Nevicata forte

## STATO DEL CIELO

Sereno — Poco nuvoloso — Nuvoloso — Molto nuvoloso — Coperto

## Parametri meteonivometrici registrati presso i campi di rilevamento il 12/04/2026.

| Località | Comune | Quota (m.s.l.m.) | Altezza neve (cm) | Neve caduta nelle 24 ore (cm) | Temp. Min (°C) | Temp. Max (°C) | Condizioni del tempo |
|---|---|---|---|---|---|---|---|
| COLLE RUTO | Campotosto (AQ) | 1384 | 0 | 0 | +5 | +18 | Assenza di precipitazioni |
| S. DONATO | Castel del Monte (AQ) | 1400 | 0 | 0 | +5 | +20 | Assenza di precipitazioni |
| SASSONE CANALE TEMPIO * | Pietracamela (TE) | 2565 | 360 | 0 | N.P. | N.P. | Assenza di precipitazioni |

(*) Rilievi fuori campo

**L'INFORMAZIONE E' PREVENZIONE - LEGGI L'ATTUALE GRADO DI PERICOLO VALANGHE!**

**IL CAPO DEL CENTRO NAZIONALE METEOMONT**
**(Ten. Col. RFI Emanuela Gini)**
**FIRMA AUTOGRAFA OMESSA AI SENSI**
**DELL'ART.3 DEL D.LGS N.39/1993**