Bulletin d'estimation du risque d'avalanche

(valable en dehors des pistes balisées et ouvertes)

MASSIF : Bauges

Rédigé le lundi 13 avril 2026 à 16h

Estimation des risques pour le : MARDI 14 AVRIL

MANTEAU NEIGEUX HUMIDE, PRINTANIER.

2

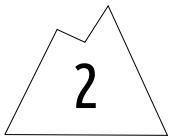

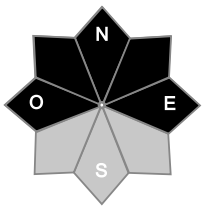

Indice de risque limité.

Départs spontanés : Départs de neige humide.

Déclenchements provoqués : De la niege humide coule sous les skis.

Indices de risque : 5 très fort - 4 fort - 3 marqué - 2 limité - 1 faible -- En noir : les pentes les plus dangereuses

Stabilité du manteau neigeux

Situation avalancheuse typique : neige humide avalanches de fond

Départs spontanés :

* Départs de neige humide avec la course du soleil et avec le réchauffement diurne. Possibles en tous versants mais principalement en ouest/nord/est. Rares départs en plaques au-dessus de 2000 m. Taille 1 à 2 (petite à moyenne).
* Plaques de fond possibles à toute heure du jour et de la nuit dans les pentes raides et lisses (pentes herbeuses, dalles rocheuses). Taille 1 à 2 (petite à moyenne).

Déclenchements provoqués :

* De la neige humide peut couler sous les skis. Possibles à toutes altitudes et en tous versants, mais principalement en ouest/nord/est. De plus en plus probable au fil du réchauffement diurne. Taille 1 à 2 (petite à moyenne).

Qualité de la neige

Enneigement :

L'enneigement est correct au-dessus de 2000 m. En dessous, il commence à être déficitaire.
On peut chausser les skis au-dessus de 1700/1800 m en sud et 1500/1600 m en nord. Des traces de neige sont présentes sous ces altitudes, mais l'enneigement est loin d'être continu.

Qualité de la neige mardi :

* En dessous de 1800 m : neige très humide ou absente. Pas de regel nocturne.
* Au-dessus de 1800 m : Faible regel nocturne. La croûte se ramollit avec le réchauffement et le manteau neigeux est alors humide en profondeur. Enfoncement piéton pouvant facilement atteindre 30/50 cm.

Aperçu météo pour le mardi 14 avril

nuit	matin	après-midi	soir

Couvert en moyenne montagne et vallées. Plus d'éclaircies en haute montagne. Doux en journée. Vent de secteur Nord faible.

Pluie-Neige				
Iso 0 °C	1 800 m	2 100 m	2 200 m	2 600 m
Vent 1500 m	↓ 15 km/h	↓ 20 km/h	↓ 25 km/h	↓ 10 km/h
Vent 2000 m	→ 10 km/h	↘ 20 km/h	↘ 20 km/h	↘ 10 km/h

Épaisseur de neige hors-piste

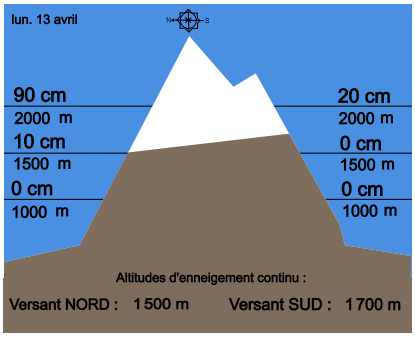

Précipitations à 1800 m

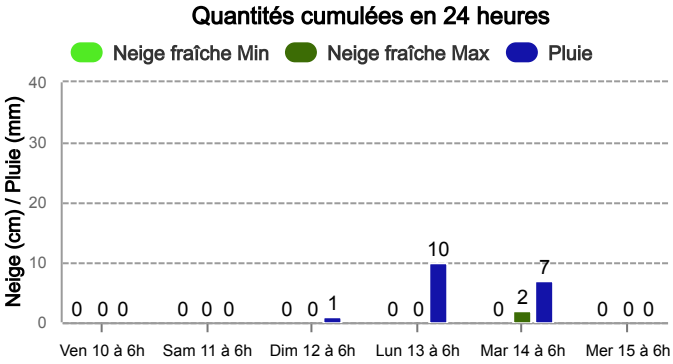

Tendance du mercredi 15 avril

2

Indice de risque limité

Le manteau neigeux continue son humidification en profondeur dans les pentes restées plus froides. Bon redoux en journée et soleil plus généreux.

Pour consulter la vigilance en cours, veuillez vous rendre sur le site https://vigilance.meteofrance.fr/fr

Météo-France - 73 avenue de Paris, 94165 Saint-Mandé cedex - Contact : contact@meteo.fr

Rédigé par Météo-France avec la contribution des observateurs du réseau nivo-météorologiques. Partenariat : ANMSM (Maires de Stations de Montagne), DSF (Domaines Skiables de France), ADSP (Directeurs de Pistes et de la Sécurité des Stations de Sports d'Hiver) et autres acteurs de la montagne.

Bulletin neige & avalanches par téléphone au

0 892 68 10 20 Service 0,35 € / min + prix appel

RÉPUBLIQUE FRANÇAISE
Liberté Égalité Fraternité

METEO FRANCE
À VOS CÔTÉS, DANS UN CLIMAT QUI CHANGE

Bulletin d'estimation du risque d'avalanche
(valable en dehors des pistes balisées et ouvertes)

MASSIF : Bauges

Rédigé le lundi 13 avril 2026 à 16h

Conditions nivo-météo des 7 derniers jours

	mar. 07/04				mer. 08/04				jeu. 09/04				ven. 10/04				sam. 11/04				dim. 12/04				lun. 13/04			
	03h	09h	15h	21h	03h	09h	15h	21h	03h	09h	15h	21h	03h	09h	15h	21h	03h	09h	15h	21h	03h	09h	15h	21h	03h	09h	15h	21h
Météo																												
Vent (km/h)	10	5	10	10	20	20	5	5	10	20	25	15	15	20	25	20	15	25	25	25	25	20	20	15	15	20	20	15
à 2000m																												
Vent (km/h)	10	0	5	10	10	15	5	5	5	10	20	10	10	10	15	10	10	20	20	20	15	15	15	10	10	10	15	10
à 1500m																												

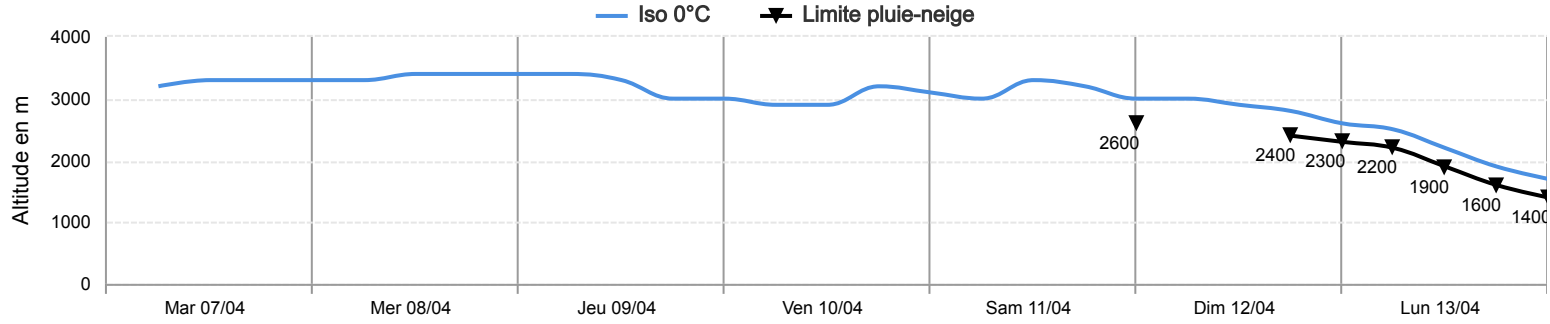

Neige fraîche à 06h

0 cm	0 cm	0 cm	0 cm	0 cm	0 cm

Risque d'avalanche	mar. 07/04	mer. 08/04	jeu. 09/04	ven. 10/04	sam. 11/04	dim. 12/04	lun. 13/04
	2	2	2	2	2	2	2

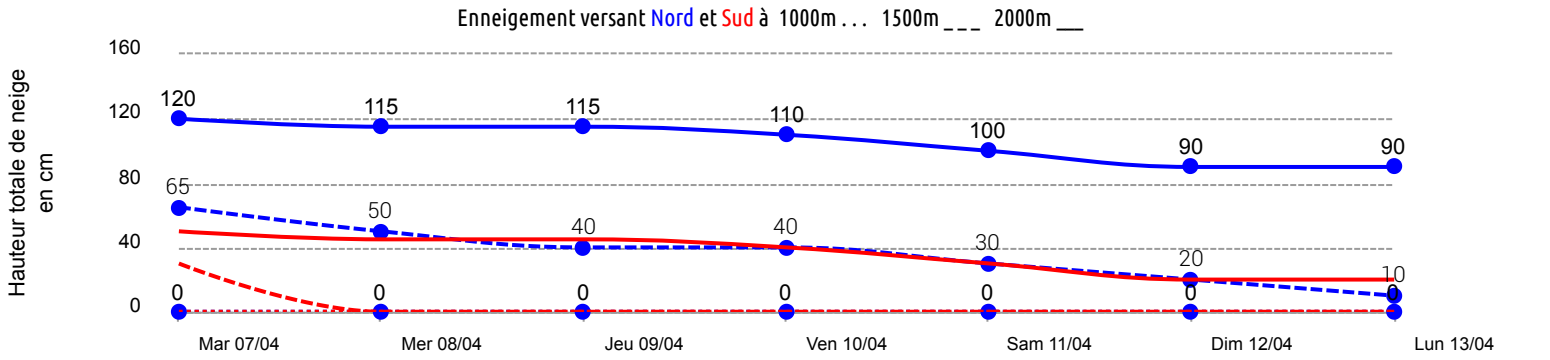

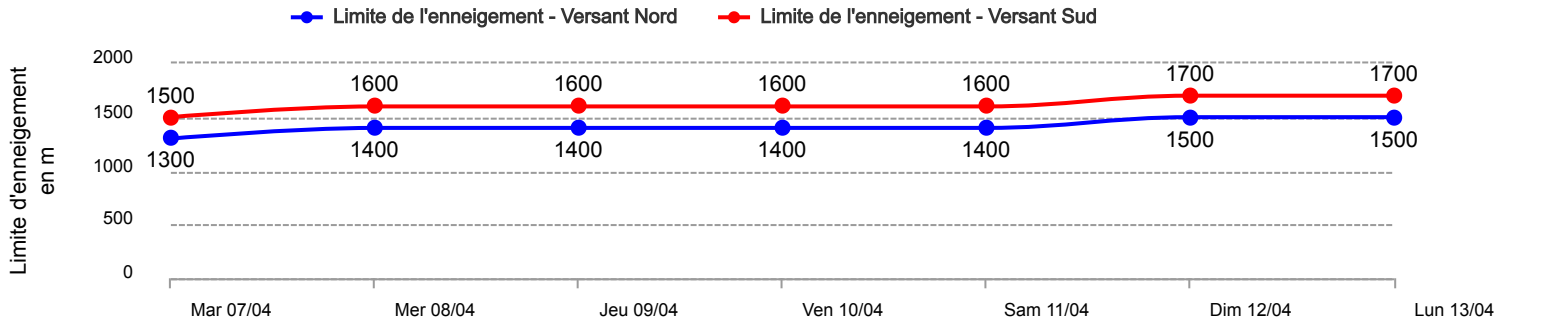

Pour consulter la vigilance en cours, veuillez vous rendre sur le site https://vigilance.meteofrance.fr/fr

Météo-France - 73 avenue de Paris, 94165 Saint-Mandé cedex - Contact : contact@meteo.fr

Rédigé par Météo-France avec la contribution des observateurs du réseau nivo-météorologiques. Partenariat : ANMSM (Maires de Stations de Montagne), DSF (Domaines Skiables de France), ADSP (Directeurs de Pistes et de la Sécurité des Stations de Sports d'Hiver) et autres acteurs de la montagne.

Bulletin neige & avalanches par téléphone au
0 892 68 10 20 Service 0,35 € / min + prix appel