Bulletin d'estimation du risque d'avalanche
(valable en dehors des pistes balisées et ouvertes)
MASSIF : Beaufortain

Rédigé le lundi 13 avril 2026 à 16h

Estimation des risques pour le : MARDI 14 AVRIL

NUAGES ET CHAUFFAGE, HUMIDIFICATION MÊME EN PLEIN NORD.

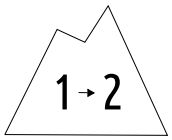

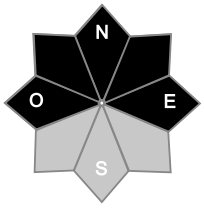

Indice de risque faible évoluant en limité.

Départs spontanés : quelques départs en neige humide.

Déclenchements provoqués : petites coulées sous les skis dans la neige fortement humidifiée (pourrie).

Indices de risque : 5 très fort - 4 fort - 3 marqué - 2 limité - 1 faible -- En noir : les pentes les plus dangereuses

Stabilité du manteau neigeux

Situation avalancheuse typique : neige humide

Départs spontanés :
- **Quelques départs en neige humide** sont attendus en **tous versants**, ils deviennent plus **fréquents l'après midi**. Ce sont principalement des **départs ponctuels (poires)**, donnant des **petites à moyennes avalanches**. Avec les nuages, les versants nord chauffent et sont donc aussi concernés par ce risque, un rare cassure linéaire au volume plus important peut y être observée si l'humidification atteint pour la première fois une couche fragile enfouie.
- **Rares avalanches de glissement** (plaques de fond) à toute heure sur terrain propice, notamment en Nord sous 2500/2600 m. Taille 2.

Déclenchements provoqués : avalanche de neige humide (pourrie) sous les skis en coupant une pente trop humidifiée au fil des heures, avec les nuages toutes les orientations chauffent en même temps.

Autres : chutes de corniches possibles.

Qualité de la neige

Enneigement : l'enneigement est revenu au niveau des normales suite à la chaleur des derniers jours, le chauffage et la présence des nuages accélèrent la fonte.

Limite skiable : vers 1200/1300 m en Nord, 1600/1700 m en Sud.

Qualité de la neige : Les quelques centimètres de fraiche possibles au dessus de 2200 m se tassent et s'humidifient vite en tous versants même en nord où la neige devient collante. Regel aléatoire et manteau profondément pourri parfois dès le matin.

Aperçu météo pour le mardi 14 avril

	nuit	matin	après-midi	soir

Éclaircies le matin, nuages de plus en plus présents en journée, températures en hausse.

Pluie-Neige	1 600 m			
Iso 0 °C	2 000 m	2 400 m	2 700 m	2 900 m
Vent 2000 m	↙ 10 km/h	↙ 15 km/h	↓ 15 km/h	↘ 5 km/h
Vent 3000 m	↘ 15 km/h	↘ 20 km/h	↘ 20 km/h	↘ 10 km/h

Épaisseur de neige hors-piste

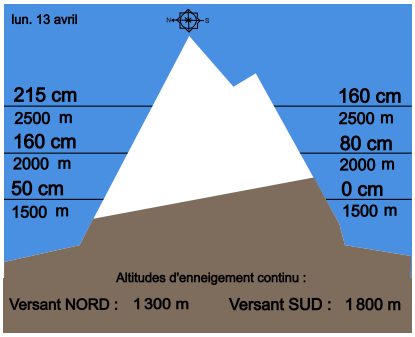

Précipitations à 1800 m

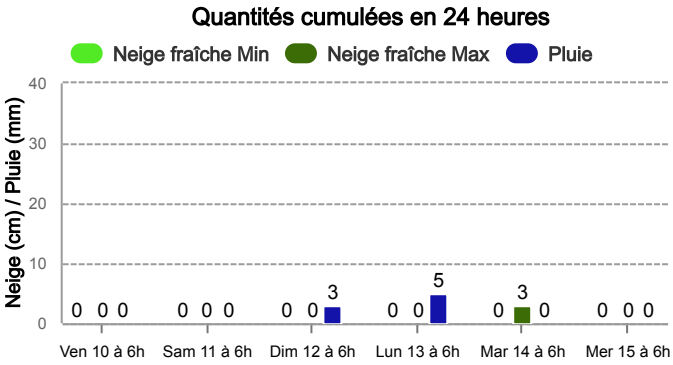

Tendance du mercredi 15 avril

Indice de risque limité

Encore des nuages et des températures élevées favorisant l'activité en neige humide, risque limité stationnaire.

Pour consulter la vigilance en cours, veuillez vous rendre sur le site https://vigilance.meteofrance.fr/fr

Météo-France - 73 avenue de Paris, 94165 Saint-Mandé cedex - Contact : contact@meteo.fr

Rédigé par Météo-France avec la contribution des observateurs du réseau nivo-météorologiques. Partenariat : ANMSM (Maires de Stations de Montagne), DSF (Domaines Skiables de France), ADSP (Directeurs de Pistes et de la Sécurité des Stations de Sports d'Hiver) et autres acteurs de la montagne.

Bulletin neige & avalanches par téléphone au **0 892 68 10 20** Service 0,35 € / min + prix appel

RÉPUBLIQUE FRANÇAISE
Liberté Égalité Fraternité

METEO FRANCE
À VOS CÔTÉS, DANS UN CLIMAT QUI CHANGE

Bulletin d'estimation du risque d'avalanche
(valable en dehors des pistes balisées et ouvertes)
MASSIF : Beaufortain

Rédigé le lundi 13 avril 2026 à 16h

Conditions nivo-météo des 7 derniers jours

	mar. 07/04				mer. 08/04				jeu. 09/04				ven. 10/04				sam. 11/04				dim. 12/04				lun. 13/04			
	03h	09h	15h	21h	03h	09h	15h	21h	03h	09h	15h	21h	03h	09h	15h	21h	03h	09h	15h	21h	03h	09h	15h	21h	03h	09h	15h	21h
Météo																												
Vent (km/h)	10	5	5	15	15	10	5	5	10	20	30	15	15	20	30	20	15	20	25	25	25	30	35	35	30	30	30	20
à 3000m																												
Vent (km/h)	5	0	5	5	10	5	0	0	5	15	25	10	10	15	25	10	10	10	15	15	15	15	20	20	20	25	25	10
à 2000m																												

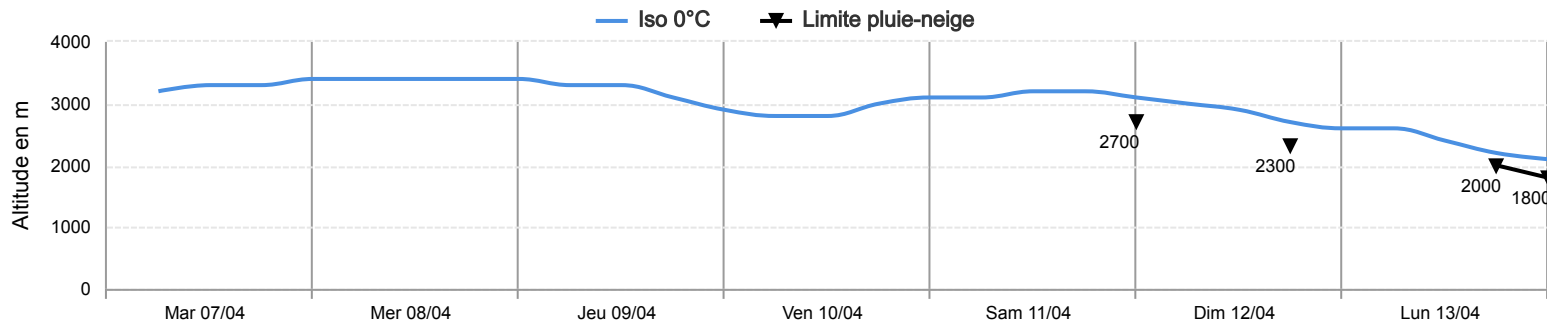

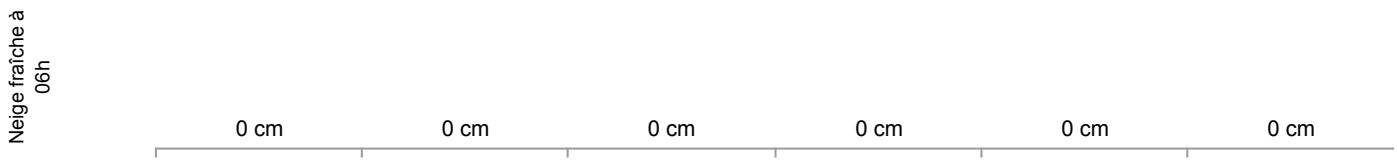

Risque d'avalanche	mar. 07/04	mer. 08/04	jeu. 09/04	ven. 10/04	sam. 11/04	dim. 12/04	lun. 13/04
	2	2	2	2	2	2	2

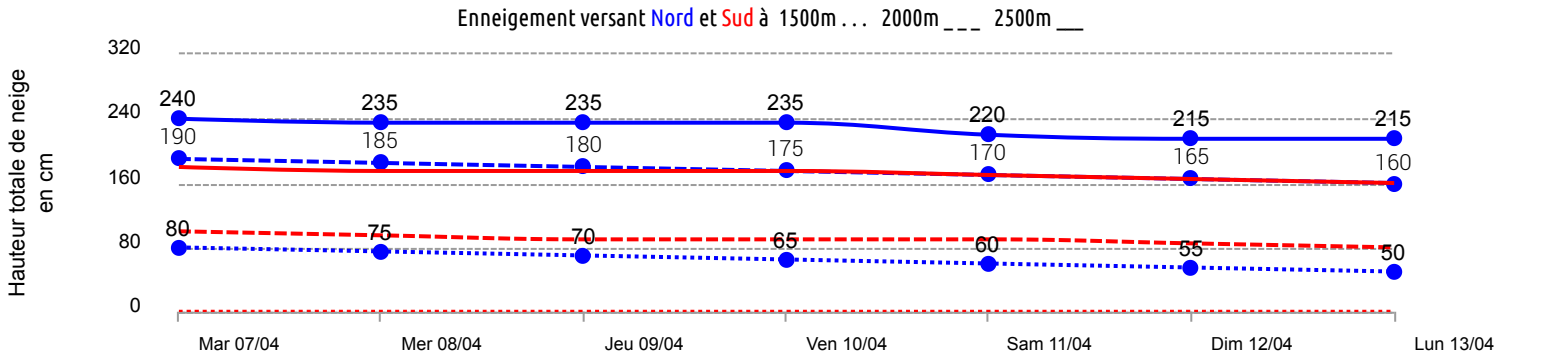

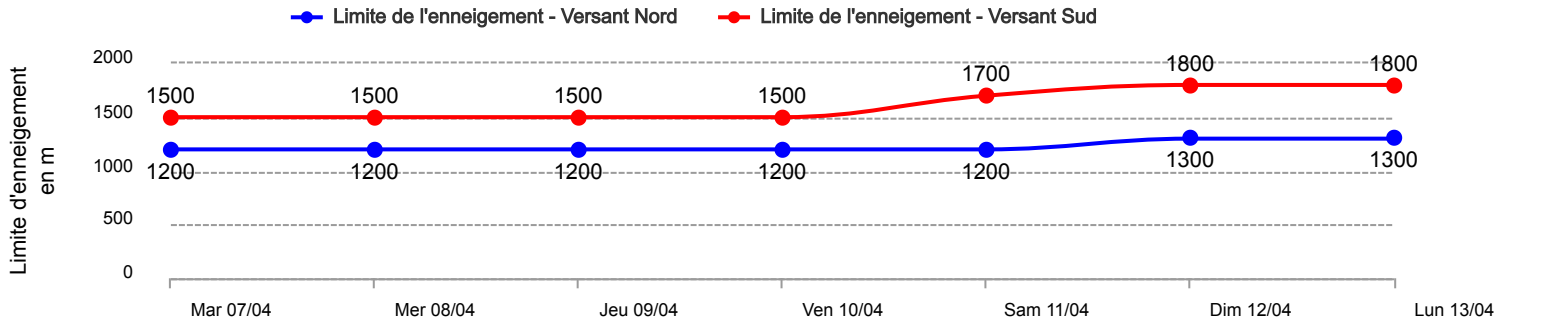

Pour consulter la vigilance en cours, veuillez vous rendre sur le site https://vigilance.meteofrance.fr/fr

Météo-France - 73 avenue de Paris, 94165 Saint-Mandé cedex - Contact : contact@meteo.fr

Rédigé par Météo-France avec la contribution des observateurs du réseau nivo-météorologiques. Partenariat : ANMSM (Maires de Stations de Montagne), DSF (Domaines Skiables de France), ADSP (Directeurs de Pistes et de la Sécurité des Stations de Sports d'Hiver) et autres acteurs de la montagne.

Bulletin neige & avalanches par téléphone au
0 892 68 10 20 Service 0,35 € / min + prix appel