Bulletin d'estimation du risque d'avalanche

(valable en dehors des pistes balisées et ouvertes)

MASSIF : Cerdagne Canigou

Rédigé le lundi 13 avril 2026 à 16h

Estimation des risques pour le : MARDI 14 AVRIL

PLAQUES EN ALTITUDE, DES COULÉES AU SOLEIL

2

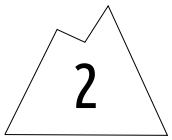

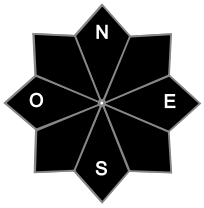

Indice de risque limité.

Départs spontanés : Fréquentes coulées de surface

Déclenchements provoqués : Quelques plaques en altitude

Indices de risque : 5 très fort - 4 fort - 3 marqué - 2 limité - 1 faible -- En noir : les pentes les plus dangereuses

Stabilité du manteau neigeux

Situation avalancheuse typique : neige ventée neige humide

Déclenchements provoqués :
De petites plaques plus ou moins friables se sont formées en altitude et pourraient continuer à se former avec le vent de secteur nord, reposant sur des neiges tombées sans vent. Ces plaques peuvent parfois être déclenchées au passage d'un simple randonneur. Ce risque se cantonne progressivement au-dessus de 2500m et dans les versants ombragés restés en neige sèche, du fait de l'humidification en journée. Un skieur coupant une pente en neige pourrie pourra également déclencher une coulée sous ses skis.
Observables : transport de la neige par le vent, disparition des traces de montée, fissures devant les skis.

Départs spontanés :
Du fait d'un soleil efficace et de la remontée de l'isotherme 0 °C de nombreuses coulées de surface se produisent dans les pentes suffisamment raides prenant le soleil, donc plutôt dans les versants d'un vaste secteur Est puis Sud puis Ouest.
Observables : neige pourrie, escargots.

Qualité de la neige

Enneigement :
L'enneigement demeure excellent pour la saison, un des meilleurs des 30 dernières années. Les dernières chutes de neige ont blanchi la montagne dès 1400m mais les quantités sont trop faibles pour modifier la limite skiable. On chausse le plus souvent à partir de 1600 m en nord, 1800 m en sud sur une couche de neige rapidement très épaisse, dépassant les 2 m à 2000m d'altitude.

Qualité de la neige :
On trouve mardi une petite couche de neige récente reposant sur un fond souvent dur et regelé au-dessus de 2000m, avec des cols et crêtes en neige dure et quelques rares combes abritées du vent et du soleil gardant une neige poudreuse.

Aperçu météo pour le mardi 14 avril

nuit	matin	après-midi	soir

Journée ensoleillée accompagnée d'un net redoux

Pluie-Neige				
Iso 0 °C	1 700 m	1 800 m	2 500 m	2 800 m
Vent 2000 m	↘ 40 km/h	↘ 45 km/h	↘ 35 km/h	↘ 30 km/h
Vent 3000 m	↓ 60 km/h	↓ 55 km/h	↘ 45 km/h	↓ 40 km/h

Épaisseur de neige hors-piste

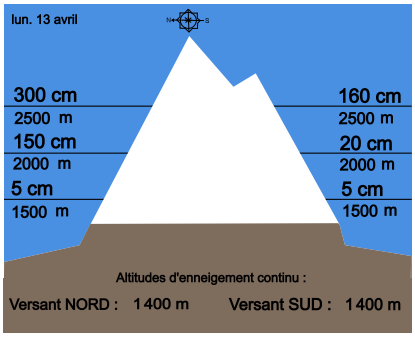

Précipitations à 1800 m

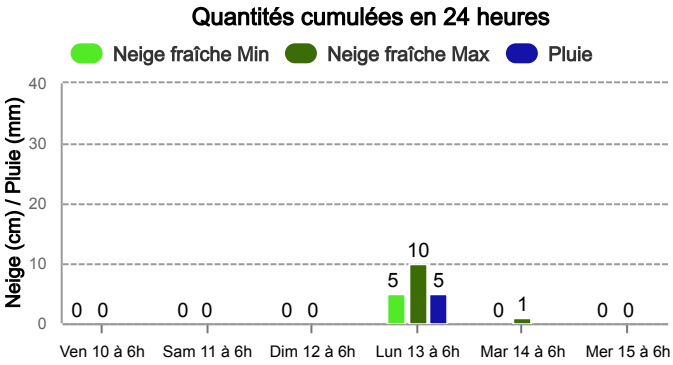

Tendance du mercredi 15 avril

2

Indice de risque limité

Maintien d'un risque limité avec une poursuite de l'humidification et une stabilisation progressive des plaques

Pour consulter la vigilance en cours, veuillez vous rendre sur le site https://vigilance.meteofrance.fr/fr

Météo-France - 73 avenue de Paris, 94165 Saint-Mandé cedex - Contact : contact@meteo.fr

Rédigé par Météo-France avec la contribution des observateurs du réseau nivo-météorologiques. Partenariat : ANMSM (Maires de Stations de Montagne), DSF (Domaines Skiables de France), ADSP (Directeurs de Pistes et de la Sécurité des Stations de Sports d'Hiver) et autres acteurs de la montagne.

Bulletin neige & avalanches par téléphone au 0 892 68 10 20 Service 0,35 € / min + prix appel

RÉPUBLIQUE FRANÇAISE
Liberté Égalité Fraternité

METEO FRANCE
À VOS CÔTÉS, DANS UN CLIMAT QUI CHANGE

Bulletin d'estimation du risque d'avalanche

(valable en dehors des pistes balisées et ouvertes)

MASSIF : Cerdagne Canigou

Rédigé le lundi 13 avril 2026 à 16h

Conditions nivo-météo des 7 derniers jours

	mar. 07/04				mer. 08/04				jeu. 09/04				ven. 10/04				sam. 11/04				dim. 12/04				lun. 13/04			
	03h	09h	15h	21h	03h	09h	15h	21h	03h	09h	15h	21h	03h	09h	15h	21h	03h	09h	15h	21h	03h	09h	15h	21h	03h	09h	15h	21h
Météo																												
Vent (km/h)	30	25	20	20	30	35	35	25	25	25	25	25	30	20	25	25	30	30	45	45	40	30	30	20	35	65	65	75
à 3000m																												
Vent (km/h)	20	15	15	10	20	25	25	20	15	15	15	15	20	15	20	15	20	20	35	35	25	20	20	15	30	50	50	45
à 2000m																												

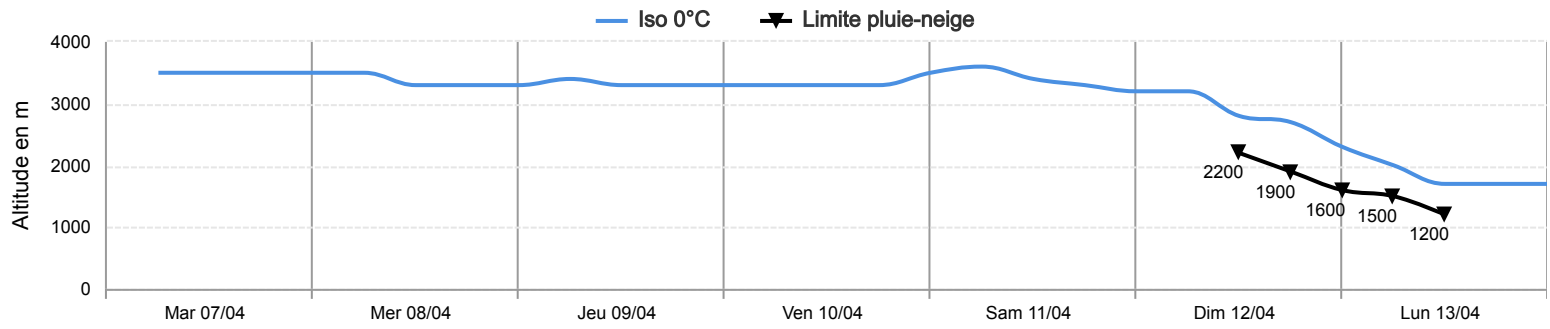

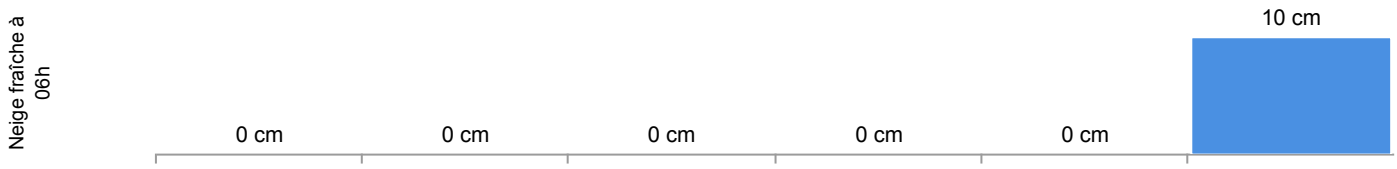

Risque d'avalanche	mar. 07/04	mer. 08/04	jeu. 09/04	ven. 10/04	sam. 11/04	dim. 12/04	lun. 13/04
	2	2	2	2	2	2	2

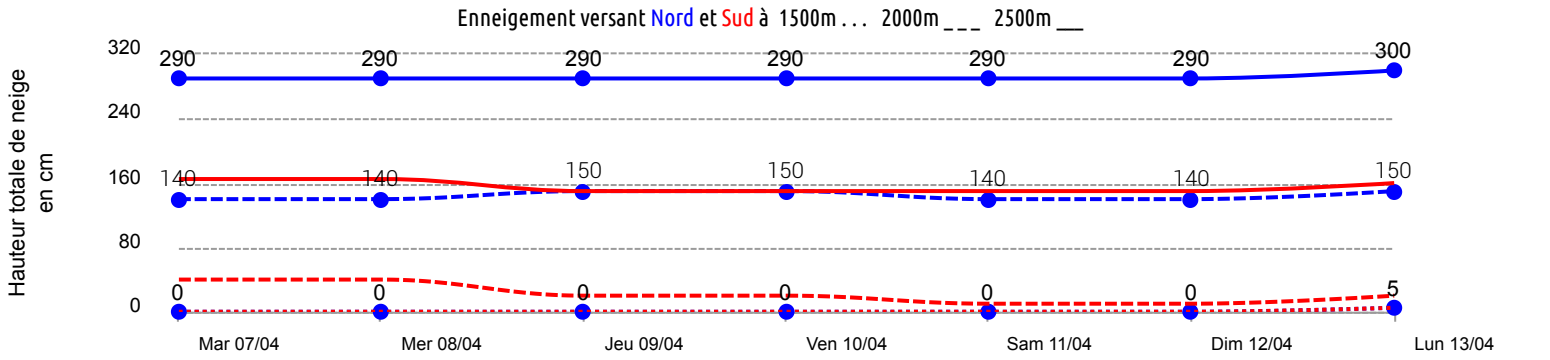

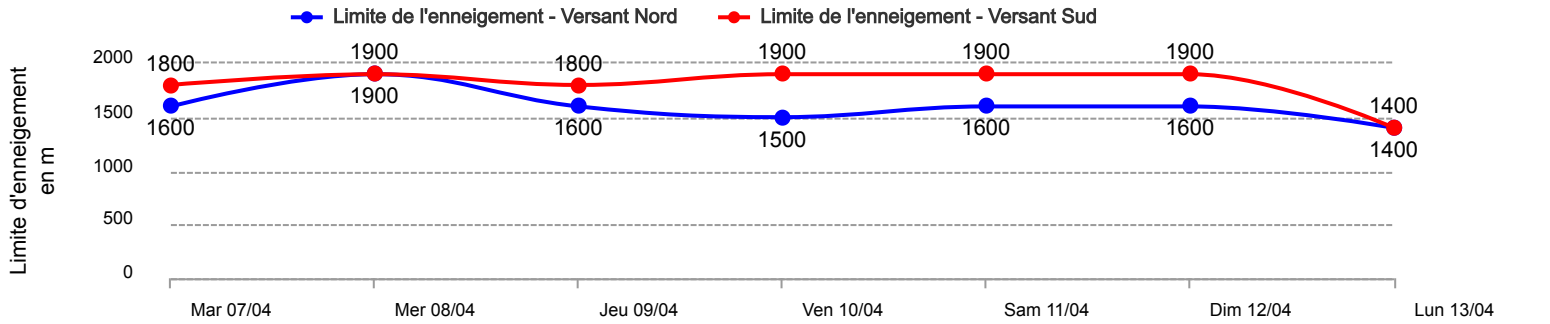

Pour consulter la vigilance en cours, veuillez vous rendre sur le site https://vigilance.meteofrance.fr/fr

Météo-France - 73 avenue de Paris, 94165 Saint-Mandé cedex - Contact : contact@meteo.fr

Rédigé par Météo-France avec la contribution des observateurs du réseau nivo-météorologiques. Partenariat : ANMSM (Maires de Stations de Montagne), DSF (Domaines Skiables de France), ADSP (Directeurs de Pistes et de la Sécurité des Stations de Sports d'Hiver) et autres acteurs de la montagne.

Bulletin neige & avalanches par téléphone au

0 892 68 10 20 Service 0,35 € / min + prix appel