Bulletin d'estimation du risque d'avalanche
(valable en dehors des pistes balisées et ouvertes)

MASSIF : Champsaur

Rédigé le lundi 13 avril 2026 à 16h

Estimation des risques pour le : MARDI 14 AVRIL

RARES PLAQUES À HAUTE ALTITUDE

2

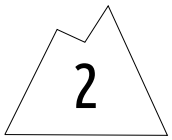

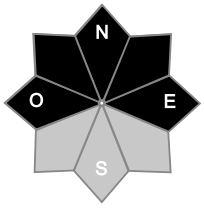

Indice de risque limité.

Départs spontanés : en neige récente humidifiée.

Déclenchements provoqués : petites instabilités dans la neige récente ventée à haute altitude.

Indices de risque : 5 très fort - 4 fort - 3 marqué - 2 limité - 1 faible -- En noir : les pentes les plus dangereuses

Stabilité du manteau neigeux

Situation avalancheuse typique : neige ventée neige humide

Déclenchements provoqués : de rares instabilités sont en place dans la neige récente ventée à haute altitude (au-dessus de 2400 m), plutôt localisées en coeur de massif. Elles sont possibles en toute orientation, mais plus nombreuses dans les orientations ouest à est en passant par le nord. Elles peuvent encore être déclenchées par un seul skieur et génèrent des avalanches de taille petite (taille 1), à rarement moyenne (taille 2).
Sous 2400 m, le manteau neigeux est maintenant complètement humidifé. Un skieur peut engendrer un départ ponctuel dans une pente raide fortement humidifiée. L'ensemble du manteau neigeux peut alors être mobilisé des avalanches de taille moyenne (taille 2) sont possibles notamment en versant ouest, nord-ouest, nord-est et est.

Départs spontanés : quelques départs en neige récente humidifiée dans les pentes raides, au fil des éclaircies se mettant en place en cours de journée.

Qualité de la neige

Enneigement déficitaire pour une mi-avril en adrets, proche des normales en ubacs et fonds de vallons.
Hauteurs de neige observées vers 2500 m : 143 cm au-dessus de Prapic à 2500 m, 89 cm à la nivôse d'Orcières à 2300 m.

Limite d'enneigement skiable : généralement vers 1600/1700 m, très localement 1400/1500 m en ubacs favorables (terrains herbeux, pistes forestières), 2000/2100 m en adrets pas trop raides.

État de la neige de surface : un peu de neige récente (5/10 cm) à partir de 2000/2200 m, sur un manteau humide ou mal regelé jusque 2700/2800 m.

Aperçu météo pour le mardi 14 avril

nuit	matin	après-midi	soir

Plutôt nuageux le matin, puis développement de belles éclaircies au fil des heures.

Pluie-Neige				
Iso 0 °C	2 200 m	2 400 m	2 700 m	2 600 m
Vent 2000 m	↙ 15 km/h	↙ 15 km/h	← 15 km/h	← 10 km/h
Vent 3000 m	↙ 25 km/h	← 25 km/h	↙ 20 km/h	← 20 km/h

Épaisseur de neige hors-piste

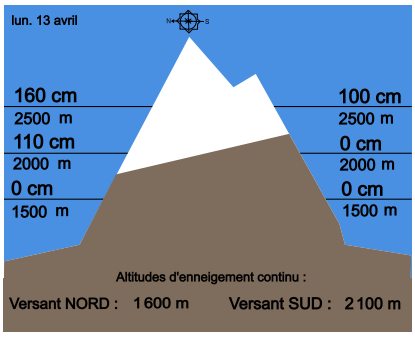

Précipitations à 1800 m

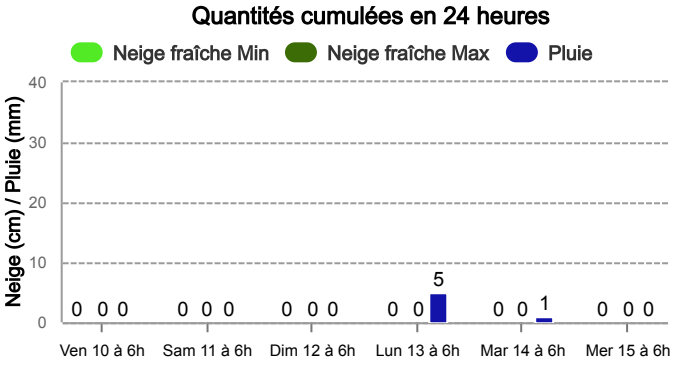

Tendance du mercredi 15 avril

2

Indice de risque limité

L'activité en neige humide reprend lentement avec le retour du soleil et le radoucissement progressif de la masse d'air.

Pour consulter la vigilance en cours, veuillez vous rendre sur le site https://vigilance.meteofrance.fr/fr

Météo-France - 73 avenue de Paris, 94165 Saint-Mandé cedex - Contact : contact@meteo.fr

Rédigé par Météo-France avec la contribution des observateurs du réseau nivo-météorologiques. Partenariat : ANMSM (Maires de Stations de Montagne), DSF (Domaines Skiables de France), ADSP (Directeurs de Pistes et de la Sécurité des Stations de Sports d'Hiver) et autres acteurs de la montagne.

Bulletin neige & avalanches par téléphone au
0 892 68 10 20 Service 0,35 € / min + prix appel

RÉPUBLIQUE FRANÇAISE
Liberté Égalité Fraternité

METEO FRANCE
À VOS CÔTÉS, DANS UN CLIMAT QUI CHANGE

Bulletin d'estimation du risque d'avalanche

(valable en dehors des pistes balisées et ouvertes)

MASSIF : Champsaur

Rédigé le lundi 13 avril 2026 à 16h

Conditions nivo-météo des 7 derniers jours

	mar. 07/04				mer. 08/04				jeu. 09/04				ven. 10/04				sam. 11/04				dim. 12/04				lun. 13/04			
	03h	09h	15h	21h	03h	09h	15h	21h	03h	09h	15h	21h	03h	09h	15h	21h	03h	09h	15h	21h	03h	09h	15h	21h	03h	09h	15h	21h
Météo																												
Vent (km/h)	10	10	10	10	10	10	10	10	10	10	20	25	25	20	20	15	15	15	15	15	15	20	35	40	35	25	20	10
à 3000m																												
Vent (km/h)	5	5	10	5	5	5	10	5	5	5	15	15	15	10	20	10	10	10	15	10	10	10	15	20	25	20	15	15
à 2000m																												

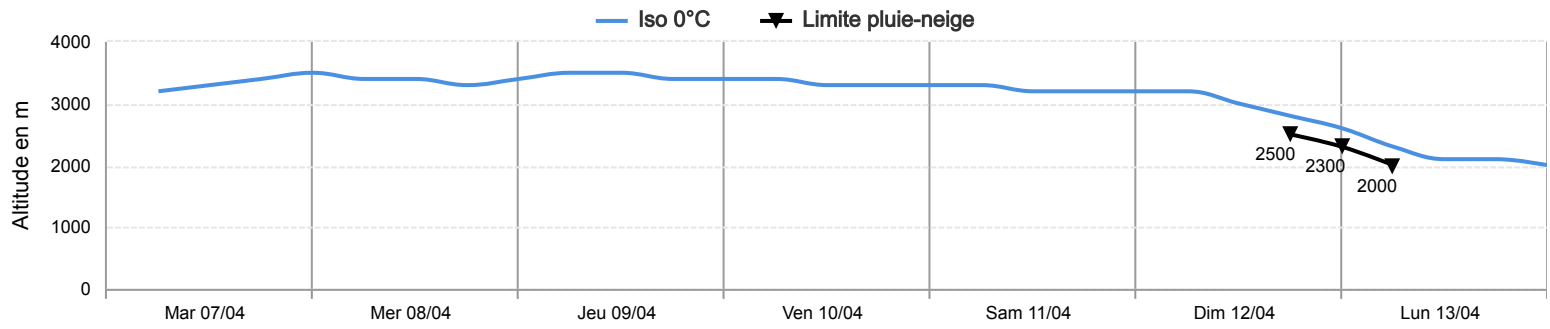

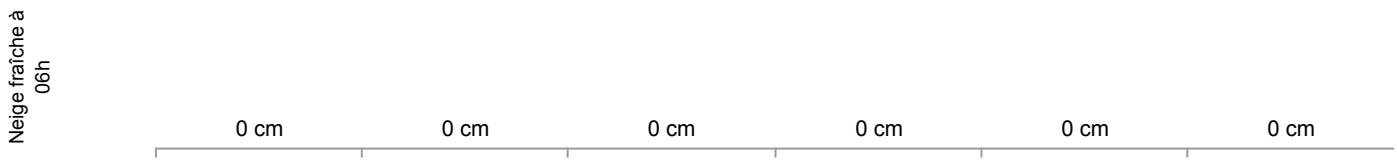

Risque d'avalanche	mar. 07/04	mer. 08/04	jeu. 09/04	ven. 10/04	sam. 11/04	dim. 12/04	lun. 13/04
	2	2	3	3	3	2	2

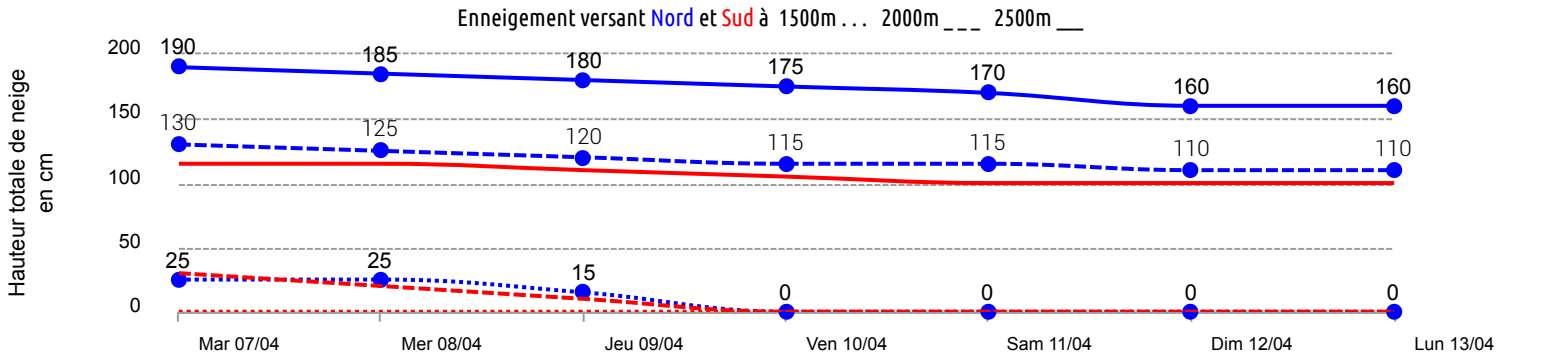

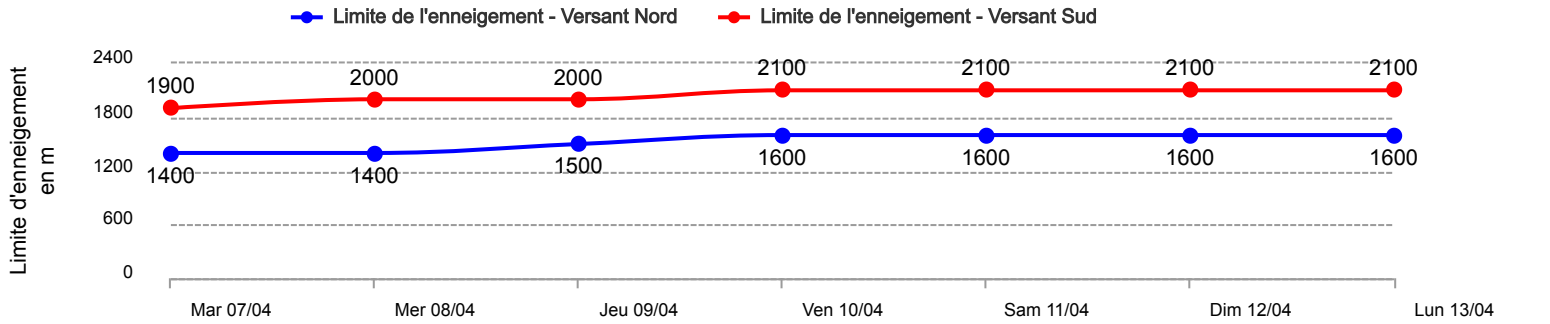

Pour consulter la vigilance en cours, veuillez vous rendre sur le site https://vigilance.meteofrance.fr/fr

Météo-France - 73 avenue de Paris, 94165 Saint-Mandé cedex - Contact : contact@meteo.fr

Rédigé par Météo-France avec la contribution des observateurs du réseau nivo-météorologiques. Partenariat : ANMSM (Maires de Stations de Montagne), DSF (Domaines Skiables de France), ADSP (Directeurs de Pistes et de la Sécurité des Stations de Sports d'Hiver) et autres acteurs de la montagne.

Bulletin neige & avalanches par téléphone au
0 892 68 10 20 Service 0,35 € / min + prix appel