Bulletin d'estimation du risque d'avalanche

(valable en dehors des pistes balisées et ouvertes)

MASSIF : Devoluy

Rédigé le lundi 13 avril 2026 à 16h

Estimation des risques pour le : MARDI 14 AVRIL

PLAQUES RÉSIDUELLES À HAUTE ALTITUDE

2

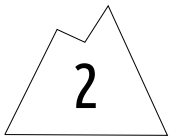

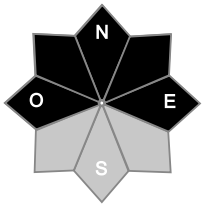

Indice de risque limité.

Départs spontanés : en neige récente humidifiée ou rare avalanche de glissement.

Déclenchements provoqués : ponctuels dans la neige humide, parfois volumineux.

Indices de risque : 5 très fort - 4 fort - 3 marqué - 2 limité - 1 faible -- En noir : les pentes les plus dangereuses

Stabilité du manteau neigeux

Situation avalancheuse typique : neige humide

Déclenchements provoqués : de rares instabilités sont en place dans la récente ventée. Elles sont plutôt localisées dans les orientations ouest, nord et est au-dessus de 2400 m. Elles sont facilement identifiables et déclenchables par le passage d'un seul skieur, générant des avalanches de taille petite (taille 1), à très rarement moyenne (taille 2).
Sous 2400 m, le manteau neigeux est maintenant complètement humidifié. Un skieur peut engendrer un départ ponctuel dans une pente raide fortement humidifiée. L'ensemble du manteau neigeux peut alors être mobilisé des avalanches de taille moyenne (taille 2) sont possibles notamment en versant ouest, nord-ouest, nord-est et est.

Départs spontanés : quelques départs en neige récente humidifiée dans les pentes raides, au fil des éclaircies se mettant en place en cours de journée. Avalanches de glissement possibles (taille moyenne).

Qualité de la neige

Enneigement encore excédentaire pour une mi-avril, notamment en ubacs et vallons d'altitude.

Limite d'enneigement skiable : vers 1400/1500 m en ubacs favorables (terrains herbeux, pistes forestières), 1900/2000 m en adrets pas trop raides.

État de la neige de surface : manteau neigeux humide regelant progressivement lundi avec le refroidissement de la masse d'air

Aperçu météo pour le mardi 14 avril

nuit	matin	après-midi	soir

Plutôt nuageux le matin, puis développement de belles éclaircies au fil des heures.

Pluie-Neige				
Iso 0 °C	2 300 m	2 500 m	2 800 m	2 900 m
Vent 2000 m	↓ 30 km/h	↓ 25 km/h	↓ 25 km/h	↓ 15 km/h
Vent 3000 m	← 25 km/h	← 10 km/h	↙ 15 km/h	↙ 10 km/h

Épaisseur de neige hors-piste

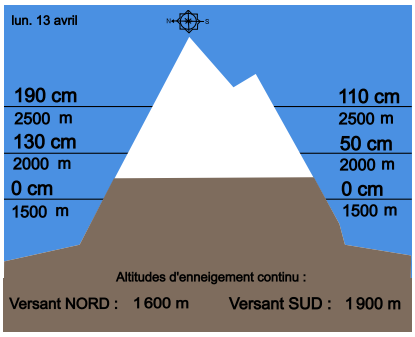

Précipitations à 1800 m

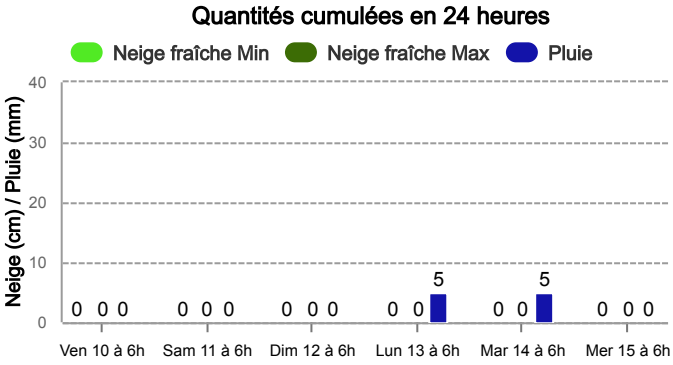

Tendance du mercredi 15 avril

2

Indice de risque limité

Maintien d'un risque limité. L'activité en neige humide reprend lentement avec le retour du soleil et le radoucissement progressif de la masse d'air.

Pour consulter la vigilance en cours, veuillez vous rendre sur le site https://vigilance.meteofrance.fr/fr

Météo-France - 73 avenue de Paris, 94165 Saint-Mandé cedex - Contact : contact@meteo.fr

Rédigé par Météo-France avec la contribution des observateurs du réseau nivo-météorologiques. Partenariat : ANMSM (Maires de Stations de Montagne), DSF (Domaines Skiables de France), ADSP (Directeurs de Pistes et de la Sécurité des Stations de Sports d'Hiver) et autres acteurs de la montagne.

Bulletin neige & avalanches par téléphone au
0 892 68 10 20 Service 0,35 € / min + prix appel

Bulletin d'estimation du risque d'avalanche

(valable en dehors des pistes balisées et ouvertes)

MASSIF : Devoluy

Rédigé le lundi 13 avril 2026 à 16h

Conditions nivo-météo des 7 derniers jours

	mar. 07/04				mer. 08/04				jeu. 09/04				ven. 10/04				sam. 11/04				dim. 12/04				lun. 13/04			
	03h	09h	15h	21h	03h	09h	15h	21h	03h	09h	15h	21h	03h	09h	15h	21h	03h	09h	15h	21h	03h	09h	15h	21h	03h	09h	15h	21h
Météo																												
Vent (km/h)	10	5	5	10	10	10	5	5	5	15	30	50	40	30	30	30	25	20	15	20	25	35	50	50	40	15	10	10
à 3000m	↓	↙	↙	←	↙	↖	↙	↙	↘	↘	↘	↓	↓	↓	↘	↘	→	→	→	↗	↑	↑	↖	↖	↖	↖	↙	←
Vent (km/h)	5	10	15	5	5	5	10	5	10	15	25	35	35	30	30	15	10	10	20	15	15	15	20	30	30	25	25	40
à 2000m	↙	↖	↗	↙	↓	↓	↘	↓	↓	↓	↓	↓	↓	↓	↘	↘	→	↑	↑	↑	↑	↑	↑	↖	↖	←	↙	↓

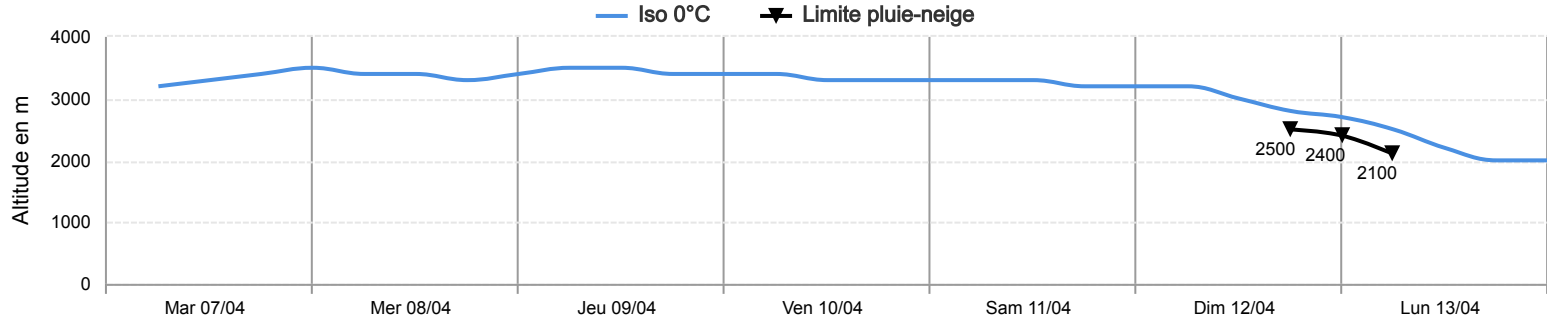

Neige fraîche à 06h

0 cm	0 cm	0 cm	0 cm	0 cm	0 cm

Risque d'avalanche	mar. 07/04	mer. 08/04	jeu. 09/04	ven. 10/04	sam. 11/04	dim. 12/04	lun. 13/04
	2	2	2	2	2	2	2

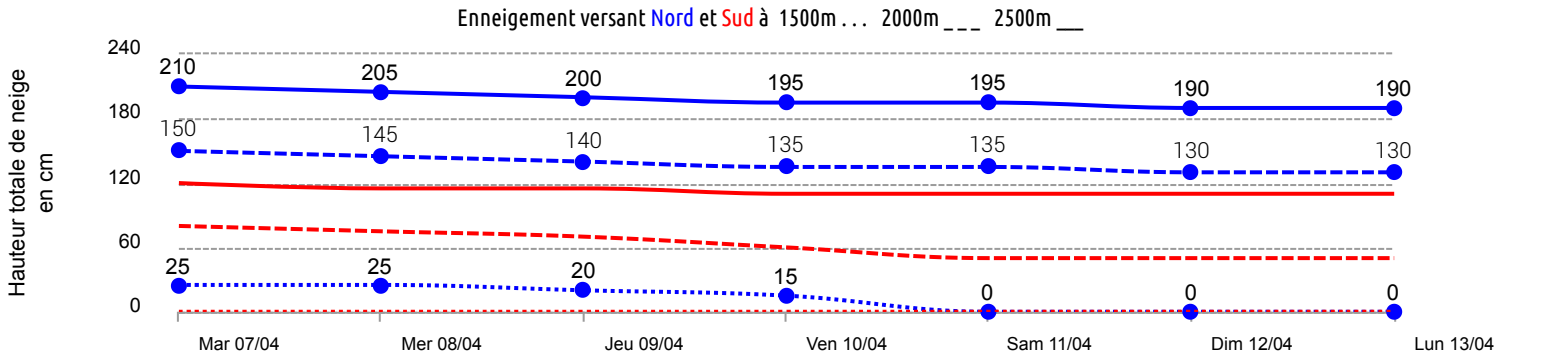

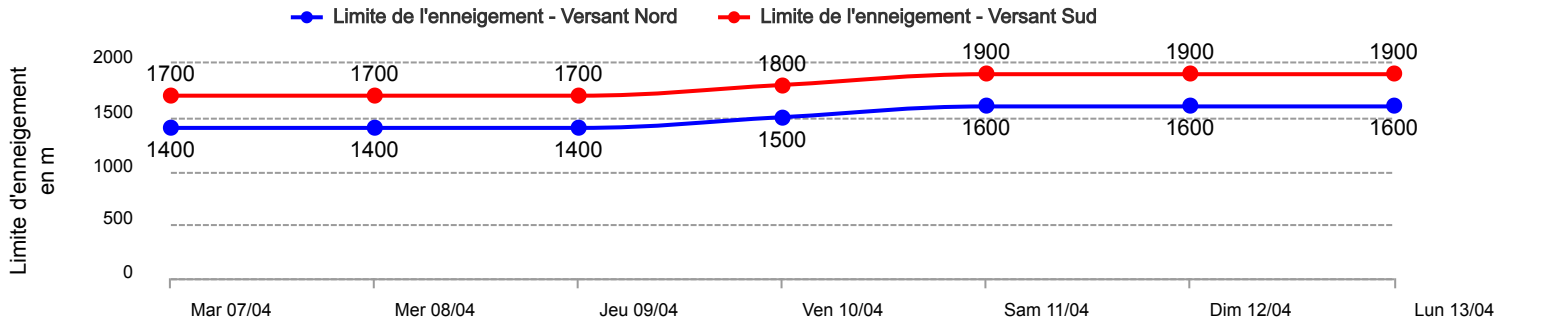

Pour consulter la vigilance en cours, veuillez vous rendre sur le site https://vigilance.meteofrance.fr/fr

Météo-France - 73 avenue de Paris, 94165 Saint-Mandé cedex - Contact : contact@meteo.fr

Rédigé par Météo-France avec la contribution des observateurs du réseau nivo-météorologiques. Partenariat : ANMSM (Maires de Stations de Montagne), DSF (Domaines Skiables de France), ADSP (Directeurs de Pistes et de la Sécurité des Stations de Sports d'Hiver) et autres acteurs de la montagne.

Bulletin neige & avalanches par téléphone au

0 892 68 10 20 Service 0,35 € / min + prix appel