# Bulletin d'estimation du risque d'avalanche

(valable en dehors des pistes balisées et ouvertes)

# MASSIF : Grandes-Rousses

Rédigé le lundi 13 avril 2026 à 16h

## Estimation des risques pour le : MARDI 14 AVRIL

**FAIBLE REGEL MARDI MATIN EN ALTITUDE, PUIS REDOUX/BROUILLARD, RISQUE LOCALISE D'AVALANCHE HUMIDE, PARFOIS AU TERRAIN ?**

2

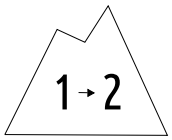


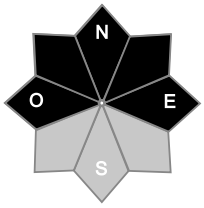


Très localisées

Indices de risque : 5 très fort - 4 fort - 3 marqué - 2 limité - 1 faible -- En noir : les pentes les plus dangereuses

Indice de risque faible évoluant en limité.

**Départs spontanés :** Au fil des heures, rares coulées humides ou avalanches plus conséquentes en faces "froides", notamment sous 2200/2500m (de taille 2, parfois 3)...

**Déclenchements provoqués :** Peu probable ou coulée humide ponctuelle sous les skis...

## Stabilité du manteau neigeux

**Situation avalancheuse typique :** neige humide avalanches de fond

Saupoudrage sans conséquence lundi. Mardi, faible regel au matin puis neige rapidement humide sur une grande épaisseur, un peu instable en versants "froids", rares avalanches possibles, glissant parfois au terrain...

**Départs spontanés :**

En altitude, un peu de regel puis avec le redoux et le brouillard prévu la neige s'humidifie en tous versants, sur une grande épaisseur...
On s'attend à quelques coulées de neige "lourde", parfois une avalanche conséquente en faces Nord (où la neige est moins dense). Noter que certaines pentes herbeuses sont fissurées, une avalanche de glissement, au terrain n'est pas exclue, notamment sous 2200/2500m environ.
Vers les crêtes un effondrement spontané de corniche n'est pas exclu.

**Déclenchements provoqués :**

Peu de risque de plaque a priori, ou une mince accumulation en altitude, sous le vent d'Est ? En journée en pentes soutenues et bien humidifiées, plutôt un risque de coulée ponctuelle sous les skis...

**Autres :** Regel superficiel mardi matin, neige parfois croutée/cassante. En journée neige très humide à "soupe" selon le versant, ski parfois difficile...

## Qualité de la neige

**Qualification de l'enneigement :** L'enneigement s'est dégradé depuis 10 jours mais reste assez important en faces peu ensoleillées et en combes d'altitude....
**Limites skiables :** Vers 1500m au Nord à 1800/2100m au soleil suivant l'exposition, la raideur de la pente...

**Qualité de la neige mardi :** Hauts sommets saupoudrés la veille.
Mardi matin faible regel au dessus de 2000/2200m (croute parfois cassante ?) puis rapide humidification, en tous versants avec les nuages... neige très humide, plus "molle" en versants froids.

## Aperçu météo pour le mardi 14 avril

| | nuit | matin | après-midi | soir |
|---|---|---|---|---|
| | | | | |

Quelques flocons lundi soir, puis temps nuageux, regel local en altitude.. Mardi très nuageux, brouillard sous 2500 puis 2800m environ...

| | | | | |
|---|---|---|---|---|
| **Pluie-Neige** | 1 700 m | | | |
| **Iso 0 °C** | 2 300 m | 2 700 m | 2 700 m | 2 800 m |
| **Vent 2000 m** | ↙ 10 km/h | ↙ 15 km/h | ↓ 20 km/h | ← 10 km/h |
| **Vent 3000 m** | ↙ 20 km/h | ↙ 15 km/h | ↓ 15 km/h | ↙ 15 km/h |

## Épaisseur de neige hors-piste

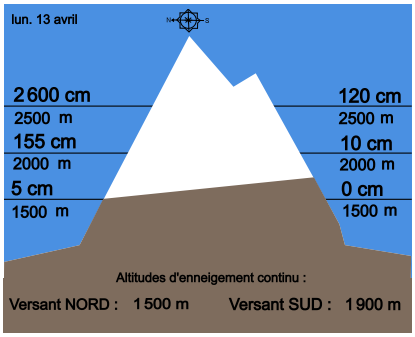


## Précipitations à 1800 m

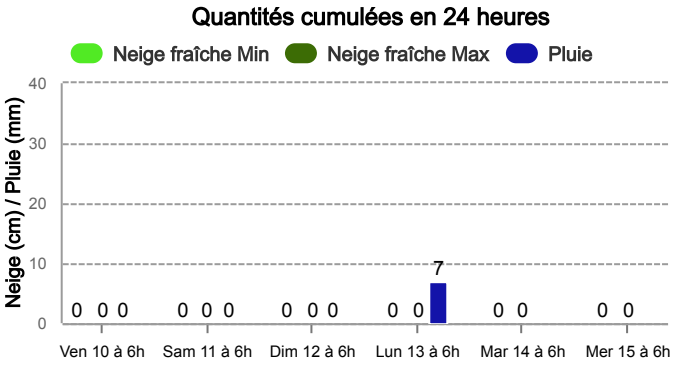


## Tendance du mercredi 15 avril

2

**Indice de risque limité**

Risque en légère baisse mercredi.
Meilleur regel le matin, puis douceur en journée, rares avalanches humides en pente raide...

Pour consulter la vigilance en cours, veuillez vous rendre sur le site https://vigilance.meteofrance.fr/fr

Météo-France - 73 avenue de Paris, 94165 Saint-Mandé cedex - Contact : contact@meteo.fr

Rédigé par Météo-France avec la contribution des observateurs du réseau nivo-météorologiques. Partenariat : ANMSM (Maires de Stations de Montagne), DSF (Domaines Skiables de France), ADSP (Directeurs de Pistes et de la Sécurité des Stations de Sports d'Hiver) et autres acteurs de la montagne.

Bulletin neige & avalanches par téléphone au

**0 892 68 10 20** Service 0,35 € / min + prix appel

# Bulletin d'estimation du risque d'avalanche

(valable en dehors des pistes balisées et ouvertes)

# MASSIF : Grandes-Rousses

Rédigé le lundi 13 avril 2026 à 16h

## Conditions nivo-météo des 7 derniers jours

| | mar. 07/04 | | | | mer. 08/04 | | | | jeu. 09/04 | | | | ven. 10/04 | | | | sam. 11/04 | | | | dim. 12/04 | | | | lun. 13/04 | | | |
|---|---|---|---|---|---|---|---|---|---|---|---|---|---|---|---|---|---|---|---|---|---|---|---|---|---|---|---|---|
| | 03h | 09h | 15h | 21h | 03h | 09h | 15h | 21h | 03h | 09h | 15h | 21h | 03h | 09h | 15h | 21h | 03h | 09h | 15h | 21h | 03h | 09h | 15h | 21h | 03h | 09h | 15h | 21h |
| Météo | | | | | | | | | | | | | | | | | | | | | | | | | | | | |
| Vent (km/h) | 10 | 0 | 5 | 10 | 15 | 5 | 5 | 5 | 10 | 20 | 20 | 30 | 35 | 25 | 25 | 20 | 20 | 20 | 25 | 20 | 25 | 25 | 25 | 25 | 40 | 45 | 35 | 20 |
| à 3000m | | | | | | | | | | | | | | | | | | | | | | | | | | | | |
| Vent (km/h) | 5 | 0 | 5 | 5 | 10 | 0 | 0 | 5 | 5 | 10 | 20 | 25 | 20 | 20 | 10 | 0 | 10 | 10 | 15 | 10 | 10 | 15 | 20 | 15 | 20 | 15 | 15 | 10 |
| à 2000m | | | | | | | | | | | | | | | | | | | | | | | | | | | | |

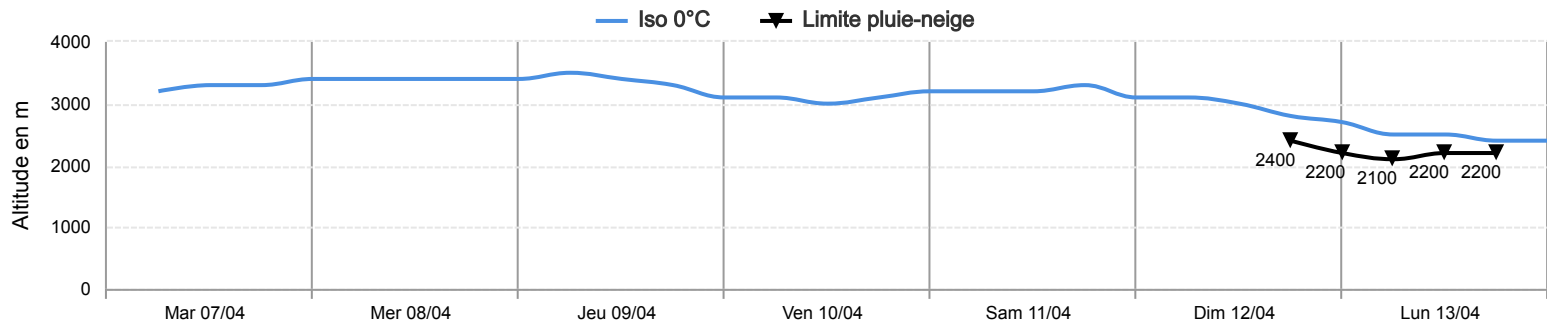


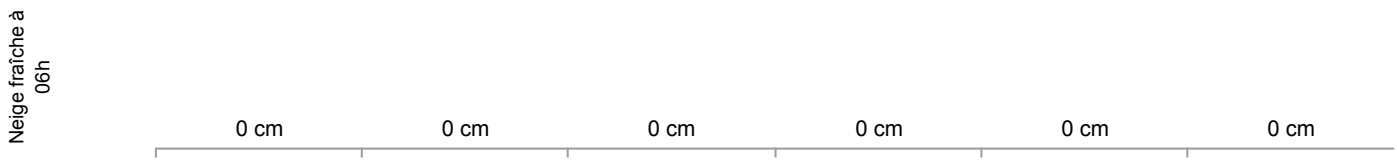


| Risque d'avalanche | mar. 07/04 | mer. 08/04 | jeu. 09/04 | ven. 10/04 | sam. 11/04 | dim. 12/04 | lun. 13/04 |
|---|---|---|---|---|---|---|---|
| | 2 | 2 | 2 | 2 | 2 | 2 | 2 |

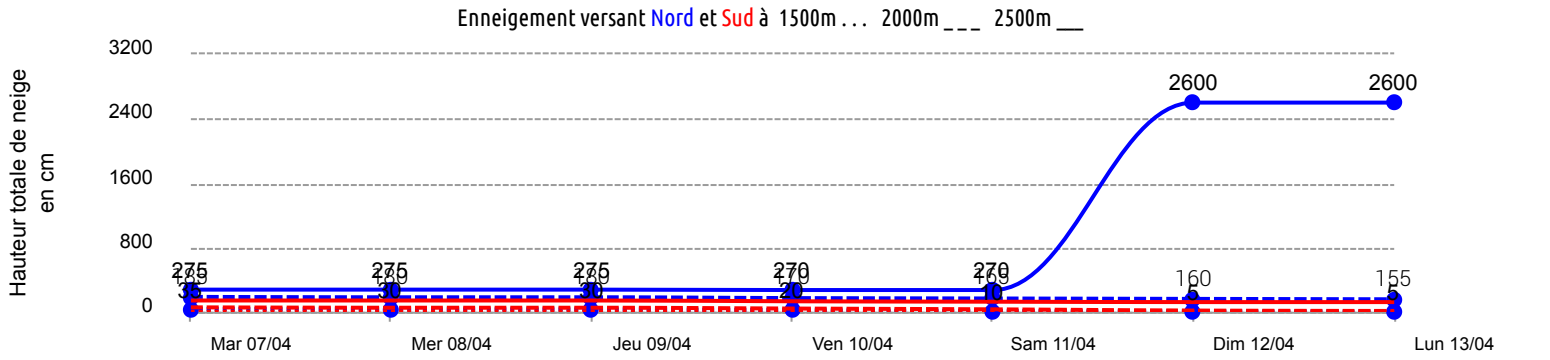


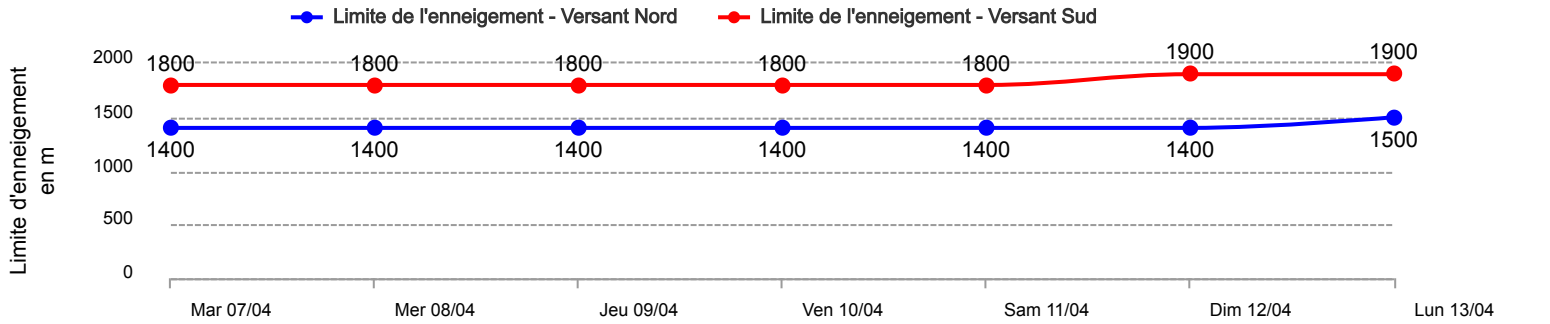


Pour consulter la vigilance en cours, veuillez vous rendre sur le site https://vigilance.meteofrance.fr/fr


Météo-France - 73 avenue de Paris, 94165 Saint-Mandé cedex - Contact : contact@meteo.fr



Rédigé par Météo-France avec la contribution des observateurs du réseau nivo-météorologiques. Partenariat : ANMSM (Maires de Stations de Montagne), DSF (Domaines Skiables de France), ADSP (Directeurs de Pistes et de la Sécurité des Stations de Sports d'Hiver) et autres acteurs de la montagne.



Bulletin neige & avalanches par téléphone au 0 892 68 10 20 Service 0,35 € / min + prix appel