RÉPUBLIQUE FRANÇAISE
Liberté Égalité Fraternité

METEO FRANCE
À VOS CÔTÉS, DANS UN CLIMAT QUI CHANGE

Bulletin d'estimation du risque d'avalanche
(valable en dehors des pistes balisées et ouvertes)
MASSIF : Haut-Var Haut-Verdon

Rédigé le lundi 13 avril 2026 à 16h

Estimation des risques pour le : MARDI 14 AVRIL

MANTEAU NEIGEUX BIEN HUMIDE ET PLUTÔT STABLE

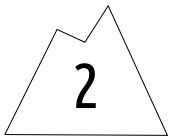

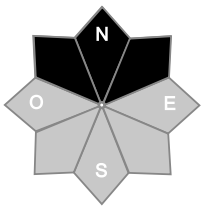

Indice de risque limité.

Départs spontanés : taille moyenne en neige humide

Déclenchements provoqués : dans la neige humide, taille moyenne

Indices de risque : 5 très fort - 4 fort - 3 marqué - 2 limité - 1 faible -- En noir : les pentes les plus dangereuses

Stabilité du manteau neigeux

Situation avalancheuse typique : neige humide couche fragile persistante

Déclenchements provoqués : manteau neigeux bien dense et plutôt stable. Les instabilités se situent surtout en orientations nord-ouest, nord et nord-est d'altitude comprise entre 2200 et 2600 m environ. Un seul skieur peut parfois déclencher une avalanche de taille moyenne, très rarement grande. Le manteau neigeux est bien humide, mais des couches fragiles sont encore localement sollicitables à sa base.
Sous 2200 m, manteau neigeux entièrement transformé et bien stable.

Départs spontanés : rares avalanches de neige humide de taille moyenne, parfois sous forme d'avalanches de glissement en orientations nord-ouest, nord et nord-est d'altitude.

Qualité de la neige

Enneigement proche des normales pour la saison.
Hauteurs de neige observées : vers 2000 m, 122 cm dans le vallon de Valdemars en Haut Verdon, 55 cm à la Sanguinière dans le Haut-Var.

Enneigement skiable généralement à partir de 1800 m en terrain favorable (routes forestières, terrains herbeux) et 2200/2300 m en adrets peu pentus.

État de la neige en surface : manteau neigeux humide et mal regelé sous 2500/2600 m, plus souvent regelé au-dessus, saupoudré d'un peu de neige récente, 10/15 cm possible vers 2800 m...
Humidification plus nette sous les éclaircies plus généreuses ce mardi

Aperçu météo pour le mardi 14 avril

	nuit	matin	après-midi	soir
Belles éclaircies l'après-midi, redoux.				
Pluie-Neige	2 500 m			
Iso 0 °C	2 700 m	2 700 m	2 700 m	2 700 m
Vent 2000 m	↓ 25 km/h	↓ 30 km/h	↓ 25 km/h	↓ 20 km/h
Vent 3000 m	← 40 km/h	← 35 km/h	← 35 km/h	← 25 km/h

Épaisseur de neige hors-piste

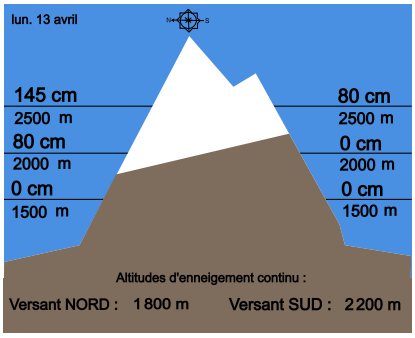

Précipitations à 1800 m

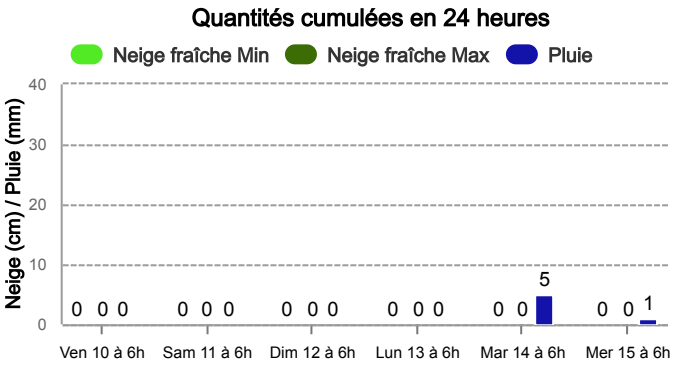

Tendance du mercredi 15 avril

Indice de risque limité

Peu d'évolution de la situation nivologique.
Risque limité, piloté par la neige humide

Pour consulter la vigilance en cours, veuillez vous rendre sur le site https://vigilance.meteofrance.fr/fr

Météo-France - 73 avenue de Paris, 94165 Saint-Mandé cedex - Contact : contact@meteo.fr

Rédigé par Météo-France avec la contribution des observateurs du réseau nivo-météorologiques. Partenariat : ANMSM (Maires de Stations de Montagne), DSF (Domaines Skiables de France), ADSP (Directeurs de Pistes et de la Sécurité des Stations de Sports d'Hiver) et autres acteurs de la montagne.

Bulletin neige & avalanches par téléphone au
0 892 68 10 20 Service 0,35 € / min + prix appel

Bulletin d'estimation du risque d'avalanche

(valable en dehors des pistes balisées et ouvertes)

MASSIF : Haut-Var Haut-Verdon

Rédigé le lundi 13 avril 2026 à 16h

Conditions nivo-météo des 7 derniers jours

	mar. 07/04				mer. 08/04				jeu. 09/04				ven. 10/04				sam. 11/04				dim. 12/04				lun. 13/04			
	03h	09h	15h	21h	03h	09h	15h	21h	03h	09h	15h	21h	03h	09h	15h	21h	03h	09h	15h	21h	03h	09h	15h	21h	03h	09h	15h	21h
Météo																												
Vent (km/h)	20	15	15	15	10	10	15	15	15	15	25	35	40	20	30	25	25	25	30	15	15	20	25	25	25	30	35	40
à 3000m																												
Vent (km/h)	10	10	15	10	5	10	15	10	5	10	20	20	20	15	25	15	20	15	20	10	10	15	25	35	35	25	25	25
à 2000m																												

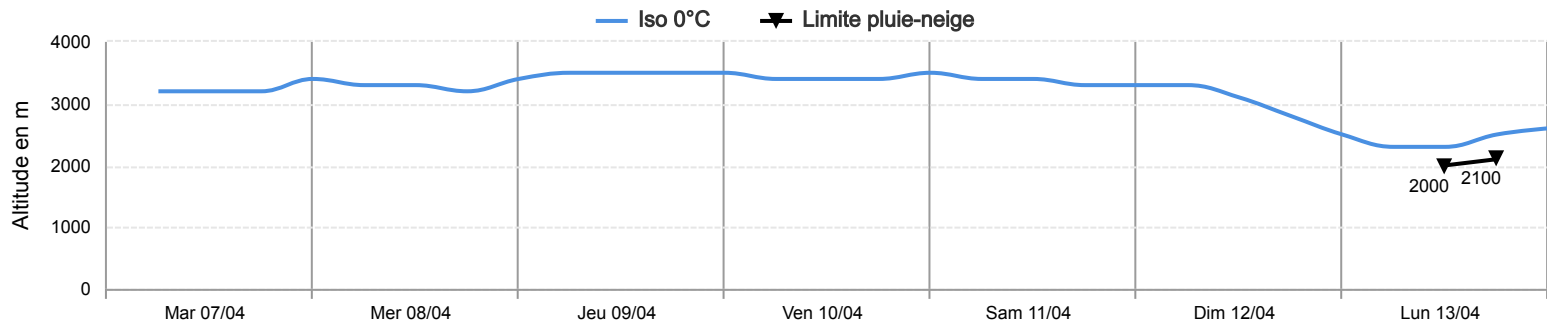

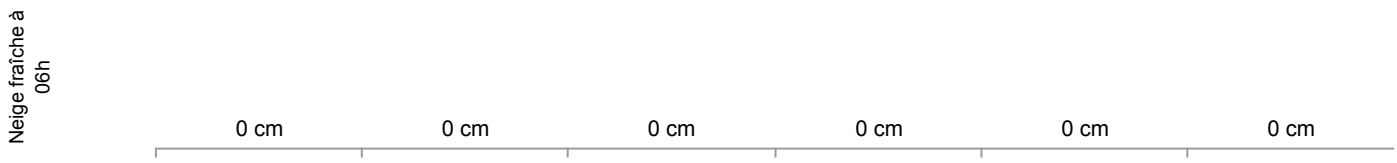

Risque d'avalanche	mar. 07/04	mer. 08/04	jeu. 09/04	ven. 10/04	sam. 11/04	dim. 12/04	lun. 13/04
	2	2	3	3	3	2	2

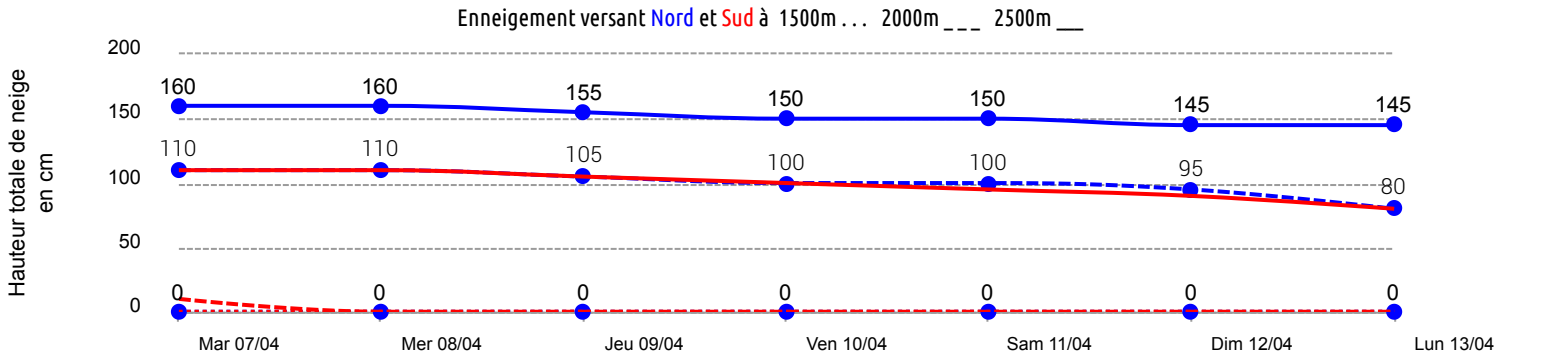

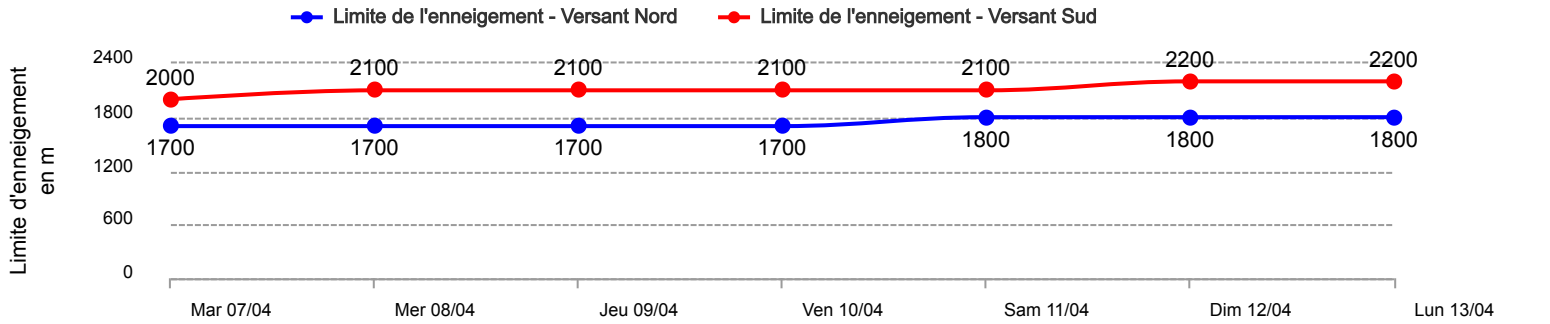

Pour consulter la vigilance en cours, veuillez vous rendre sur le site https://vigilance.meteofrance.fr/fr

Météo-France - 73 avenue de Paris, 94165 Saint-Mandé cedex - Contact : contact@meteo.fr

Rédigé par Météo-France avec la contribution des observateurs du réseau nivo-météorologiques. Partenariat : ANMSM (Maires de Stations de Montagne), DSF (Domaines Skiables de France), ADSP (Directeurs de Pistes et de la Sécurité des Stations de Sports d'Hiver) et autres acteurs de la montagne.

Bulletin neige & avalanches par téléphone au 0 892 68 10 20 Service 0,35 € / min + prix appel