Bulletin d'estimation du risque d'avalanche
(valable en dehors des pistes balisées et ouvertes)

MASSIF : Haute-Ariege

Rédigé le lundi 13 avril 2026 à 16h

Estimation des risques pour le : MARDI 14 AVRIL

PLAQUES EN ALTITUDE, DES COULÉES AU SOLEIL

2

2

N O E S

Indice de risque limité.

Départs spontanés : Fréquentes coulées de surface

Déclenchements provoqués : Plaques en altitude

Indices de risque : 5 très fort - 4 fort - 3 marqué - 2 limité - 1 faible -- En noir : les pentes les plus dangereuses

Stabilité du manteau neigeux

Situation avalancheuse typique : neige ventée neige humide

Déclenchements provoqués :
Des plaques plus ou moins friables se sont formées en altitude et pourraient continuer à se former avec le vent de secteur nord, reposant sur des neiges tombées sans vent. Ces plaques peuvent parfois être déclenchées au passage d'un simple randonneur. Ce risque se cantonne progressivement au-dessus de 2400m et dans les versants ombragés restés en neige sèche, du fait de l'humidification en journée. Un skieur coupant une pente en neige pourrie pourra également déclencher une coulée sous ses skis.
Observables : transport de la neige par le vent, disparition des traces de montée, fissures devant les skis.

Départs spontanés :
Du fait d'un soleil efficace et de la remontée de l'isotherme 0 °C de nombreuses coulées de surface se produisent dans les pentes suffisamment raides prenant le soleil, donc plutôt dans les versants d'un vaste secteur Est puis Sud puis Ouest. De rares cassures linéaires peuvent également se produire générant des avalanches de taille moyenne.
Observables : neige pourrie, escargots.

Qualité de la neige

Enneigement :
L'enneigement demeure excellent pour la saison, un des meilleurs des 30 dernières années. Les nouvelles chutes de neige blanchissent à nouveau la montagne dès 1200 à 1300m d'altitude mais il faut en général atteindre 1400 à 1500m pour trouver une sous-couche versant Nord et parfois 1800m en versant Sud. Cette couche augmente très vite en prenant de l'altitude avec des cumuls dépassant parfois les 2m dès 1900m, 3 à 4 m vers 2500m.

Qualité de la neige :
Mardi matin, on trouve une couche de neige fraîche ou récente dès 1300m. En journée cette neige s'humidifie rapidement au soleil et ne reste sèche que dans les versants nord restant à l'ombre, ou au-dessus de 2400m. Quelques cols et crêtes risquent de rester en neige très dure voire en glace à haute altitude.

Aperçu météo pour le mardi 14 avril

Journée ensoleillée accompagnée d'un net redoux

	nuit	matin	après-midi	soir
Pluie-Neige	1 100 m			
Iso 0 °C	1 400 m	1 600 m	2 000 m	2 300 m
Vent 2000 m	25 km/h	20 km/h	25 km/h	15 km/h
Vent 3000 m	50 km/h	45 km/h	40 km/h	30 km/h

Épaisseur de neige hors-piste

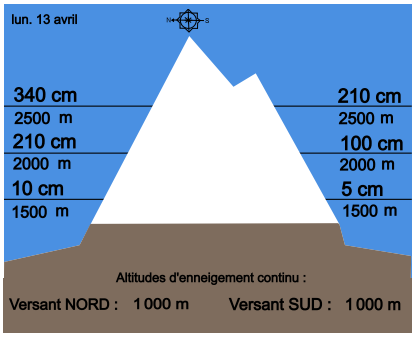

Précipitations à 1800 m

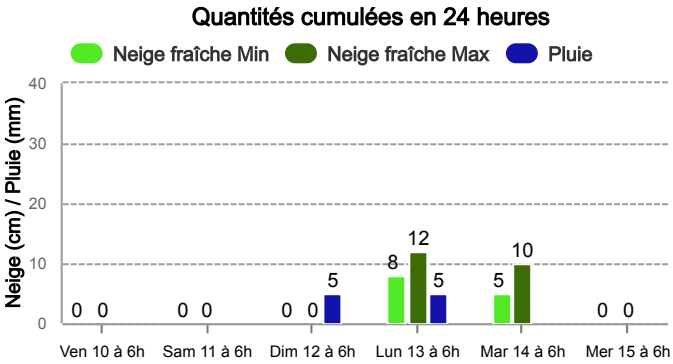

Tendance du mercredi 15 avril

2

Indice de risque limité

Maintien d'un risque limité avec une poursuite de l'humidification et une stabilisation progressive des plaques

Pour consulter la vigilance en cours, veuillez vous rendre sur le site https://vigilance.meteofrance.fr/fr

Météo-France - 73 avenue de Paris, 94165 Saint-Mandé cedex - Contact : contact@meteo.fr

Rédigé par Météo-France avec la contribution des observateurs du réseau nivo-météorologiques. Partenariat : ANMSM (Maires de Stations de Montagne), DSF (Domaines Skiables de France), ADSP (Directeurs de Pistes et de la Sécurité des Stations de Sports d'Hiver) et autres acteurs de la montagne.

Bulletin neige & avalanches par téléphone au
0 892 68 10 20 Service 0,35 € / min + prix appel

RÉPUBLIQUE FRANÇAISE
Liberté Égalité Fraternité

METEO FRANCE
À VOS CÔTÉS, DANS UN CLIMAT QUI CHANGE

Bulletin d'estimation du risque d'avalanche
(valable en dehors des pistes balisées et ouvertes)
MASSIF : Haute-Ariege

Rédigé le lundi 13 avril 2026 à 16h

Conditions nivo-météo des 7 derniers jours

	mar. 07/04				mer. 08/04				jeu. 09/04				ven. 10/04				sam. 11/04				dim. 12/04				lun. 13/04			
	03h	09h	15h	21h	03h	09h	15h	21h	03h	09h	15h	21h	03h	09h	15h	21h	03h	09h	15h	21h	03h	09h	15h	21h	03h	09h	15h	21h
Météo																												
Vent (km/h)	30	25	20	20	30	35	35	25	20	20	20	20	20	20	20	30	30	35	45	45	45	30	25	20	45	50	45	50
à 3000m																												
Vent (km/h)	20	15	15	10	20	20	20	15	10	10	10	10	10	10	10	20	20	25	35	35	15	15	15	15	15	30	30	30
à 2000m																												

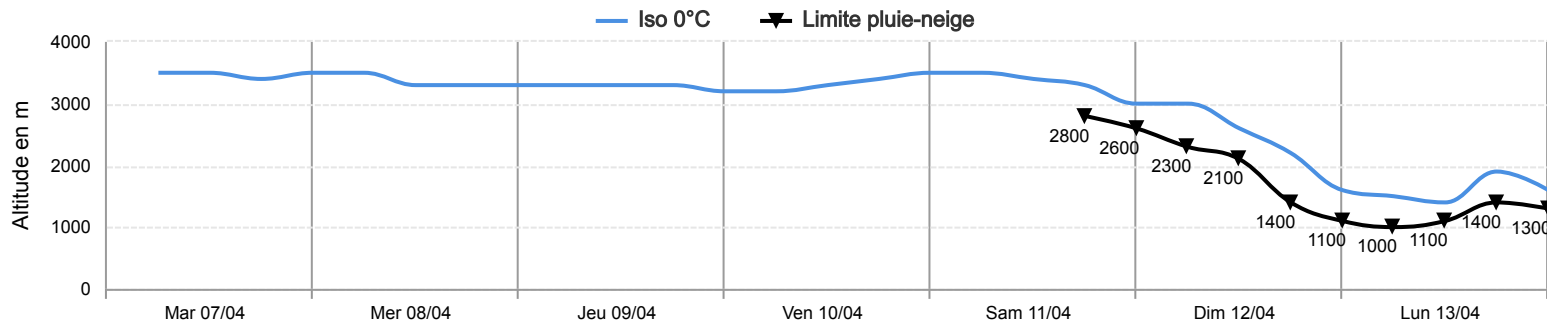

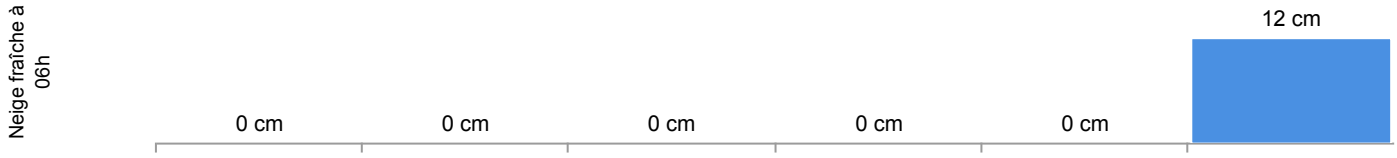

Risque d'avalanche	mar. 07/04	mer. 08/04	jeu. 09/04	ven. 10/04	sam. 11/04	dim. 12/04	lun. 13/04
	2	2	2	2	3	2	3

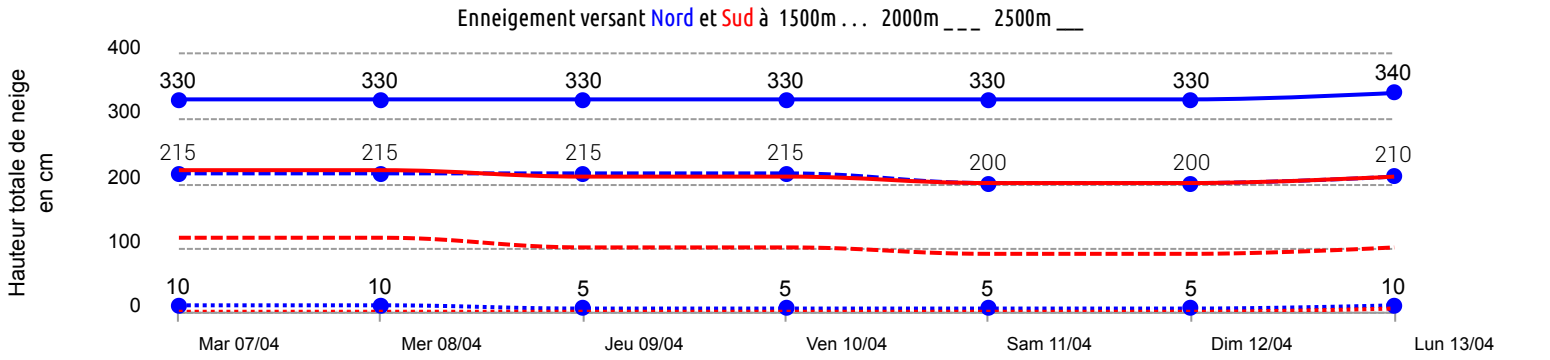

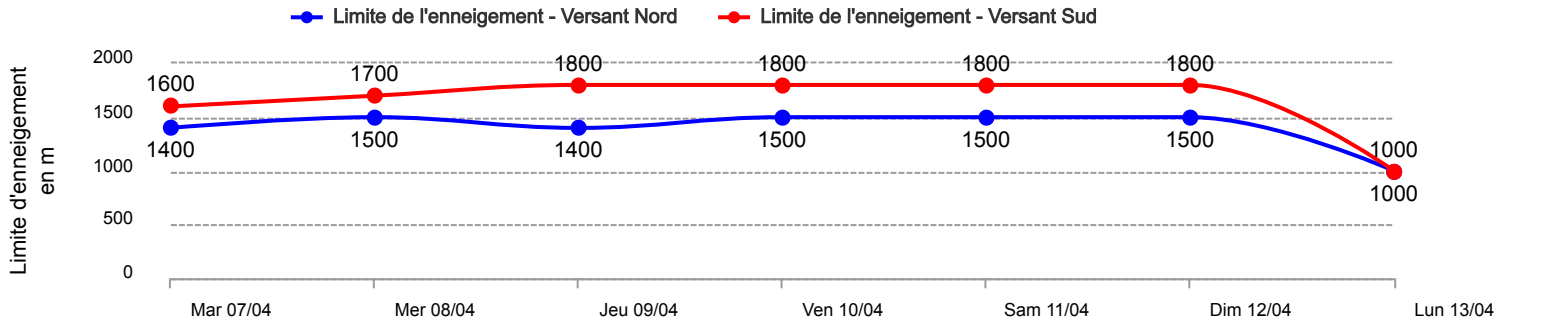

Pour consulter la vigilance en cours, veuillez vous rendre sur le site https://vigilance.meteofrance.fr/fr

Météo-France - 73 avenue de Paris, 94165 Saint-Mandé cedex - Contact : contact@meteo.fr

Rédigé par Météo-France avec la contribution des observateurs du réseau nivo-météorologiques. Partenariat : ANMSM (Maires de Stations de Montagne), DSF (Domaines Skiables de France), ADSP (Directeurs de Pistes et de la Sécurité des Stations de Sports d'Hiver) et autres acteurs de la montagne.

Bulletin neige & avalanches par téléphone au
0 892 68 10 20 Service 0,35 € / min + prix appel