Bulletin d'estimation du risque d'avalanche

(valable en dehors des pistes balisées et ouvertes)

MASSIF : Haute-Bigorre

Rédigé le lundi 13 avril 2026 à 16h

Estimation des risques pour le : MARDI 14 AVRIL

PLAQUES EN ALTITUDE, HUMIDIFICATION RAPIDE

2

2

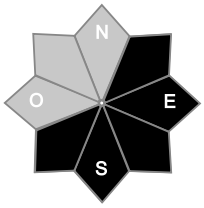

Indice de risque limité.

Départs spontanés : ponctuels dans la neige récente

Déclenchements provoqués : plaques décelenchables au-dessus de 2000 à 2200m

Indices de risque : 5 très fort - 4 fort - 3 marqué - 2 limité - 1 faible -- En noir : les pentes les plus dangereuses

Stabilité du manteau neigeux

Situation avalancheuse typique : neige ventée — neige humide

Déclenchements provoqués :
Des plaques se sont formées lors des dernières chutes de neige. Elles sont assez rares, limitées aux zones d'accumulation suffisante, instables surtout au-dessus de 2000 à 2200. Plus bas, les éclaircies de lundi ont bien tassé la neige fraîche. On les trouve plutôt près des cols et crêtes, formées par un vent modéré, dans les orientations à l'abri du vent de nord-nord-ouest. Elles sont rapidement stabilisées en versants ensoleillés, mais persistent en versants ombragés.

Départs spontanés :
Principalement des départs ponctuels de petite taille, dans la neige récente, au fil de l'ensoleillement (versants, est, puis sud, puis ouest). Quelques moyennes sont possibles avec le départ spontané d'une plaque au-dessus de 2000m en versant ensoleillé. Une plus grande par départ d'une avalanche de fond est moins probable mardi après cette période de rafraîchissement.

Qualité de la neige

Enneigement : L'enneigement est bon pour la saison, débutant vers 1500m en nord, 1700m en sud. Saupoudrage ou quelques centimètres de neige sur un sol nu sous ces limites.

État de la neige :une petite épaisseur de neige récente, assez légère mardi matin, mais s'humidifiant rapidement.

Cette neige récente repose sur un sol nu en sud sous 1900m et sous 1600m en nord. Plus haut, souvent sur de la vieille neige humide à peine ou mal regelée mais portante.

Aperçu météo pour le mardi 14 avril

	nuit	matin	après-midi	soir

Largement ensoleillé, matinée fraîche, remontée des tempratures l'après-midi

Pluie-Neige	1 200 m			
Iso 0 °C	1 600 m	2 100 m	2 400 m	2 800 m
Vent 2000 m	15 km/h	20 km/h	20 km/h	10 km/h
Vent 3000 m	50 km/h	55 km/h	45 km/h	30 km/h

Épaisseur de neige hors-piste

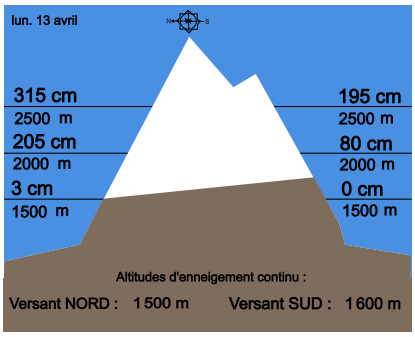

Précipitations à 1800 m

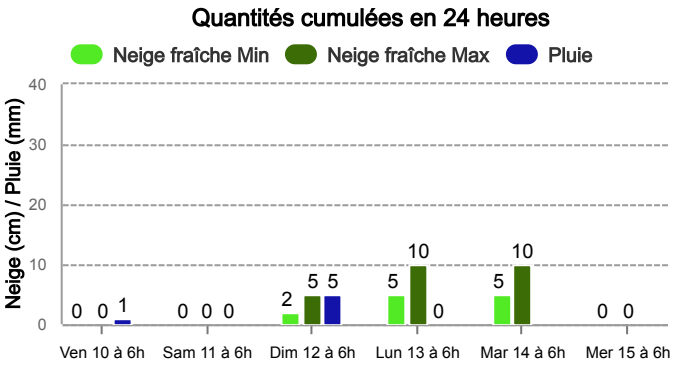

Tendance du mercredi 15 avril

2

Indice de risque limité

Persistance de quelques plaques en pentes ombragées d'altitude, conditions printanières ailleurs.

Pour consulter la vigilance en cours, veuillez vous rendre sur le site https://vigilance.meteofrance.fr/fr

Météo-France - 73 avenue de Paris, 94165 Saint-Mandé cedex - Contact : contact@meteo.fr

Rédigé par Météo-France avec la contribution des observateurs du réseau nivo-météorologiques. Partenariat : ANMSM (Maires de Stations de Montagne), DSF (Domaines Skiables de France), ADSP (Directeurs de Pistes et de la Sécurité des Stations de Sports d'Hiver) et autres acteurs de la montagne.

Bulletin neige & avalanches par téléphone au 0 892 68 10 20 Service 0,35 € / min + prix appel

Bulletin d'estimation du risque d'avalanche

(valable en dehors des pistes balisées et ouvertes)

MASSIF : Haute-Bigorre

Rédigé le lundi 13 avril 2026 à 16h

Conditions nivo-météo des 7 derniers jours

	mar. 07/04				mer. 08/04				jeu. 09/04				ven. 10/04				sam. 11/04				dim. 12/04				lun. 13/04			
	03h	09h	15h	21h	03h	09h	15h	21h	03h	09h	15h	21h	03h	09h	15h	21h	03h	09h	15h	21h	03h	09h	15h	21h	03h	09h	15h	21h
Météo																												
Vent (km/h)	45	40	30	30	30	20	20	25	20	20	15	10	20	35	35	45	50	45	35	60	30	25	20	30	55	45	35	30
à 3000m																												
Vent (km/h)	25	20	10	20	20	10	10	5	5	10	10	5	5	10	10	20	30	25	10	15	5	10	10	10	20	20	15	10
à 2000m																												

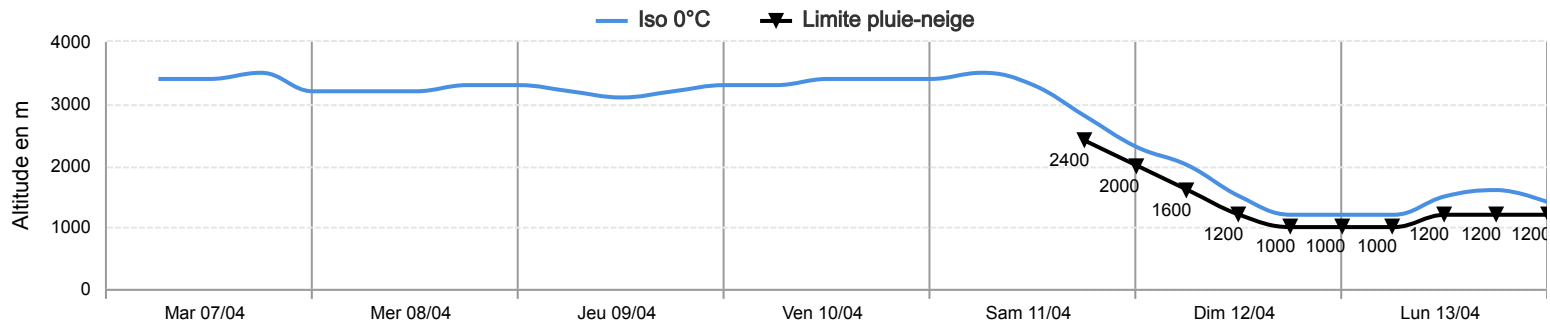

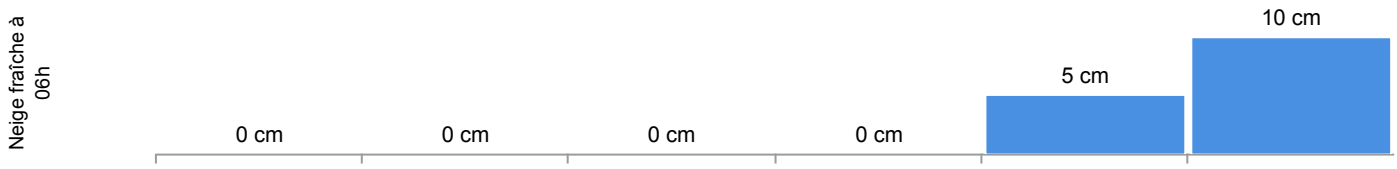

Risque d'avalanche	mar. 07/04	mer. 08/04	jeu. 09/04	ven. 10/04	sam. 11/04	dim. 12/04	lun. 13/04
	2	2	2	2	2	2	3

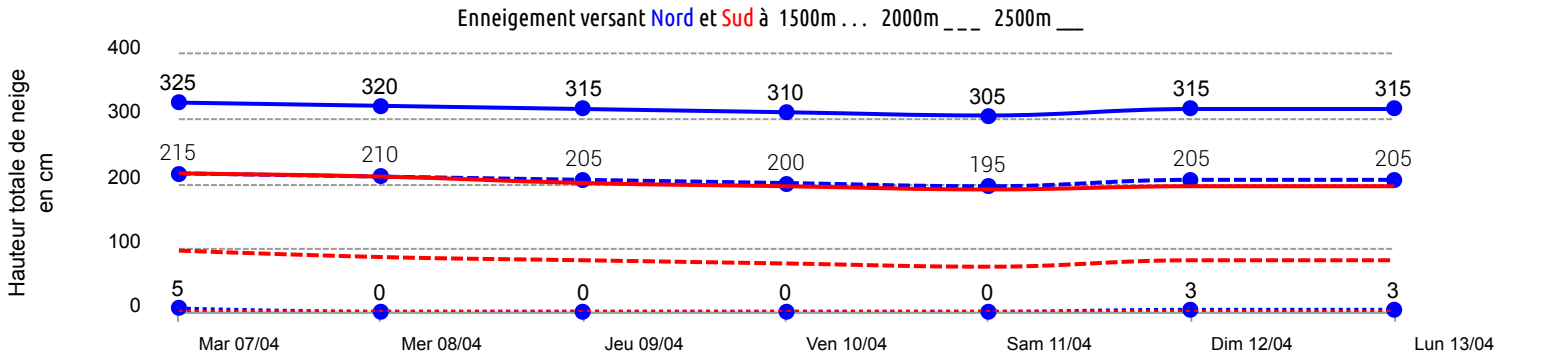

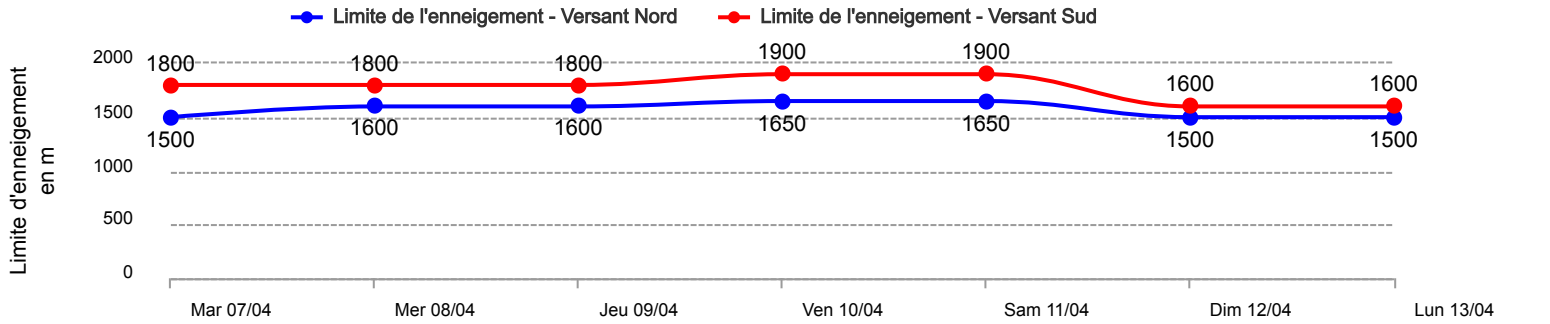

Pour consulter la vigilance en cours, veuillez vous rendre sur le site https://vigilance.meteofrance.fr/fr

Météo-France - 73 avenue de Paris, 94165 Saint-Mandé cedex - Contact : contact@meteo.fr

Rédigé par Météo-France avec la contribution des observateurs du réseau nivo-météorologiques. Partenariat : ANMSM (Maires de Stations de Montagne), DSF (Domaines Skiables de France), ADSP (Directeurs de Pistes et de la Sécurité des Stations de Sports d'Hiver) et autres acteurs de la montagne.

Bulletin neige & avalanches par téléphone au

0 892 68 10 20 Service 0,35 € / min + prix appel