RÉPUBLIQUE FRANÇAISE
Liberté Égalité Fraternité

METEO FRANCE
À VOS CÔTÉS, DANS UN CLIMAT QUI CHANGE

Bulletin d'estimation du risque d'avalanche
(valable en dehors des pistes balisées et ouvertes)
MASSIF : Haute-Maurienne

Rédigé le lundi 13 avril 2026 à 16h

Estimation des risques pour le : MARDI 14 AVRIL

INSTABILITÉS TEMPORAIRES EN NEIGE RÉCENTE ET HUMIDIFICATION RAPIDE.

3

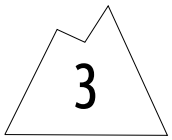

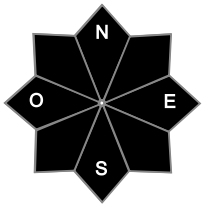

Indice de risque marqué.

Départs spontanés : Quelques départs humides en bas; secs et parfois volumineux en haut.

Déclenchements provoqués : quelques plaques réactives en altitude et plaques d'aspect humide plus bas.

Indices de risque : 5 très fort - 4 fort - 3 marqué - 2 limité - 1 faible -- En noir : les pentes les plus dangereuses

Stabilité du manteau neigeux

Situation avalancheuse typique : neige fraîche neige humide

Départs spontanés : - quelques avalanches par humidification de la neige récente, plus fréquents l'après-midi. Elles sont attendues en **tous versants** avec le retour des éclaircies et **même en nord avec l'effet des nuages**. Ce sont principalement des **départs ponctuels (poires)**, donnant des petites à moyennes avalanches mais aussi plus rarement des cassures **linéaires (plaques) donnant alors de grandes avalanches (taille 3)** car l'eau de fonte qui percole dans le manteau atteint désormais les couches fragiles enfouies du début de saison. **Ces cassures linéaires semblent plus probables en versants Est/Nord/Ouest, sous 2700 m**.
- **Rares avalanches de glissement** (plaques de fond) à toute heure sur terrain propice, notamment en Nord sous 2500/2600 m. Taille 2.

Déclenchements provoqués :
- Le matin au dessus de 2500 m et par la suite uniquement en versants froids de haute altitude, quelques plaques réactives d'aspect poudreux sont en place, surtout près des crêtes et vers la frontière italienne. Toute pente suffisamment raide est concernée.
- En journée, avalanches de neige humide (pourrie) sous les skis en coupant une pente trop humidifiée au fil des heures, avec les nuages toutes les orientations chauffent en même temps. Coulées sous les skis voire cassure linéaire pouvant donner une rare grande avalanche quand les couches fragiles du début de saison s'humidifient.

Qualité de la neige

Enneigement : l'enneigement est revenu au niveau des normales suite à la chaleur des derniers jours, le chauffage et la présence des nuages accélèrent la fonte.

Limite skiable : vers 1400 m en Nord, 1800/1900 m en Sud.

Qualité de la neige : Sous les 2000/2200 m, neige pourrie par la pluie, au-dessus, la couche de neige fraîche s'épaissit vite, surtout près de la frontière (des Lévanna à la dent d'Ambin). Toutefois la neige s'humidifie vite, y compris en versant nord avec les nuages, la neige botte facilement. En versants nord de haute altitude on peut trouver de la poudreuse un peu dense par endroit.

Aperçu météo pour le mardi 14 avril

Éclaircies le matin, nuages de plus en plus présents en journée, températures en hausse.

	nuit	matin	après-midi	soir
Pluie-Neige	1 800 m			
Iso 0 °C	2 300 m	2 800 m	2 800 m	2 700 m
Vent 2500 m	← 15 km/h	← 20 km/h	→ 20 km/h	← 10 km/h
Vent 3500 m	← 20 km/h	← 25 km/h	↙ 25 km/h	↙ 15 km/h

Épaisseur de neige hors-piste

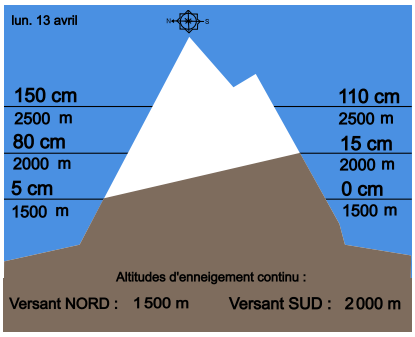

Précipitations à 1800 m

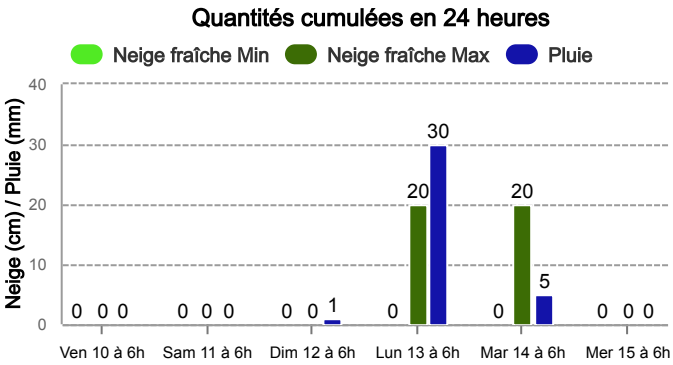

Tendance du mercredi 15 avril

3

Indice de risque marqué

Encore des nuages et des températures élevées favorisant l'activité en neige humide, risque marqué stationnaire.

Pour consulter la vigilance en cours, veuillez vous rendre sur le site https://vigilance.meteofrance.fr/fr

Météo-France - 73 avenue de Paris, 94165 Saint-Mandé cedex - Contact : contact@meteo.fr

Rédigé par Météo-France avec la contribution des observateurs du réseau nivo-météorologiques. Partenariat : ANMSM (Maires de Stations de Montagne), DSF (Domaines Skiables de France), ADSP (Directeurs de Pistes et de la Sécurité des Stations de Sports d'Hiver) et autres acteurs de la montagne.

Bulletin neige & avalanches par téléphone au
0 892 68 10 20 Service 0,35 € / min + prix appel

RÉPUBLIQUE FRANÇAISE
Liberté Égalité Fraternité

METEO FRANCE
À VOS CÔTÉS, DANS UN CLIMAT QUI CHANGE

Bulletin d'estimation du risque d'avalanche
(valable en dehors des pistes balisées et ouvertes)
MASSIF : Haute-Maurienne

Rédigé le lundi 13 avril 2026 à 16h

Conditions nivo-météo des 7 derniers jours

	mar. 07/04				mer. 08/04				jeu. 09/04				ven. 10/04				sam. 11/04				dim. 12/04				lun. 13/04			
	03h	09h	15h	21h	03h	09h	15h	21h	03h	09h	15h	21h	03h	09h	15h	21h	03h	09h	15h	21h	03h	09h	15h	21h	03h	09h	15h	21h
Météo																												
Vent (km/h)	10	5	10	10	10	10	10	10	10	15	30	45	20	25	35	20	30	30	25	25	25	30	40	40	40	35	25	25
à 3500m																												
Vent (km/h)	5	0	5	5	5	5	5	5	5	5	20	35	10	20	30	15	10	10	10	15	15	20	30	30	30	25	15	15
à 2500m																												

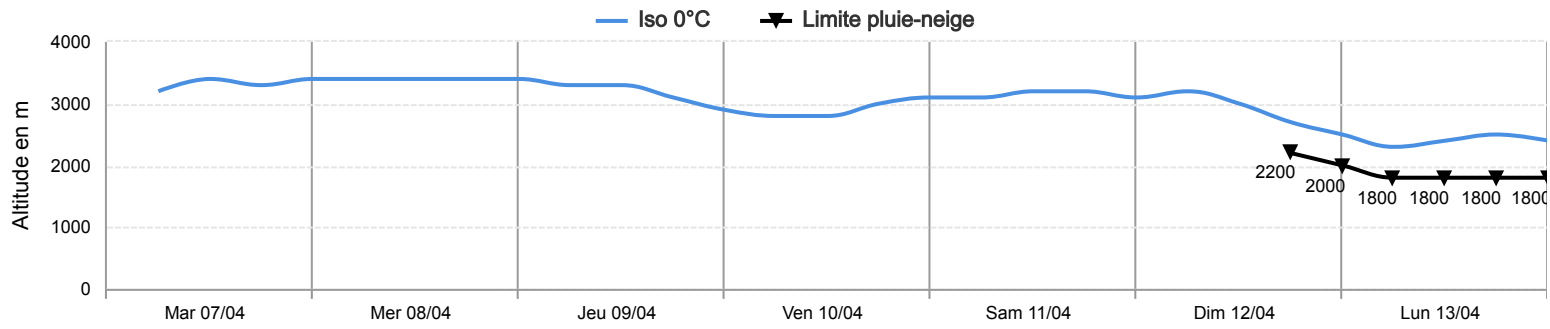

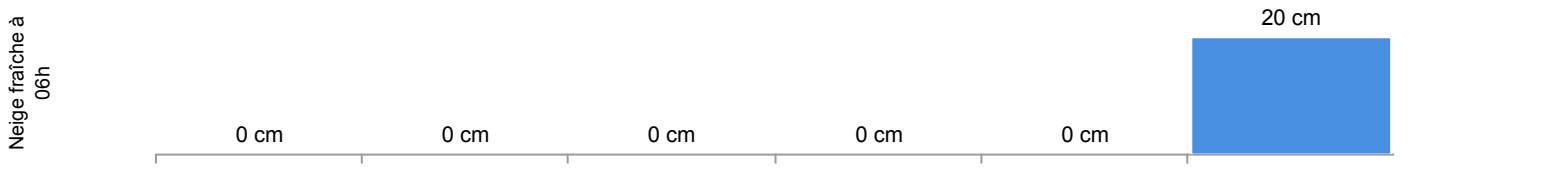

Risque d'avalanche	mar. 07/04	mer. 08/04	jeu. 09/04	ven. 10/04	sam. 11/04	dim. 12/04	lun. 13/04
	2	3	3	3	3	2	3

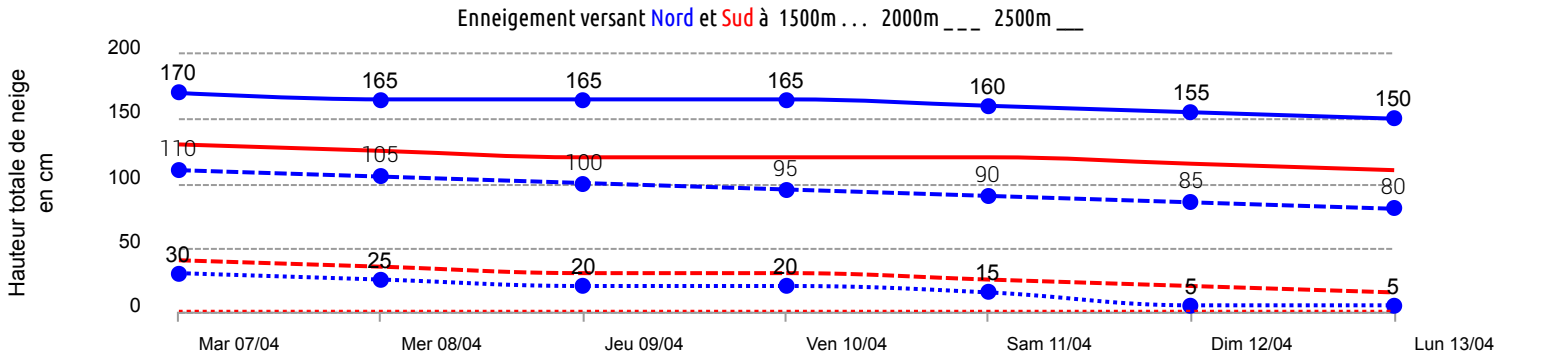

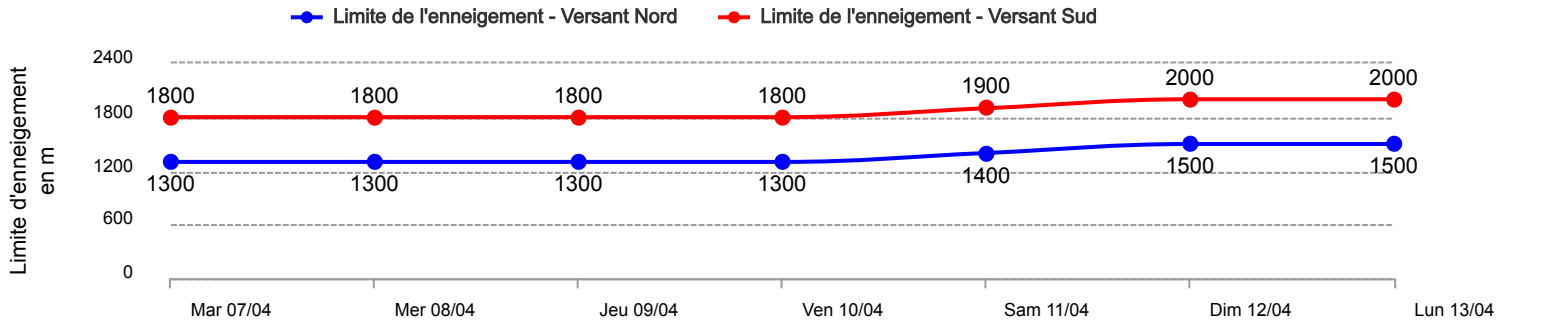

Pour consulter la vigilance en cours, veuillez vous rendre sur le site https://vigilance.meteofrance.fr/fr

Météo-France - 73 avenue de Paris, 94165 Saint-Mandé cedex - Contact : contact@meteo.fr

Rédigé par Météo-France avec la contribution des observateurs du réseau nivo-météorologiques. Partenariat : ANMSM (Maires de Stations de Montagne), DSF (Domaines Skiables de France), ADSP (Directeurs de Pistes et de la Sécurité des Stations de Sports d'Hiver) et autres acteurs de la montagne.

Bulletin neige & avalanches par téléphone au
0 892 68 10 20
Service 0,35 € / min + prix appel