Bulletin d'estimation du risque d'avalanche
(valable en dehors des pistes balisées et ouvertes)

MASSIF : Haute-Tarentaise

Rédigé le lundi 13 avril 2026 à 16h

Estimation des risques pour le : MARDI 14 AVRIL

NUAGES ET CHAUFFAGE, HUMIDIFICATION MÊME EN PLEIN NORD.

2

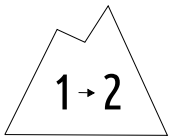

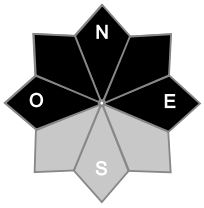

Indice de risque faible évoluant en limité.

Départs spontanés : quelques départs en neige humide.

Déclenchements provoqués : petites coulées voire localement une plaque sous les skis dans la neige fortement humidifiée (pourrie).

Indices de risque : 5 très fort - 4 fort - 3 marqué - 2 limité - 1 faible -- En noir : les pentes les plus dangereuses

Stabilité du manteau neigeux

Situation avalancheuse typique : neige humide couche fragile persistante

Départs spontanés :
- **Quelques départs en neige humide** sont attendus en **tous versants**, ils deviennent **plus fréquents l'après midi**. Ce sont principalement des **départs ponctuels (poires)**, donnant des **petites à moyennes avalanches**. Avec les nuages, les versants nord chauffent et sont donc aussi concernés par ce risque. Plus rarement des cassures **linéaires (plaques) donnant alors de grandes avalanches (taille 3)** car l'eau de fonte qui percole dans le manteau atteint désormais les couches fragiles enfouies du début de saison. **Ces cassures linéaires semblent plus probables en versants Est/Nord/Ouest, sous 2700 m**.
- **Rares avalanches de glissement** (plaques de fond) à toute heure sur terrain propice, notamment en Nord sous 2500/2600 m. Taille 2.

Déclenchements provoqués : avalanche de neige humide (pourrie) sous les skis en coupant une pente trop humidifiée au fil des heures, avec les nuages toutes les orientations chauffent en même temps. Coulées sous les skis voire cassure linéaire pouvant donner une rare grande avalanche quand les couches fragiles du début de saison s'humidifient.

Secteur sources de l'Isère et Pisaillas : En altitude, le retour d'Est de la veille a créé de nouvelles plaques d'aspect poudreux, réactives et on les trouve en toute orientation, plutôt près des crêtes et des ruptures de pentes, au dessus de 2200m. Petites à moyennes avalanches.

Autres : chutes de corniches possibles.

Qualité de la neige

Enneigement : l'enneigement est revenu au niveau des normales suite à la chaleur des derniers jours, le chauffage et la présence des nuages accélèrent la fonte.

Limite skiable : vers 1300 m en Nord, 1700/1800 m en Sud.

Qualité de la neige : Les quelques centimètres de fraiche possibles au dessus de 2200 m se tassent et s'humidifient vite en tous versants même en nord où la neige devient collante. Regel aléatoire et manteau profondément pourri parfois dès le matin. Des sources de l'Isère au Pisaillas, la neige fraîche se tasse et s'humidifie rapidement.

Aperçu météo pour le mardi 14 avril

Éclaircies le matin, nuages de plus en plus présents en journée, températures en hausse.

	nuit	matin	après-midi	soir
Pluie-Neige	1 800 m			
Iso 0 °C	2 300 m	2 800 m	2 800 m	2 700 m
Vent 2500 m	10 km/h	15 km/h	15 km/h	10 km/h
Vent 3500 m	15 km/h	20 km/h	20 km/h	15 km/h

Épaisseur de neige hors-piste

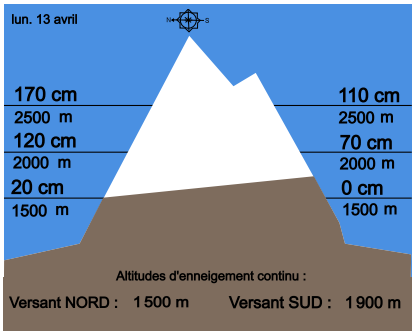

Précipitations à 1800 m

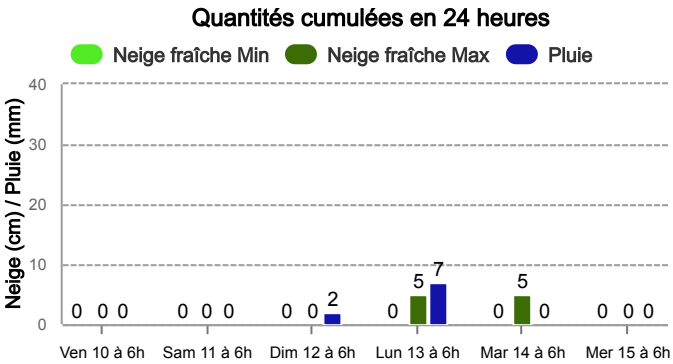

Tendance du mercredi 15 avril

2

Indice de risque limité

Encore des nuages et des températures élevées favorisant l'activité en neige humide, risque limité stationnaire.

Pour consulter la vigilance en cours, veuillez vous rendre sur le site https://vigilance.meteofrance.fr/fr

Météo-France - 73 avenue de Paris, 94165 Saint-Mandé cedex - Contact : contact@meteo.fr

Rédigé par Météo-France avec la contribution des observateurs du réseau nivo-météorologiques. Partenariat : ANMSM (Maires de Stations de Montagne), DSF (Domaines Skiables de France), ADSP (Directeurs de Pistes et de la Sécurité des Stations de Sports d'Hiver) et autres acteurs de la montagne.

Bulletin neige & avalanches par téléphone au 0 892 68 10 20 Service 0,35 € / min + prix appel

RÉPUBLIQUE FRANÇAISE
Liberté Égalité Fraternité

METEO FRANCE
À VOS CÔTÉS, DANS UN CLIMAT QUI CHANGE

Bulletin d'estimation du risque d'avalanche

(valable en dehors des pistes balisées et ouvertes)

MASSIF : Haute-Tarentaise

Rédigé le lundi 13 avril 2026 à 16h

Conditions nivo-météo des 7 derniers jours

	mar. 07/04				mer. 08/04				jeu. 09/04				ven. 10/04				sam. 11/04				dim. 12/04				lun. 13/04			
	03h	09h	15h	21h	03h	09h	15h	21h	03h	09h	15h	21h	03h	09h	15h	21h	03h	09h	15h	21h	03h	09h	15h	21h	03h	09h	15h	21h
Météo																												
Vent (km/h)	10	10	10	15	15	15	15	10	10	15	25	35	20	25	35	20	30	30	25	25	30	30	35	35	40	35	30	25
à 3500m																												
Vent (km/h)	5	5	5	5	5	10	5	5	5	5	15	20	10	20	30	15	10	10	10	15	15	20	30	30	30	25	20	10
à 2500m																												

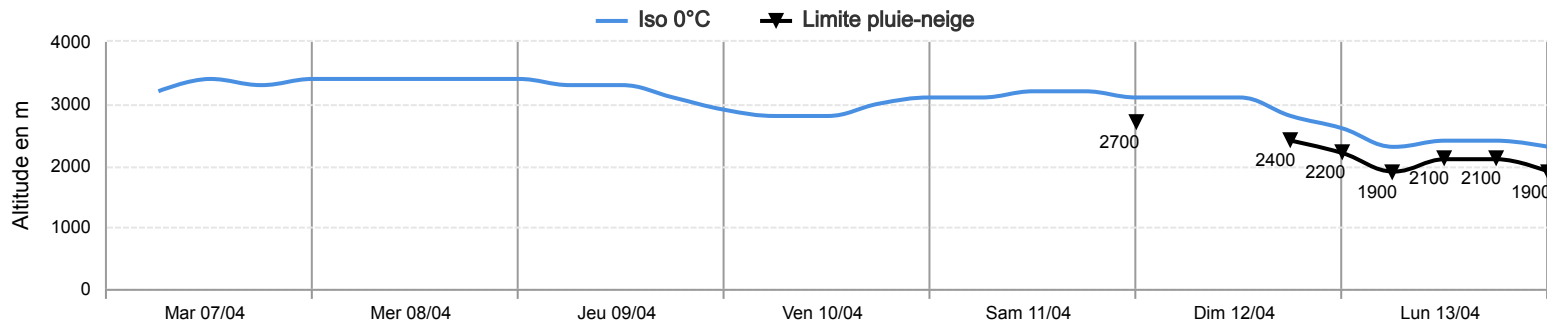

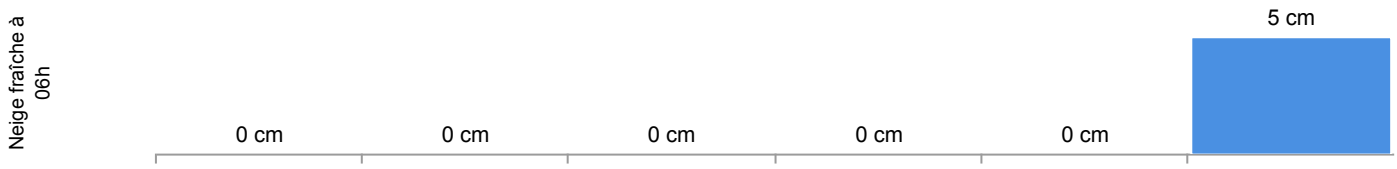

Risque d'avalanche	mar. 07/04	mer. 08/04	jeu. 09/04	ven. 10/04	sam. 11/04	dim. 12/04	lun. 13/04
	2	3	3	3	3	2	2

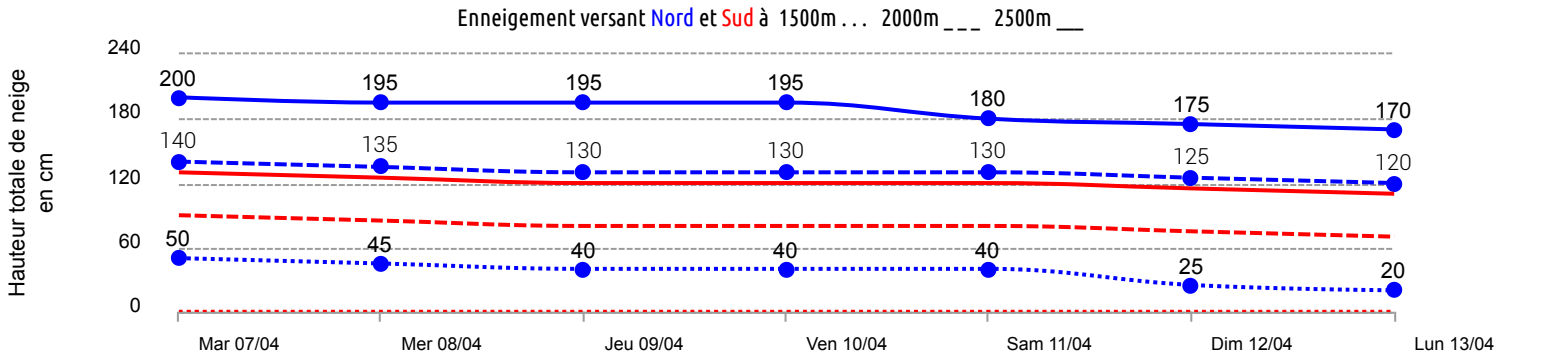

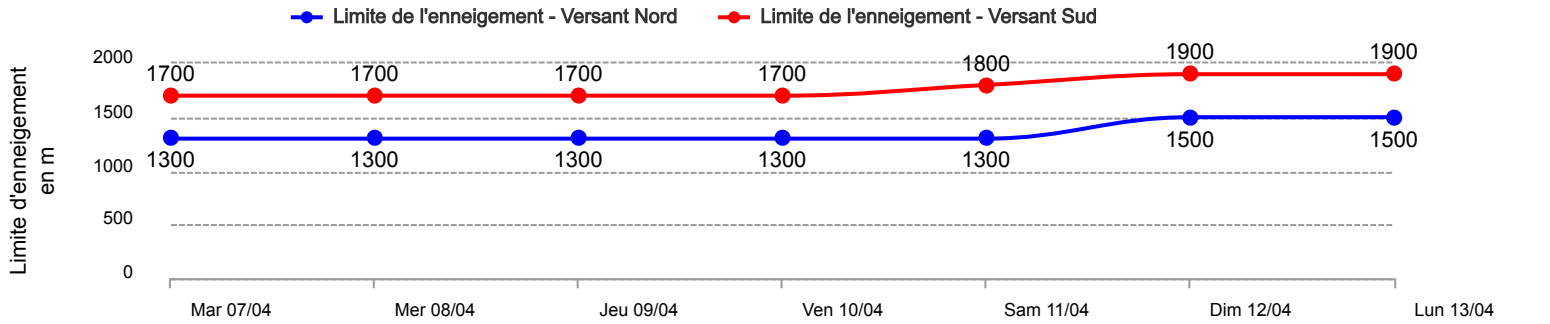

Pour consulter la vigilance en cours, veuillez vous rendre sur le site https://vigilance.meteofrance.fr/fr

Météo-France - 73 avenue de Paris, 94165 Saint-Mandé cedex - Contact : contact@meteo.fr

Rédigé par Météo-France avec la contribution des observateurs du réseau nivo-météorologiques. Partenariat : ANMSM (Maires de Stations de Montagne), DSF (Domaines Skiables de France), ADSP (Directeurs de Pistes et de la Sécurité des Stations de Sports d'Hiver) et autres acteurs de la montagne.

Bulletin neige & avalanches par téléphone au
0 892 68 10 20 Service 0,35 € / min + prix appel