Bulletin d'estimation du risque d'avalanche
(valable en dehors des pistes balisées et ouvertes)

MASSIF : Mercantour

Rédigé le lundi 13 avril 2026 à 16h

Estimation des risques pour le : MARDI 14 AVRIL

ÉPISODE NEIGEUX NON NÉGLIGEABLE A LA FRONTIÈRE ITALIENNE, SUR L'EST DU MASSIF

2

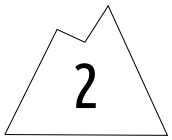

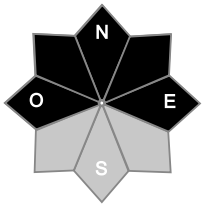

Indice de risque limité.

Départs spontanés : Taille parfois moyenne en neige récente à la frontière italienne

Déclenchements provoqués : Instabilités localisées à la frontière italienne, plus épaisses sur l'est du massif

Indices de risque : 5 très fort - 4 fort - 3 marqué - 2 limité - 1 faible -- En noir : les pentes les plus dangereuses

Stabilité du manteau neigeux

Situation avalancheuse typique : neige fraîche

Déclenchements provoqués : dans la neige récente (et qui tombe encore ce mardi) sur la frontière italienne sur les hautes vallées du Boréon, de la Gordolasque ou de Valmasque, aussi bien en neige froide aux plus hautes altitudes qu'en fraîche s'humidifiant aux premières éclaircies l'après-midi. Déclenchables par un seul skieur, parfois de taille moyenne au-dessus de 2400 m. En Tinée, les chutes prévues sont trop faibles pour aggraver le danger d'avalanche. Les instabilités sont plus minces et plus rares, elles se situent surtout dans la vieille neige humide en large nord d'altitude et sont difficilement déclenchables par un seul skieur, mais peuvent être volumineuses (taille moyenne).

Départs spontanés : sous 2200/2400 m, des avalanches de neige humide peuvent encore se produire à tout moment, en particulier en versant nord, favorisées par les pluies sous 2000/2200 m et par l'eau qui continue de percoler dans le manteau neigeux. Avalanches le plus souvent de taille moyenne (taille 2). Au dessus de 2500 m, des petits départs de neige sèche ventée sont possibles en pentes raides pendant les chutes.

Qualité de la neige

Enneigement proche des normales pour la saison.
Hauteurs de neige observées : 118 cm à la nivose de Millefonts à 2430 m, 56 cm à Isola 2000 à 1900 m.

Enneigement skiable généralement à partir de 1800 m en terrain favorable et 2200/2300 m en adrets peu pentus.

État de la neige en surface : neige récente à la frontière italienne, en quantité négligeable (5/10 cm au plus) en Tinée, bien plus épaisse en allant en hautes vallées du Boréon, de la Gordolasque ou de Valmasque (jusqu'à 30/40 cm au-dessus de 2400 m). Cette chute s'humidifie rapidement l'après-midi sous les éclaircies.

Aperçu météo pour le mardi 14 avril

	nuit	matin	après-midi	soir
Pluie-Neige	2 200 m	2 200 m		2 300 m
Iso 0 °C	2 500 m	2 500 m	2 500 m	2 600 m
Vent 2000 m	40 km/h	40 km/h	45 km/h	40 km/h
Vent 3000 m	50 km/h	50 km/h	50 km/h	45 km/h

Épaisseur de neige hors-piste

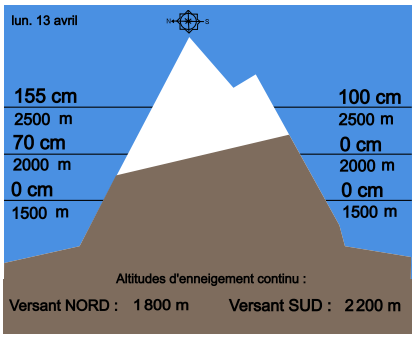

Précipitations à 1800 m

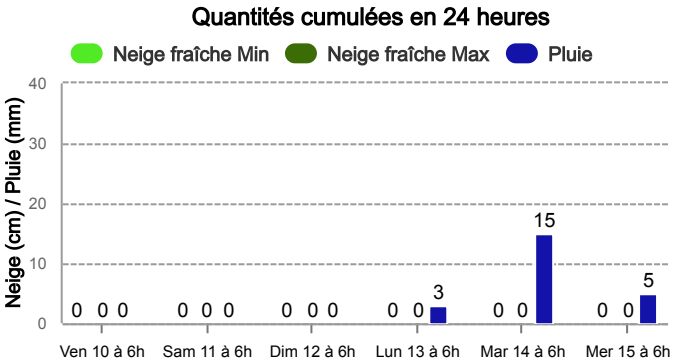

Tendance du mercredi 15 avril

2

Indice de risque limité

Tendance à la baisse. Risque limité, piloté par la neige humide.

Pour consulter la vigilance en cours, veuillez vous rendre sur le site https://vigilance.meteofrance.fr/fr

Météo-France - 73 avenue de Paris, 94165 Saint-Mandé cedex - Contact : contact@meteo.fr

Rédigé par Météo-France avec la contribution des observateurs du réseau nivo-météorologiques. Partenariat : ANMSM (Maires de Stations de Montagne), DSF (Domaines Skiables de France), ADSP (Directeurs de Pistes et de la Sécurité des Stations de Sports d'Hiver) et autres acteurs de la montagne.

Bulletin neige & avalanches par téléphone au
0 892 68 10 20 Service 0,35 € / min + prix appel

RÉPUBLIQUE FRANÇAISE
Liberté Égalité Fraternité

METEO FRANCE
À VOS CÔTÉS, DANS UN CLIMAT QUI CHANGE

Bulletin d'estimation du risque d'avalanche

(valable en dehors des pistes balisées et ouvertes)

MASSIF : Mercantour

Rédigé le lundi 13 avril 2026 à 16h

Conditions nivo-météo des 7 derniers jours

	mar. 07/04				mer. 08/04				jeu. 09/04				ven. 10/04				sam. 11/04				dim. 12/04				lun. 13/04			
	03h	09h	15h	21h	03h	09h	15h	21h	03h	09h	15h	21h	03h	09h	15h	21h	03h	09h	15h	21h	03h	09h	15h	21h	03h	09h	15h	21h
Météo																												
Vent (km/h)	20	20	25	10	10	15	15	10	15	20	25	25	30	25	30	20	25	25	30	15	15	20	20	20	20	20	40	55
à 3000m																												
Vent (km/h)	10	10	20	10	10	10	20	10	10	10	15	20	20	15	20	10	10	20	20	10	10	15	15	15	15	15	30	45
à 2000m																												

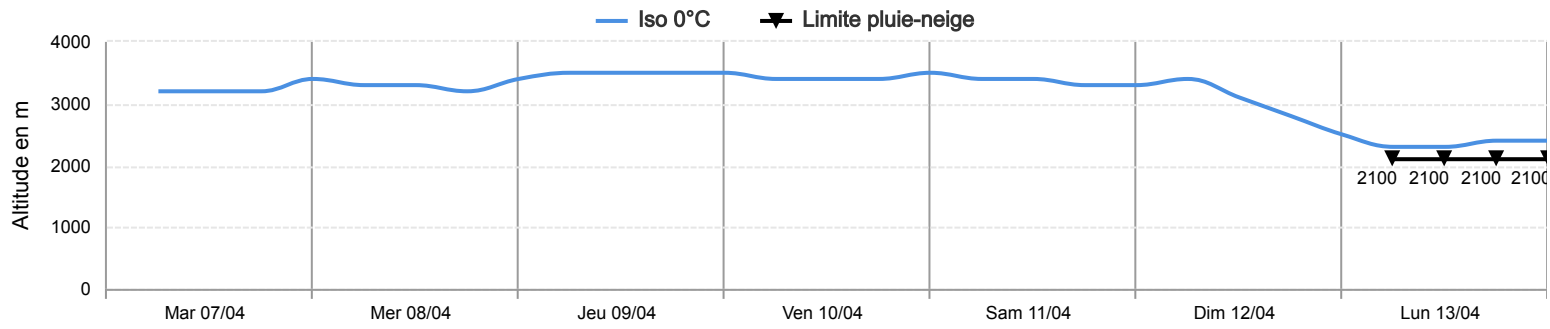

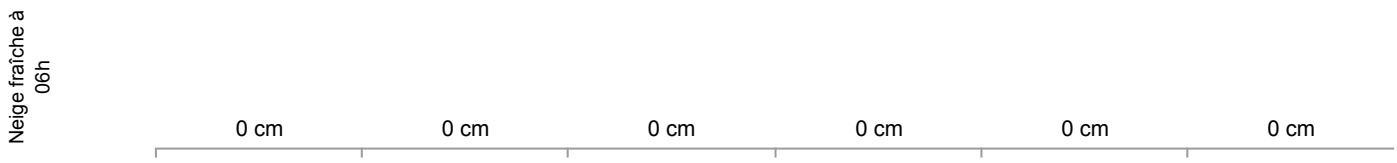

Risque d'avalanche	mar. 07/04	mer. 08/04	jeu. 09/04	ven. 10/04	sam. 11/04	dim. 12/04	lun. 13/04
	2	2	3	3	3	2	2

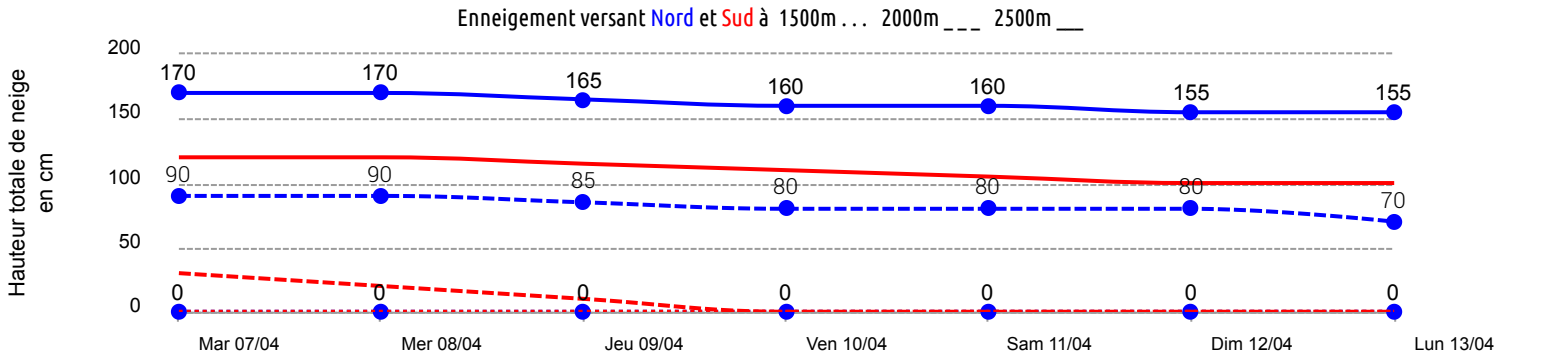

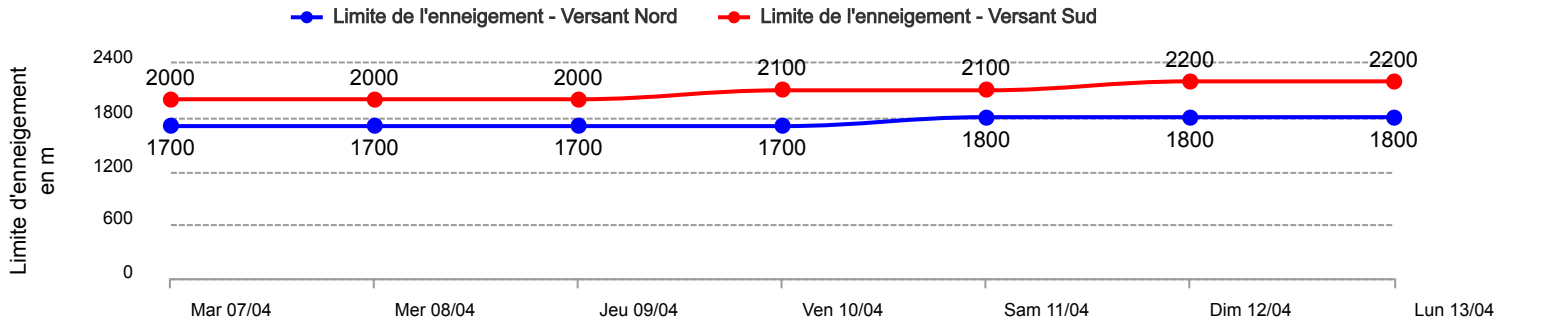

Pour consulter la vigilance en cours, veuillez vous rendre sur le site https://vigilance.meteofrance.fr/fr

Météo-France - 73 avenue de Paris, 94165 Saint-Mandé cedex - Contact : contact@meteo.fr

Rédigé par Météo-France avec la contribution des observateurs du réseau nivo-météorologiques. Partenariat : ANMSM (Maires de Stations de Montagne), DSF (Domaines Skiables de France), ADSP (Directeurs de Pistes et de la Sécurité des Stations de Sports d'Hiver) et autres acteurs de la montagne.

Bulletin neige & avalanches par téléphone au

0 892 68 10 20 Service 0,35 € / min + prix appel