Bulletin d'estimation du risque d'avalanche
(valable en dehors des pistes balisées et ouvertes)

MASSIF : Oisans

Rédigé le lundi 13 avril 2026 à 16h

Estimation des risques pour le : MARDI 14 AVRIL

POSSIBLES COULES/AVALANCHES HUMIDES AU FIN DES HEURES ; VERS LES ECRINS, A HAUTE ALTITUDE, RARES PETITES PLAQUES SOUS LE VENT D'EST ?

2

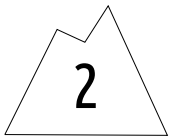

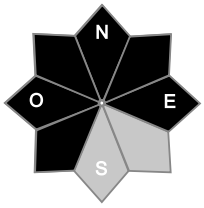

Localisées/altitude

Indices de risque : 5 très fort - 4 fort - 3 marqué - 2 limité - 1 faible -- En noir : les pentes les plus dangereuses

Indice de risque limité.

Départs spontanés : Au fil des heures, rares coulées humides ou avalanches plus conséquentes en faces "froides", notamment sous 2500 voire 2800m (de taille 2, parfois 3 ?)...

Déclenchements provoqués : Peu probable ou coulée humide ponctuelle sous les skis...

Stabilité du manteau neigeux

Situation avalancheuse typique : neige humide neige ventée

Lundi, jusque 10/15 cm de neige fraîche vers les hauts sommets, près des Ecrins... Mardi matin un peu de regel, puis neige rapidement humide sur une grande épaisseur, un peu instable en versants "froids", notamment sous 2500m : rares avalanches possibles.

Départs spontanés :

En altitude, là où il a neigé (près des Ecrins surtout) des coulées ou boules au soleil.

En journée, neige humide, voire sans grande cohésion en faces Nord sous 2500/2800m. On attend quelques coulées ou avalanches locales, parfois volumineuses, au terrain (de taille 2 à 3) - présence d'anciennes couches à moindre cohésion.

Noter que certaines pentes herbeuses sont fissurées, une avalanche de glissement n'est pas exclue, notamment sous 2000/2300m environ. Enfin vers les crêtes un effondrement spontané de corniche n'est pas exclu.

Les faces Sud sont aussi humides mais en neige plus dense/transformée, peu de risque d'avalanche volumineuse...

Déclenchements provoqués :

Risque de plaque a priori très localisé, plutôt le matin en altitude et près des Ecrins, de La Meije, sous le vent d'Est (cassure accidentelle non exclue de 10/20 cm ?). En journée, peu de risque de plaque, mais en pentes soutenues et bien humidifiées, plutôt un risque de coulée ponctuelle sous les skis...

Autres : Regel superficiel mardi matin, neige parfois croutée/cassante. En journée neige très humide à "soupe" selon le versant/ l'altitude, ski parfois difficile...

Qualité de la neige

Qualification de l'enneigement : L'enneigement s'est dégradé depuis 10 jours mais reste assez important en faces peu ensoleillées et en combes d'altitude....

Limites skiables : Vers 1500m au Nord à 1800/2200m au soleil suivant l'exposition, la raideur de la pente...

Qualité de la neige mardi : Hauts sommets saupoudrés la veille, jusque 10/20 cm maxi près des Ecrins, de La Meije.

Mardi matin faible regel au dessus de 2000/2200m (croute parfois cassante ?) puis rapide humidification, en tous versants avec les nuages... neige très humide, plus "molle" en versants froids.

Aperçu météo pour le mardi 14 avril

nuit	matin	après-midi	soir

Quelques flocons lundi soir, puis temps nuageux, regel local en altitude.. Mardi très nuageux, brouillard sous 2500 puis 2800m environ...

Pluie-Neige				
Iso 0 °C	2 200 m	2 700 m	2 900 m	2 900 m
Vent 2500 m	10 km/h	10 km/h	10 km/h	10 km/h
Vent 3500 m	20 km/h	15 km/h	15 km/h	20 km/h

Épaisseur de neige hors-piste

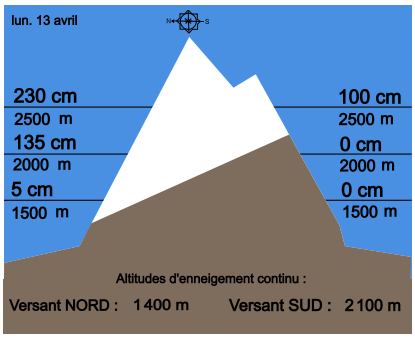

Précipitations à 1800 m

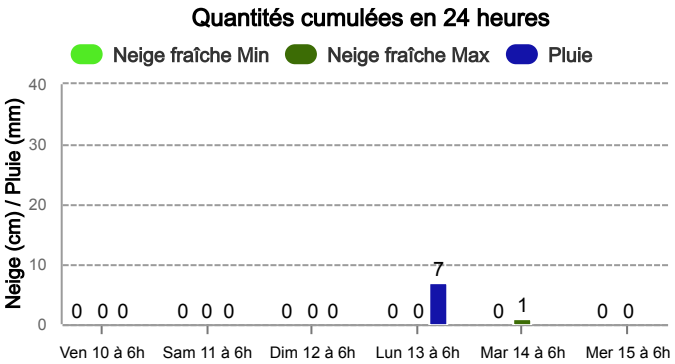

Tendance du mercredi 15 avril

2

Indice de risque limité

Risque en légère baisse mercredi.
Meilleur regel le matin, puis douceur en journée, rares avalanches humides en pente raide...

Pour consulter la vigilance en cours, veuillez vous rendre sur le site https://vigilance.meteofrance.fr/fr

Météo-France - 73 avenue de Paris, 94165 Saint-Mandé cedex - Contact : contact@meteo.fr

Bulletin neige & avalanches par téléphone au 0 892 68 10 20 Service 0,35 € / min + prix appel

Rédigé par Météo-France avec la contribution des observateurs du réseau nivo-météorologiques. Partenariat : ANMSM (Maires de Stations de Montagne), DSF (Domaines Skiables de France), ADSP (Directeurs de Pistes et de la Sécurité des Stations de Sports d'Hiver) et autres acteurs de la montagne.

RÉPUBLIQUE FRANÇAISE
Liberté Égalité Fraternité

METEO FRANCE
À VOS CÔTÉS, DANS UN CLIMAT QUI CHANGE

Bulletin d'estimation du risque d'avalanche
(valable en dehors des pistes balisées et ouvertes)

MASSIF : Oisans

Rédigé le lundi 13 avril 2026 à 16h

Conditions nivo-météo des 7 derniers jours

	mar. 07/04				mer. 08/04				jeu. 09/04				ven. 10/04				sam. 11/04				dim. 12/04				lun. 13/04			
	03h	09h	15h	21h	03h	09h	15h	21h	03h	09h	15h	21h	03h	09h	15h	21h	03h	09h	15h	21h	03h	09h	15h	21h	03h	09h	15h	21h
Météo																												
Vent (km/h)	5	0	5	10	15	5	5	5	5	10	10	20	20	15	10	10	25	25	20	25	25	30	30	30	40	45	30	20
à 3500m																												
Vent (km/h)	5	0	5	10	10	5	5	5	5	0	5	5	5	0	5	5	10	10	15	15	15	15	20	20	25	30	10	15
à 2500m																												

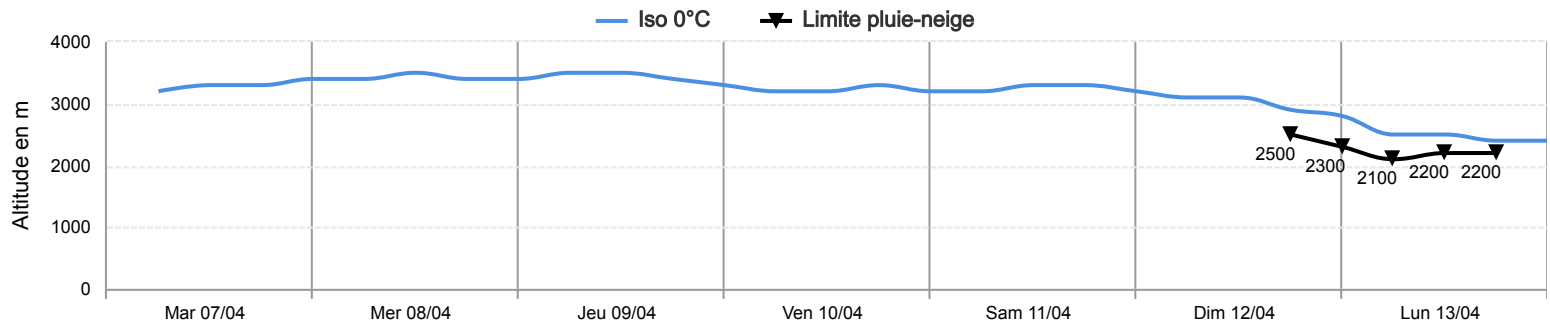

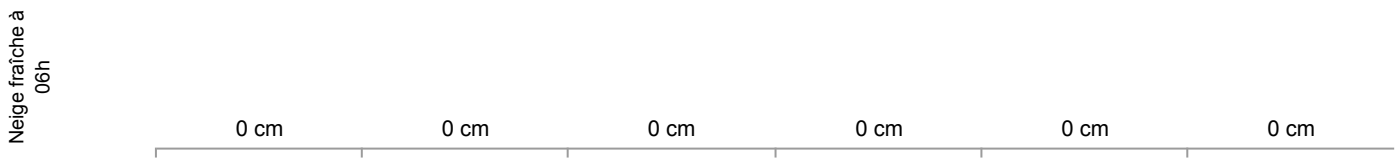

Risque d'avalanche	mar. 07/04	mer. 08/04	jeu. 09/04	ven. 10/04	sam. 11/04	dim. 12/04	lun. 13/04
	2	2	2	2	2	2	2

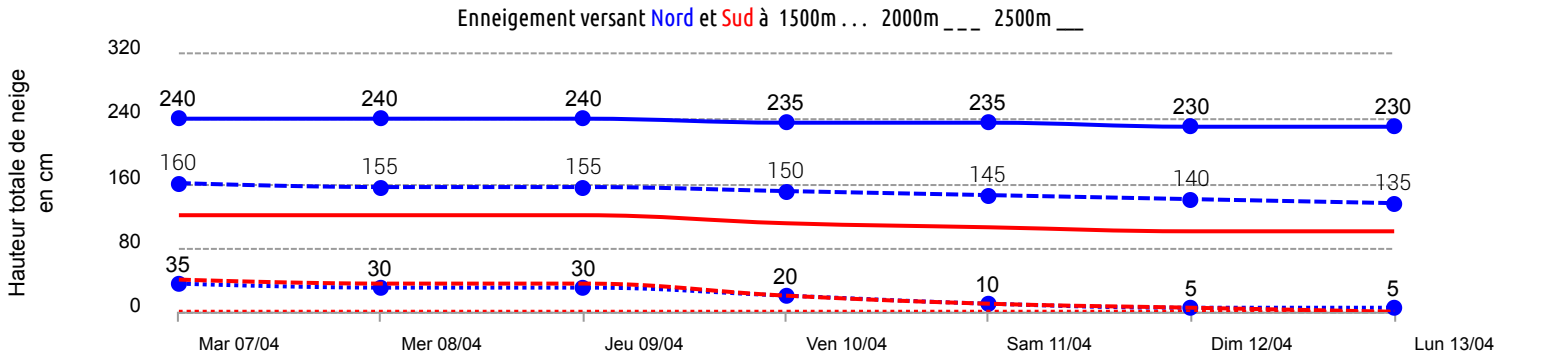

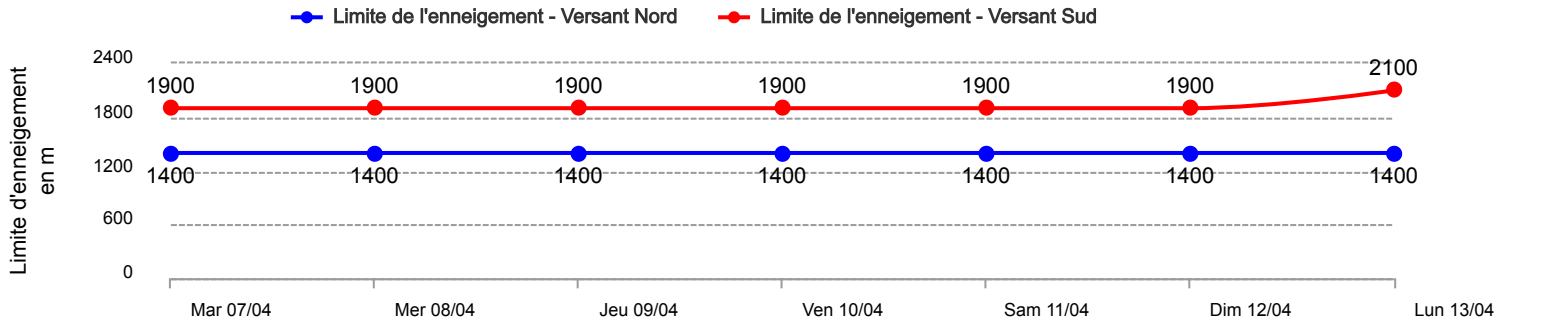

Pour consulter la vigilance en cours, veuillez vous rendre sur le site https://vigilance.meteofrance.fr/fr

Météo-France - 73 avenue de Paris, 94165 Saint-Mandé cedex - Contact : contact@meteo.fr

Rédigé par Météo-France avec la contribution des observateurs du réseau nivo-météorologiques. Partenariat : ANMSM (Maires de Stations de Montagne), DSF (Domaines Skiables de France), ADSP (Directeurs de Pistes et de la Sécurité des Stations de Sports d'Hiver) et autres acteurs de la montagne.

Bulletin neige & avalanches par téléphone au
0 892 68 10 20 Service 0,35 € / min + prix appel