Bulletin d'estimation du risque d'avalanche
(valable en dehors des pistes balisées et ouvertes)

MASSIF : Queyras

Rédigé le lundi 13 avril 2026 à 16h

Estimation des risques pour le : MARDI 14 AVRIL

PLAQUES DANS LA NEIGE FRAÎCHE À LA FRONTIÈRE ITALIENNE

3

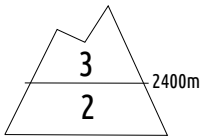

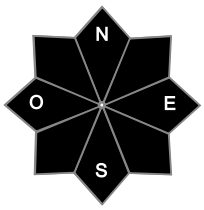

Au-dessus de 2400m indice de risque marqué, plus bas indice limité.

Départs spontanés : Avalanches de neige récente à haute altitude sur le secteur frontalier.

Déclenchements provoqués : instabilités en place dans la neige récente sur le secteur frontalier.

Indices de risque : 5 très fort - 4 fort - 3 marqué - 2 limité - 1 faible -- En noir : les pentes les plus dangereuses

Stabilité du manteau neigeux

Situation avalancheuse typique : neige fraîche couche fragile persistante

Déclenchements provoqués : sur le secteur frontalier avec l'Italie (Fonts de Cervières, Le Roux, Valpréveyre, l'Echalp), de nombreuses instabilités sont en formation au-dessus de 2400 m avec les chutes de neige s'intensifiant dans la nuit de lundi à mardi. Elles sont localisées en toute orientation et encore facilement déclenchables par un seul skieur. En ubacs de haute altitude, cette neige fraîche se dépose sur un manteau neigeux encore peu stabilisé, composé de couches fragiles enfouies à la base du manteau neigeux. Ces instabilités peuvent engendrer des avalanches de taille petite à moyenne (taille 1 à 2), voire une grande (taille 3) dans les ubacs de haute altitude dans le cas de sollicitation d'une couche fragile.
Sur l'ouest du massif, les chutes de neige sont négligeables. le danger est plus limité, les instabilités se situent dans la neige encore humide, plutôt sous 2400 m.

Départs spontanés : sur le secteur frontalier avec l'Italie, avalanches de neige fraîche ventée au cours des chutes de neige dans la nuit de lundi à mardi. En journée de mardi, des avalanches se produisent en pentes raides au fil des éclaircies. Avalanches de taille petite à moyenne (taille 1 à 2), voire grande (taille 3) dans les zones de forte accumulation par la lombarde. Sur le reste du massif, rares départs ponctuels en neige humide, de taille petite à moyenne.

Qualité de la neige

Enneigement nettement déficitaire pour une mi-avril avant l'épisode de ce lundi, notamment en adrets, parfois secs jusqu'à 2500 m.
Hauteurs de neige observées vers 2500 m : 115 cm en versant nord du col Izoard et au-dessus de Saint-Véran à 2700 m, 67 cm à la Nivôse du Col Agnel à 2630 m.

Limite d'enneigement skiable : au plus bas à 1700/1800 m en ubacs bien protégés ou sur pistes forestières, plutôt 2200/2300 m en adrets.

État de la neige de surface : neige fraîche de plus en plus épaisse en allant vers la frontière italienne, tombant sèche et modérément ventée à partir de 2300/2400 m. Sur la majeure partie du massif, manteau neigeux humide, regel très limité à partir de 2600/2800 m.

Aperçu météo pour le mardi 14 avril

	nuit	matin	après-midi	soir

Neige résiduelle à proximité de la frontière italienne puis retour de belles éclaircies sur tout le massif au fil des heures.

Pluie-Neige	1 900 m			
Iso 0 °C	2 100 m	2 400 m	2 700 m	2 600 m
Vent 2000 m	↓ 15 km/h	↙ 20 km/h	↙ 25 km/h	← 10 km/h
Vent 3000 m	↙ 35 km/h	← 30 km/h	↙ 30 km/h	↙ 30 km/h

Épaisseur de neige hors-piste

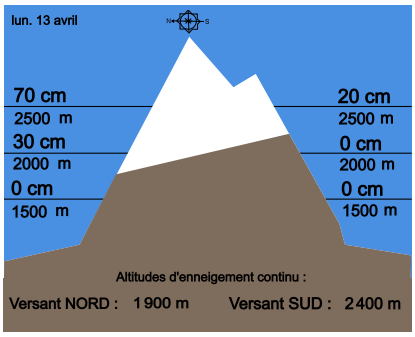

Précipitations à 1800 m

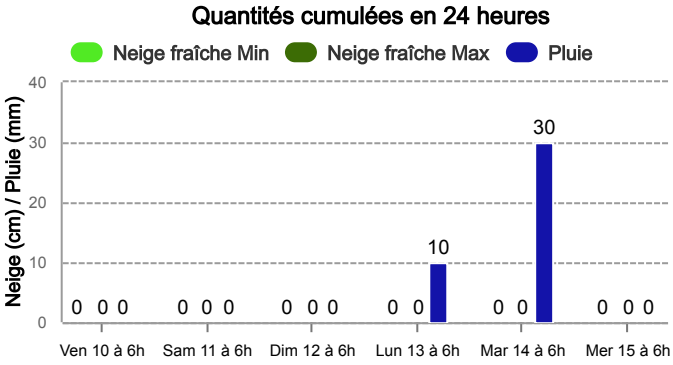

Tendance du mercredi 15 avril

Indice de risque limité

Risque en baisse et devenant limité sur l'ensemble du massif. Le retour du soleil et le radoucissement de la masse d'air entraine une stabilisation rapide des plaques formées sur le secteur frontalier, alors que l'activité en neige humide reprend lentement.

Pour consulter la vigilance en cours, veuillez vous rendre sur le site https://vigilance.meteofrance.fr/fr

Météo-France - 73 avenue de Paris, 94165 Saint-Mandé cedex - Contact : contact@meteo.fr

Rédigé par Météo-France avec la contribution des observateurs du réseau nivo-météorologiques. Partenariat : ANMSM (Maires de Stations de Montagne), DSF (Domaines Skiables de France), ADSP (Directeurs de Pistes et de la Sécurité des Stations de Sports d'Hiver) et autres acteurs de la montagne.

Bulletin neige & avalanches par téléphone au
0 892 68 10 20 Service 0,35 € / min + prix appel

RÉPUBLIQUE FRANÇAISE
Liberté Égalité Fraternité

METEO FRANCE
À VOS CÔTÉS, DANS UN CLIMAT QUI CHANGE

Bulletin d'estimation du risque d'avalanche

(valable en dehors des pistes balisées et ouvertes)

MASSIF : Queyras

Rédigé le lundi 13 avril 2026 à 16h

Conditions nivo-météo des 7 derniers jours

	mar. 07/04				mer. 08/04				jeu. 09/04				ven. 10/04				sam. 11/04				dim. 12/04				lun. 13/04			
	03h	09h	15h	21h	03h	09h	15h	21h	03h	09h	15h	21h	03h	09h	15h	21h	03h	09h	15h	21h	03h	09h	15h	21h	03h	09h	15h	21h
Météo																												
Vent (km/h)	20	15	15	10	10	10	10	10	15	20	25	25	30	30	35	25	25	25	25	15	20	25	30	30	25	40	30	30
à 3000m																												
Vent (km/h)	5	5	20	5	5	5	15	5	5	10	25	15	20	20	25	10	10	10	25	10	10	15	30	20	25	20	25	15
à 2000m																												

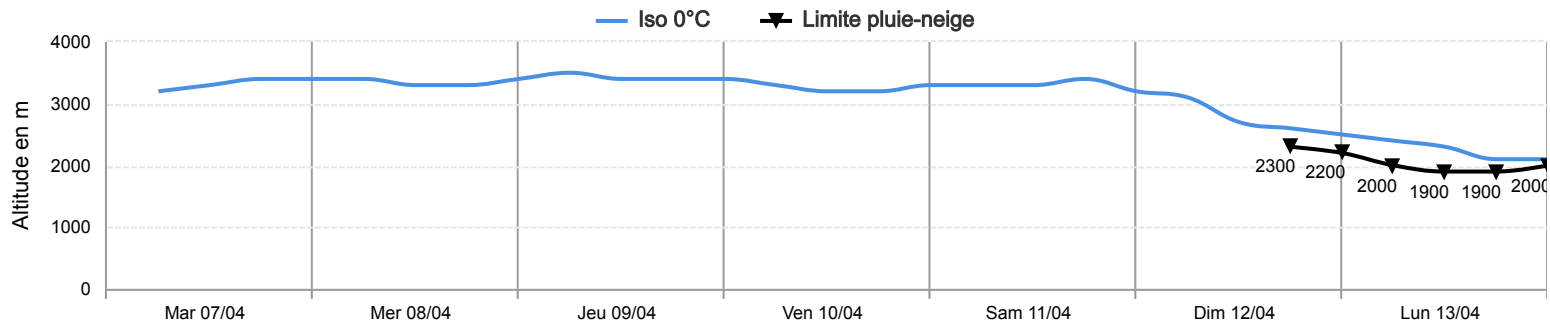

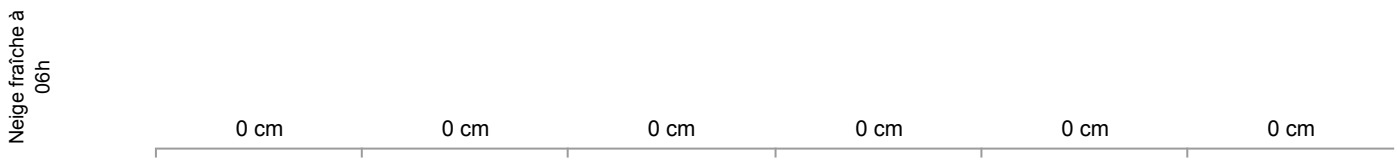

Risque d'avalanche	mar. 07/04	mer. 08/04	jeu. 09/04	ven. 10/04	sam. 11/04	dim. 12/04	lun. 13/04
	2	2	3	3	3	2	3

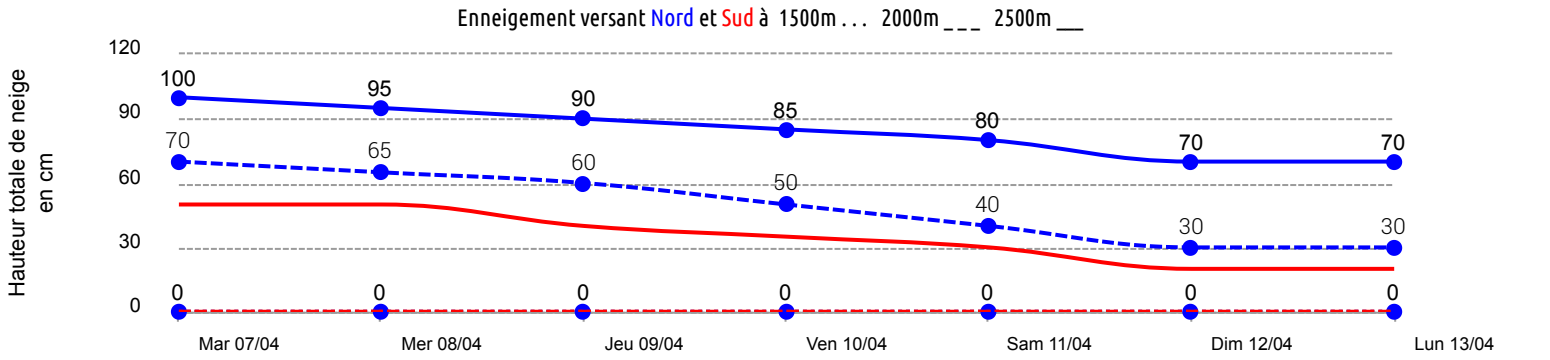

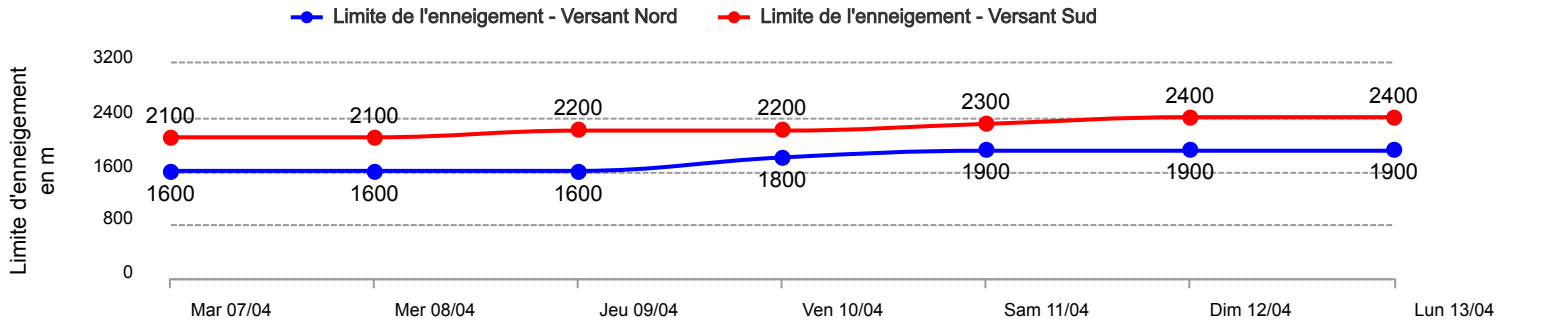

Pour consulter la vigilance en cours, veuillez vous rendre sur le site https://vigilance.meteofrance.fr/fr

Météo-France - 73 avenue de Paris, 94165 Saint-Mandé cedex - Contact : contact@meteo.fr

Rédigé par Météo-France avec la contribution des observateurs du réseau nivo-météorologiques. Partenariat : ANMSM (Maires de Stations de Montagne), DSF (Domaines Skiables de France), ADSP (Directeurs de Pistes et de la Sécurité des Stations de Sports d'Hiver) et autres acteurs de la montagne.

Bulletin neige & avalanches par téléphone au
0 892 68 10 20
Service 0,35 € / min + prix appel