Bulletin d'estimation du risque d'avalanche
(valable en dehors des pistes balisées et ouvertes)

MASSIF : Ubaye

Rédigé le lundi 13 avril 2026 à 16h

Estimation des risques pour le : MARDI 14 AVRIL

MANTEAU NEIGEUX BIEN HUMIDE ET PLUTÔT STABLE

2

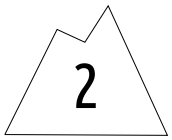

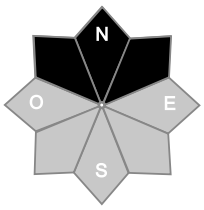

Indice de risque limité.

Départs spontanés : taille moyenne en neige humide

Déclenchements provoqués : dans la neige humide, taille moyenne

Indices de risque : 5 très fort - 4 fort - 3 marqué - 2 limité - 1 faible -- En noir : les pentes les plus dangereuses

Stabilité du manteau neigeux

Situation avalancheuse typique : neige humide couche fragile persistante

Déclenchements provoqués : manteau neigeux bien dense et plutôt stable. Les instabilités se situent surtout en orientations nord-ouest, nord et nord-est d'altitude comprise entre 2200 et 2600 m environ. Un seul skieur peut parfois déclencher une avalanche de taille moyenne. Le manteau neigeux est bien humide, mais des couches fragiles sont encore localement sollicitables à sa base. A plus haute altitude, un départ en neige sèche n'est pas exclu sur la frontière italienne en Haute Ubaye. Taille petite à moyenne dans les accumulations de neige par le vent. Sous 2200 m, manteau neigeux entièrement transformé et bien stable.

Départs spontanés : rares avalanches de neige humide de taille moyenne, parfois sous forme d'avalanches de glissement en orientations nord-ouest, nord et nord-est d'altitude.

Qualité de la neige

Enneigement déficitaire pour la saison.
Hauteurs de neige observées : 41 cm à la nivose de Restefond à 2550 m

Enneigement skiable généralement à partir de 1800/1900 m en terrain favorable et 2300/2400 m en adrets peu pentus.

État de la neige en surface : manteau neigeux humide et mal regelé sous 2500/2600 m, plus souvent regelé au-dessus, saupoudré d'un peu de neige récente, notamment en Haute Ubaye.
Humidification plus nette sous les éclaircies plus généreuses ce mardi

Aperçu météo pour le mardi 14 avril

	nuit	matin	après-midi	soir
	Belles éclaircies l'après-midi, redoux.			
Pluie-Neige				
Iso 0 °C	2 500 m	2 600 m	2 700 m	2 800 m
Vent 2000 m	20 km/h	20 km/h	20 km/h	15 km/h
Vent 3000 m	40 km/h	30 km/h	25 km/h	20 km/h

Épaisseur de neige hors-piste

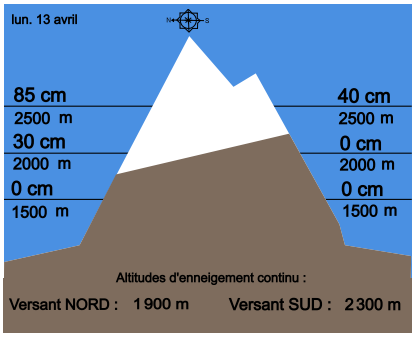

Précipitations à 1800 m

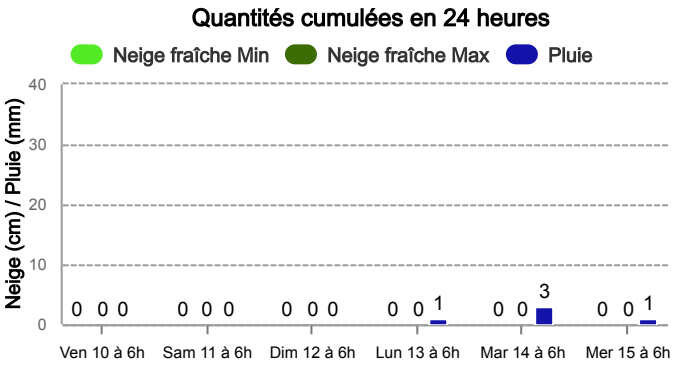

Tendance du mercredi 15 avril

2

Indice de risque limité

Peu d'évolution de la situation nivologique.
Risque limité, piloté par la neige humide

Pour consulter la vigilance en cours, veuillez vous rendre sur le site https://vigilance.meteofrance.fr/fr

Météo-France - 73 avenue de Paris, 94165 Saint-Mandé cedex - Contact : contact@meteo.fr

Rédigé par Météo-France avec la contribution des observateurs du réseau nivo-météorologiques. Partenariat : ANMSM (Maires de Stations de Montagne), DSF (Domaines Skiables de France), ADSP (Directeurs de Pistes et de la Sécurité des Stations de Sports d'Hiver) et autres acteurs de la montagne.

Bulletin neige & avalanches par téléphone au
0 892 68 10 20 Service 0,35 € / min + prix appel

RÉPUBLIQUE FRANÇAISE
Liberté Égalité Fraternité

METEO FRANCE
À VOS CÔTÉS, DANS UN CLIMAT QUI CHANGE

Bulletin d'estimation du risque d'avalanche

(valable en dehors des pistes balisées et ouvertes)

MASSIF : Ubaye

Rédigé le lundi 13 avril 2026 à 16h

Conditions nivo-météo des 7 derniers jours

	mar. 07/04				mer. 08/04				jeu. 09/04				ven. 10/04				sam. 11/04				dim. 12/04				lun. 13/04			
	03h	09h	15h	21h	03h	09h	15h	21h	03h	09h	15h	21h	03h	09h	15h	21h	03h	09h	15h	21h	03h	09h	15h	21h	03h	09h	15h	21h
Météo																												
Vent (km/h)	10	10	15	10	10	15	10	10	15	20	25	35	40	30	30	20	25	25	30	15	20	20	20	20	25	30	35	40
à 3000m																												
Vent (km/h)	5	5	20	5	5	5	15	5	5	5	15	10	15	15	25	10	10	15	20	10	10	10	10	15	15	20	20	20
à 2000m																												

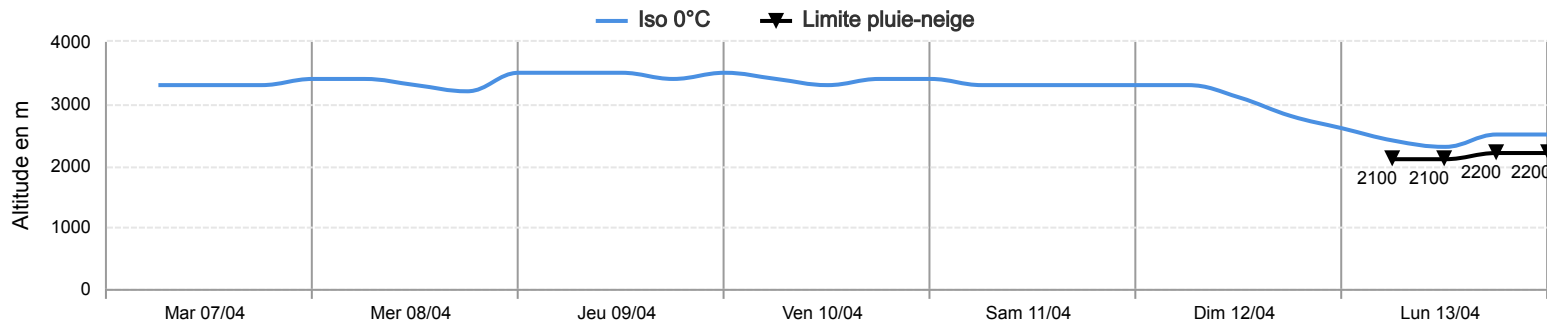

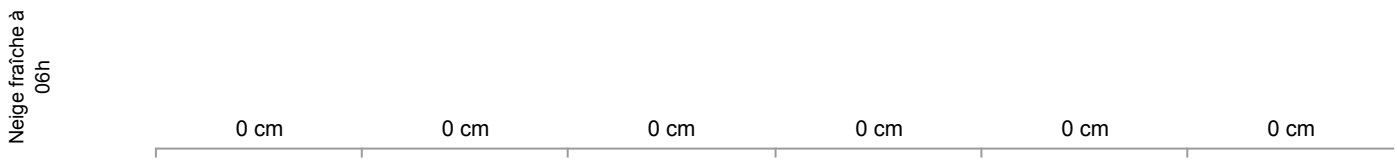

Risque d'avalanche	mar. 07/04	mer. 08/04	jeu. 09/04	ven. 10/04	sam. 11/04	dim. 12/04	lun. 13/04
	2	2	3	3	3	2	2

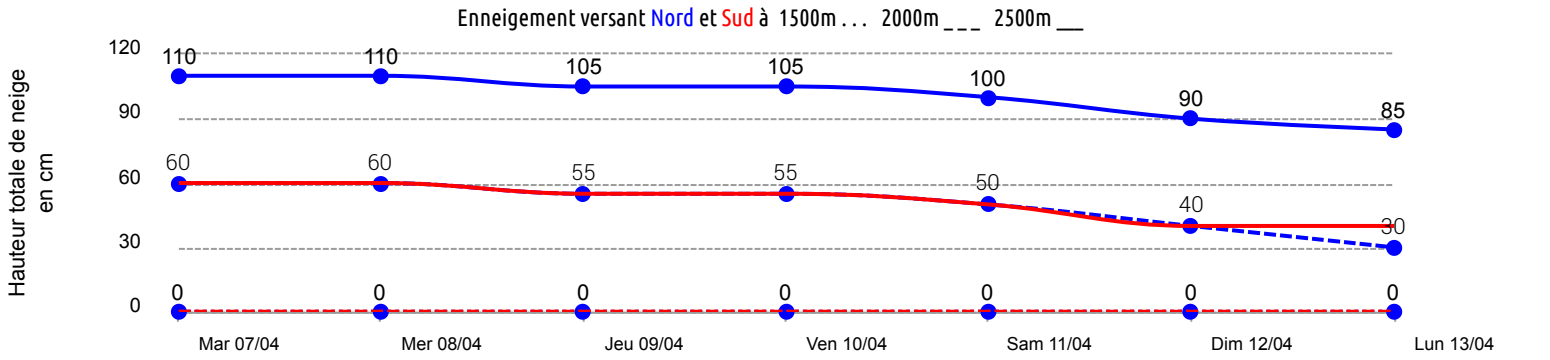

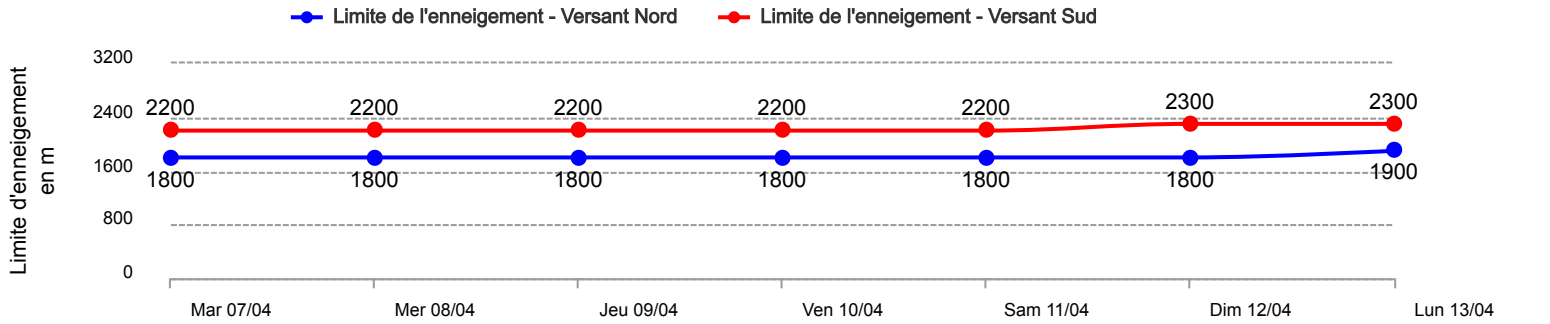

Pour consulter la vigilance en cours, veuillez vous rendre sur le site https://vigilance.meteofrance.fr/fr

Météo-France - 73 avenue de Paris, 94165 Saint-Mandé cedex - Contact : contact@meteo.fr

Rédigé par Météo-France avec la contribution des observateurs du réseau nivo-météorologiques. Partenariat : ANMSM (Maires de Stations de Montagne), DSF (Domaines Skiables de France), ADSP (Directeurs de Pistes et de la Sécurité des Stations de Sports d'Hiver) et autres acteurs de la montagne.

Bulletin neige & avalanches par téléphone au
0 892 68 10 20 Service 0,35 € / min + prix appel