Bulletin d'estimation du risque d'avalanche
(valable en dehors des pistes balisées et ouvertes)
MASSIF : Vercors

Rédigé le lundi 13 avril 2026 à 16h

Estimation des risques pour le : MARDI 14 AVRIL

MANTEAU DENSE MAIS BIEN HUMIDE EN PROFONDEUR, RARES COULEES OU AVALANCHE DE FOND...

2

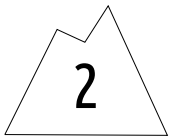

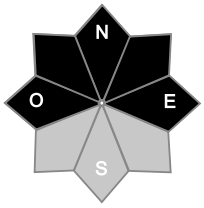

Rares...

Indices de risque : 5 très fort - 4 fort - 3 marqué - 2 limité - 1 faible -- En noir : les pentes les plus dangereuses

Indice de risque limité.

Départs spontanés : Là où il a neigé, des boules/coulées de surface. En faces "froides" plus enneigées rare avalanche humide conséquente (taille 2 à 3), parfois glissant au terrain (faces Nord raides/herbeuses ?) ...

Déclenchements provoqués : RAS ou coulée de surface humide sous les skis...

Stabilité du manteau neigeux

Situation avalancheuse typique : neige humide avalanches de fond

Mardi 10 cm de neige récente possibles sur l'Ouest du massif, saupoudrage ailleurs... quelques mini coulées de surface... En versants froid d'altitude/pentes herbeuses, rare avalanche de fond, glissant au terrain ?

Départs spontanés :

Dès le matin rapide dégel en tous versants.
Là où il a neigé (jusque 10 cm sur les sommets de Ouest Vercors), de possibles boules/coulées de surface.
En faces froides, il reste encore pas mal de neige dense, humide en profondeur, des fissures de reptation s'ouvrent ponctuellement.
A toute heure, risque très local de coulée ou avalanche de glissement au terrain, de taille plus conséquente ? (pentes herbeuses notamment)

Déclenchements provoqués :

Peu probable ou coulée ponctuelle de neige humide sous les skis, en pentes soutenues...

Qualité de la neige

Qualification de l'enneigement : L'enneigement a nettement régressé depuis 10 jours, et ne reste correct que sur les hauts du massif en pentes peu ensoleillées. Un peu de fraîche lundi sur l'Ouest du massif, saupoudrage ailleurs.
Limites skiables : Vers 1400 à 1800m selon le versant (hors sapins), plein Sud sec...

Qualité de la neige mardi : Faible regel nocturne à l'aube en haut du massif, puis rapide dégel en matinée.
Un peu de neige récente sur les sommets de l'Ouest du massif (10 cm maxi, ailleurs saupoudrage), devenant collante/humide. Sous couche en neige dense très humide, pas du grand ski en perspective..

Aperçu météo pour le mardi 14 avril

nuit	matin	après-midi	soir

Quelques gouttes/flocons lundi soir, puis temps nuageux, frais.. Mardi très nuageux, brouillard des forêts aux sommets, redoux...

Pluie-Neige				
Iso 0 °C	1 700 m	2 100 m	2 200 m	2 700 m
Vent 1500 m	35 km/h	40 km/h	40 km/h	25 km/h
Vent 2000 m	35 km/h	35 km/h	35 km/h	35 km/h

Épaisseur de neige hors-piste

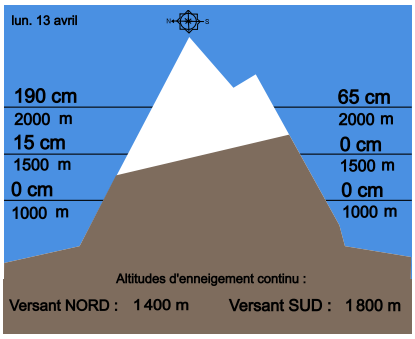

Précipitations à 1800 m

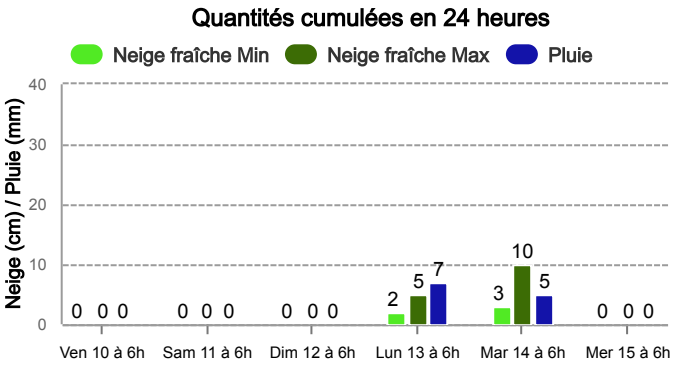

Tendance du mercredi 15 avril

2

Indice de risque limité

Risque stationnaire ou en légère baisse mercredi.
Meilleur regel le matin, puis douceur en journée, rare avalanche de glissement...

Pour consulter la vigilance en cours, veuillez vous rendre sur le site https://vigilance.meteofrance.fr/fr

Météo-France - 73 avenue de Paris, 94165 Saint-Mandé cedex - Contact : contact@meteo.fr

Rédigé par Météo-France avec la contribution des observateurs du réseau nivo-météorologiques. Partenariat : ANMSM (Maires de Stations de Montagne), DSF (Domaines Skiables de France), ADSP (Directeurs de Pistes et de la Sécurité des Stations de Sports d'Hiver) et autres acteurs de la montagne.

Bulletin neige & avalanches par téléphone au 0 892 68 10 20 Service 0,35 € / min + prix appel

RÉPUBLIQUE FRANÇAISE
Liberté Égalité Fraternité

METEO FRANCE
À VOS CÔTÉS, DANS UN CLIMAT QUI CHANGE

Bulletin d'estimation du risque d'avalanche

(valable en dehors des pistes balisées et ouvertes)

MASSIF : Vercors

Rédigé le lundi 13 avril 2026 à 16h

Conditions nivo-météo des 7 derniers jours

	mar. 07/04				mer. 08/04				jeu. 09/04				ven. 10/04				sam. 11/04				dim. 12/04				lun. 13/04			
	03h	09h	15h	21h	03h	09h	15h	21h	03h	09h	15h	21h	03h	09h	15h	21h	03h	09h	15h	21h	03h	09h	15h	21h	03h	09h	15h	21h
Météo																												
Vent (km/h)	5	15	10	10	10	10	5	10	15	15	25	45	40	35	25	20	20	25	20	15	25	15	15	10	15	20	35	35
à 2000m	↓	↗	↑	↙	↙	↙	↗	↙	↙	↙	↓	↓	↙	↓	↓	→	↗	↗	↑	↗	→	→	↘	←	←	↓	↓	↙
Vent (km/h)	5	5	5	10	10	5	5	5	10	10	20	25	20	30	20	10	15	15	20	10	15	15	20	15	15	20	30	35
à 1500m	↓	↑	↑	↙	↙	↙	↓	↓	↓	↓	↓	↓	↓	↓	↓	↓	↑	↑	↑	↗	↓	↑	↓	↓	↓	↓	↓	↓

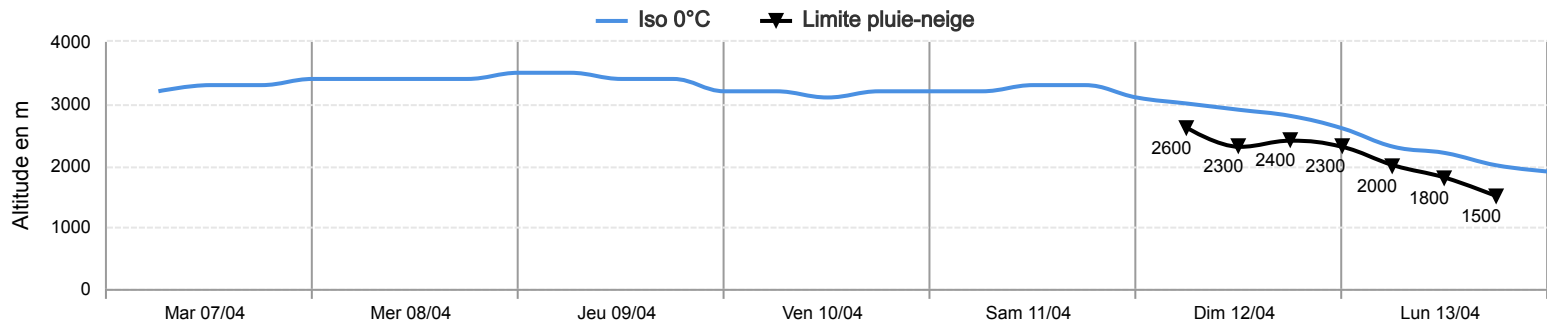

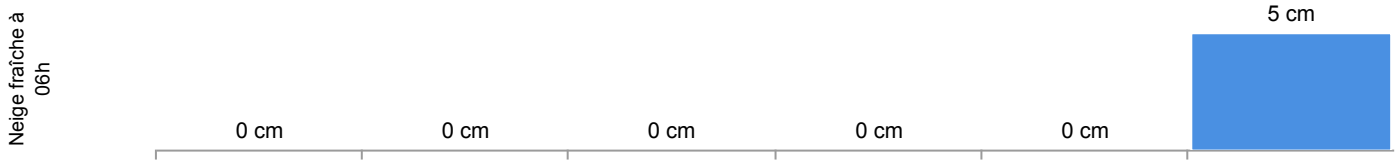

Risque d'avalanche	mar. 07/04	mer. 08/04	jeu. 09/04	ven. 10/04	sam. 11/04	dim. 12/04	lun. 13/04
	2	2	2	2	2	2	2

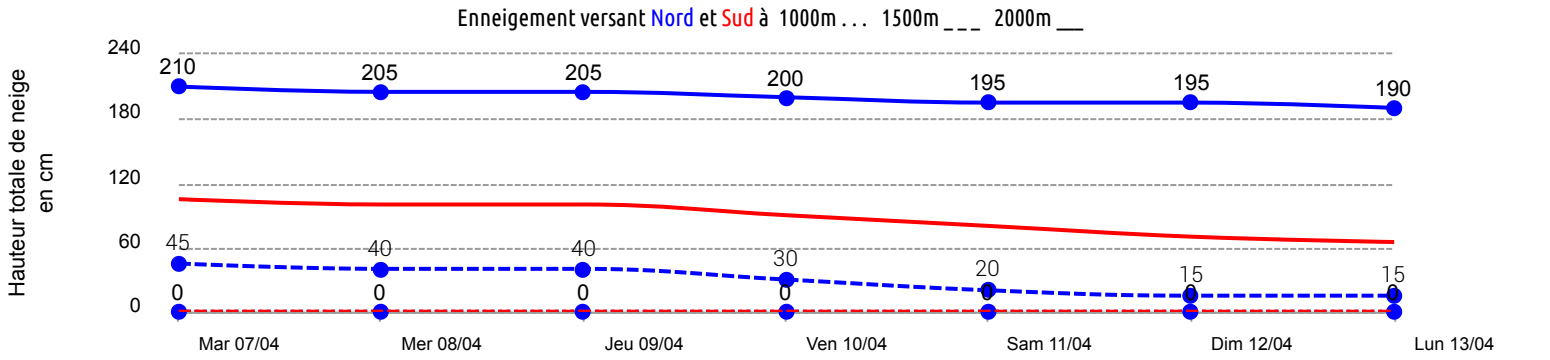

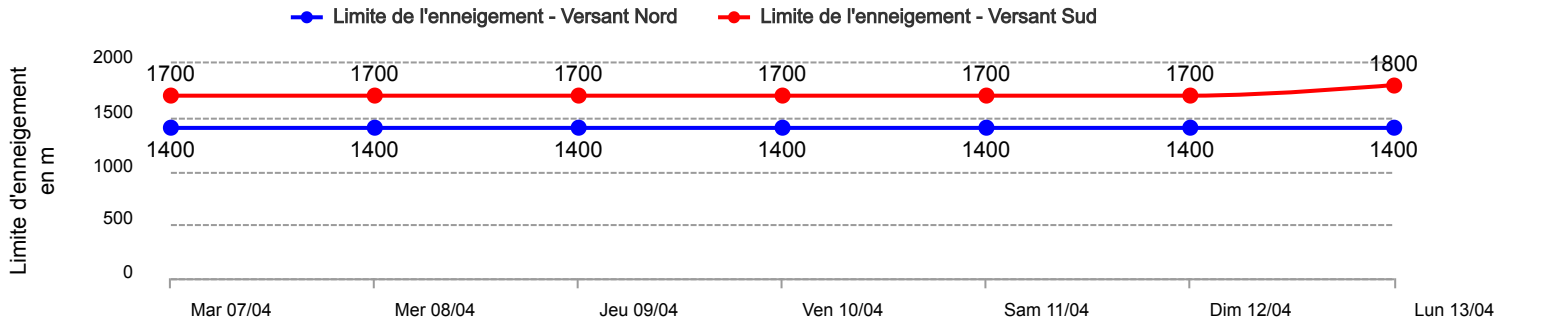

Pour consulter la vigilance en cours, veuillez vous rendre sur le site https://vigilance.meteofrance.fr/fr

Météo-France - 73 avenue de Paris, 94165 Saint-Mandé cedex - Contact : contact@meteo.fr

Rédigé par Météo-France avec la contribution des observateurs du réseau nivo-météorologiques. Partenariat : ANMSM (Maires de Stations de Montagne), DSF (Domaines Skiables de France), ADSP (Directeurs de Pistes et de la Sécurité des Stations de Sports d'Hiver) et autres acteurs de la montagne.

Bulletin neige & avalanches par téléphone au
0 892 68 10 20 Service 0,35 € / min + prix appel