Lawinengefahr

Aktualisiert am 13.4.2026, 08:00

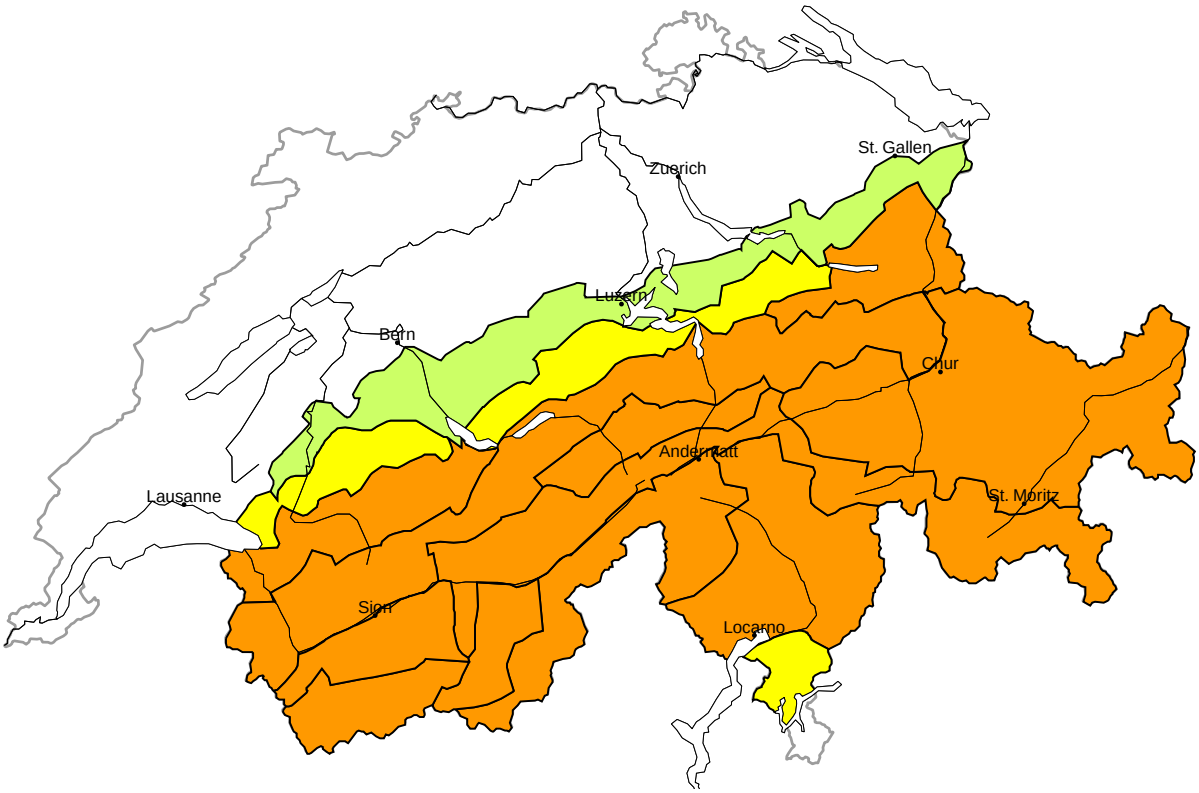

Gebiet A

Erheblich (3+)

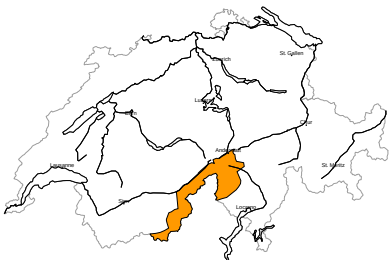

Neuschnee, Altschnee

Gefahrenstellen

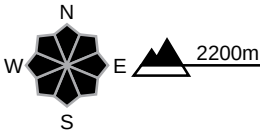

Gefahrenbeschrieb

Es fällt weniger Schnee als erwartet.
Neu- und Triebschnee sind in der Höhe störanfällig. Im Tagesverlauf sind zunehmend spontane trockene Lawinen möglich. Trockene Lawinen können teilweise im Altschnee anbrechen und gross werden. Sie können den nassen Altschnee mitreissen und bis ins Grüne vorstossen. Touren erfordern viel Erfahrung in der Beurteilung der Lawinengefahr und Zurückhaltung.

Erheblich (3)

Nassschnee

Mit dem Regen sind zahlreiche nasse Lawinen zu erwarten, vor allem an steilen West-, Nord- und Osthängen unterhalb von rund 2200 m. Nasse Lawinen können teilweise die gesamte Schneedecke mitreissen und gross werden. Für Touren sind die Verhältnisse kritisch.

Gefahrenstufen 1 gering | 2 mässig | 3 erheblich | 4 gross | 5 sehr gross

Gebiet B

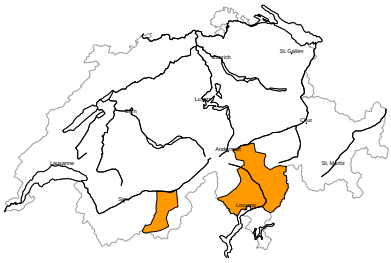

Erheblich (3=)

Neuschnee, Altschnee

Gefahrenstellen

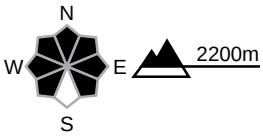

Gefahrenbeschrieb
Neu- und Triebschnee sind in der Höhe störanfällig. Trockene Lawinen können auch im Altschnee anbrechen und gross werden. Es sind im Tagesverlauf einzelne spontane Lawinen möglich. Touren und Variantenabfahrten erfordern Erfahrung in der Beurteilung der Lawinengefahr und Vorsicht.

Erheblich (3)

Nassschnee

Mit dem Regen sind zahlreiche nasse Lawinen zu erwarten, vor allem an steilen West-, Nord- und Osthängen unterhalb von rund 2200 m. Nasse Lawinen können teilweise die gesamte Schneedecke mitreissen und gross werden. Für Touren sind die Verhältnisse kritisch.

Gebiet C

Erheblich (3-)

Triebschnee, Altschnee

Gefahrenstellen

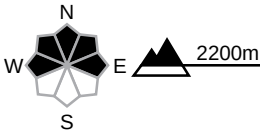

Gefahrenbeschrieb
Mit Neuschnee und Südwind entstehen störanfällige Triebschneeansammlungen. Einzelne Wintersportler können Lawinen auslösen. Stellenweise können trockene Lawinen auch im Altschnee ausgelöst werden und vereinzelt gross werden.
Touren erfordern Erfahrung in der Beurteilung der Lawinengefahr.

Erheblich (3)

Nassschnee

Die Schneeoberfläche gefriert kaum und weicht rasch auf. Es sind Nass- und Gleitschneelawinen zu erwarten. Dies vor allem an steilen Ost-, Süd- und Westhängen zwischen etwa 2000 und 2800 m sowie an steilen Nordhängen unterhalb von rund 2400 m. Zudem können stellenweise nasse Lawinen durch Personen ausgelöst werden. Lawinen können gross werden.
Für Touren sind die Verhältnisse kritisch.

Gebiet D

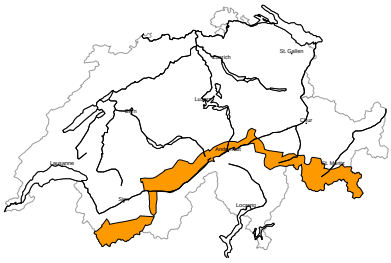

Erheblich (3-)

Triebschnee, Altschnee

Gefahrenstellen

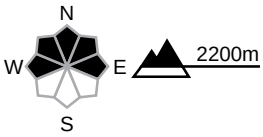

Gefahrenbeschrieb
Mit Neuschnee und Südwind entstehen störanfällige Triebschneeansammlungen. Einzelne Wintersportler können Lawinen auslösen. Stellenweise können trockene Lawinen auch im Altschnee ausgelöst werden und vereinzelt gross werden.
Touren erfordern Erfahrung in der Beurteilung der Lawinengefahr.

Erheblich (3)

Nassschnee

Mit dem Regen sind zahlreiche nasse Lawinen zu erwarten, vor allem an steilen West-, Nord- und Osthängen unterhalb von rund 2200 m. Nasse Lawinen können teilweise die gesamte Schneedecke mitreissen und gross werden. Für Touren sind die Verhältnisse kritisch.

Gebiet E

Erheblich (3)

Nassschnee

Die Schneeoberfläche gefriert kaum und weicht rasch auf. Es sind Nass- und Gleitschneelawinen zu erwarten. Dies vor allem an steilen Ost-, Süd- und Westhängen zwischen etwa 2000 und 2800 m sowie an steilen Nordhängen unterhalb von rund 2400 m. Zudem können stellenweise nasse Lawinen durch Personen ausgelöst werden. Lawinen können gross werden.
Für Touren sind die Verhältnisse kritisch.

Gering (1)

Kein ausgeprägtes Lawinenproblem

Gefahrenstellen

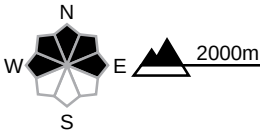

Gefahrenbeschrieb
Trockene Lawinen sind kaum zu erwarten. Sehr vereinzelte Gefahrenstellen liegen vor allem an extrem steilen Schattenhängen in der Höhe.

Gebiet F

Erheblich (3)

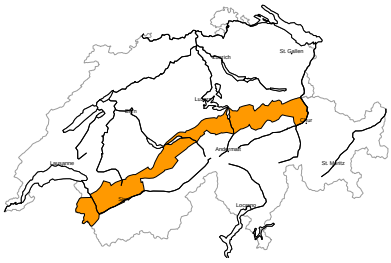

Nassschnee

Die Schneeoberfläche gefriert kaum und weicht rasch auf. Es sind Nass- und Gleitschneelawinen zu erwarten. Dies vor allem an steilen Ost-, Süd- und Westhängen zwischen etwa 2000 und 2800 m sowie an steilen Nordhängen unterhalb von rund 2400 m. Zudem können stellenweise nasse Lawinen durch Personen ausgelöst werden. Lawinen können gross werden.
Für Touren sind die Verhältnisse kritisch.

Mässig (2=)

Triebschnee

Gefahrenstellen

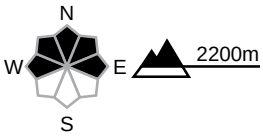

Gefahrenbeschrieb
Mit Südwind entstehen lokal meist kleine Triebschneeansammlungen. Diese liegen vor allem in Kammlagen, Rinnen und Mulden. Die Lawinen können stellenweise von einzelnen Wintersportlern ausgelöst werden und mittlere Grösse erreichen.
Eine vorsichtige Routenwahl ist empfohlen.

Gebiet G

Erheblich (3)

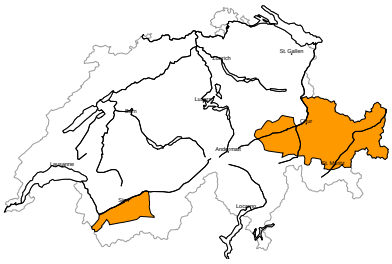

Nassschnee

Die Schneeoberfläche gefriert kaum. Es sind ab dem Vormittag nasse Lawinen möglich. Dies vor allem an steilen Sonnenhängen zwischen etwa 2000 und 3000 m sowie an steilen Nordhängen unterhalb von rund 2400 m. Nasse Lawinen können durch Personen ausgelöst werden. Einzelne Wummgeräusche können auf die Gefahr hinweisen. Lawinen können gross werden.
Die Tourenverhältnisse sind kritisch.

Mässig (2=)

Triebschnee, Altschnee

Gefahrenstellen

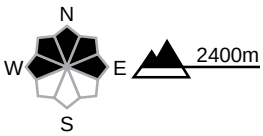

Gefahrenbeschrieb
Stellenweise können trockene Lawinen im Altschnee ausgelöst werden und vereinzelt gross werden. Diese Gefahrenstellen sind auch für Geübte kaum zu erkennen. Vorsicht an eher schneearmen Stellen im selten befahrenen Tourengelände.
Mit Südwind entstehen lokal eher kleine Triebschneeansammlungen.
Eine vorsichtige Routenwahl ist empfohlen.

Gebiet H

Mässig (2)

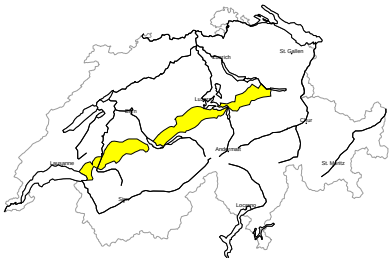

Nassschnee

Es sind Nass- und Gleitschneelawinen möglich, auch mittelgrosse. Die Gefahrenstellen liegen vor allem an West-, Nord- und Osthängen.
Eine vorsichtige Routenwahl ist wichtig.

Gering (1)

Kein ausgeprägtes Lawinenproblem

Gefahrenstellen

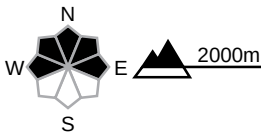

Gefahrenbeschrieb

Trockene Lawinen sind kaum zu erwarten. Sehr vereinzelte Gefahrenstellen liegen vor allem an extrem steilen Schattenhängen in der Höhe.

Gebiet I

Mässig (2)

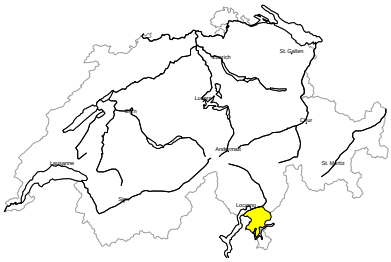

Nassschnee

Mit dem Regen sind nasse Lawinen möglich, vor allem an steilen West-, Nord- und Osthängen. Lawinen können vereinzelt mittlere Grösse erreichen.
Schon eine kleine Lawine kann Personen mitreissen und zum Absturz bringen.

Gebiet J

Gering (1)

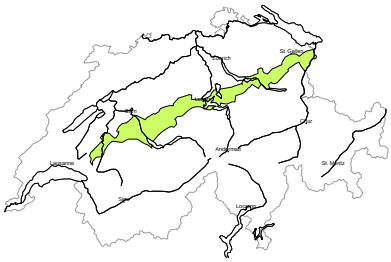

Nassschnee

An steilen Grashängen sind einzelne nasse Rutsche möglich. Die Mitreiss- und Absturzgefahr sollte beachtet werden.

Schneedecke und Wetter

Aktualisiert am 12.4.2026, 17:00

Schneedecke

Mit der milden Witterung, teils bedeckten Nächten und zeitweisem Regen schritt die Durchfeuchtung der Schneedecke in der zu Ende gehenden Woche weiter voran. An Südhängen ist die Schneedecke bis auf rund 3000 m, an Ost- und Westhängen bis auf 2500 bis 2700 m durchfeuchtet. An Nordhängen ist sie unterhalb von 2000 m durchfeuchtet und zwischen 2000 und 2400 m schreitet die Durchfeuchtung voran.
Mit den erwarteten, im Süden teils intensiven Schneefällen entstehen in der Höhe grosse Triebschneeansammlungen. Spontane Lawinen können vor allem an Nordhängen teils die ganze Schneedecke mitreissen. Dies vor allem in den Hauptniederschlagsgebieten im Wallis, vereinzelt aber auch in den anderen Gebieten. Zudem können Personen Lawinen im Neu- und Triebschnee auslösen.
Mit dem Regen sind vermehrt Nass- und Gleitschneelawinen zu erwarten.

Wetter Rückblick auf Sonntag

Es war meist bewölkt mit schwachen Schauern an den Voralpen. Die Schneefallgrenze lag bei 2000 m. In Graubünden war es teils aufgehellt.

Neuschnee
-

Temperatur
am Mittag auf 2000 m um +3 °C im Norden und im Tessin und bei +6 °C in den inneralpinen Gebieten

Wind
schwach bis mässig, im Tagesverlauf am nördlichen Alpenkamm mässig bis stark aus südlichen Richtungen

Wetter Prognose bis Montag

Am Sonntagabend setzen im Süden Niederschläge ein, die sich in der Nacht auf Montag intensiveren und im Süden gebietsweise sehr ergiebig sind. Die Niederschläge greifen auch auf den Norden über, sind dort aber schwächer. Die Schneefallgrenze liegt bei 1800 bis 2000 m, in den Hauptniederschlagsgebieten am Oberwalliser Alpenhauptkamm sinkt sie bis am Montagmorgen auf 1500 bis 1700 m.

Neuschnee
bis Montagnachmittag, oberhalb von 2200 bis 2400 m:
- Monte Rosa Gebiet, Saastal, Simplongebiet: 60 bis 80 cm
- übriger Oberwalliser Alpenhauptkamm, nordwestliches Tessin: 40 bis 60 cm
- übriger Alpenhauptkamm vom Grossen St. Bernhard bis zum Lukmanierpass, nördlicher Alpenkamm vom Lötschental bis zur Reuss, untere Maggiatäler, Leventina: 20 bis 40 cm
- übriges Wallis, übriger nördlicher Alpenkamm westlich vom Tödi, Alpenhauptkamm vom Lukmanier Pass bis ins Berninagebiet: 15 bis 30 cm
- sonst wenige Zentimeter oder trocken

Temperatur
am Mittag auf 2000 m bei +2 °C im Westen und Süden sowie bei +4 °C im Osten

Wind
in der Nacht auf Montag im Hochgebirge stark, sonst mässig bis stark aus Süd bis Südost, am Nachmittag nachlassend

Tendenz

Dienstag
Es ist stark bewölkt mit schwachen Niederschlägen. Die Schneefallgrenze liegt im Norden bei 1500 bis 1800 m und im Süden bei 1800 bis 2000 m. Im Tagesverlauf hellt es vor allem im Wallis und im Süden auf. Der Wind weht schwach bis mässig aus Nordost.
Die Gefahr von trockenen Lawinen nimmt im Süden ab. Die Verhältnisse für Touren bleiben aber in der Höhe kritisch. Im Norden ändert sich die Gefahr von trockenen Lawinen kaum. Nasse Lawinen sind in allen Gebieten möglich, vor allem an West-, Nord- und Osthängen unterhalb von rund 2400 m. In den Neuschneegebieten sind mit der Einstrahlung in der Höhe Lockerschneelawinen aus dem Neuschnee zu erwarten, in mittleren Lagen feuchte Rutsche und Gleitschneelawinen.

Mittwoch
Es ist recht sonnig, einzelne schwache Schauer sind im Tagesverlauf möglich. Die Nullgradgrenze steigt auf 2800 m. Der Wind weht meist schwach. Die Gefahr von trockenen Lawinen nimmt ab. Die Gefahr von nassen Lawinen steigt im Tagesverlauf an.